MINISTERO DELLA DIFESA

meteomont
Servizio Nazionale di previsione neve e valanghe

EAWS EUROPEAN AVALANCHE WARNING SERVICES

CARABINIERI

VELINO - SIRENTE

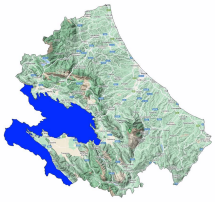

Bollettino Valanghe N. 351/2026 del 19/03/2026 ore 14.00
Validità 48 ore prossima emissione 20/03/2026

A cura del Servizio METEOMONT dell'ARMA dei CARABINIERI
In collaborazione con Servizio Meteorologico dell'Aeronautica militare

SITUAZIONE alle 14:00 del 19/03/2026

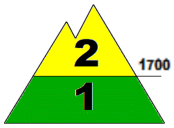

SITUAZIONE TIPO: neve a debole coesione e vento.

SITUAZIONE TIPO: neve a debole coesione e vento.

Quota neve (mslm)	Nord	Sud
	1100 - 1200	1200 - 1300

Altezza Neve (cm)	Neve al suolo	Neve Fresca	Quota (mslm)
	185	007	2079
	010	010	1276

VALANGHE OSSERVATE: Nessuna valanga.

PREVISIONI 20/03/2026

GRADO DI PERICOLO: MODERATO 2

SITUAZIONE TIPO: neve a debole coesione e vento.

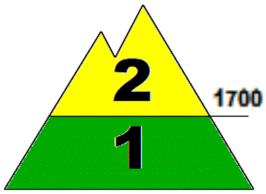

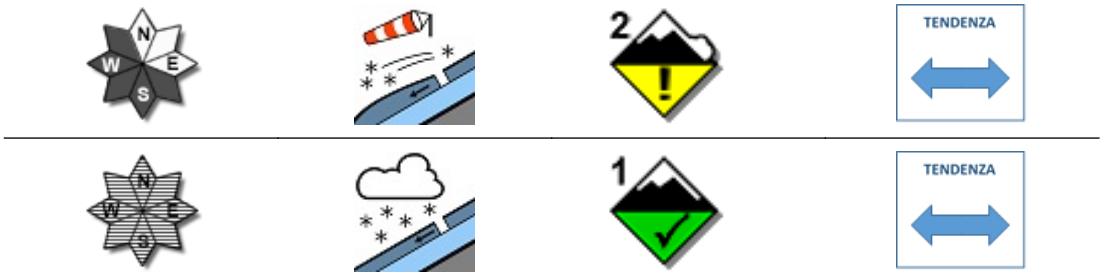

SITUAZIONE TIPO: neve a debole coesione e vento.

MANTO NEVOSO: La stabilità del manto nevoso è discreta su alcuni punti (aree) per versanti da sud est a nord ovest al di sopra di 1700 mslm, possibili valanghe di dimensioni medie.
La stabilità del manto nevoso è discreta su pochi punti (aree) per isolati pendii al di sotto di 1700 mslm, possibili valanghe di dimensioni piccole.

AVVERTENZE

A seguito dell'attività eolica registrata sono da evitare le zone di accumulo, conche, canaloni, cambi di pendenza e pendii sotto vento in genere.

SCALA EUROPEA DEL GRADO DI PERICOLO VALANGHE

LEGENDA PROBLEMA

Bollettino realizzato su scala sinottica-regionale (standard EAWS). La sua valutazione non può escludere in alcun modo la necessità di una seria e capace valutazione locale del pericolo (singolo pendio) che può essere anche sensibilmente diverso. Le previsioni meteorologiche sono relative all'orario UTC (per l'Italia +1 in inverno e +2 in estate).

MINISTERO DELLA DIFESA

meteomont
Servizio Nazionale di previsione neve e valanghe

EAWS EUROPEAN AVALANCHE WARNING SERVICES

CARABINIERI

VELINO - SIRENTE

PREVISIONE METEO

Quota		20/03/2026 h6:00	20/03/2026 h12:00	20/03/2026 h18:00
1000	Venti	03 Nodi da N-Est	04 Nodi da N-Est	02 Nodi da N-Est
	Temperature	-04 °C	-02 °C	-03 °C
	Temp.percepita	-6 °C	-5 °C	-3 °C
2000	Venti	04 Nodi da N-Est	05 Nodi da N-Est	03 Nodi da N-Est
	Temperature	-05 °C	-03 °C	-04 °C
	Temp.percepita	-8 °C	-7 °C	-6 °C
3000	Venti	05 Nodi da Nord	09 Nodi da N-Est	03 Nodi da Nord
	Temperature	-09 °C	-08 °C	-07 °C
	Temp.percepita	-14 °C	-15 °C	-10 °C
Zero termico		1100-1300 m.	1600-1800 m.	1300-1500 m.
Fenomeno		—	—	—
Stato del cielo				

LEGENDA FENOMENI

— Assenza Fenomeni
Nebbia
Foschia
Pioggia debole
Pioggia moderata
Pioggia forte
Temporali
Nevicata debole
Nevicata moderata
Nevicata forte

STATO DEL CIELO

Sereno
Poco nuvoloso
Nuvoloso
Molto nuvoloso
Coperto

Parametri meteonivometrici registrati presso i campi di rilevamento il 19/03/2026.

Località	Comune	Quota (m.s.l.m.)	Altezza neve (cm)	Neve caduta nelle 24 ore (cm)	Temp. Min (°C)	Temp. Max (°C)	Condizioni del tempo
PASSO LE FORCHE	Magliano de' Marsi (AQ)	1276	10	10	-1	+6	Assenza di precipitazioni
FONTE SANT'ELIA	Collelongo (AQ)	1521	10	10	-3	-1	Assenza di precipitazioni
MARSIA	Tagliacozzo (AQ)	1450	5	5	-1	0	Assenza di precipitazioni
LA CROCETTA	Lucoli (AQ)	1573	13	13	-2	+3	Assenza di precipitazioni
MONTE FREDDO *	Ovindoli (AQ)	2079	185	7	N.P.	N.P.	Scaccianeve (tormenta) sulla stazione

(*) Rilievi fuori campo

L'INFORMAZIONE E' PREVENZIONE - LEGGI L'ATTUALE GRADO DI PERICOLO VALANGHE!

IL CAPO DEL CENTRO NAZIONALE METEOMONT
(Ten. Col. RFI Emanuela Gini)
FIRMA AUTOGRAFA OMESSA AI SENSI
DELL'ART.3 DEL D.LGS N.39/1993

Bollettino realizzato su scala sinottica-regionale (standard EAWS). La sua valutazione non può escludere in alcun modo la necessità di una seria e capace valutazione locale del pericolo (singolo pendio) che può essere anche sensibilmente diverso. Le previsioni meteorologiche sono relative all'orario UTC (per l'Italia +1 in inverno e +2 in estate).