Bulletin d'estimation du risque d'avalanche

(valable en dehors des pistes balisées et ouvertes)

MASSIF : Renoso Incudine

Rédigé le jeudi 19 mars 2026 à 15h

Estimation des risques pour le : VENDREDI 20 MARS

INSTABILITÉS EN ALTITUDE DANS LA NEIGE RECENTE VENTÉE.

2

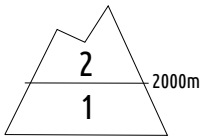

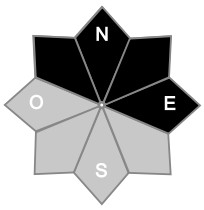

Au-dessus de 2000m indice de risque limité, plus bas indice faible.

Départs spontanés : Très rares départs superficiels en neige récente dans les pentes raides

Déclenchements provoqués : Nombreuses plaques à vent difficilement sollicitables en altitude au-dessus de 2000 m.

Indices de risque : 5 très fort - 4 fort - 3 marqué - 2 limité - 1 faible -- En noir : les pentes les plus dangereuses

Stabilité du manteau neigeux

Situation avalancheuse typique : neige ventée

Déclenchements provoqués : Le vent de Nord-est qui a accompagné les récentes chutes de neige a formé de nouvelles structures de plaques au-dessus de 2000 m. Elles reposent parfois sur des couches fragiles composées de neige roulée. Avec des températures basses pour la saison, ces plaques persistent en versants ne voyant que peu le soleil. Elles peuvent engendrer des avalanches de taille moyenne (taille 1 à 2) et peuvent être sensible au simple passage d'un randonneur ou skieur.
En dessous de 2000 m, la neige fraîche repose sur une sous-couche regelée et plus stable.
Départs spontanés : peu probables et seulement dans les couloirs et pentes raides.
Autres : Nombreuses des surfaces dures et glacées.

Qualité de la neige

Qualification de l'enneigement : L'enneigement est excellent pour la saison au-dessus de 1600 m. Au Val d'Ese, on relève 2m00 de neige à 1800 m. À Ghisoni Capanelle, on mesure environ 3m00 dans les combes abritées.
Limite d'enneigement skiable : 1500 m.
État de la neige : Un petit saupoudrage de la veille vient recouvrir 20 à 30cm de neige récente. Cette neige s'humidifie en surface dans les pentes SE à SO bien exposées au soleil, surtout en-dessous de 2000m. Plus haut, et en pentes plus froides NE à NO, elle reste plus froide et assez légère, ou bien densifiée ou durcie sur les zones qui ont été exposées au Grecale. Le net refroidissement permet une consolidation par regel des couches de neige humide. Des croûtes épaisses et des surfaces dures sont généralisées. À noter également la présence de corniches parfois volumineuses.

Aperçu météo pour le vendredi 20 mars

	nuit	matin	après-midi	soir
Beau temps.				
Pluie-Neige				
Iso 0 °C	1 900 m	2 000 m	2 000 m	2 100 m
Vent 1500 m	30 km/h	40 km/h	20 km/h	20 km/h
Vent 2000 m	30 km/h	50 km/h	20 km/h	30 km/h

Épaisseur de neige hors-piste

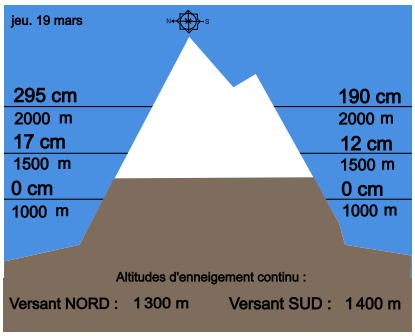

Précipitations à 1800 m

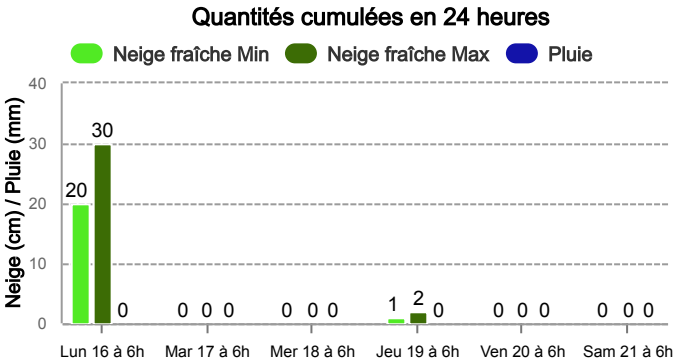

Tendance du samedi 21 mars

2

Indice de risque limité

Avec des températures froides, persistance de plaques localement sensibles en versants ombragés.

Pour consulter la vigilance en cours, veuillez vous rendre sur le site https://vigilance.meteofrance.fr/fr

Météo-France - 73 avenue de Paris, 94165 Saint-Mandé cedex - Contact : contact@meteo.fr

Rédigé par Météo-France avec la contribution des observateurs du réseau nivo-météorologiques. Partenariat : ANMSM (Maires de Stations de Montagne), DSF (Domaines Skiables de France), ADSP (Directeurs de Pistes et de la Sécurité des Stations de Sports d'Hiver) et autres acteurs de la montagne.

Bulletin neige & avalanches par téléphone au

0 892 68 10 20 Service 0,35 € / min + prix appel

RÉPUBLIQUE FRANÇAISE
Liberté Égalité Fraternité

METEO FRANCE
À VOS CÔTÉS, DANS UN CLIMAT QUI CHANGE

Bulletin d'estimation du risque d'avalanche

(valable en dehors des pistes balisées et ouvertes)

MASSIF : Renoso Incudine

Rédigé le jeudi 19 mars 2026 à 15h

Conditions nivo-météo des 7 derniers jours

	ven. 13/03				sam. 14/03				dim. 15/03				lun. 16/03				mar. 17/03				mer. 18/03				jeu. 19/03			
	03h	09h	15h	21h	03h	09h	15h	21h	03h	09h	15h	21h	03h	09h	15h	21h	03h	09h	15h	21h	03h	09h	15h	21h	03h	09h	15h	21h
Météo																												
Vent (km/h)	25	15	5	5	10	30	50	35	25	40	70	60	60	45	15	35	30	45	15	10	20	40	45	70	60	40	25	25
à 2000m																												
Vent (km/h)	20	20	15	10	10	20	50	45	45	40	65	45	50	40	10	15	10	15	10	5	10	25	35	40	55	40	25	20
à 1500m																												

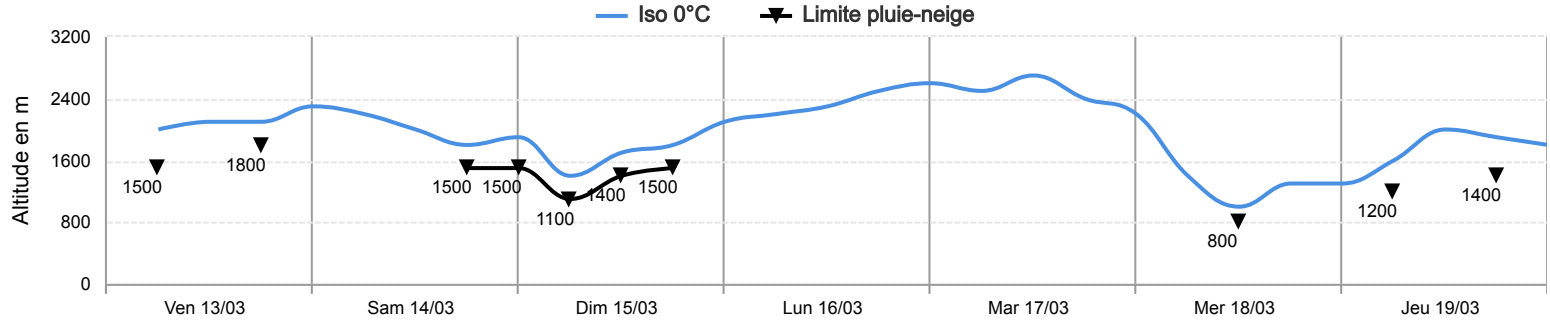

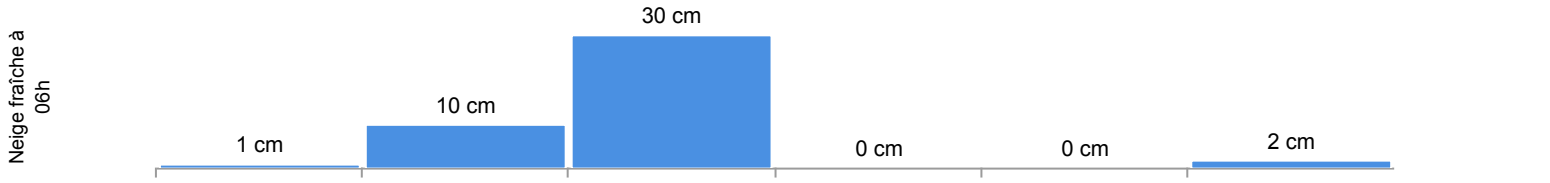

Risque d'avalanche	ven. 13/03	sam. 14/03	dim. 15/03	lun. 16/03	mar. 17/03	mer. 18/03	jeu. 19/03
	1	2	2	3	2	2	2

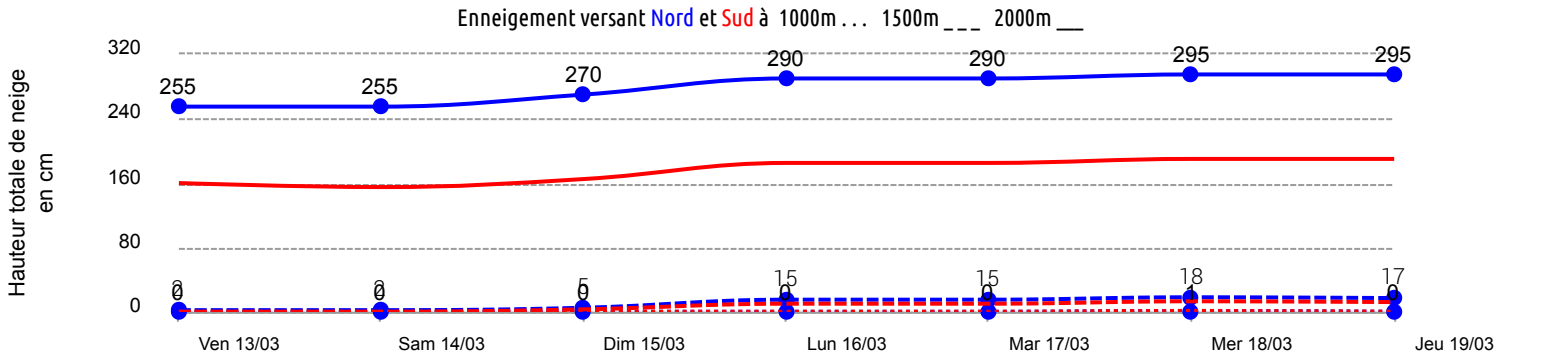

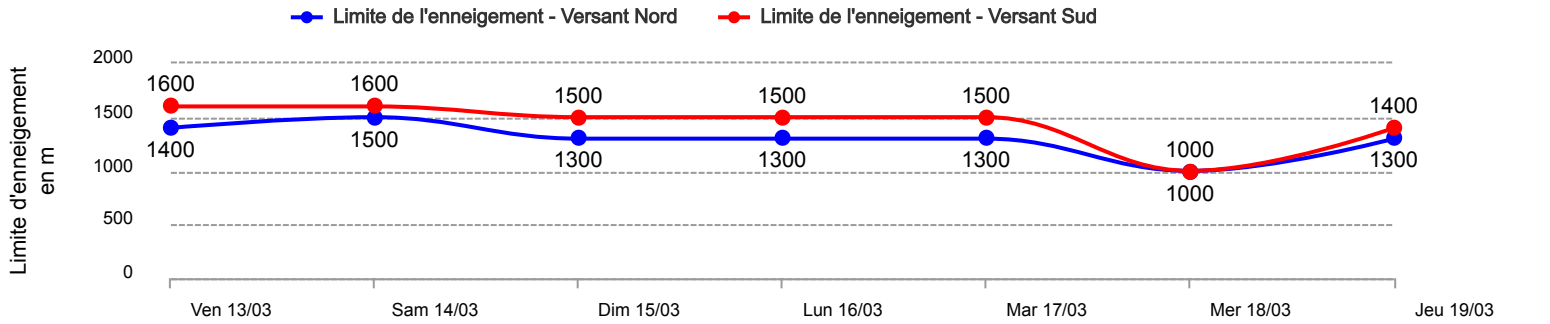

Pour consulter la vigilance en cours, veuillez vous rendre sur le site https://vigilance.meteofrance.fr/fr

Météo-France - 73 avenue de Paris, 94165 Saint-Mandé cedex - Contact : contact@meteo.fr

Rédigé par Météo-France avec la contribution des observateurs du réseau nivo-météorologiques. Partenariat : ANMSM (Maires de Stations de Montagne), DSF (Domaines Skiables de France), ADSP (Directeurs de Pistes et de la Sécurité des Stations de Sports d'Hiver) et autres acteurs de la montagne.

Bulletin neige & avalanches par téléphone au

0 892 68 10 20 Service 0,35 € / min + prix appel