Bulletin d'estimation du risque d'avalanche

(valable en dehors des pistes balisées et ouvertes)

MASSIF : Capcir Puymorens

Rédigé le jeudi 19 mars 2026 à 16h

Estimation des risques pour le : VENDREDI 20 MARS

QUELQUES STRUCTURES DE PLAQUES ENCORE PRÉSENTES EN ALTITUDE ; HUMIDIFICATION AU SOLEIL EN JOURNÉE.

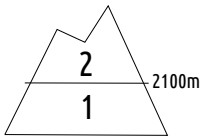

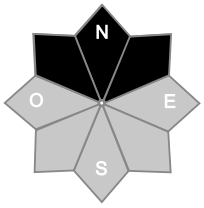

Plaques en altitude

Au-dessus de 2100m indice de risque limité, plus bas indice faible.

Départs spontanés : Reprise de l'humidification en cours de journée, au gré de l'ensoleillement

Déclenchements provoqués : Quelques structures de plaques à vent en altitude

Indices de risque : 5 très fort - 4 fort - 3 marqué - 2 limité - 1 faible -- En noir : les pentes les plus dangereuses

Stabilité du manteau neigeux

Situation avalancheuse typique : neige ventée neige humide

Déclenchements provoqués :
Avalanches de plus en plus difficiles à déclencher même s'il reste encore des structures de plaques en versants Nord au-dessus de 2100/2200 m et dans les secteurs ayant résisté à l'humidification. Des accumulations en neige sèche sont encore susceptibles de reposer sur du givre de surface ou de la neige roulée avec des cassures typiques de 30/40 cm. Plus bas, l'humidification a gagné une bonne partie des pentes et les possibilités de déclenchements provoqués diminuent significativement.
Observables : neige travaillée par le vent en surface, fissures sous les skis, affaissement accompagné de 'whoomf'.

Départs spontanés :
Avalanches de taille petite à moyenne possibles en neige humide, emportant parfois toute l'épaisseur de neige, dès la matinée dans les versants Est, puis dans les versants s'humidifiant progressivement avec l'ensoleillement. Les accumulations dans les versants Est à Sud-Est sont encore conséquentes et peuvent mobiliser des volumes de neige importants au-dessus de 2100/2200m. Plus bas, rares coulées ponctuelles en neige humide dans les pentes ou couloirs raides. En effet, après le bon regel nocturne, l'humidification devrait être moins prononcée que les jours précédents.

Qualité de la neige

Enneigement :
Malgré le redoux de ces derniers jours, l'enneigement reste excellent pour la saison, après plusieurs hivers déficitaires et la fonte conséquente au soleil et en moyenne montagne depuis le début de semaine.
On peut encore envisager de chausser les skis vers 1500/1+00 m dans des configurations favorables en versants nord, plutôt désormais 1900 à 2000 m en versants sud.

État de la neige :
Vendredi matin, la neige est souvent dure et bien regelée en matinée sauf dans la forêt. On pourra trouver localement quelques cm de neige fraiche des averses de jeudi après-midi. Ensuite, en cours de journée, l'humidification reprend dans les versants ensoleillés avec une neige de printemps meuble dans tous les versants en dessous de 2000 m, et jusqu'à 2600/2700 m en versants Sud. Sinon en versants Nord, quelques combes ombragées permettent encore de trouver de la neige poudreuse au-delà de 2300/2500 m, puis travaillée par le vent en altitude.

Aperçu météo pour le vendredi 20 mars

nuit	matin	après-midi	soir

Belle journée au programme avec de la douceur.

Pluie-Neige				
Iso 0 °C	2 300 m	2 500 m	2 600 m	2 500 m
Vent 2000 m	↖ 15 km/h	↖ 10 km/h	← 10 km/h	↑ 5 km/h
Vent 3000 m	← 30 km/h	← 25 km/h	← 20 km/h	↑ 20 km/h

Épaisseur de neige hors-piste

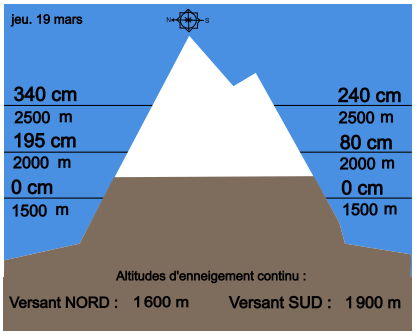

Précipitations à 1800 m

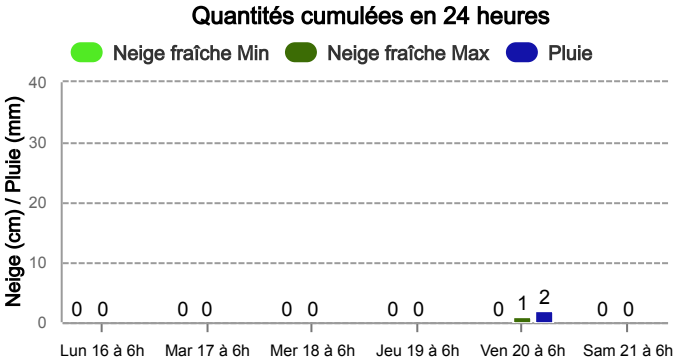

Tendance du samedi 21 mars

Indice de risque limité

Stationnaire avec peu d'évolution.

Pour consulter la vigilance en cours, veuillez vous rendre sur le site https://vigilance.meteofrance.fr/fr

Météo-France - 73 avenue de Paris, 94165 Saint-Mandé cedex - Contact : contact@meteo.fr

Rédigé par Météo-France avec la contribution des observateurs du réseau nivo-météorologiques. Partenariat : ANMSM (Maires de Stations de Montagne), DSF (Domaines Skiables de France), ADSP (Directeurs de Pistes et de la Sécurité des Stations de Sports d'Hiver) et autres acteurs de la montagne.

Bulletin neige & avalanches par téléphone au
0 892 68 10 20 Service 0,35 € / min + prix appel

RÉPUBLIQUE FRANÇAISE
Liberté Égalité Fraternité

METEO FRANCE
À VOS CÔTÉS, DANS UN CLIMAT QUI CHANGE

Bulletin d'estimation du risque d'avalanche

(valable en dehors des pistes balisées et ouvertes)

MASSIF : Capcir Puymorens

Rédigé le jeudi 19 mars 2026 à 16h

Conditions nivo-météo des 7 derniers jours

	ven. 13/03				sam. 14/03				dim. 15/03				lun. 16/03				mar. 17/03				mer. 18/03				jeu. 19/03			
	03h	09h	15h	21h	03h	09h	15h	21h	03h	09h	15h	21h	03h	09h	15h	21h	03h	09h	15h	21h	03h	09h	15h	21h	03h	09h	15h	21h
Météo																												
Vent (km/h)	25	25	30	40	50	50	55	70	95	120	85	65	75	60	60	35	40	30	30	25	15	10	15	20	30	25	30	25
à 3000m	↓	→	→	↘	↘	↘	↘	↘	↓	↓	↘	↓	↓	↓	↘	↓	↓	↓	↘	↓	↓	↓	↘	↘	↘	↘	↓	←
Vent (km/h)	15	15	15	25	30	30	35	45	75	100	80	50	60	50	40	30	30	15	15	15	5	5	5	10	15	15	20	15
à 2000m	↓	→	→	↘	↘	↘	↘	↘	↘	↓	↓	↘	↘	↘	↘	↘	↘	↘	↘	↗	→	↘	→	→	↘	→	↘	←

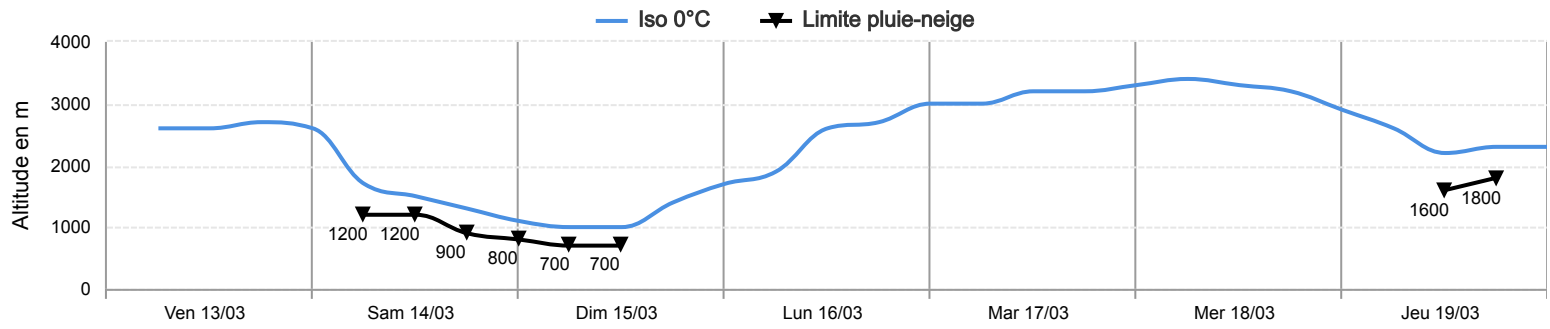

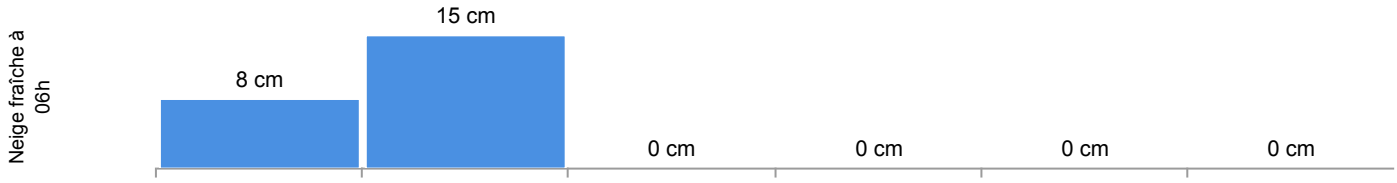

Risque d'avalanche	ven. 13/03	sam. 14/03	dim. 15/03	lun. 16/03	mar. 17/03	mer. 18/03	jeu. 19/03
	2	3	3	3	3	3	2

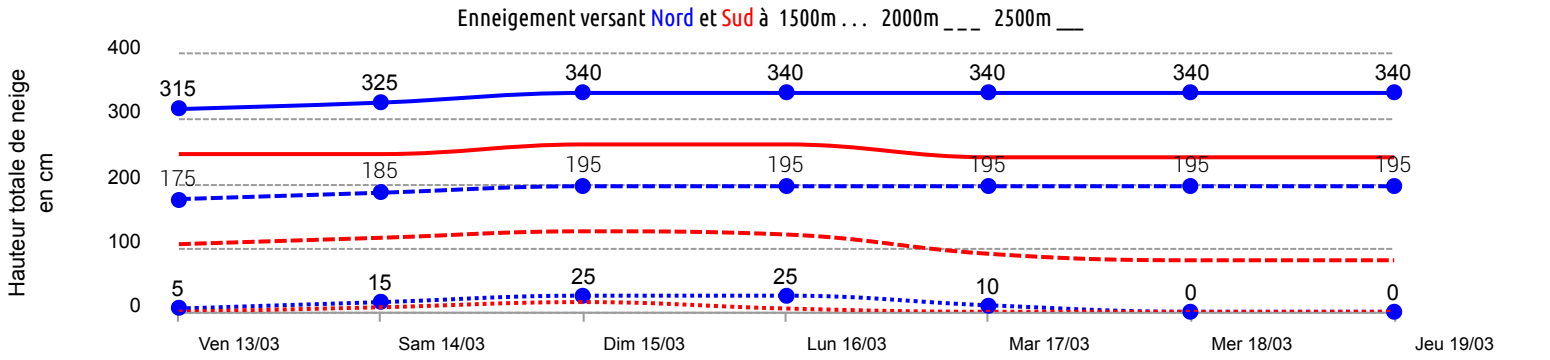

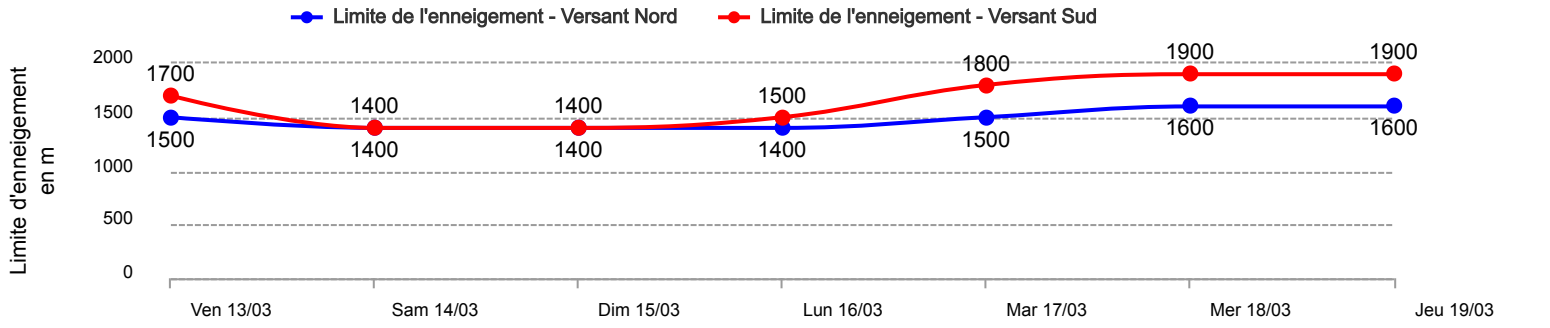

Pour consulter la vigilance en cours, veuillez vous rendre sur le site https://vigilance.meteofrance.fr/fr

Météo-France - 73 avenue de Paris, 94165 Saint-Mandé cedex - Contact : contact@meteo.fr

Rédigé par Météo-France avec la contribution des observateurs du réseau nivo-météorologiques. Partenariat : ANMSM (Maires de Stations de Montagne), DSF (Domaines Skiables de France), ADSP (Directeurs de Pistes et de la Sécurité des Stations de Sports d'Hiver) et autres acteurs de la montagne.

Bulletin neige & avalanches par téléphone au
0 892 68 10 20 Service 0,35 € / min + prix appel