Bulletin d'estimation du risque d'avalanche

(valable en dehors des pistes balisées et ouvertes)

MASSIF : Cerdagne Canigou

Rédigé le jeudi 19 mars 2026 à 16h

Estimation des risques pour le : VENDREDI 20 MARS

QUELQUES STRUCTURES DE PLAQUES ENCORE PRÉSENTES EN ALTITUDE ; HUMIDIFICATION AU SOLEIL EN JOURNÉE.

2

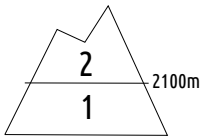

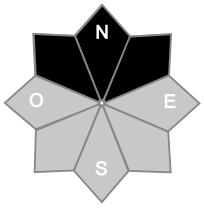

Plaques en altitude

Au-dessus de 2100m indice de risque limité, plus bas indice faible.

Départs spontanés : Reprise de l'humidification en cours de journée avec la douceur et l'ensoleillement

Déclenchements provoqués : Quelques structures de plaques à vent encore présent en altitude

Indices de risque : 5 très fort - 4 fort - 3 marqué - 2 limité - 1 faible -- En noir : les pentes les plus dangereuses

Stabilité du manteau neigeux

Situation avalancheuse typique : neige ventée neige humide

Déclenchements provoqués :

Avalanches de plus en plus difficiles à déclencher même s'il reste encore des structures de plaques en place en versants Nord au-dessus de 2100/2200 m et dans les secteurs ayant résisté à l'humidification. Des accumulations en neige sèche et ventée sont encore susceptibles de reposer sur du givre de surface ou de la neige roulée avec des cassures typiques de 20 à 40 cm. Plus bas, l'humidification a gagné une bonne partie des pentes et les possibilités de déclenchements provoqués diminuent significativement.

Observables : neige travaillée par le vent en surface., traces d'avalanches récentes, fissures sous les skis, affaissement accompagné de 'whoomf',

Départs spontanés :

Avalanches de neige humide de taille petite ou moyenne possible avec l'humidification dans les versants ensoleillés au fil de la journée. Les accumulations dans les versants Est à Sud-Est sont encore conséquentes et peuvent mobiliser des volumes de neige importants au-dessus de 2100/2200 m. Plus bas, plus rares coulées ponctuelles en neige humide dans les pentes ou couloirs raides.

Qualité de la neige

Enneigement :

Malgré le redoux de ces derniers jours, l'enneigement reste excellent pour la saison, après plusieurs hivers déficitaires.

On peut encore envisager de chausser les skis vers 1600/1700m, parfois un peu plus bas dans des configurations favorables (pistes forestières ombragées) et plutôt vers 1800/1900m en versants sud.

État de la neige :

Vendredi matin, la neige est souvent dure et bien regelée en matinée sauf dans la forêt. On pourra trouver localement quelques cm de neige fraiche des averses de jeudi après-midi. Ensuite, en cours de journée, l'humidification reprend dans les versants ensoleillés avec une neige de printemps meuble dans tous les versants sous 2100 m, et jusqu'à 2600/2700 m en versants Sud. Sinon en versants Nord, quelques combes ombragées permettent encore de trouver de la neige sèche au-delà de 2300/2500 m, rarement poudreuse et plus souvent travaillée par le vent.

Aperçu météo pour le vendredi 20 mars

	nuit	matin	après-midi	soir

Belle journée au soleil pour ce vendredi.

Pluie-Neige				
Iso 0 °C	2 300 m	2 400 m	2 600 m	2 600 m
Vent 2000 m	↑ 10 km/h	↗ 10 km/h	↑ 10 km/h	↗ 10 km/h
Vent 3000 m	↑ 20 km/h	↑ 20 km/h	↑ 20 km/h	↑ 25 km/h

Épaisseur de neige hors-piste

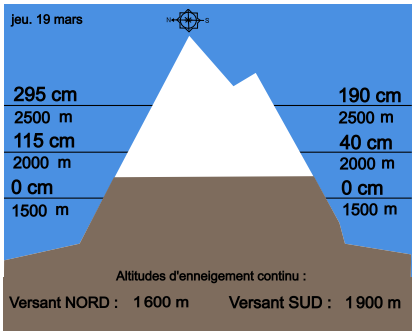

Précipitations à 1800 m

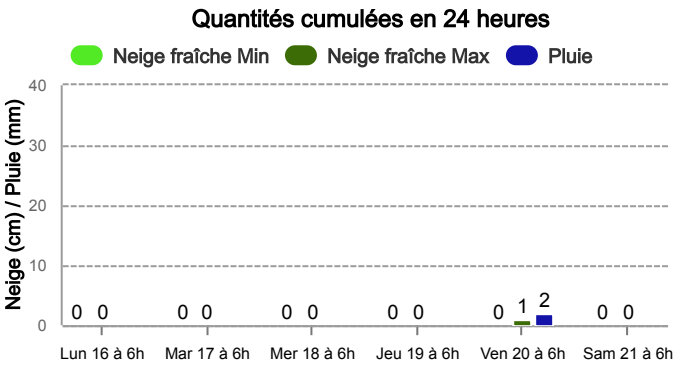

Tendance du samedi 21 mars

2

Indice de risque limité

Stationnaire avec la poursuite d'une situation calme.

Pour consulter la vigilance en cours, veuillez vous rendre sur le site https://vigilance.meteofrance.fr/fr

Météo-France - 73 avenue de Paris, 94165 Saint-Mandé cedex - Contact : contact@meteo.fr

Rédigé par Météo-France avec la contribution des observateurs du réseau nivo-météorologiques. Partenariat : ANMSM (Maires de Stations de Montagne), DSF (Domaines Skiables de France), ADSP (Directeurs de Pistes et de la Sécurité des Stations de Sports d'Hiver) et autres acteurs de la montagne.

Bulletin neige & avalanches par téléphone au 0 892 68 10 20 Service 0,35 € / min + prix appel

RÉPUBLIQUE FRANÇAISE
Liberté Égalité Fraternité

METEO FRANCE
À VOS CÔTÉS, DANS UN CLIMAT QUI CHANGE

Bulletin d'estimation du risque d'avalanche

(valable en dehors des pistes balisées et ouvertes)

MASSIF : Cerdagne Canigou

Rédigé le jeudi 19 mars 2026 à 16h

Conditions nivo-météo des 7 derniers jours

	ven. 13/03				sam. 14/03				dim. 15/03				lun. 16/03				mar. 17/03				mer. 18/03				jeu. 19/03			
	03h	09h	15h	21h	03h	09h	15h	21h	03h	09h	15h	21h	03h	09h	15h	21h	03h	09h	15h	21h	03h	09h	15h	21h	03h	09h	15h	21h
Météo																												
Vent (km/h)	25	25	30	40	50	50	55	70	95	130	95	70	70	60	55	40	45	25	15	15	15	15	20	30	35	35	30	25
à 3000m																												
Vent (km/h)	15	15	15	25	30	30	35	45	70	95	75	45	50	45	35	25	25	15	10	10	10	10	15	20	25	25	20	10
à 2000m																												

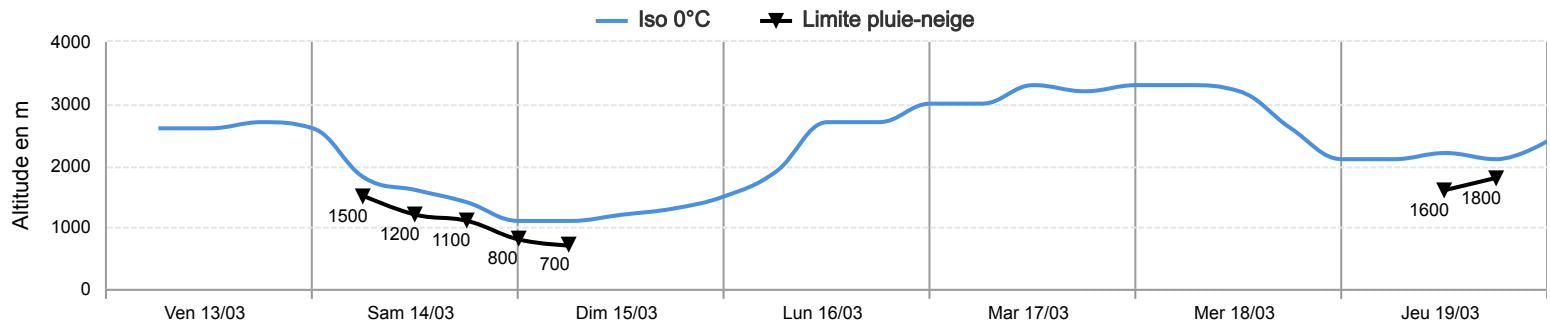

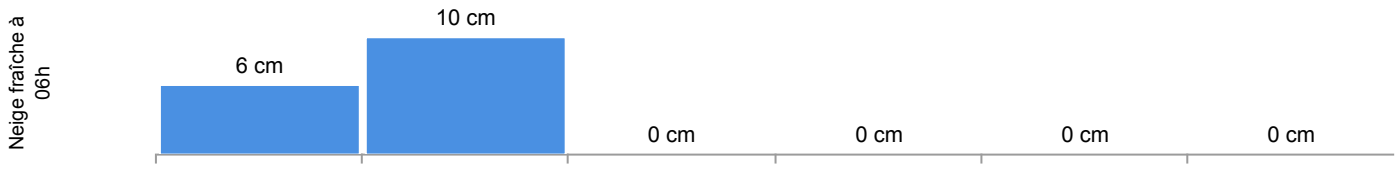

Risque d'avalanche	ven. 13/03	sam. 14/03	dim. 15/03	lun. 16/03	mar. 17/03	mer. 18/03	jeu. 19/03
	2	3	3	3	3	3	2

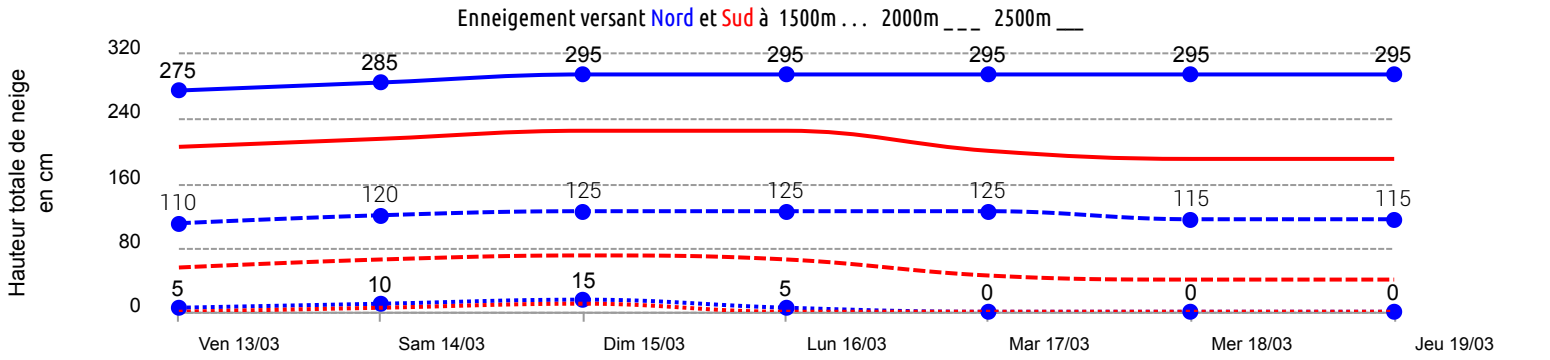

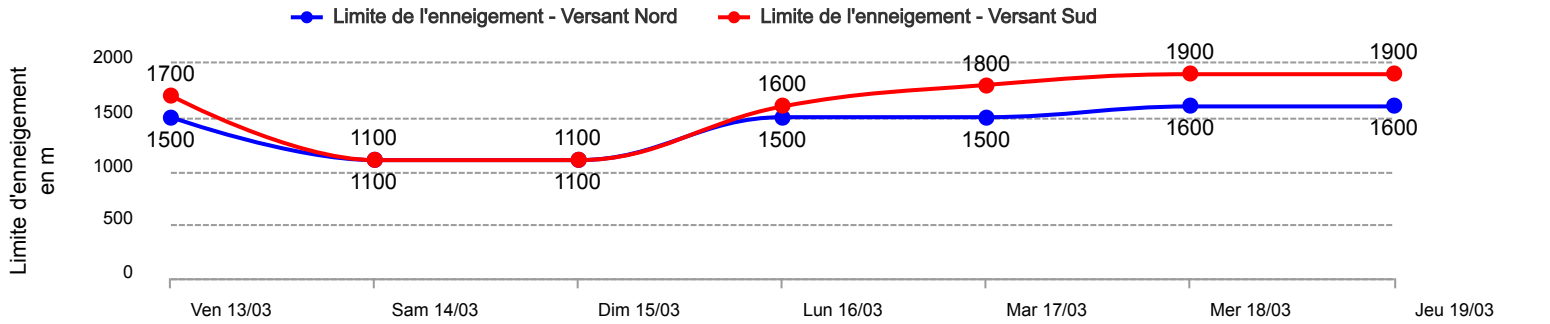

Pour consulter la vigilance en cours, veuillez vous rendre sur le site https://vigilance.meteofrance.fr/fr

Météo-France - 73 avenue de Paris, 94165 Saint-Mandé cedex - Contact : contact@meteo.fr

Bulletin neige & avalanches par téléphone au **0 892 68 10 20** Service 0,35 € / min + prix appel

Rédigé par Météo-France avec la contribution des observateurs du réseau nivo-météorologiques. Partenariat : ANMSM (Maires de Stations de Montagne), DSF (Domaines Skiables de France), ADSP (Directeurs de Pistes et de la Sécurité des Stations de Sports d'Hiver) et autres acteurs de la montagne.