Bulletin d'estimation du risque d'avalanche
(valable en dehors des pistes balisées et ouvertes)
MASSIF : Chablais

Rédigé le jeudi 19 mars 2026 à 16h

Estimation des risques pour le : VENDREDI 20 MARS

2

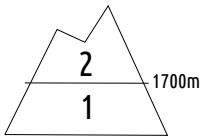

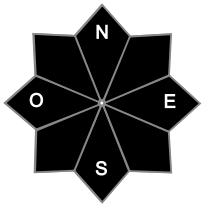

Au-dessus de 1700m indice de risque limité, plus bas indice faible.

Départs spontanés : rares plaques à vent

Déclenchements provoqués : petites avalanches de neige humide au soleil

Indices de risque : 5 très fort - 4 fort - 3 marqué - 2 limité - 1 faible -- En noir : les pentes les plus dangereuses

Stabilité du manteau neigeux

Situation avalancheuse typique : neige ventée

Déclenchements provoqués :
* **quelques plaques à vent**, dans la neige froide (versants **est, nord et ouest au-dessus de 1800 m**), surtout près de la frontière suisse. Elles sont dures. **Assez difficile à déclencher**. Elles ont été formées par le vent d'est de mercredi après-midi. Taille 1 à 2 (petite à moyenne).
Observables : accumulation de neige, vaguelettes, fissures sous les skis, sous 2500 m.
* un peu de neige humide peut couler sous les skis dans les versants ensoleillés aux heures les plus chaudes. Taille 1 (petite)
* rares plaques dures sur sous-couche fragile persistante enfouies, au-dessus de 2200 m. Très difficile à déclencher par un skieur. Départ possible par chutes de corniches ou avalanches en cascade. Taille 2 (moyenne) avec d'épaisses cassures.

Départs spontanés :
* rares avalanches de neige humide, dans les versants ensoleillés sous 2500 m, très rares en début de matinée et un peu plus nombreuses au fil de la course du soleil. Taille 1 rarement 2.
Observables : enfoncement piéton important, escargots.
* rares plaques de fond, de jour comme de nuit, dans les pentes lisses et raides (zones herbeuses, dalles rocheuses). Dans les versants sud sous 2200 m et dans les versants nord sous 2000 m. Taille 2.

Qualité de la neige

Enneigement :
Pour la saison, l'enneigement est correct.
On peut chausser les skis vers 1200/1300 m en nord et 1400/1500 m en sud.
Grosses corniches présentes.

Qualité de la neige ce vendredi matin :
* Dans les adrets sous 2000 m, neige de printemps avec un bon regel nocturne
* Dans les adrets au-dessus de 2000 m et les ubacs sous 1800 m : petite croûte de regel non portante reposant sur de la neige dense. Humidification de surface en journée.
* Dans les ubacs au-dessus de 1800 m, neige dure et froide, fortement travaillée par le vent.

Aperçu météo pour le vendredi 20 mars

nuit	matin	après-midi	soir

Belle journée température atteignant 5°C à 2000 m et 7°C à 1500 m. Rares petis cumumus l'après-midi au-dessus du relief

Pluie-Neige				
Iso 0 °C	2 300 m	2 200 m	2 100 m	2 100 m
Vent 2000 m	20 km/h	10 km/h	5 km/h	5 km/h
Vent 2500 m	25 km/h	20 km/h	5 km/h	5 km/h

Épaisseur de neige hors-piste

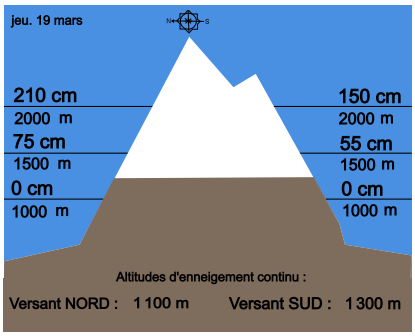

Précipitations à 1800 m

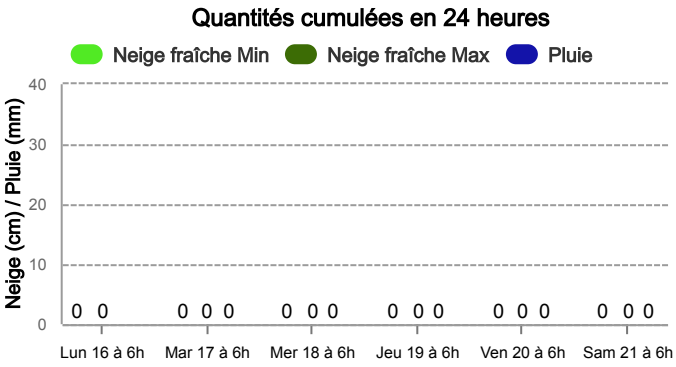

Tendance du samedi 21 mars

2

Indice de risque limité

Samedi, un peu plus nuageux avec du vent faible et un isotherme 0°C vers 1800/2000 m.
⇒ peu d'évolution, poursuite de la stabilisation du manteau neigeux.

Pour consulter la vigilance en cours, veuillez vous rendre sur le site https://vigilance.meteofrance.fr/fr

Météo-France - 73 avenue de Paris, 94165 Saint-Mandé cedex - Contact : contact@meteo.fr

Rédigé par Météo-France avec la contribution des observateurs du réseau nivo-météorologiques. Partenariat : ANMSM (Maires de Stations de Montagne), DSF (Domaines Skiables de France), ADSP (Directeurs de Pistes et de la Sécurité des Stations de Sports d'Hiver) et autres acteurs de la montagne.

Bulletin neige & avalanches par téléphone au
0 892 68 10 20 Service 0,35 € / min + prix appel

RÉPUBLIQUE FRANÇAISE
Liberté Égalité Fraternité

METEO FRANCE
À VOS CÔTÉS, DANS UN CLIMAT QUI CHANGE

Bulletin d'estimation du risque d'avalanche

(valable en dehors des pistes balisées et ouvertes)

MASSIF : Chablais

Rédigé le jeudi 19 mars 2026 à 16h

Conditions nivo-météo des 7 derniers jours

	ven. 13/03				sam. 14/03				dim. 15/03				lun. 16/03				mar. 17/03				mer. 18/03				jeu. 19/03			
	03h	09h	15h	21h	03h	09h	15h	21h	03h	09h	15h	21h	03h	09h	15h	21h	03h	09h	15h	21h	03h	09h	15h	21h	03h	09h	15h	21h
Météo																												
Vent (km/h)	40	45	50	70	70	35	25	50	45	25	15	20	25	25	25	20	25	30	40	50	40	30	60	35	25	30	20	30
à 2500m																												
Vent (km/h)	25	40	40	60	50	20	15	40	40	15	5	10	15	15	15	10	20	20	30	30	25	20	40	25	15	20	15	25
à 2000m																												

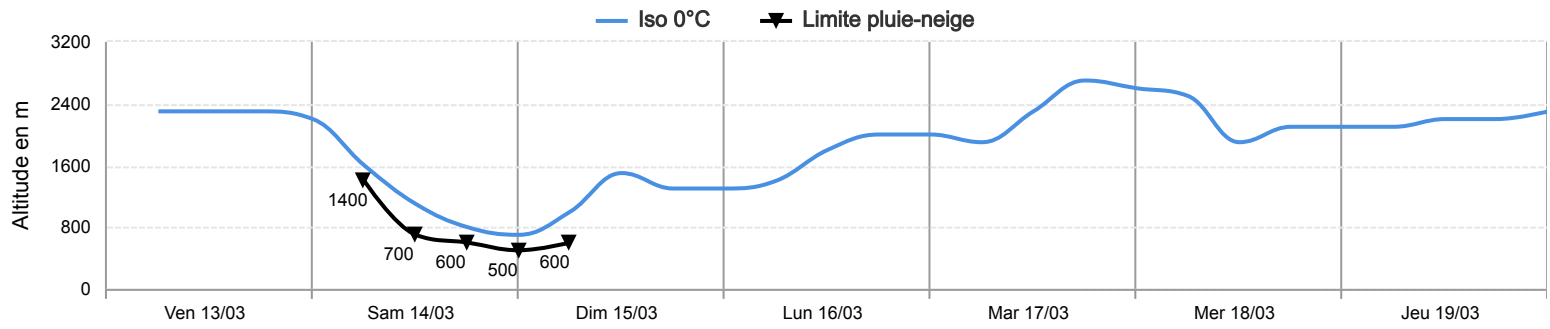

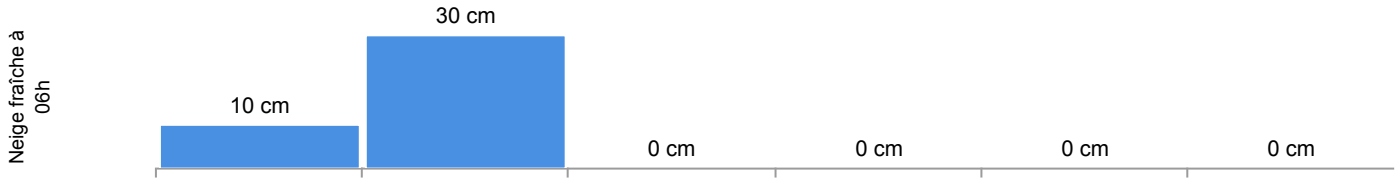

Risque d'avalanche							
	2	3	3	3	2	3	3
	ven. 13/03	sam. 14/03	dim. 15/03	lun. 16/03	mar. 17/03	mer. 18/03	jeu. 19/03

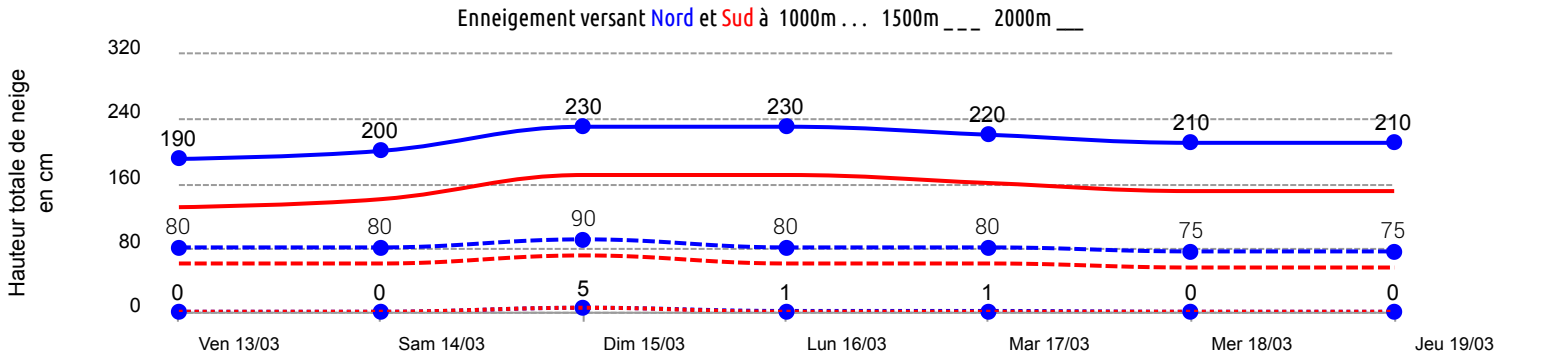

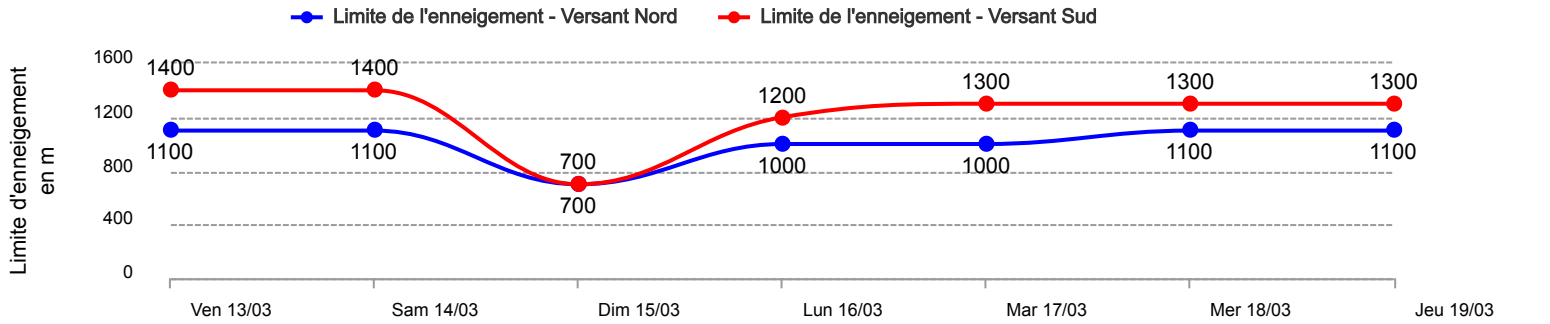

Pour consulter la vigilance en cours, veuillez vous rendre sur le site https://vigilance.meteofrance.fr/fr

Météo-France - 73 avenue de Paris, 94165 Saint-Mandé cedex - Contact : contact@meteo.fr

Bulletin neige & avalanches par téléphone au

0 892 68 10 20 Service 0,35 € / min + prix appel

Rédigé par Météo-France avec la contribution des observateurs du réseau nivo-météorologiques. Partenariat : ANMSM (Maires de Stations de Montagne), DSF (Domaines Skiables de France), ADSP (Directeurs de Pistes et de la Sécurité des Stations de Sports d'Hiver) et autres acteurs de la montagne.