Bulletin d'estimation du risque d'avalanche
(valable en dehors des pistes balisées et ouvertes)

MASSIF : Couserans

Rédigé le jeudi 19 mars 2026 à 16h

Estimation des risques pour le : VENDREDI 20 MARS

QUELQUES STRUCTURES DE PLAQUES ENCORE PRÉSENTES EN HAUTE MONTAGNE ; REPRISE DE L'HUMIDIFICATION AU SOLEIL EN JOURNÉE.

2

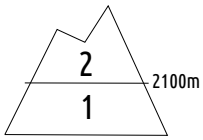

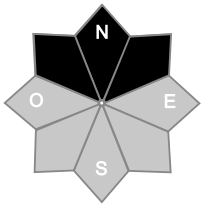

Plaques en altitude

Au-dessus de 2100m indice de risque limité, plus bas indice faible.

Départs spontanés : Reprise de l'humidification en cours de journée, au gré de l'ensoleillement

Déclenchements provoqués : Encore quelques plaques à vent en haute montagne

Indices de risque : 5 très fort - 4 fort - 3 marqué - 2 limité - 1 faible -- En noir : les pentes les plus dangereuses

Stabilité du manteau neigeux

Situation avalancheuse typique : neige ventée neige humide

Déclenchements provoqués :
Avalanches de plus en plus difficiles à déclencher. Il reste encore des structures de plaques en versants Nord au-dessus de 2100/2200 m et dans les secteurs ayant résisté à l'humidification. Des accumulations en neige sèche sont encore susceptibles de reposer sur du givre de surface ou de la neige roulée avec des cassures typiques de 30/40 cm. Plus bas, l'humidification a gagné une bonne partie des pentes et les possibilités de déclenchements provoqués diminuent significativement.
Observables : neige travaillée par le vent en surface, fissures sous les skis, affaissement accompagné de 'whoomf'.

Départs spontanés :
Avalanches de taille petite à moyenne possibles en neige humide, emportant parfois toute l'épaisseur de neige, dès la matinée dans les versants Est, puis dans les versants s'humidifiant progressivement avec l'ensoleillement. Les accumulations dans les versants Est à Sud-Est sont encore conséquentes et peuvent mobiliser des volumes de neige importants au-dessus de 2100/2200m. Plus bas, rares coulées ponctuelles en neige humide dans les pentes ou couloirs raides. En effet, après le bon regel nocturne, l'humidification devrait être moins prononcée que les jours précédents.

Qualité de la neige

Enneigement :
Malgré le redoux de ces derniers jours, l'enneigement reste excellent pour la saison, après plusieurs hivers déficitaires. La fonte est tout de même importante au soleil et en moyenne montagne notamment en versants sud.
La limite skiable évolue peu avec des quantités de neige encore importantes dès 1500/1700m. On peut souvent chausser les skis vers 1300/1400 m dans les meilleures configurations en versants nord, plus surement au-dessus de 1500 m en versants froids, 1700/1800m en versants sud.

Qualité de la neige :
Vendredi matin, la neige devrait être bien dure et regelée en matinée après une nuit claire sauf en forêt où le regel sera alors mauvais. On pourra trouver une fine couche de neige des averses de jeudi après-midi (1 à 3 cm) au-dessus de 2000/2100 m. En cours de journée, la neige s'humidifie progressivement sous 2100 m en tous versants et jusqu'à haute altitude dans les versants ensoleillés. On trouve alors une neige de printemps meuble en dessous de 2500/2600 m, devenant lourde et collante l'après-midi en Sud. Quelques combes bien ombragées devraient encore être poudreuses à partir de 2200/2400 m.

Aperçu météo pour le vendredi 20 mars

	nuit	matin	après-midi	soir

Belle journée douce et ensoleillée.

Pluie-Neige				
Iso 0 °C	2 400 m	2 500 m	2 600 m	2 600 m
Vent 2000 m	↑ 10 km/h	↑ 10 km/h	↗ 10 km/h	↑ 15 km/h
Vent 3000 m	↑ 15 km/h	↑ 20 km/h	↗ 20 km/h	↑ 15 km/h

Épaisseur de neige hors-piste

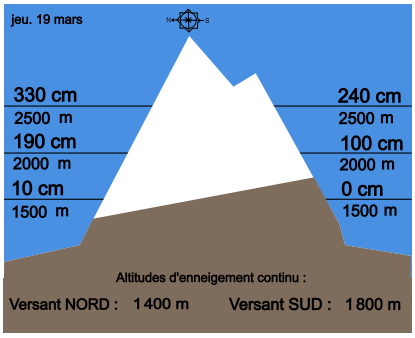

Précipitations à 1800 m

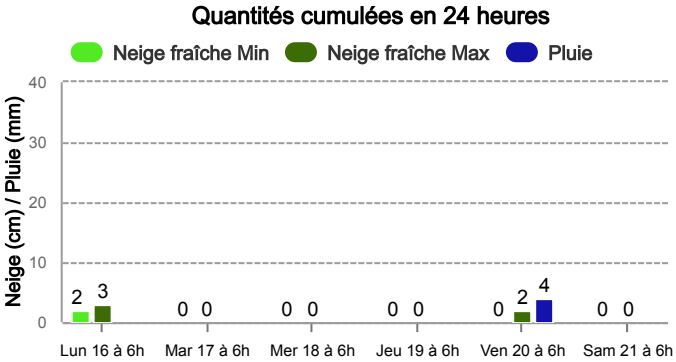

Tendance du samedi 21 mars

2 **Indice de risque limité**

Peu d'évolution nivo-météorologiques avec des conditions encore calmes

Pour consulter la vigilance en cours, veuillez vous rendre sur le site https://vigilance.meteofrance.fr/fr

Météo-France - 73 avenue de Paris, 94165 Saint-Mandé cedex - Contact : contact@meteo.fr

Rédigé par Météo-France avec la contribution des observateurs du réseau nivo-météorologiques. Partenariat : ANMSM (Maires de Stations de Montagne), DSF (Domaines Skiables de France), ADSP (Directeurs de Pistes et de la Sécurité des Stations de Sports d'Hiver) et autres acteurs de la montagne.

Bulletin neige & avalanches par téléphone au **0 892 68 10 20** Service 0,35 € / min + prix appel

RÉPUBLIQUE FRANÇAISE
Liberté Égalité Fraternité

METEO FRANCE
À VOS CÔTÉS, DANS UN CLIMAT QUI CHANGE

Bulletin d'estimation du risque d'avalanche
(valable en dehors des pistes balisées et ouvertes)
MASSIF : Couserans

Rédigé le jeudi 19 mars 2026 à 16h

Conditions nivo-météo des 7 derniers jours

	ven. 13/03				sam. 14/03				dim. 15/03				lun. 16/03				mar. 17/03				mer. 18/03				jeu. 19/03			
	03h	09h	15h	21h	03h	09h	15h	21h	03h	09h	15h	21h	03h	09h	15h	21h	03h	09h	15h	21h	03h	09h	15h	21h	03h	09h	15h	21h
Météo																												
Vent (km/h)	25	25	30	40	50	50	55	70	95	95	75	50	40	30	30	20	25	15	15	15	15	15	20	25	40	35	30	20
à 3000m																												
Vent (km/h)	15	15	15	25	30	30	35	45	60	60	50	30	25	20	20	10	15	10	10	10	10	5	10	20	30	25	20	10
à 2000m																												

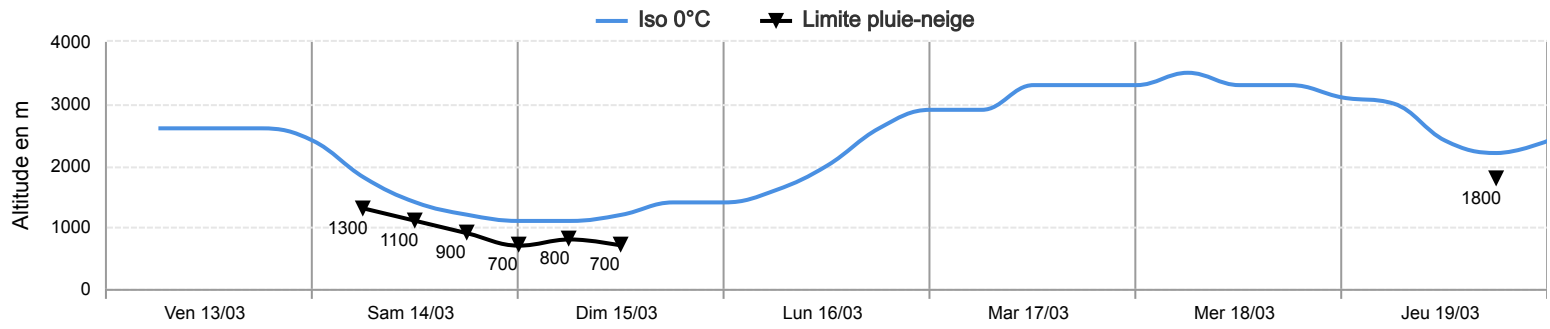

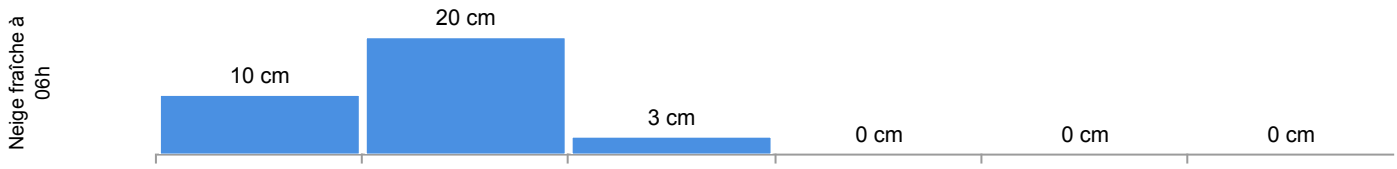

Risque d'avalanche	ven. 13/03	sam. 14/03	dim. 15/03	lun. 16/03	mar. 17/03	mer. 18/03	jeu. 19/03
	2	3	3	3	3	3	2

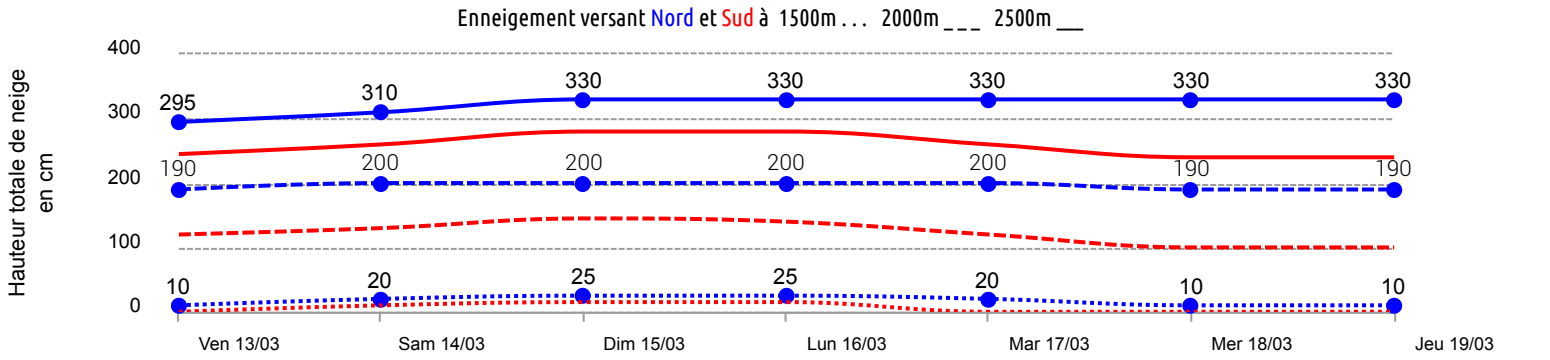

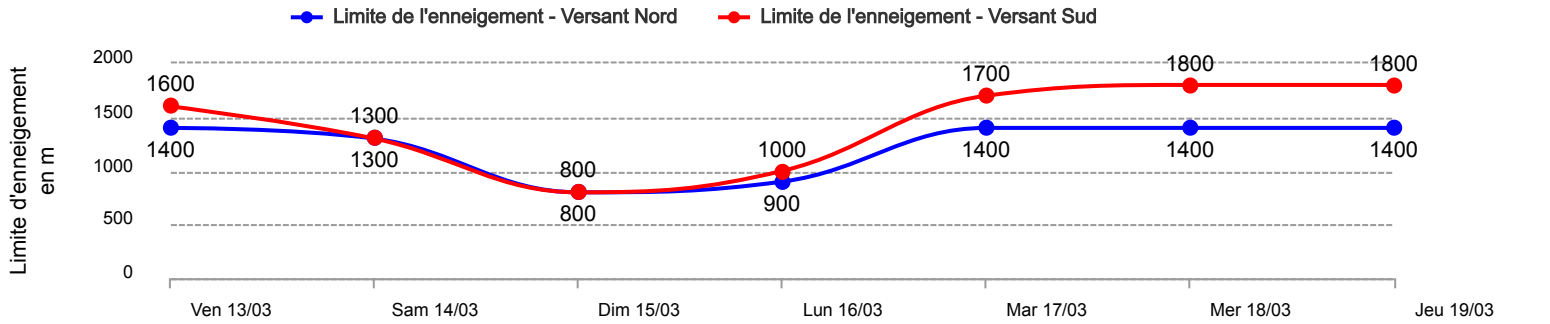

Pour consulter la vigilance en cours, veuillez vous rendre sur le site https://vigilance.meteofrance.fr/fr

Météo-France - 73 avenue de Paris, 94165 Saint-Mandé cedex - Contact : contact@meteo.fr

Rédigé par Météo-France avec la contribution des observateurs du réseau nivo-météorologiques. Partenariat : ANMSM (Maires de Stations de Montagne), DSF (Domaines Skiables de France), ADSP (Directeurs de Pistes et de la Sécurité des Stations de Sports d'Hiver) et autres acteurs de la montagne.

Bulletin neige & avalanches par téléphone au
0 892 68 10 20 Service 0,35 € / min + prix appel