Bulletin d'estimation du risque d'avalanche

(valable en dehors des pistes balisées et ouvertes)

MASSIF : Grandes-Rousses

Rédigé le jeudi 19 mars 2026 à 16h

Estimation des risques pour le : VENDREDI 20 MARS

QUELQUES INSTABILITÉS SUPERFICIELLES DUES AU VENT D'EST.

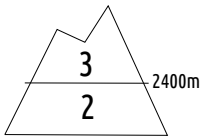

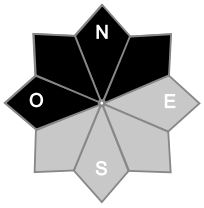

Au-dessus de 2400m indice de risque marqué, plus bas indice limité.

Départs spontanés : Rares coulées au soleil.

Déclenchements provoqués : Quelques plaques en altitude.

Indices de risque : 5 très fort - 4 fort - 3 marqué - 2 limité - 1 faible -- En noir : les pentes les plus dangereuses

Stabilité du manteau neigeux

Situation avalancheuse typique : neige ventée

Déclenchements provoqués : sous l'effet du soleil, le manteau neigeux s'est bien consolidé dans les adrets. Les plaques anciennes formées par le vent de nord, essentiellement dans les versants froids à plus de 2400 m, se raréfient. Ces plaques sont constituées de neige plus ou moins compacte suivant l'action du vent, et les cassures ne dépassent généralement pas 20/40 cm. De nouvelles plaques plus fines, plus réactives et plus difficilement détectables se sont formées mercredi après-midi sous l'effet du vent d'est parfois violent.

Départs spontanés : Après un bon regel nocturne, l'humidification du manteau neigeux reprend grâce au soleil. Ponctuellement, une avalanche de neige lourde (taille 1 à 2) reste possible jeudi dans une pente surchauffée qui n'aurait pas déjà purgé depuis les dernières chutes de neige.

Qualité de la neige

Qualification de l'enneigement : L'enneigement est bon pour la saison en versants ombragés au dessus de 1300 m. Il est correct en Sud au dessus de1700 m.
Limites skiables : Vers 1200/1700 m selon les versants.
Qualité de la neige vendredi : Neige croûtée voire très dure, s'humidifiant en journée dans les versants au soleil. Neige dense, parfois travaillée par le vent dans les ubacs.

Aperçu météo pour le vendredi 20 mars

	nuit	matin	après-midi	soir
Pluie-Neige				
Iso 0 °C	2 300 m	2 500 m	2 500 m	2 200 m
Vent 2000 m	← 10 km/h	← 5 km/h	→ 10 km/h	↑ 5 km/h
Vent 3000 m	↙ 15 km/h	↙ 15 km/h	↓ 10 km/h	↑ 10 km/h

Épaisseur de neige hors-piste

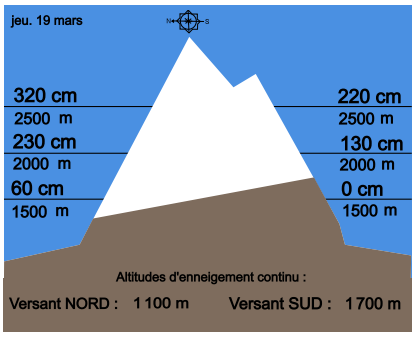

Précipitations à 1800 m

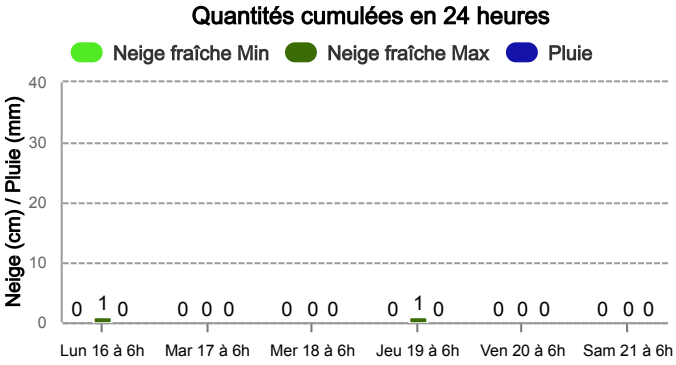

Tendance du samedi 21 mars

Indice de risque limité

Reprise de l'humidification en journée de samedi. Risques stationnaires.

Pour consulter la vigilance en cours, veuillez vous rendre sur le site https://vigilance.meteofrance.fr/fr

Météo-France - 73 avenue de Paris, 94165 Saint-Mandé cedex - Contact : contact@meteo.fr

Rédigé par Météo-France avec la contribution des observateurs du réseau nivo-météorologiques. Partenariat : ANMSM (Maires de Stations de Montagne), DSF (Domaines Skiables de France), ADSP (Directeurs de Pistes et de la Sécurité des Stations de Sports d'Hiver) et autres acteurs de la montagne.

Bulletin neige & avalanches par téléphone au
0 892 68 10 20 Service 0,35 € / min + prix appel

RÉPUBLIQUE FRANÇAISE
Liberté Égalité Fraternité

METEO FRANCE
À VOS CÔTÉS, DANS UN CLIMAT QUI CHANGE

Bulletin d'estimation du risque d'avalanche

(valable en dehors des pistes balisées et ouvertes)

MASSIF : Grandes-Rousses

Rédigé le jeudi 19 mars 2026 à 16h

Conditions nivo-météo des 7 derniers jours

	ven. 13/03				sam. 14/03				dim. 15/03				lun. 16/03				mar. 17/03				mer. 18/03				jeu. 19/03			
	03h	09h	15h	21h	03h	09h	15h	21h	03h	09h	15h	21h	03h	09h	15h	21h	03h	09h	15h	21h	03h	09h	15h	21h	03h	09h	15h	21h
Météo																												
Vent (km/h)	15	20	35	45	60	40	25	65	70	40	45	35	45	35	45	35	25	15	20	20	30	30	45	55	60	35	20	15
à 3000m																												
Vent (km/h)	10	10	25	35	40	15	20	40	40	30	30	25	35	25	30	25	15	10	10	10	15	15	40	40	40	20	15	10
à 2000m																												

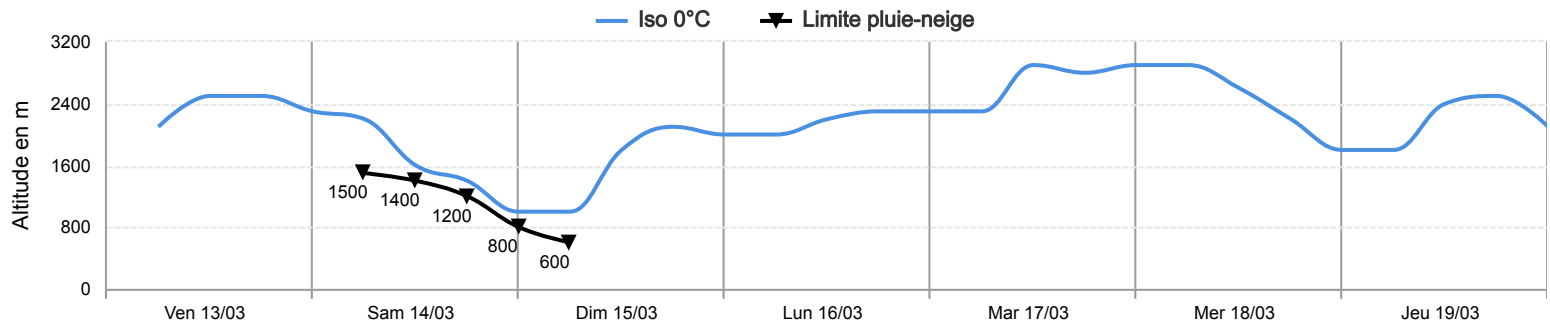

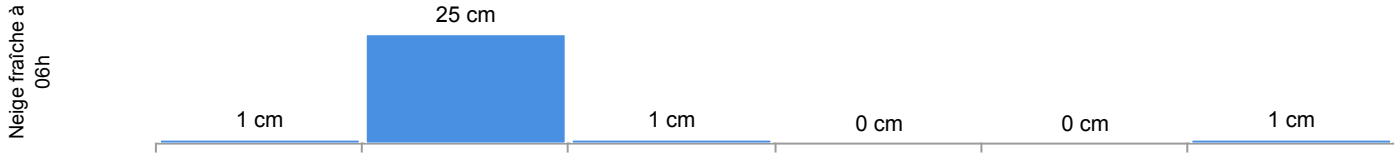

Risque d'avalanche	ven. 13/03	sam. 14/03	dim. 15/03	lun. 16/03	mar. 17/03	mer. 18/03	jeu. 19/03
	3	3	3	3	3	3	3

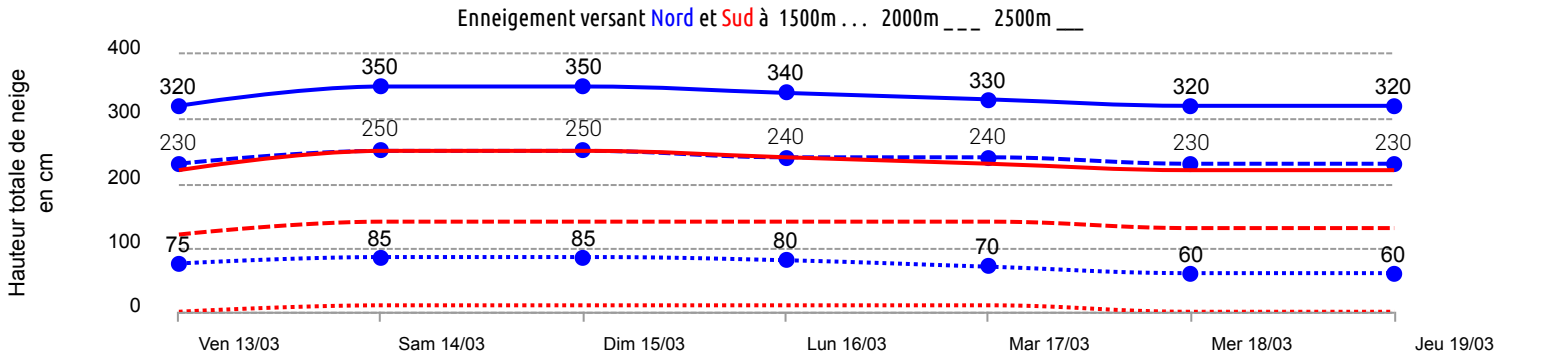

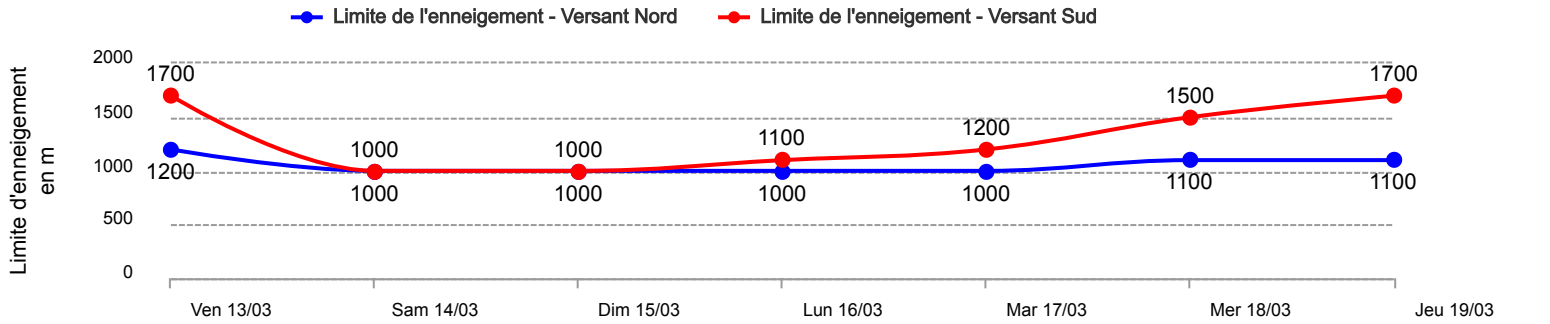

Pour consulter la vigilance en cours, veuillez vous rendre sur le site https://vigilance.meteofrance.fr/fr

Météo-France - 73 avenue de Paris, 94165 Saint-Mandé cedex - Contact : contact@meteo.fr

Bulletin neige & avalanches par téléphone au

0 892 68 10 20 Service 0,35 € / min + prix appel

Rédigé par Météo-France avec la contribution des observateurs du réseau nivo-météorologiques. Partenariat : ANMSM (Maires de Stations de Montagne), DSF (Domaines Skiables de France), ADSP (Directeurs de Pistes et de la Sécurité des Stations de Sports d'Hiver) et autres acteurs de la montagne.