# Bulletin d'estimation du risque d'avalanche
(valable en dehors des pistes balisées et ouvertes)

# MASSIF : Mont-Blanc

Rédigé le jeudi 19 mars 2026 à 16h

## Estimation des risques pour le : VENDREDI 20 MARS

2

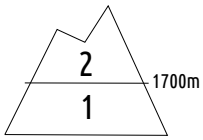


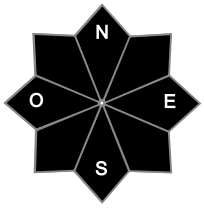


Au-dessus de 1700m indice de risque limité, plus bas indice faible.

**Départs spontanés :** rares plaques à vent

**Déclenchements provoqués :** petites avalanches de neige humide au soleil

Indices de risque : 5 très fort - 4 fort - 3 marqué - 2 limité - 1 faible -- En noir : les pentes les plus dangereuses

## Stabilité du manteau neigeux

**Situation avalancheuse typique :** neige ventée

Déclenchements provoqués :
* **quelques plaques à vent**, dans les versants **est, nord et ouest au-dessus de 2000 m**. Elles sont plus nombreuses en montant en altitude. Elles sont dures. **Assez difficile à déclencher**. Elles ont été formées par le Foehn mercredi après-midi et en haute montagne aussi jeudi matin. Taille 1 à 2 (petite à moyenne).
*Observables :* accumulation de neige, vaguelettes, fissures sous les skis.
* un peu de neige humide peut couler sous les skis dans les versants ensoleillés aux heures les plus chaudes, sous 2500 m. Taille 1 (petite)
* rares plaques dures sur sous-couche fragile persistante enfouies, au-dessus de 2200 m. Très difficile à déclencher par un skieur. Départ possible par chutes de corniches, séracs ou avalanches en cascade. Taille 2 (moyenne) et rarement 3 (grande) avec d'épaisses cassures.

Départs spontanés :
* rares avalanches de neige humide, dans les versants ensoleillés sous 2500 m, très rares en début de matinée et un peu plus nombreuses au fil de la course du soleil. Taille 1 rarement 2.
*Observables :* enfoncement piéton important, escargots.
* rares plaques de fond, de jour comme de nuit, dans les pentes lisses et raides (zones herbeuses, dalles rocheuses). Dans les versants sud sous 2200 m et dans les versants nord sous 2000 m. Taille 2.

## Qualité de la neige

Enneigement :
Pour la saison, l'enneigement est correct.
On peut chausser les skis vers 1200/1300 m en nord et 1400/1500 m en sud.
Grosses corniches présentes.

Qualité de la neige ce vendredi matin :
* Dans les adrets sous 2000 m, neige de printemps avec un bon regel nocturne
* Dans les adrets vers 2000/2800 m et les ubacs sous 2000 m : petite croûte de regel non portante reposant sur de la neige dense. Humidification de surface en journée.
* Dans les ubacs au-dessus de 2000 m, neige dure et froide, fortement travaillée par le vent. Des vielles traces de skis ressortent par endroits.
* En haute montagne, neige très hétérogène soit très dure (la glace ressort dans certaines zones) ou grosses accumulations de neige froide avec un enfoncement piéton important.

## Aperçu météo pour le vendredi 20 mars

| | nuit | matin | après-midi | soir |
|---|---|---|---|---|
| Belle journée température atteignant 5°C à 2000 m et 7°C à 1500 m. | | | | |
| **Pluie-Neige** | | | | |
| **Iso 0 °C** | 2 100 m | 2 100 m | 2 200 m | 2 100 m |
| **Vent 2000 m** | 15 km/h | 5 km/h | 10 km/h | 5 km/h |
| **Vent 4000 m** | 50 km/h | 50 km/h | 20 km/h | 20 km/h |

## Épaisseur de neige hors-piste

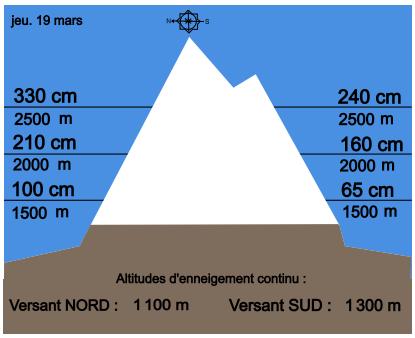


## Précipitations à 1800 m

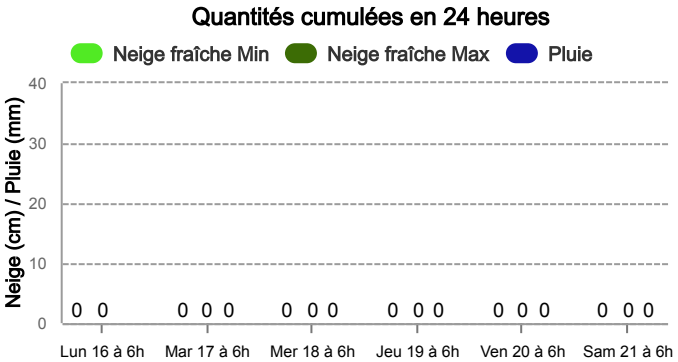


## Tendance du samedi 21 mars

2

**Indice de risque limité**

Samedi, un peu plus nuageux avec du vent faible et un isotherme 0°C vers 1800/2000 m.
⇒ peu d'évolution, poursuite de la stabilisation du manteau neigeux.

Pour consulter la vigilance en cours, veuillez vous rendre sur le site https://vigilance.meteofrance.fr/fr

Météo-France - 73 avenue de Paris, 94165 Saint-Mandé cedex - Contact : contact@meteo.fr

Rédigé par Météo-France avec la contribution des observateurs du réseau nivo-météorologiques. Partenariat : ANMSM (Maires de Stations de Montagne), DSF (Domaines Skiables de France), ADSP (Directeurs de Pistes et de la Sécurité des Stations de Sports d'Hiver) et autres acteurs de la montagne.

Bulletin neige & avalanches par téléphone au
0 892 68 10 20 Service 0,35 € / min + prix appel

RÉPUBLIQUE FRANÇAISE
*Liberté Égalité Fraternité*

METEO FRANCE
À VOS CÔTÉS, DANS UN CLIMAT QUI CHANGE

# Bulletin d'estimation du risque d'avalanche
## (valable en dehors des pistes balisées et ouvertes)
# MASSIF : Mont-Blanc

Rédigé le jeudi 19 mars 2026 à 16h

## Conditions nivo-météo des 7 derniers jours

| | ven. 13/03 | | | | sam. 14/03 | | | | dim. 15/03 | | | | lun. 16/03 | | | | mar. 17/03 | | | | mer. 18/03 | | | | jeu. 19/03 | | | |
|---|---|---|---|---|---|---|---|---|---|---|---|---|---|---|---|---|---|---|---|---|---|---|---|---|---|---|---|---|
| | 03h | 09h | 15h | 21h | 03h | 09h | 15h | 21h | 03h | 09h | 15h | 21h | 03h | 09h | 15h | 21h | 03h | 09h | 15h | 21h | 03h | 09h | 15h | 21h | 03h | 09h | 15h | 21h |
| Météo | | | | | | | | | | | | | | | | | | | | | | | | | | | | |
| Vent (km/h) | 25 | 35 | 45 | 60 | 45 | 40 | 25 | 30 | 30 | 35 | 40 | 60 | 70 | 80 | 60 | 70 | 65 | 65 | 70 | 70 | 80 | 100 | 100 | 80 | 60 | 50 | 50 | 60 |
| à 4000m | | | | | | | | | | | | | | | | | | | | | | | | | | | | |
| Vent (km/h) | 20 | 30 | 40 | 50 | 30 | 25 | 20 | 25 | 25 | 10 | 10 | 10 | 10 | 20 | 15 | 20 | 20 | 20 | 25 | 20 | 15 | 40 | 80 | 40 | 20 | 30 | 10 | 20 |
| à 2000m | | | | | | | | | | | | | | | | | | | | | | | | | | | | |

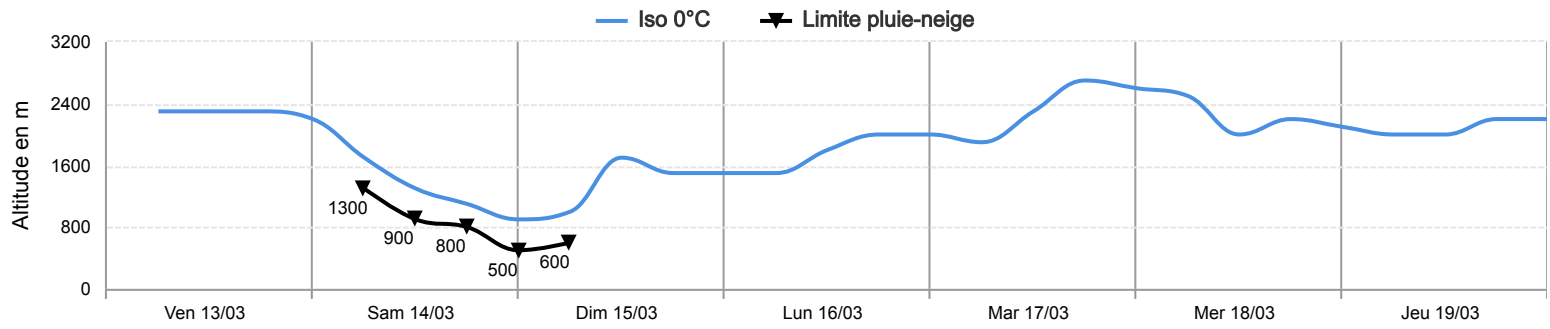


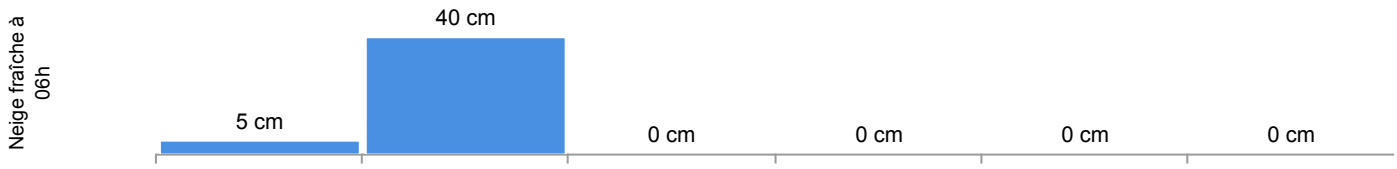


| Risque d'avalanche | ven. 13/03 | sam. 14/03 | dim. 15/03 | lun. 16/03 | mar. 17/03 | mer. 18/03 | jeu. 19/03 |
|---|---|---|---|---|---|---|---|
| | 3 | 3 | 3 | 3 | 3 | 3 | 3 |

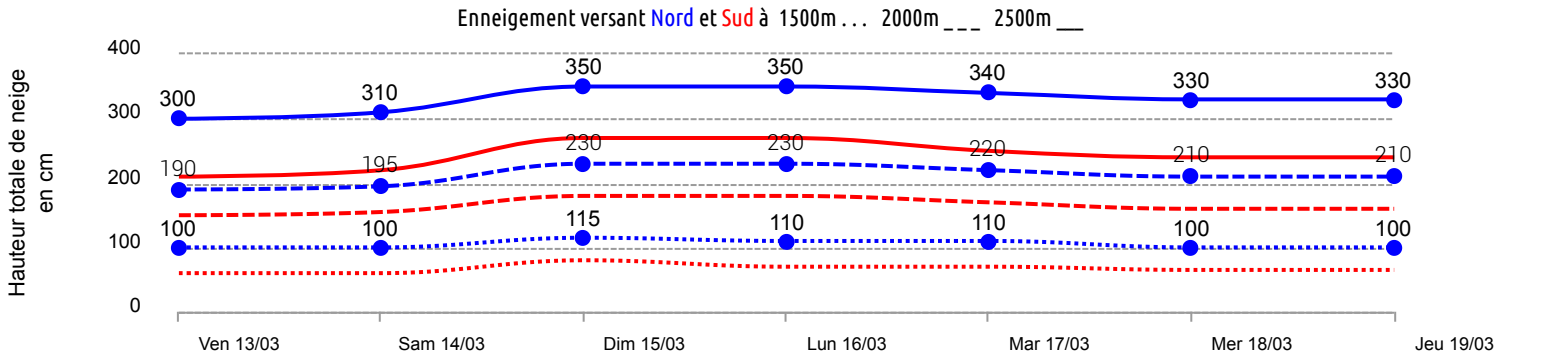


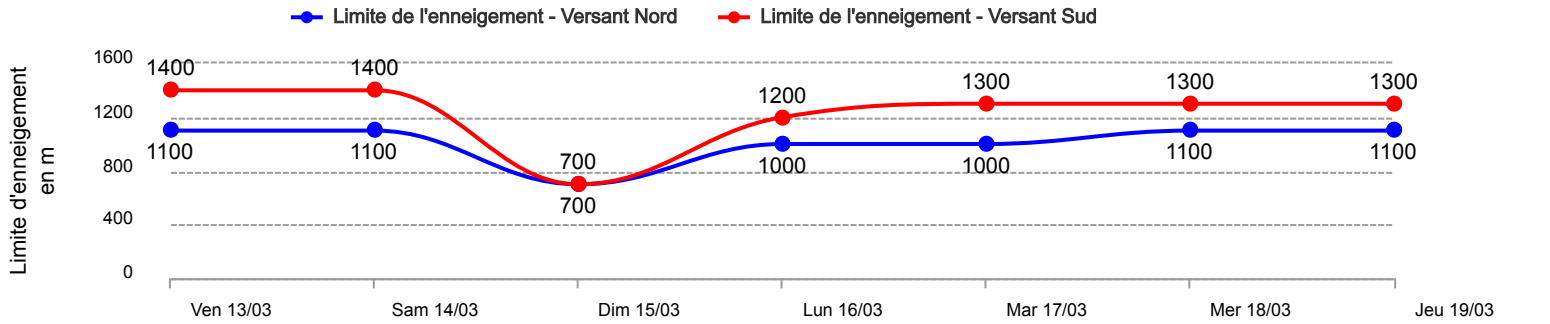


Pour consulter la vigilance en cours, veuillez vous rendre sur le site https://vigilance.meteofrance.fr/fr


Météo-France - 73 avenue de Paris, 94165 Saint-Mandé cedex - Contact : contact@meteo.fr


Rédigé par Météo-France avec la contribution des observateurs du réseau nivo-météorologiques. Partenariat : ANMSM (Maires de Stations de Montagne), DSF (Domaines Skiables de France), ADSP (Directeurs de Pistes et de la Sécurité des Stations de Sports d'Hiver) et autres acteurs de la montagne.

Bulletin neige & avalanches par téléphone au
0 892 68 10 20 Service 0,35 € / min + prix appel