Bulletin d'estimation du risque d'avalanche
(valable en dehors des pistes balisées et ouvertes)

MASSIF : Thabor

Rédigé le jeudi 19 mars 2026 à 16h

Estimation des risques pour le : VENDREDI 20 MARS

QUELQUES PLAQUES DANS LA NEIGE RÉCENTE VENTÉE

2

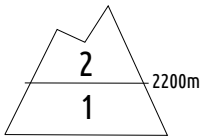

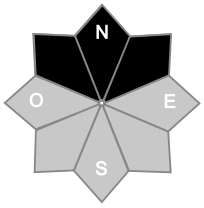

Au-dessus de 2200m indice de risque limité, plus bas indice faible.

Départs spontanés : rares départs en neige humide au soleil

Déclenchements provoqués : quelques plaques en place en versants nord.

Indices de risque : 5 très fort - 4 fort - 3 marqué - 2 limité - 1 faible -- En noir : les pentes les plus dangereuses

Stabilité du manteau neigeux

Situation avalancheuse typique : neige ventée

Déclenchements provoqués : quelques plaques à vent en place. Ces instabilités se situent dans les zones d'accumulation de neige, souvent derrière les crêtes et ruptures de pentes. Elles sont présentes principalement au dessus de 2200/2300 m environ, principalement en un large versant nord. Elles sont en cours de stabilisation, mais peuvent être localement déclenchées au passage d'un skieur, et provoquer des avalanches de taille petite, à parfois moyenne (1 à 2).
Bien que difficile à déclencher, une rare grande avalanche n'est pas exclue, si la surcharge d'une avalanche de surface vient déstabiliser une couche fragile persistante enfouie en profondeur dans le manteau neigeux.
En dessous de 2200/2300 m, le manteau neigeux est généralement stabilisé.

Départs spontanés :
- Rares départs ponctuels de neige s'humidifiant en pentes raides ensoleillées au fil de la journée. Départs généralement de petite taille.

Qualité de la neige

L'enneigement est proche des normales pour une mi-mars.
Hauteurs de neige observées vers 2500 m : 175 cm dans le vallon du Chardonnet, 123 cm à la nivôse des Rochilles, 83 cm à la Nivôse du Galibier.

Limite d'enneigement skiable : vers 1400/1500 m en ubacs, 1700/1900 m en adrets pas trop raides.

État de la neige de surface : après un bon regel nocturne en versants ensoleillés, reprise de l'humidification en journée. Au-dessus de 2200/2300 m, neige récente souvent travaillée par le vent, encore localement poudreuse en ubacs restés abrités.

Aperçu météo pour le vendredi 20 mars

nuit	matin	après-midi	soir
Temps calme, bien ensoleillé.			

Pluie-Neige				
Iso 0 °C	2 200 m	2 300 m	2 400 m	2 200 m
Vent 2000 m	↓ 10 km/h	↓ 10 km/h	→ 15 km/h	↘ 5 km/h
Vent 3000 m	↓ 15 km/h	↘ 10 km/h	↘ 15 km/h	↘ 15 km/h

Épaisseur de neige hors-piste

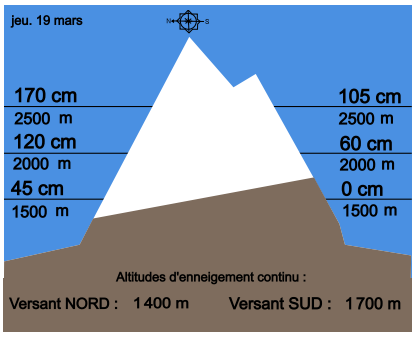

Précipitations à 1800 m

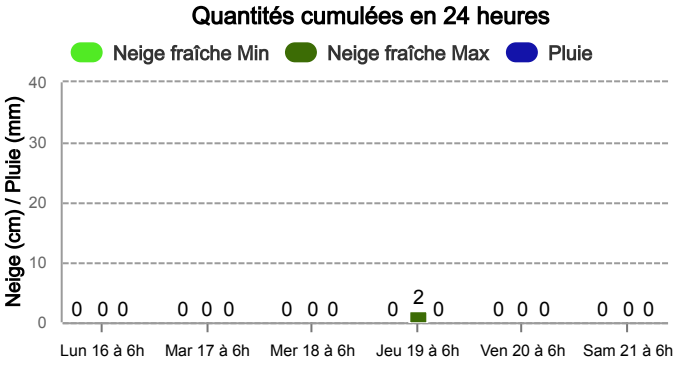

Tendance du samedi 21 mars

2

Indice de risque limité

peu dévolution du risque, les faibles averses de l'après-midi ne modifiant pas la stabilité du manteau neigeux.

Pour consulter la vigilance en cours, veuillez vous rendre sur le site https://vigilance.meteofrance.fr/fr

Météo-France - 73 avenue de Paris, 94165 Saint-Mandé cedex - Contact : contact@meteo.fr

Rédigé par Météo-France avec la contribution des observateurs du réseau nivo-météorologiques. Partenariat : ANMSM (Maires de Stations de Montagne), DSF (Domaines Skiables de France), ADSP (Directeurs de Pistes et de la Sécurité des Stations de Sports d'Hiver) et autres acteurs de la montagne.

Bulletin neige & avalanches par téléphone au
0 892 68 10 20 Service 0,35 € / min + prix appel

RÉPUBLIQUE FRANÇAISE
Liberté Égalité Fraternité

METEO FRANCE
À VOS CÔTÉS, DANS UN CLIMAT QUI CHANGE

Bulletin d'estimation du risque d'avalanche
(valable en dehors des pistes balisées et ouvertes)

MASSIF : Thabor

Rédigé le jeudi 19 mars 2026 à 16h

Conditions nivo-météo des 7 derniers jours

	ven. 13/03				sam. 14/03				dim. 15/03				lun. 16/03				mar. 17/03				mer. 18/03				jeu. 19/03			
	03h	09h	15h	21h	03h	09h	15h	21h	03h	09h	15h	21h	03h	09h	15h	21h	03h	09h	15h	21h	03h	09h	15h	21h	03h	09h	15h	21h
Météo																												
Vent (km/h)	10	10	15	20	50	30	5	15	20	45	40	10	30	40	50	40	35	20	25	25	40	50	70	65	55	45	30	10
à 3000m																												
Vent (km/h)	10	10	15	10	5	5	10	20	10	20	15	5	10	30	40	25	20	15	20	15	20	30	40	20	20	15	15	10
à 2000m																												

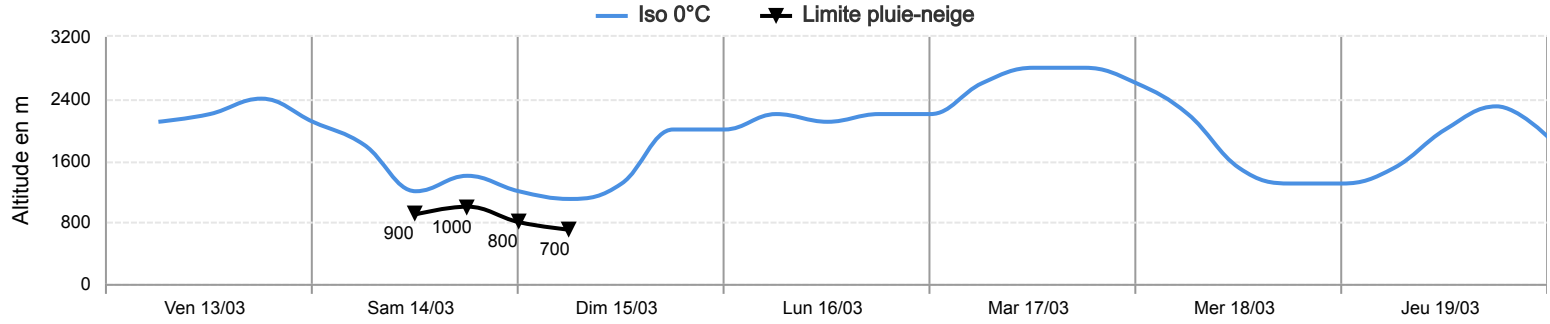

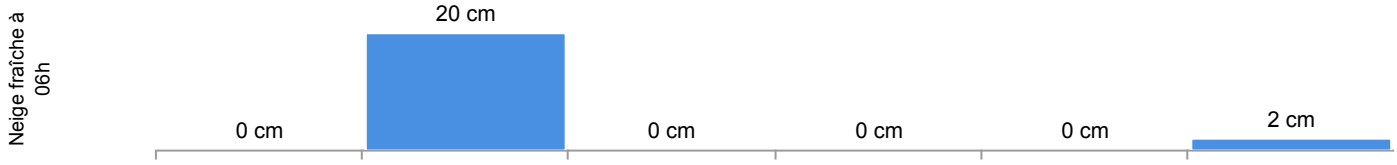

Risque d'avalanche	ven. 13/03	sam. 14/03	dim. 15/03	lun. 16/03	mar. 17/03	mer. 18/03	jeu. 19/03
	2	3	3	3	3	3	3

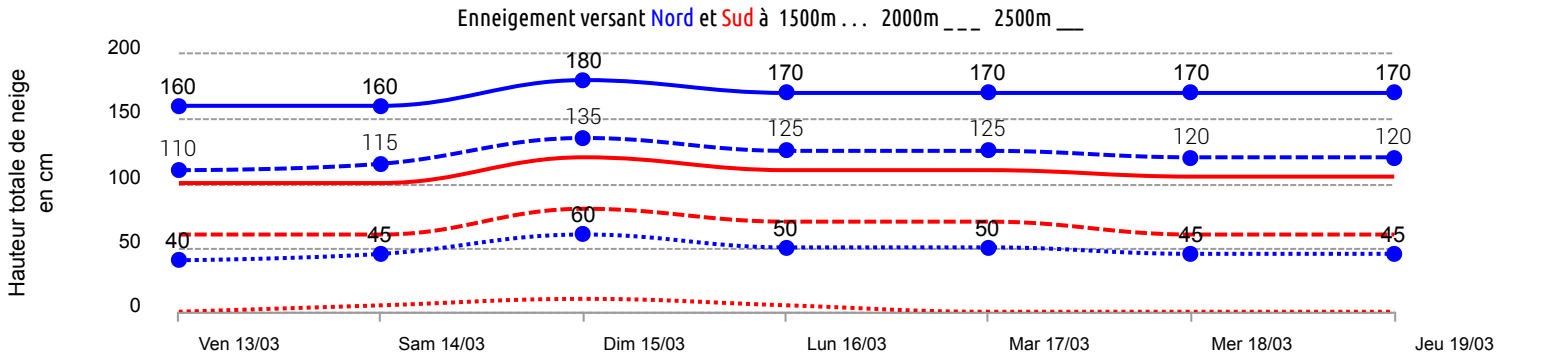

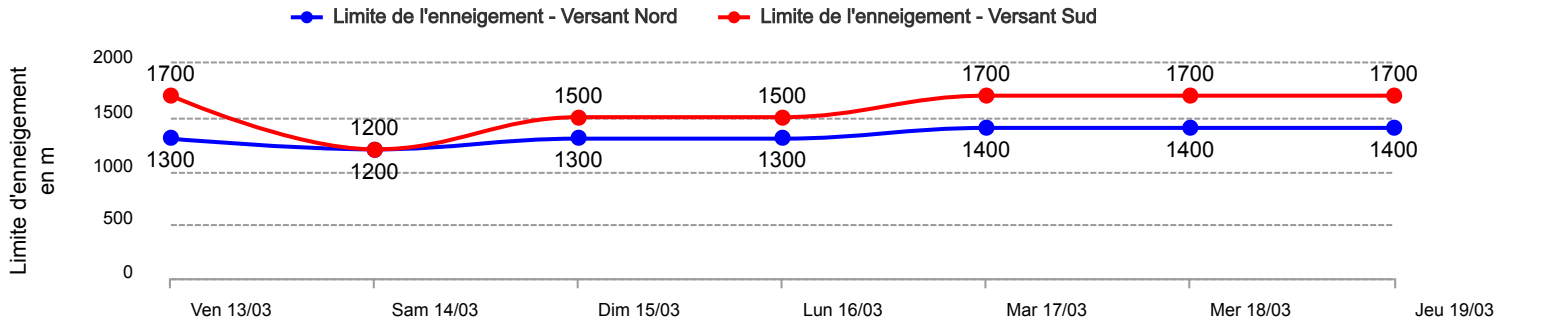

Pour consulter la vigilance en cours, veuillez vous rendre sur le site https://vigilance.meteofrance.fr/fr

Météo-France - 73 avenue de Paris, 94165 Saint-Mandé cedex - Contact : contact@meteo.fr

Rédigé par Météo-France avec la contribution des observateurs du réseau nivo-météorologiques. Partenariat : ANMSM (Maires de Stations de Montagne), DSF (Domaines Skiables de France), ADSP (Directeurs de Pistes et de la Sécurité des Stations de Sports d'Hiver) et autres acteurs de la montagne.

Bulletin neige & avalanches par téléphone au
0 892 68 10 20 Service 0,35 € / min + prix appel