Bulletin d'estimation du risque d'avalanche
(valable en dehors des pistes balisées et ouvertes)
MASSIF : Vanoise

Rédigé le jeudi 19 mars 2026 à 16h

Estimation des risques pour le : VENDREDI 20 MARS

MANTEAU PRINTANIER EN SUD, TRÈS TRAVAILLÉ PAR LE VENT EN NORD AVEC QUELQUES INSTABILITÉS.

2

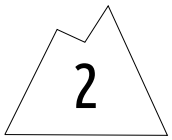

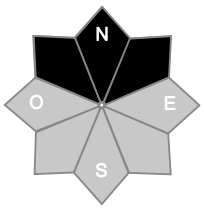

Indice de risque limité.

Départs spontanés : Petites avalanches sous les rochers au soleil

Déclenchements provoqués : Quelques plaques, souvent dures, en versant ombragé au dessus de 2000 m essentielement

Indices de risque : 5 très fort - 4 fort - 3 marqué - 2 limité - 1 faible -- En noir : les pentes les plus dangereuses

Stabilité du manteau neigeux

Situation avalancheuse typique : neige ventée

Déclenchements provoqués : Quelques **plaques** en cours de tassement dans les **versants ombragés plutôt au dessus de 2000m.** Ces plaques formées suite aux chutes de samedi dernier et/ou avec le transport par le vent de ce mercredi se stabilisent rapidement. Ces plaques sont plutôt **dures.** Elles sont localement **encore sensible au passage d'un skieur** ce vendredi et se rencontrent notamment **dans les creux ou derrière les ruptures de terrain** en milieu voir pied de pente, les hauts de pente étant souvent trop décapées par le vent.
Observables: accumulation de neige ventée derrière une rupture de pente, test de stabilité, fissures devant les skis, éventuellement encore quelques woumfs possible.

Départs spontanés : Peu probable à part **quelques départs ponctuels en poire de neige humide dans les faces ensoleillées** les plus raides. Départs souvent au pied des falaises ou rochers surchauffés par le soleil. **Taille 1.**

Qualité de la neige

Enneigement : Encore un peu au dessus de la moyenne , sauf aux plus basses altitudes où les hauteurs de neige sont tout juste correctes pour la saison.

Limite skiable : 1300m au mieux en Nord. Plutôt 1500 m en sud pas trop raide.

Qualité de la neige : Neige de printemps en sud : dure le matin juste ramollie comme il faut en descendant à la bonne heure (fonction de l'altitude et l'orientation)
En nord au dessus de 2000: Neige souvent travaillée par le vent: dure, irrégulière, carton suivant les endroits avec de rares combes protégées du vent encore en poudre assez légère. Crêtes et croupes souvent pelées ou en neige très dures (la glace ressort par endroit)
En Est et Ouest neige souvent croutée le matin puis mouillée ensuite , manque encore quelques cycles gel/dégel pour arriver à une parfaite neige de printemps.

Aperçu météo pour le vendredi 20 mars

	nuit	matin	après-midi	soir

Grand beau , voilé en fin de journée. Vent calme à tous niveaux

Pluie-Neige				
Iso 0 °C	2 200 m	2 300 m	2 500 m	2 200 m
Vent 2500 m	10 km/h	5 km/h	0 km/h	5 km/h
Vent 3500 m	20 km/h	20 km/h	15 km/h	15 km/h

Épaisseur de neige hors-piste

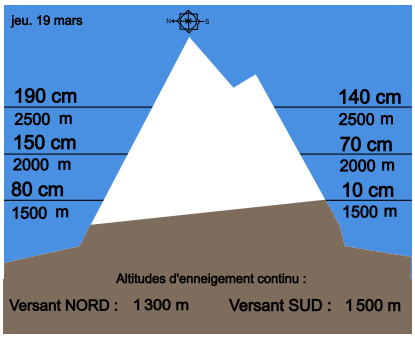

Précipitations à 1800 m

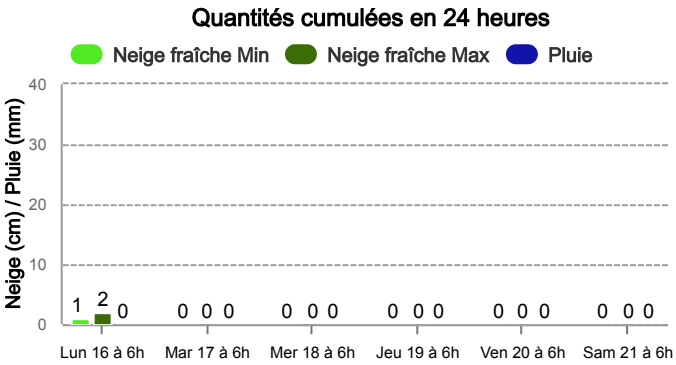

Tendance du samedi 21 mars

2

Indice de risque limité

Encore une belle journée samedi après un regel nocturne à peine moins bon (à cause d'un voile nuageux nocturne).
Risque en légère baisse avec de rares plaques dures résiduelles en versants ombragés d'altitude.

Pour consulter la vigilance en cours, veuillez vous rendre sur le site https://vigilance.meteofrance.fr/fr

Météo-France - 73 avenue de Paris, 94165 Saint-Mandé cedex - Contact : contact@meteo.fr

Rédigé par Météo-France avec la contribution des observateurs du réseau nivo-météorologiques. Partenariat : ANMSM (Maires de Stations de Montagne), DSF (Domaines Skiables de France), ADSP (Directeurs de Pistes et de la Sécurité des Stations de Sports d'Hiver) et autres acteurs de la montagne.

Bulletin neige & avalanches par téléphone au
0 892 68 10 20 Service 0,35 € / min + prix appel

RÉPUBLIQUE FRANÇAISE
Liberté Égalité Fraternité

METEO FRANCE
À VOS CÔTÉS, DANS UN CLIMAT QUI CHANGE

Bulletin d'estimation du risque d'avalanche
(valable en dehors des pistes balisées et ouvertes)

MASSIF : Vanoise

Rédigé le jeudi 19 mars 2026 à 16h

Conditions nivo-météo des 7 derniers jours

	ven. 13/03				sam. 14/03				dim. 15/03				lun. 16/03				mar. 17/03				mer. 18/03				jeu. 19/03			
	03h	09h	15h	21h	03h	09h	15h	21h	03h	09h	15h	21h	03h	09h	15h	21h	03h	09h	15h	21h	03h	09h	15h	21h	03h	09h	15h	21h
Météo																												
Vent (km/h)	20	25	35	65	50	15	35	40	30	40	20	15	30	40	40	30	30	30	30	30	35	45	60	50	40	20	15	15
à 3500m																												
Vent (km/h)	10	15	20	40	30	5	20	25	15	25	10	5	10	20	25	15	10	10	15	15	20	30	50	40	30	15	10	10
à 2500m																												

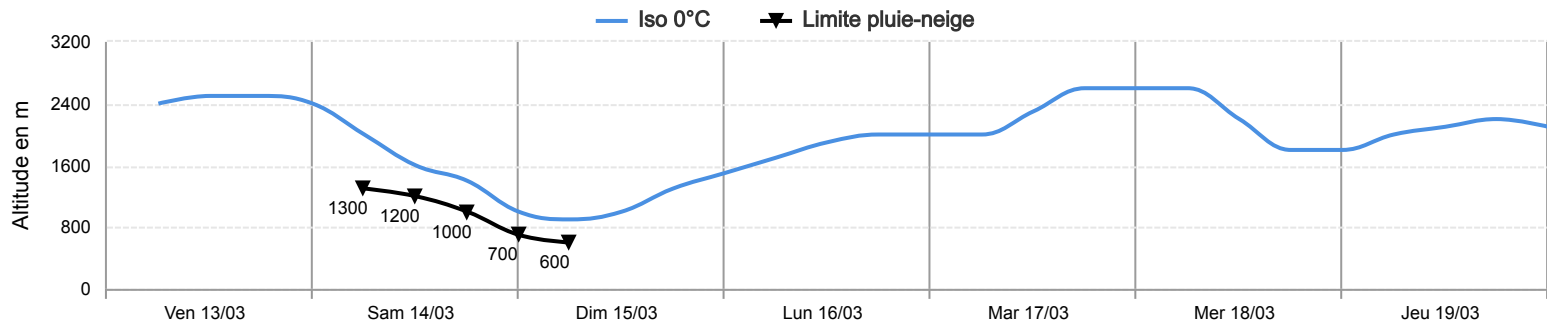

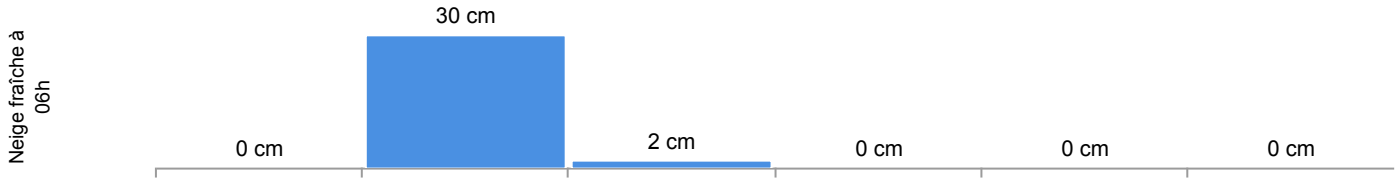

Risque d'avalanche	ven. 13/03	sam. 14/03	dim. 15/03	lun. 16/03	mar. 17/03	mer. 18/03	jeu. 19/03
	2	3	3	3	2	3	3

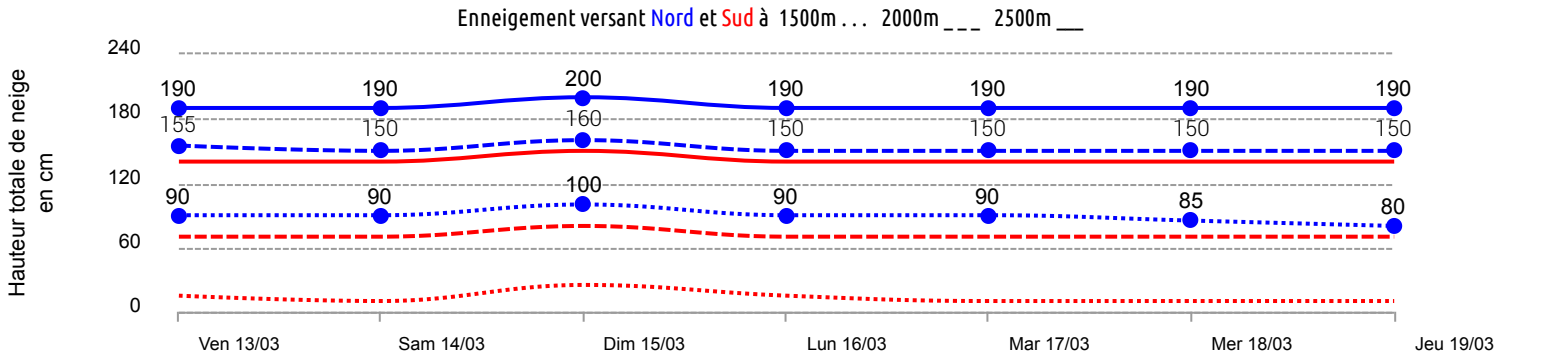

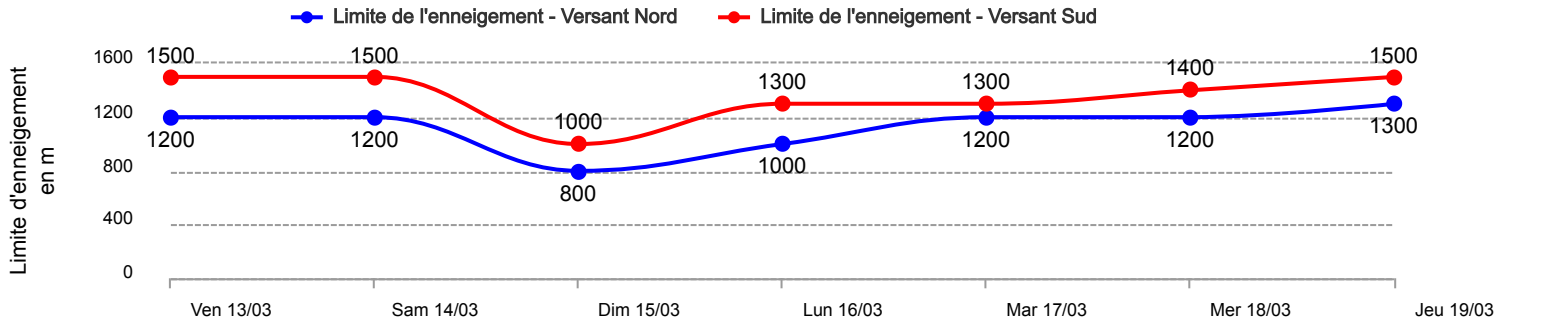

Pour consulter la vigilance en cours, veuillez vous rendre sur le site https://vigilance.meteofrance.fr/fr

Météo-France - 73 avenue de Paris, 94165 Saint-Mandé cedex - Contact : contact@meteo.fr

Rédigé par Météo-France avec la contribution des observateurs du réseau nivo-météorologiques. Partenariat : ANMSM (Maires de Stations de Montagne), DSF (Domaines Skiables de France), ADSP (Directeurs de Pistes et de la Sécurité des Stations de Sports d'Hiver) et autres acteurs de la montagne.

Bulletin neige & avalanches par téléphone au
0 892 68 10 20 Service 0,35 € / min + prix appel