GOBIERNO DE ESPAÑA
VICEPRESIDENCIA TERCERA DEL GOBIERNO
MINISTERIO PARA LA TRANSICIÓN ECOLÓGICA Y EL RETO DEMOGRÁFICO

Boletín de información nivológica y de peligro de aludes

Pirineo Catalán

aemet Agencia Estatal de Meteorología

viernes, 20 de marzo de 2026

Pronóstico hasta las 24 horas del sábado, día 21 de marzo

(Válido fuera de pistas de esquí balizadas y abiertas)

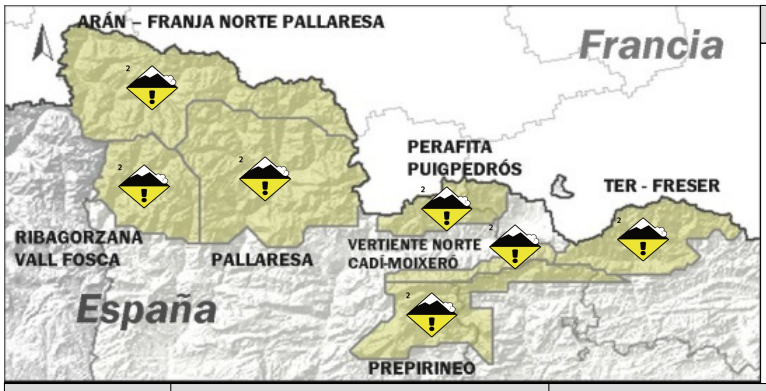

Problemas de aludes

Nieve húmeda

Capas débiles persistentes

Macizo	Peligro	Problemas de aludes, cota, orientación, tamaño	Innivación observada (m)
Arán - Franja norte Pallaresa	2 – 2 – **Limitado**	**Nieve húmeda** – 2 – N, O, E, S **Capas débiles persistentes** – 2400 – 2 – N, O, E, S	2026-03-20 N / S Cota más baja caras N
Ribagorzana - Vall Fosca	2 – 2 – **Limitado**	**Nieve húmeda** – 2 – N, O, E, S **Capas débiles persistentes** – 2400 – 2 – N, O, E, S	2026-03-20 N / S Cota más baja caras N
Pallaresa	2 – 2 – **Limitado**	**Nieve húmeda** – 2 – N, O, E, S **Capas débiles persistentes** – 2400 – 2 – N, O, E, S	2026-03-20 N / S Cota más baja caras N

AEMET. Se autoriza la reproducción de su contenido citando la fuente.

Boletín de información nivológica y de peligro de aludes

Pirineo Catalán

Perafita - Puigpedrós	2 **Limitado**	**Nieve húmeda**  **Capas débiles persistentes** 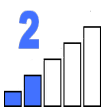	2026-03-20 Cota más baja caras N
Ter - Freser	2 **Limitado**	**Nieve húmeda** 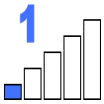 **Capas débiles persistentes** 	2026-03-20 Cota más baja caras N
Vertiente norte Cadí - Moixeró	2 **Limitado**	**Nieve húmeda** 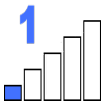	2026-03-20 Cota más baja caras N
Prepirineo	2 **Limitado**	**Nieve húmeda** 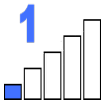	2026-03-20 Cota más baja caras N

Estado del manto y observaciones recientes

Continúan los procesos de fusión y apelmazamiento de la nieve, con unos espesores que durante las últimas 24 horas han disminuido, en general, varios cm, exceptuando áreas del valle de Arán y Franja Norte Pallaresa, donde se han producido algunas precipitaciones débiles que han depositado una leve capa de nieve reciente en cotas altas. El manto sigue presentando continuidad desde medianías, aunque a mayor altitud en la solanas, donde la insolación lo ha erosionado con relativa intensidad. Los espesores siguen estando muy por encima de lo que cabría esperar a estas alturas de la temporada, superándose frecuentemente los 200 cm por encima de 2.100 ó 2.200 metros.

La nieve se encuentra muy humedecida en zonas medias y bajas. En cotas altas hallamos nieve húmeda superficial en las solanas que está sometida al ciclo de fusión diurna y rehielo nocturno; en las umbrías predomina la nieve más seca, venteada y encostrada, pudiendo existir estratos débiles en el interior del manto localizados a no demasiada profundidad.

AEMET. Se autoriza la reproducción de su contenido citando la fuente.

Evolución del manto y peligro de aludes para el sábado, día 21

Situación de nieve húmeda. En cotas altas, capas débiles persistentes y placas de viento.

Las heladas nocturnas previstas favorecerán la formación de costras de rehielo sobre la superficie del manto, lo que facilitará que se mantenga estable a primeras horas, pero según transcurra la mañana, con el aumento de la insolación, esta costra tenderá a fundirse y la nieve se irá reblandeciendo progresivamente, lo que podrá dar lugar a purgas de nieve vieja húmeda en pendientes con suficiente inclinación, siendo más probables en áreas de solana y por debajo de unos 2.400 metros en el resto de orientaciones. En general serían de tamaño pequeño o mediano, aunque cabe la posibilidad de que en laderas herbosas o de roca lisa pueda haber algún deslizamiento basal que adquiera una mayor magnitud.

En umbrías de cotas altas persisten estratos débiles en el interior del manto sobre los cuales pueden descansar antiguas placas de viento, sobre todo en las cercanías de crestas y collados. Estas estructuras son susceptibles de fracturarse ante una sobrecarga débil, como es el paso de un esquiador, dando lugar a aludes de dimensiones medianas, sin poder descartarse que, de manera muy local, puedan llegar a ser de tamaño grande, suficiente como para enterrar a un grupo de personas, por lo que se recomienda tomar precauciones durante el tránsito por la zona.

Predicción meteorológica para el sábado, día 21

Poco nuboso o despejado durante la primera mitad del día. Por la tarde, algunas nubes de evolución diurna y aumento de la nubosidad de tipo bajo en el valle de Arán y resto de la divisoria fronteriza. Temperaturas mínimas en ligero descenso en los valles y en ligero o moderado ascenso en medianías y cumbres. Las máximas experimentarán pocos cambios. Heladas débiles, localmente moderadas. Vientos flojos de dirección variable, tendiendo a flojos o moderados de componente norte.

Datos en la atmósfera libre:

Altitud de la isoterma de 0 ºC: 2.400 m
Altitud de la isoterma de -10 ºC: 4.000 m

Viento a 1500 m: S 10 km/h
Viento a 3000 m: N 10 km/h

Evolución para el domingo día 22

Nivel de peligro por nieve húmeda en ligero descenso.

Escala europea de peligro de aludes

Problemas de aludes

Nota1: Se recuerda que, siempre que haya nieve, la ausencia total de peligro no existe. Hay que tener presente que en circunstancias desfavorables, con aludes de tamaño 1 (alud pequeño o colada) y tamaño 2 (alud mediano), se pueden sufrir severos daños personales.

Nota2: Los BPA se elaboran en base a información meteorológica así como al estado del manto nivoso a través de sondeos puntuales. Se advierte a los usuarios de la variabilidad de esta información al extrapolarla a zonas extensas de montaña. Por ello, AEMET no se hace responsable de su uso para la toma de decisiones que conciernen a la seguridad personal, ni de los riesgos físicos o materiales de ellas

AEMET. Se autoriza la reproducción de su contenido citando la fuente.

derivadas.

AEMET. Se autoriza la reproducción de su contenido citando la fuente.