Samstag 21.03.2026

Veröffentlicht am 20.03.2026 um 17:00

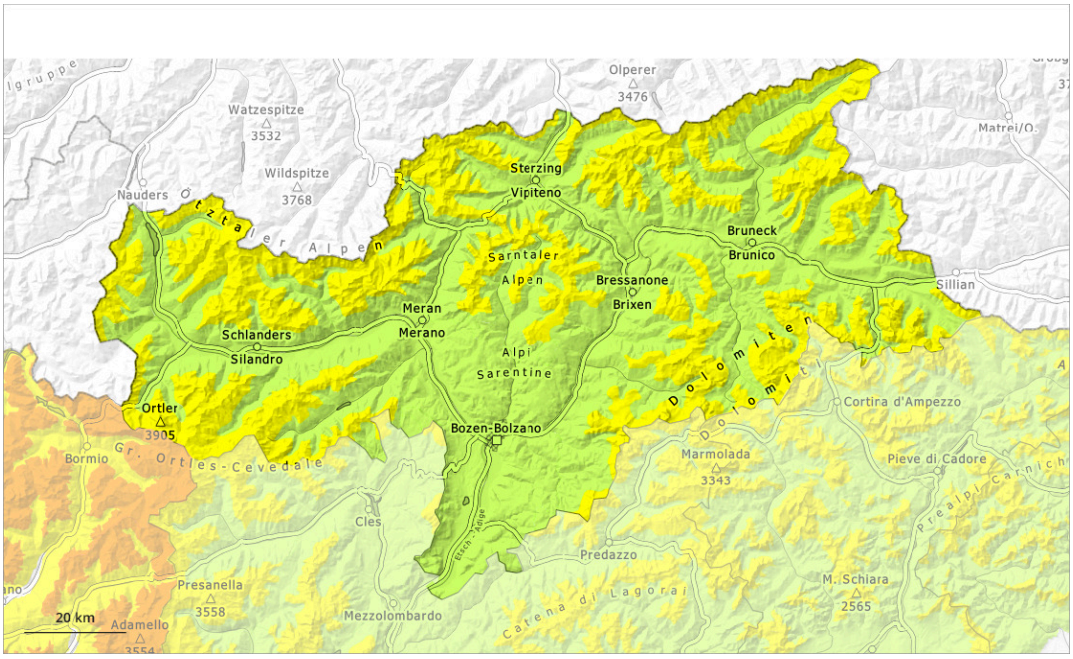

1	2	3	4	5
gering	mäßig	erheblich	groß	sehr groß

Gefahrenstufe 2 - Mäßig

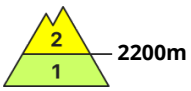

Tendenz: Lawinengefahr bleibt gleich
am Sonntag, den 22.03.2026

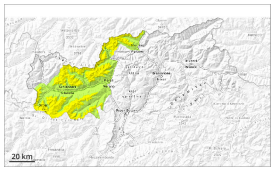

Triebschnee

Altschnee

Triebschnee und schwachen Altschnee vorsichtig beurteilen.

Schon einzelne Wintersportler können stellenweise Lawinen auslösen. Diese können teilweise in oberflächennahen Schichten anreißen und mittlere Größe erreichen, besonders an sehr steilen Schattenhängen oberhalb von rund 2200 m sowie an sehr steilen Sonnenhängen oberhalb von rund 2500 m. Gefahrenstellen liegen in Rinnen, Mulden und hinter Geländekanten.
Einzelne Wummgeräusche können auf die Gefahr hinweisen. Fernauslösungen sind vereinzelt möglich.

Zudem können vereinzelt Lawinen in bodennahen Schichten anreißen. Die Gefahrenstellen liegen vor allem an sehr steilen West-, Nord- und Osthängen oberhalb von rund 2200 m. Solche Gefahrenstellen sind selten aber kaum zu erkennen. Ungünstig sind besonders Übergänge von wenig zu viel Schnee. Lawinen können vereinzelt groß werden.

Schneedecke

Gefahrenmuster gm.6: lockerer schnee und wind | gm.7: schneearm neben schneereich

Es fallen lokal bis zu 10 cm Schnee.

West-, Nord- und Osthänge oberhalb von rund 2200 m:
Triebschneeansammlungen liegen auf einer ungünstigen Altschneeoberfläche.
Im unteren Teil der Schneedecke sind störanfällige Schwachschichten vorhanden.

Steile Sonnenhänge: Sonne und Wärme führen zu einer Anfeuchtung der Schneedecke. Dies vor allem bei Sonneneinstrahlung.

Tendenz

In der Nacht fallen bis zu 10 cm Schnee, lokal auch mehr. Triebschnee und schwachen Altschnee beachten.

Gefahrenstufe 2 - Mäßig

2200m

Tendenz: Lawinengefahr bleibt gleich
am Sonntag, den 22.03.2026

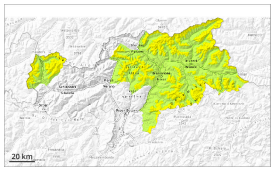

Triebschnee

2200m

Altschnee

2200m

Triebschnee und schwachen Altschnee beachten.

Die schon etwas älteren Triebschneeansammlungen können stellenweise leicht ausgelöst werden, besonders an sehr steilen West-, Nord- und Osthängen oberhalb von rund 2200 m. Gefahrenstellen liegen in Rinnen, Mulden und hinter Geländekanten. Sie sind für Geübte gut zu erkennen. Es sind kleine und vereinzelt mittlere Lawinen möglich.

Zudem können vereinzelt Lawinen in bodennahen Schichten anreißen. Solche Gefahrenstellen sind selten aber kaum zu erkennen. Ungünstig sind besonders Übergänge von wenig zu viel Schnee.

Schneedecke

Gefahrenmuster gm.6: lockerer schnee und wind | gm.7: schneearm neben schneereich

Es fallen lokal bis zu 10 cm Schnee.

West-, Nord- und Osthänge oberhalb von rund 2200 m:
Triebschneeansammlungen liegen auf einer ungünstigen Altschneeoberfläche.
Im unteren Teil der Schneedecke sind störanfällige Schwachschichten vorhanden.

Steile Sonnenhänge: Sonne und Wärme führen zu einer Anfeuchtung der Schneedecke. Dies vor allem bei Sonneneinstrahlung.

Tendenz

In der Nacht fallen bis zu 10 cm Schnee, lokal auch mehr. Triebschnee und schwachen Altschnee beachten.

Gefahrenstufe 1 - Gering

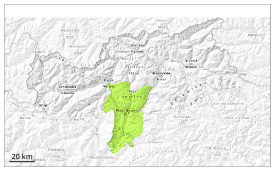

1

Tendenz: Lawinengefahr bleibt gleich
am Sonntag, den 22.03.2026

Geringe Lawinengefahr.

Trockene Lawinen können vor allem mit großer Belastung ausgelöst werden, sind aber meist klein.
Einzelne Gefahrenstellen liegen an steilen Schattenhängen in hohen Lagen.
Mit der tageszeitlichen Erwärmung sind einzelne feuchte Rutsche und Lawinen möglich, aber meist nur kleine, vor allem an extrem steilen Hängen bei Sonneneinstrahlung.

Schneedecke

Gefahrenmuster gm.10: frühjahrssituation

Es fällt lokal etwas Schnee.

Schattenhänge: In der Altschneedecke sind v.a. an Nordwest-, Nord- und Nordosthängen vereinzelt störanfällige Schwachschichten vorhanden.

Sonnenhänge: Die Altschneedecke ist feucht. Die Wetterbedingungen führen in mittleren und hohen Lagen zu einer Durchnässung der Schneedecke.

Tendenz

Geringe Lawinengefahr. In der Nacht fällt lokal etwas Schnee.