ICGC Institut Cartogràfic i Geològic de Catalunya

Servei Meteorològic de Catalunya meteo.cat

Boletín de peligro de aludes para el Pirineo de Catalunya
Del 20/03/2026 al 21/03/2026

(Válido fuera pistas de esquí y zonas no controladas)

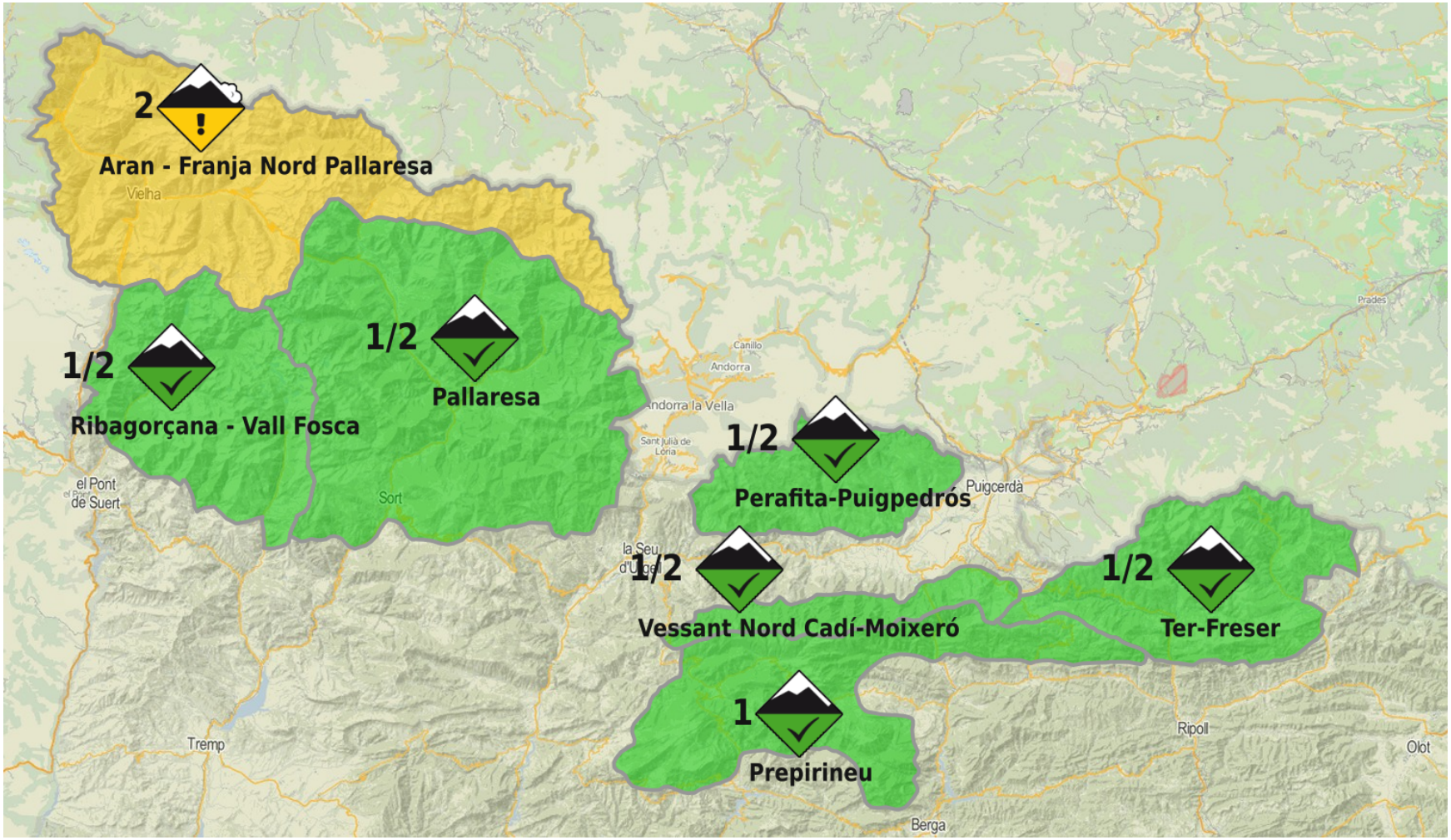

5 MUY FUERTE	4 FUERTE	3 NOTABLE	2 LIMITADO	1 DÉBIL

ICGC Institut Cartogràfic i Geològic de Catalunya

Servei Meteorològic de Catalunya

Boletín de peligro de aludes Aran - Franja Nord Pallaresa Del 20/03/2026 al 21/03/2026

(Válido fuera pistas de esquí y zonas no controladas)

LIMITADO (2).

Situación primaria

Capas débiles persistentes

Distribución

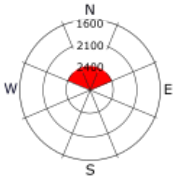

Tamaño

Origen

Tendencia

Situación secundaria

Nieve húmeda

Distribución

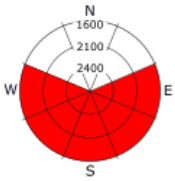

Tamaño

Origen

Tendencia

Estado del manto nivoso

Para el sábado encontraremos un manto rehelado a primera hora y bien asentado, sobre todo en solanas. En umbrías, en cambio, el manto todavía presenta una estabilidad pobre, especialmente las placas antiguas que permanecen sobre facetas o escarcha. Los lugares más delicados son las vertientes umbrías inclinadas y poco frecuentadas, por encima de los 2.400 m. En estos lugares podremos desencadenar aludes de tamaño 2 (medio), con capacidad de enterrar a una persona e, incluso, de tamaño 3 (grande), suficiente para enterrar a un grupo de montañeros, sobre todo en las vertientes umbrías protegidas y poco frecuentadas. Con el viento del E se habrá movido la nieve más reciente y se habrán formado placas de viento nuevas, de pequeño tamaño, bajo collados y crestas en O y N. Son probables también aludes de nieve húmeda, a partir de mediodía, de hasta tamaño 2 (medio), en todas las cotas, en medias y hasta solanas. No se descarta algún deslizamiento basal, en solanas, de hasta tamaño grande.

Distribución del manto nivoso

Hay nieve por encima de unos 1-500 m en umbrías y 1.800 m en solanas. Los espesores a unos 2.200 m son ligeramente superiores a los normales en la Franja Norte de la Pallaresa y en la mitad sur de Arán donde rondan los 180-220 cm. En la mitad norte de Arán son los normales por estas fechas con unos 120-140 cm de espesor total.

Tendencia para las próximas 48-72h

Continuaremos con problemas por nieve húmeda a mediodía y por las capas débiles persistentes en umbrías elevadas. Peligro: SIN CAMBIOS

El próximo boletín será emitido el día 2026-03-21

5 MUY FUERTE	4 FUERTE	3 NOTABLE	2 LIMITADO	1 DÉBIL

EAWS EUROPEAN AVALANCHE WARNING SERVICES

ICGC Institut Cartogràfic i Geològic de Catalunya

Servei Meteorològic de Catalunya

Boletín de peligro de aludes Ribagorçana - Vall Fosca Del 20/03/2026 al 21/03/2026

(Válido fuera pistas de esquí y zonas no controladas)

DÉBIL (1), LIMITADO (2), a partir de mediodía.

Situación primaria

Nieve húmeda

Distribución

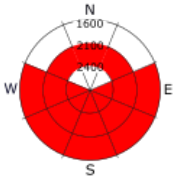

Tamaño

Origen

Tendencia

Estado del manto nivoso

Para el sábado esperamos una dinámica primaveral, con una mañana con rehielo y una transformación de la nieve a mediodía a causa de la radiación. Con el humedecimiento del manto pueden caer aludes de fusión de forma natural que llegarán a tamaño 1 (pequeño), sin capacidad para enterrar a una persona. El terreno más afectado por aludes de fusión son las salidas de puntos oscuros (rocas y árboles) y las canales a solanas. No se descartan tampoco a umbrías de cota media. En umbrías elevadas, en el límite norte del sector, podemos encontrar, localmente, alguna placa antigua que con una carga fuerte, podría acabar cayendo. Los lugares delicados están bajo collados y cordales, por encima de 2.500 m y también en las orientaciones umbrías resguardadas y poco frecuentadas. Las placas, en caso de romperse, podrán generar aludes de tamaño 2 (medio), con capacidad de enterrar a un montañero. Habrá que vigilar con los resbalones a primera hora, por la presencia de costras duras.

Distribución del manto nivoso

Hay nieve en el suelo a 1.600 m en terreno umbrío, y por encima de unos 1.800 m en laderas soleadas. El manto es esquiable por encima de unos 1.800-1.900 m en umbrías. Los grosores alcanzan los 105-135 cm a unos 2.200 m. Estos valores son superiores a los normales para la época.

Tendencia para las próximas 48-72h

El domingo tarde y lunes puede nevar, con un poco de viento en altura Peligro: SIN CAMBIOS o EN LEVE ASCENSO.

El próximo boletín será emitido el día 2026-03-21

5 MUY FUERTE	4 FUERTE	3 NOTABLE	2 LIMITADO	1 DÉBIL

EAWS EUROPEAN AVALANCHE WARNING SERVICES

ICGC Institut Cartogràfic i Geològic de Catalunya

Servei Meteorològic de Catalunya

Boletín de peligro de aludes Pallaresa
Del 20/03/2026 al 21/03/2026

(Válido fuera pistas de esquí y zonas no controladas)

DÉBIL (1), LIMITADO (2), a partir de mediodía.

Situación primaria

Nieve húmeda

Distribución

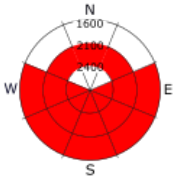

Tamaño

Origen

Tendencia

Estado del manto nivoso

Para el sábado esperamos una dinámica primaveral, con una mañana con rehielo y una transformación de la nieve a mediodía a causa de la radiación. Con el humedecimiento del manto pueden caer aludes de fusión de forma natural que llegarán a tamaño 1 (pequeño), sin capacidad para enterrar a una persona. El terreno más afectado por aludes de fusión son las salidas de puntos oscuros (rocas y árboles) y las canales a solanas. No se descartan tampoco a umbrías de cota media. En umbrías elevadas, en el límite norte del sector, podemos encontrar, localmente, alguna placa antigua que con una carga fuerte, podría acabar cayendo. Los lugares delicados están bajo collados y cordales, por encima de 2.500 m y también en las orientaciones umbrías resguardadas y poco frecuentadas. Las placas, en caso de romperse, podrán generar aludes de tamaño 2 (media), con capacidad de enterrar a un montañero. Habrá que vigilar con los resbalones a primera hora, por la presencia de costras duras.

Distribución del manto nivoso

Hay nieve en el suelo a 1.600 m en N, y a 1.800-1.900 m en S. El manto es esquiable por encima de unos 1.800-1.900 m en umbrías. Los espesores alcanzan los 115-155 cm en cotas medias, variable según los efectos del viento.

Tendencia para las próximas 48-72h

El domingo tarde y lunes puede nevar, con un poco de viento en altura. Peligro: SIN CAMBIOS o EN LEVE ASCENSO.

El próximo boletín será emitido el día 2026-03-21

5 MUY FUERTE	4 FUERTE	3 NOTABLE	2 LIMITADO	1 DÉBIL

EAWS EUROPEAN AVALANCHE WARNING SERVICES

ICGC Institut Cartogràfic i Geològic de Catalunya

Servei Meteorològic de Catalunya meteo.cat

Boletín de peligro de aludes Perafita-Puigpedrós Del 20/03/2026 al 21/03/2026

(Válido fuera pistas de esquí y zonas no controladas)

DÉBIL (1), LIMITADO (2), a partir de mediodía.

Situación primaria

Nieve húmeda

Distribución

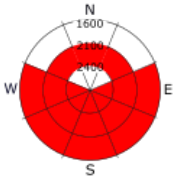

Tamaño

Origen

Tendencia

Estado del manto nivoso

Para el sábado esperamos una dinámica primaveral, con una mañana con rehielo y una transformación de la nieve a mediodía a causa de la radiación. Con el humedecimiento del manto pueden caer aludes de fusión de forma natural que llegarán a tamaño 1 (pequeño), sin capacidad para enterrar a una persona. El terreno más afectado por aludes de fusión son las salidas de puntos oscuros (rocas y árboles) y las canales a solanas. No se descartan tampoco a umbrías de cota media. En umbrías elevadas, en el límite norte del sector, podemos encontrar, localmente, alguna placa antigua que con una carga fuerte, podría acabar cayendo. Los lugares delicados están bajo collados y cordales, por encima de 2.500 m y también en las orientaciones umbrías resguardadas y poco frecuentadas. Las placas, en caso de romperse, podrán generar aludes de tamaño 2 (medio), con capacidad de enterrar a un montañero. Habrá que vigilar con los resbalones a primera hora, por la presencia de costras duras.

Distribución del manto nivoso

En umbrías hay nieve por encima de 1.400-1.500 m, y en las solanas está presente por encima de 1.700 m. Los espesores, aunque irregulares, rondan los 85-105 cm en cotas medias. Son grosores por encima de los habituales para la época.

Tendencia para las próximas 48-72h

El domingo tarde y lunes puede nevar, con un poco de viento en altura. Peligro: SIN CAMBIOS o EN LEVE ASCENSO.

El próximo boletín será emitido el día 2026-03-21

5 MUY FUERTE	4 FUERTE	3 NOTABLE	2 LIMITADO	1 DÉBIL

EAWS EUROPEAN AVALANCHE WARNING SERVICES

ICGC Institut Cartogràfic i Geològic de Catalunya

Servei Meteorològic de Catalunya meteo.cat

Boletín de peligro de aludes
Vessant Nord Cadí-Moixeró
Del 20/03/2026 al 21/03/2026

(Válido fuera pistas de esquí y zonas no controladas)

DÉBIL (1), LIMITADO (2), durante las horas centrales del día por encima de los 2.200 m.

Situación primaria

Nieve húmeda

Distribución

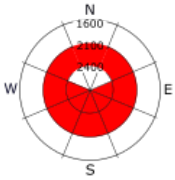

Tamaño

Origen

Tendencia

Estado del manto nivoso

El sábado se espera un manto rehelado y endurecido a primera hora. Con el avance de la jornada, el humedecimiento superficial del manto irá avanzando y pueden caer aludes pequeños de fusión de forma natural y también a nuestro paso (al ablandarse las costras), sin capacidad para enterrar a una persona, excepto en terreno trampa donde habrá que evitar pasar mientras la nieve no regele. El terreno más afectado por aludes de fusión son las zonas de salida de puntos oscuros como rocas y árboles.
Habrá que vigilar los resbalones, sobre todo en lo alto de las Canals y bajo collados y crestas más elevadas.

Distribución del manto nivoso

En umbrías hay presencia discontinua de nieve por encima de 1.600 my es esquiable por encima de 1.900 m. Los grosores están alrededor de 160-180 cm a 2.200 m. Estos valores son muy excedentarios para la época del año.

Tendencia para las próximas 48-72h

Seguiremos con dinámica primaveral, con fusión-rehielo. Peligro: SIN CAMBIOS.

El próximo boletín será emitido el día 2026-03-21

5 MUY FUERTE	4 FUERTE	3 NOTABLE	2 LIMITADO	1 DÉBIL

EAWS EUROPEAN AVALANCHE WARNING SERVICES

ICGC Institut Cartogràfic i Geològic de Catalunya

Servei Meteorològic de Catalunya

Boletín de peligro de aludes Prepirineu
Del 20/03/2026 al 21/03/2026

(Válido fuera pistas de esquí y zonas no controladas)

DÉBIL (1).

Situación primaria

Nieve húmeda

Distribución

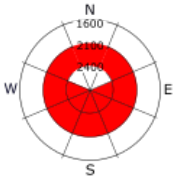

Tamaño

Origen

Tendencia

Estado del manto nivoso

El manto se muestra bastante asentado y endurecido internamente, con presencia de costras duras, grano fino y algunas formas mixtas. Por el sábado se espera rehielo, después de una madrugada serena, y el manto se mostrará asentado. Con el humedecimiento, a partir de mediodía, debido a la transformación de la nieve por la radiación solar, no se descarta la caída de bolas o de algún alud húmedo, pequeño, que no tendrá capacidad para enterrar a una persona, excepto en terreno trampa donde habrá que evitar pasar mientras la nieve no hiele. Las orientaciones más sensibles a la caída de aludes de nieve húmeda son las orientadas a Este, Sur y Oeste, así como las umbrías de cota media. Habrá que vigilar con los resbalones, sobre todo por la mañana.

Distribución del manto nivoso

En umbrías hay nieve por encima de 1700 m. En solanas la nieve está presente por encima de 1.900 m. Los espesores, aunque irregulares, rondan los 65-85 cm en cotas medias.

Tendencia para las próximas 48-72h

Seguiremos con dinámica primaveral, con fusión-rehielo. Peligro: SIN CAMBIOS.

El próximo boletín será emitido el día 2026-03-21

5 MUY FUERTE	4 FUERTE	3 NOTABLE	2 LIMITADO	1 DÉBIL

EAWS EUROPEAN AVALANCHE WARNING SERVICES

ICGC Institut Cartogràfic i Geològic de Catalunya

Servei Meteorològic de Catalunya

Boletín de peligro de aludes Ter-Freser Del 20/03/2026 al 21/03/2026

(Válido fuera pistas de esquí y zonas no controladas)

DÉBIL (1), LIMITADO (2), a partir de mediodía.

Situación primaria

Nieve húmeda

Distribución

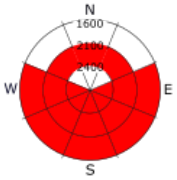

Tamaño

Origen

Tendencia

Estado del manto nivoso

Vamos a seguir con una dinámica primaveral. A primera hora el manto se mostrará asentado y endurecido superficialmente a causa del rehielo, pero el humedecimiento avanzará con el paso de las horas debido a la radiación solar. En solanas o en umbrías de cota media, en terreno con fuerte inclinación, pueden caer aludes naturales de fusión de forma natural o en nuestro paso esquiando que llegarán a tamaño 1(pequeño), sin capacidad para enterrar a una persona. También es posible encontrar alguna placa antigua, donde el viento no haya deflactado las laderas y sobre algún nivel débil que podría caer a nuestro paso, con una sobrecarga fuerte. Serían muy locales, bajo collados y cordales por encima de 2.400 m, en orientaciones que van de E hacia S. En caso de romperse alguna placa se generarán aludes de hasta tamaño medio (con capacidad de enterrar a una persona). Habrá que vigilar con los resbalones a primera hora, por la presencia de costras duras.

Distribución del manto nivoso

Hay nieve en el suelo por encima de 1.700 m. El manto es esquiable a umbrías a partir de unos 1.700 m. Los grosores son muy excedentarios para la época del año y en lugares no afectados por el viento oscilan entre 85-105 cm a unos 2.000 m y más de 150 cm por encima de 2.400 m.

Tendencia para las próximas 48-72h

El domingo tarde y lunes puede nevar, con un poco de viento en altura. Peligro: SIN CAMBIOS o EN LEVE ASCENSO.

El próximo boletín será emitido el día 2026-03-21

5 MUY FUERTE	4 FUERTE	3 NOTABLE	2 LIMITADO	1 DÉBIL

EAWS EUROPEAN AVALANCHE WARNING SERVICES