BUTLLETÍ DEL PERILL D'ALLAUS DEL PRINCIPAT D'ANDORRA

Servei meteorològic nacional
Principat d'Andorra

Elaborat el 20/03/2026 16:00
Propera actualització 21/03/2026 a les 16h

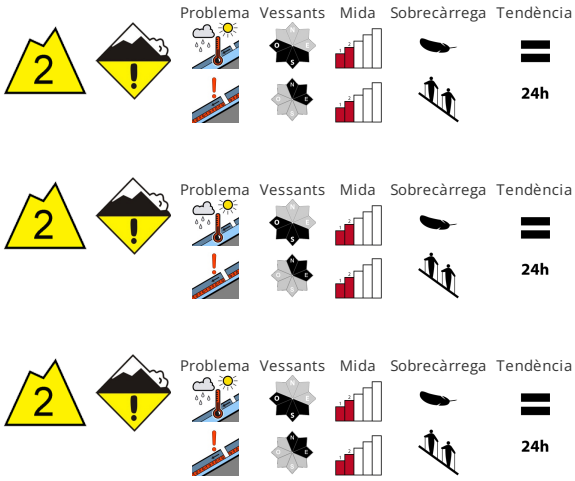

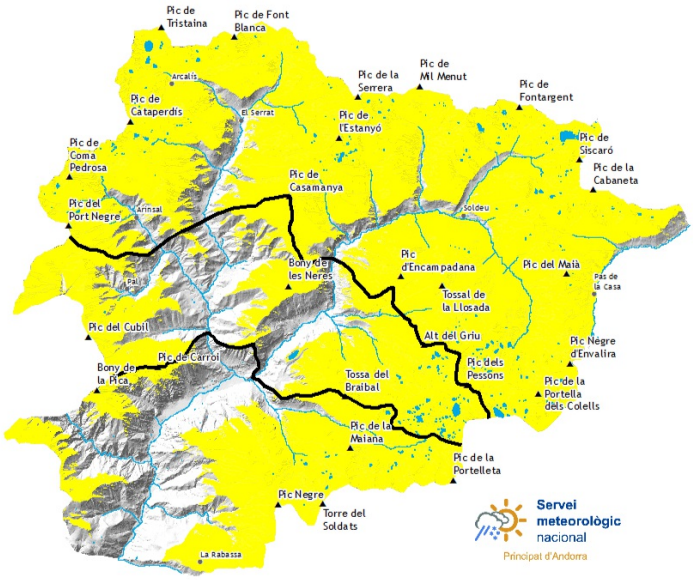

ESTABILITAT DEL MANTELL NIVAL

Amb l'augment de la temperatura diürna i la radiació solar, són probables allaus de neu humida de mida petita i mitjana. Això es dona especialment en vessants assolellats inclinats., precaució a la base de parets rocoses. A més en el transcurs de la jornada són possibles algunes allaus de lliscament basal. També a cotes altes :. Sobretot als vessants inclinats orientats a , nord i est a la part superior del mantell de neu hi ha , de manera aïllada, capes febles inestables. Aquestes poden ser desencadenades sobretot per una sobrecàrrega forta i assolir mida mitjana. Els indrets perillosos es troben prop del límit del bosc i també a les transicions de mantell prim a gruixut. A més del perill de ser enterrat per una allau, cal tenir en compte sobretot el perill de ser arrossegat cap a una trampa del terreny.

QUALITAT DE LA NEU

A cotes baixes i mitges :. La superfície del mantell de neu es regelarà per formar una crosta portant i s'estovarà ja durant el matí. A causa de la superfície dura del mantell de neu hi ha el perill de relliscar i caure als vessants inclinats. Prop de les carenes els gruixos de neu varien molt per la influència del vent. Les capes febles a la part superior del mantell de neu requereixen cautela. Es recomana mantenir la distància entre els components.

GRUIXOS DEL MANTELL NIVAL FORA DE PISTA

Zona nord		Gruix neu		
Mantell Nival		1500m	2000m	2500m
N	1600 m	0 cm	150 cm	200 cm
S	1900 m	0 cm	100 cm	150 cm

Zona centre		Gruix neu		
Mantell Nival		1500m	2000m	2500m
N	1600 m	0 cm	150 cm	200 cm
S	1900 m	0 cm	100 cm	150 cm

Zona sud		Gruix neu		
Mantell Nival		1500m	2000m	2500m
N	1600 m	0 cm	120 cm	150 cm
S	1900 m	0 cm	60 cm	100 cm

Govern d'Andorra

EAWS
EUROPEAN AVALANCHE WARNING SERVICES

Aquest butlletí ha estat elaborat seguint les normes i recomanacions de l'**European Avalanche Warning Services**, del qual el **Servei meteorològic Nacional** n'és membre

BUTLLETÍ DEL PERILL D'ALLAUS DEL PRINCIPAT D'ANDORRA

Servei meteorològic nacional
Principat d'Andorra

Informació detallada per espais naturals protegits

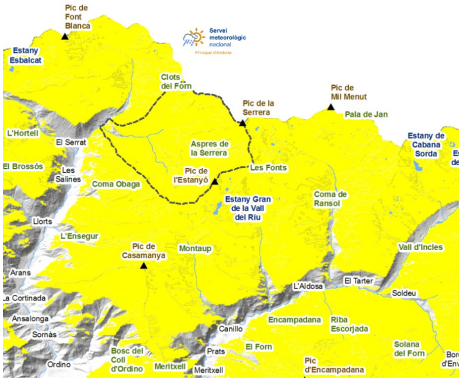

SORTENY

El regel de primeres hores aportarà bones condicions per circular per la muntanya, mantenint la cautela en els vessants nord i est on poden haver-hi capes febles persistents. En el transcurs de la jornada i amb la penetració de la humitat, tornarem a tenir neu tova i humida per sota de 2.200 metres.

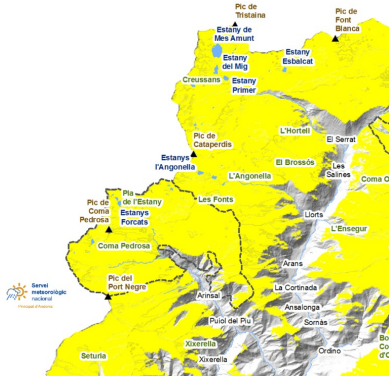

COMAPEDROSA

Com a tot el país, haurem de prestar atenció als problemes de neu humida en els vessants assolellats més inclinats i als peus de parets rocoses. Esperem activitat d´allaus de fons amb les esquerdes obertes. Als vessants nord i est trobem capes febles encara sol·licitables, amb les que haurem de fer atenció.

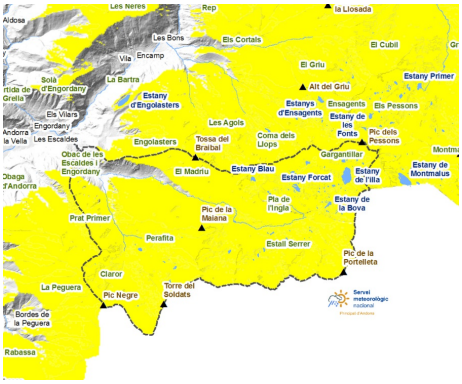

MADRIU-PERAFITA-CLAROR

Amb la precipitació i humitat de dijous la neu ha patit un retrocés important a cotes baixes, tot i que hi ha neu suficient per fer nombroses rutes. Haurem de tenir en compte que, a cotes mitges, trobarem neu dura i regelada a primeres hores però que s´estovarà amb la presència del sol, i ser cautelosos als vessants amb problemes de capes febles persistents.

Govern d'Andorra

EAWS
EUROPEAN AVALANCHE WARNING SERVICES

Aquest butlletí ha estat elaborat seguint les normes i recomanacions de l'**European Avalanche Warning Services**, del qual el **Servei meteorològic Nacional** n'és membre

BUTLLETÍ DEL PERILL D'ALLAUS DEL PRINCIPAT D'ANDORRA

Servei meteorològic nacional
Principat d'Andorra

Gruixos de neu nova dels darrers dies (de les últimes 24h mesurat a les 06:00h UTC)

	16/03/2026	17/03/2026	18/03/2026	19/03/2026
FEDA (Central)	0 cm	0 cm	0 cm	0 cm
Engolasters - FEDA	0 cm	0 cm	0 cm	0 cm
Bony de les Neres	0 cm	0 cm	0 cm	0 cm
Sorteny	0 cm	0 cm	0 cm	0 cm
Les Fonts d'Arinsal	0 cm	0 cm	0 cm	0 cm
Perafita	0 cm	0 cm	0 cm	0 cm
Tossa Espiolets	0 cm	0 cm	0 cm	0 cm
Grau Roig - FEDA	0 cm	0 cm	1 cm	0 cm
Fontverd	0 cm	0 cm	0 cm	0 cm
Ransol - FEDA	0 cm	0 cm	0 cm	0 cm
Caborreu	0 cm	0 cm	0 cm	0 cm
La Solana	0 cm	0 cm	0 cm	0 cm
Coll Pa	0 cm	0 cm	3 cm	0 cm
Envalira Antenes	0 cm	0 cm	0 cm	0 cm
Vall del Riu FEDA	0 cm	0 cm	2 cm	0 cm