BUTLLETÍ DEL PERILL D'ALLAUS DEL PRINCIPAT D'ANDORRA

Elaborado el 20/03/2026 16:00
Proxima actualización 21/03/2026 a las 16h

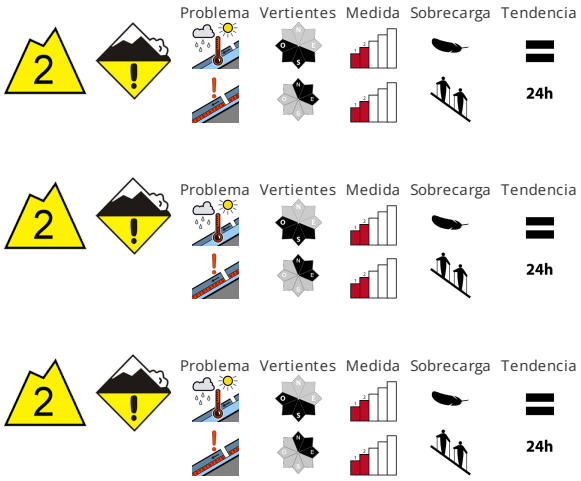

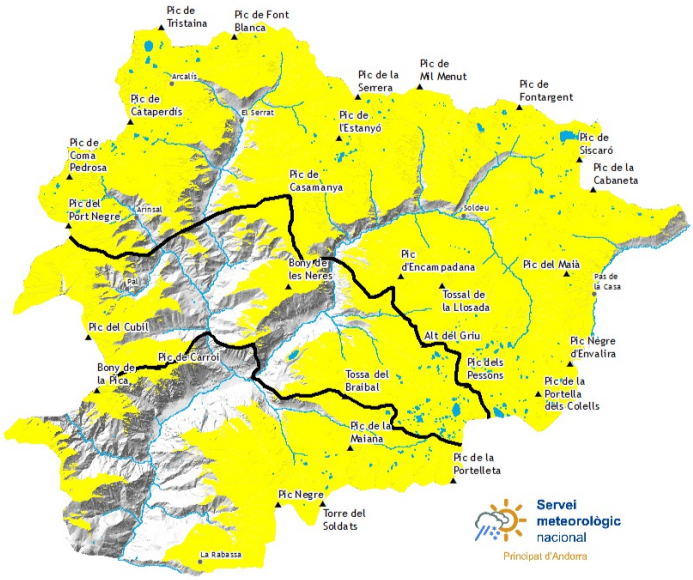

CALIDAD DE LA NIEVE

Con la subida de la temperatura diurna y la radiación solar, son probables avalanchas de nieve húmeda de tamaño pequeño y mediano. Esto se da especialmente en las laderas solanas inclinadas., precaución en la base de las paredes rocosas. Además en el transcurso de la jornada son posibles algunas avalanchas de deslizamiento basal. También en cotas altas :. Sobre todo en las laderas inclinadas orientadas a norte y este en la parte superior del manto de nieve hay , de manera aislada, capas débiles inestables. Estas pueden ser desencadenadas sobre todo por una sobrecarga fuerte y alcanzar un tamaño mediano. Los lugares peligrosos se encuentran cerca del límite del bosque y en las transiciones de manto delgado a grueso. Además del peligro de ser enterrado por un alud, se debe tener en cuenta sobre todo el peligro de ser arrastrado hacia una trampa del terreno.

ESTABILIDAD DEL MANTO NIVOSO

En cotas bajas y medias :. La superficie del manto de nieve se volverá a helar para formar una costra portante y se ablandará ya durante la mañana. Debido a la superficie dura del manto de nieve hay el peligro de resbalar y caer en las laderas inclinadas. Cerca de los cordales los espesores de nieve varían mucho por la influencia del viento. Las capas débiles en la parte superior del manto de nieve requieren cautela. Se recomienda mantener la distancia de seguridad entre los miembros del grupo.

ESPESORES DEL MANTO NIVOSO FUERA DE PISTA

BUTLLETÍ DEL PERILL D'ALLAUS DEL PRINCIPAT D'ANDORRA

Servei meteorològic nacional
Principat d'Andorra

Zona norte		Espesor nieve		
Manto Nival		1500m	2000m	2500m
N	1600 m	0 cm	150 cm	200 cm
S	1900 m	0 cm	100 cm	150 cm

Zona centro		Espesor nieve		
Manto Nival		1500m	2000m	2500m
N	1600 m	0 cm	150 cm	200 cm
S	1900 m	0 cm	100 cm	150 cm

Zona sur		Espesor nieve		
Manto Nival		1500m	2000m	2500m
N	1600 m	0 cm	120 cm	150 cm
S	1900 m	0 cm	60 cm	100 cm

BUTLLETÍ DEL PERILL D'ALLAUS DEL PRINCIPAT D'ANDORRA

Servei meteorològic nacional
Principat d'Andorra

Información detallada por espacios naturales protegidos

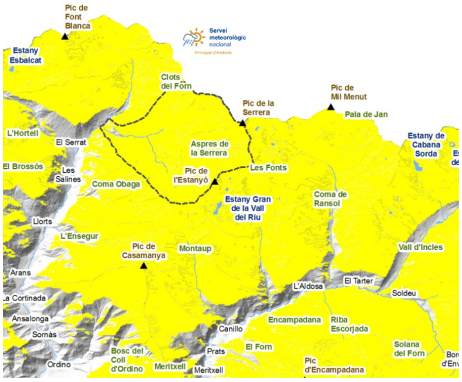

SORTENY

El rehielo de primeras horas aportará buenas condiciones para circular por la montaña, manteniendo la cautela en las laderas norte y este donde pueden existir capas débiles persistentes. En el transcurso de la jornada y con la penetración de la humedad, volveremos a tener nieve blanda y húmeda por debajo de 2.200 metros.

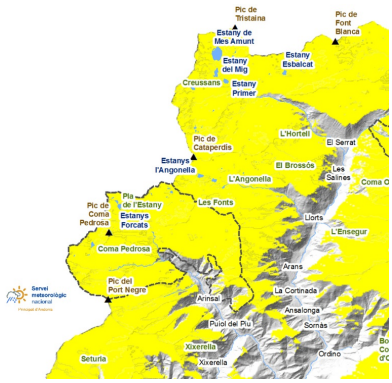

COMAPEDROSA

Como en todo el país, deberemos prestar atención a los problemas de nieve húmeda en las vertientes soleadas más inclinadas ya los pies de paredes rocosas. Esperamos actividad de aludes de fondo con las grietas abiertas. En las vertientes norte y este encontramos capas débiles todavía solicitables, con las que deberemos prestar atención.

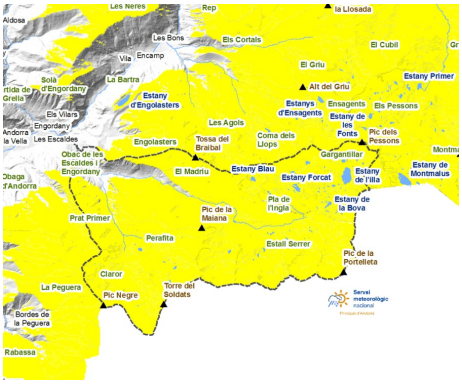

MADRIU-PERAFITA-CLAROR

Con la precipitación y humedad del jueves la nieve ha sufrido un retroceso importante en cotas bajas, aunque hay nieve suficiente para realizar numerosas rutas. Deberemos tener en cuenta que, en cotas medias, encontraremos nieve dura y rehelada a primeras horas pero que se ablandará con la presencia del sol, y ser cautelosos en las laderas con problemas de capas débiles persistentes.

Govern d'Andorra

EAWS
EUROPEAN AVALANCHE WARNING SERVICES

Aquest butlletí ha estat elaborat seguint les normes i recomanacions de l'**European Avalanche Warning Services**, del qual el **Servei meteorològic Nacional** n'és membre

BUTLLETÍ DEL PERILL D'ALLAUS DEL PRINCIPAT D'ANDORRA

Servei meteorològic nacional
Principat d'Andorra

Espesores de nieve nueva de los últimos días (de las ultimas 24h mesurado a las 06:00h UTC)

	16/03/2026	17/03/2026	18/03/2026	19/03/2026
FEDA (Central)	0 cm	0 cm	0 cm	0 cm
Engolasters - FEDA	0 cm	0 cm	0 cm	0 cm
Bony de les Neres	0 cm	0 cm	0 cm	0 cm
Sorteny	0 cm	0 cm	0 cm	0 cm
Les Fonts d'Arinsal	0 cm	0 cm	0 cm	0 cm
Perafita	0 cm	0 cm	0 cm	0 cm
Tossa Espiolets	0 cm	0 cm	0 cm	0 cm
Grau Roig - FEDA	0 cm	0 cm	1 cm	0 cm
Fontverd	0 cm	0 cm	0 cm	0 cm
Ransol - FEDA	0 cm	0 cm	0 cm	0 cm
Caborreu	0 cm	0 cm	0 cm	0 cm
La Solana	0 cm	0 cm	0 cm	0 cm
Coll Pa	0 cm	0 cm	3 cm	0 cm
Envalira Antenes	0 cm	0 cm	0 cm	0 cm
Vall del Riu FEDA	0 cm	0 cm	2 cm	0 cm