BUTLLETÍ DEL PERILL D'ALLAUS DEL PRINCIPAT D'ANDORRA

Préparé le 20/03/2026 16:00
Prochaine mise à jour le 21/03/2026 à 16h

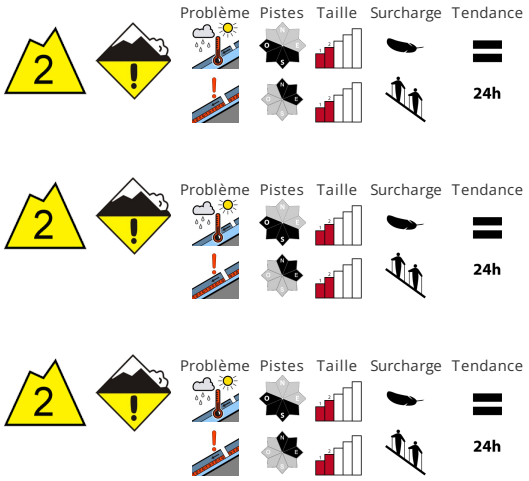

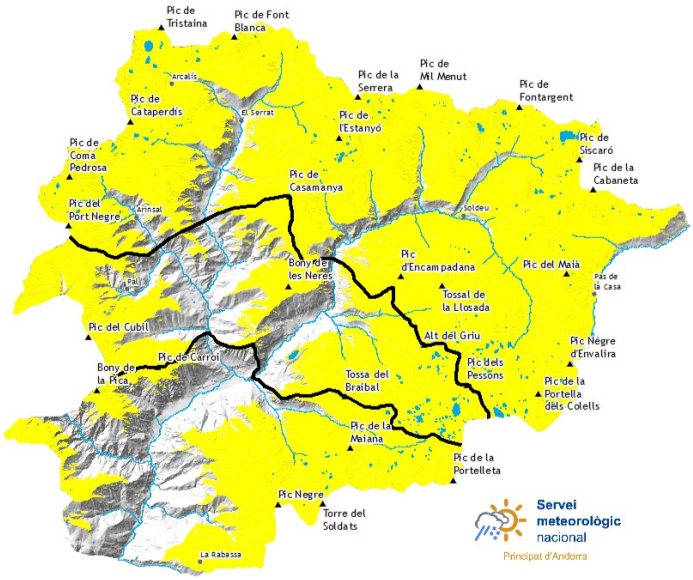

STABILITÉ DU MANTEAU NEIGEUX

Des avalanches petites et moyennes humides sont ils sont à attendre avec le réchauffement diurne et le rayonnement solaire. Ceci surtout sur les pentes raides ensoleillées et à l'extrême sud d'Andorra. , prudence au pied des parois rocheuses et à l'extrême sud d'Andorra. En outre en cours de journée , quelques avalanches de glissement sont possibles. Aussi à haute altitude (-):. Dans la partie supérieure du manteau neigeux des couches fragiles isolées susceptibles d'être déclenchées sont présentes ils se rencontrent , surtout sur les pentes raides exposées au nord et à l'est. Celles-ci peuvent peut être déchaîné surtout avec une surcharge importante et atteindre une taille moyenne.. Les endroits dangereux se situent dans la zone de la limite de la forêt ainsi qu'aux transitions entre les endroits faiblement et fortement enneigés. A côté du danger d'ensevelissement, il faut surtout penser au danger d'être emporté et de chuter..

QUALITÈ DE LA NEIGE

À basses et moyennes altitudes (-):. La surface de la neige regèle et devient porteuse et se ramollit dès la matinée.. Sur la surface de neige dure il existe en terrain raide un risque de chute.. À proximité des crêtes on trouve suivant l'influence du vent des hauteurs de neiges très différentes. Des couches fragiles en partie supérieure du manteau neigeux demandent de la prudence.. Des distances de délestage sont recommandées..

EPAISSEUR DE NEIGE HORS PISTE

Zone nord		Epaisseur de neige		
Nival manteau		1500m	2000m	2500m
N	1600 m	0 cm	150 cm	200 cm
S	1900 m	0 cm	100 cm	150 cm

Zone centre		Epaisseur de neige		
Nival manteau		1500m	2000m	2500m
N	1600 m	0 cm	150 cm	200 cm
S	1900 m	0 cm	100 cm	150 cm

Zone sud		Epaisseur de neige		
Nival manteau		1500m	2000m	2500m
N	1600 m	0 cm	120 cm	150 cm
S	1900 m	0 cm	60 cm	100 cm

Govern d'Andorra

EAWS EUROPEAN AVALANCHE WARNING SERVICES

Aquest butlletí ha estat elaborat seguint les normes i recomanacions de l'**European Avalanche Warning Services**, del qual el **Servei meteorològic Nacional** n'és membre

BUTLLETÍ DEL PERILL D'ALLAUS DEL PRINCIPAT D'ANDORRA

Servei meteorològic nacional
Principat d'Andorra

Des informations détaillées par espace naturel protégé

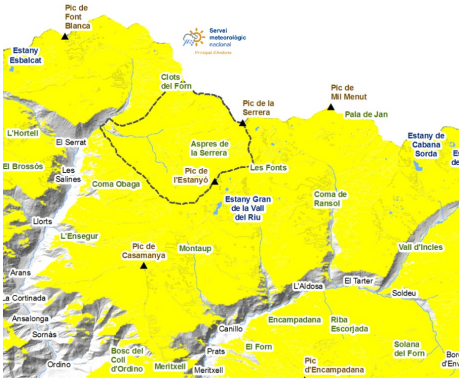

SORTENY

Le gel des premières heures offrira de bonnes conditions pour circuler en montagne, en maintenant la prudence sur les versants nord et est où des couches fragiles peuvent persister. Au cours de la journée et avec la pénétration de l'humidité, nous aurons à nouveau de la neige molle et mouillée en dessous de 2 200 mètres. , , ,

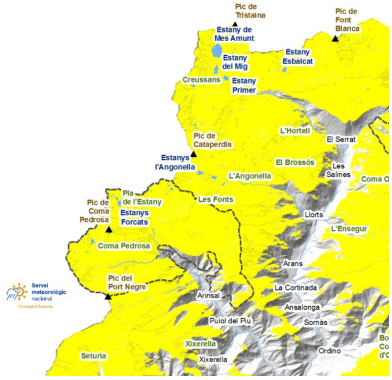

COMAPEDROSA

Comme pour l'ensemble du pays, il faudra faire attention aux problèmes de neige mouillée sur les pentes ensoleillées les plus raides et au pied des parois rocheuses. Nous nous attendons à une activité avalancheuse en arrière-plan avec les fissures ouvertes. Sur les versants nord et est, nous trouvons des couches faibles encore applicables, auxquelles nous devrons faire attention. , , , , ,

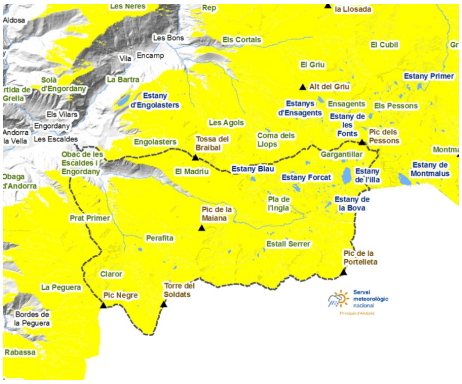

MADRIU-PERAFITA-CLAROR

Avec les précipitations et l'humidité de jeudi, la neige a subi un recul important à basse altitude, bien qu'il y ait suffisamment de neige pour parcourir de nombreux itinéraires. Il faudra tenir compte du fait qu'à moyenne altitude, on trouvera de la neige dure et gelée au petit matin mais qui se ramollira avec la présence du soleil, et être prudent sur les pentes avec des problèmes de couches fragiles persistantes. , , ,

Govern d'Andorra

EAWS
EUROPEAN AVALANCHE WARNING SERVICES

Aquest butlletí ha estat elaborat seguint les normes i recomanacions de l'**European Avalanche Warning Services**, del qual el **Servei meteorològic Nacional** n'és membre

BUTLLETÍ DEL PERILL D'ALLAUS DEL PRINCIPAT D'ANDORRA

Servei meteorològic nacional
Principat d'Andorra

Couche de neige fraiche des derniers jours (De 24 h mesurée à 06:00 h UTC)

	16/03/2026	17/03/2026	18/03/2026	19/03/2026
FEDA (Central)	0 cm	0 cm	0 cm	0 cm
Engolasters - FEDA	0 cm	0 cm	0 cm	0 cm
Bony de les Neres	0 cm	0 cm	0 cm	0 cm
Sorteny	0 cm	0 cm	0 cm	0 cm
Les Fonts d'Arinsal	0 cm	0 cm	0 cm	0 cm
Perafita	0 cm	0 cm	0 cm	0 cm
Tossa Espiolets	0 cm	0 cm	0 cm	0 cm
Grau Roig - FEDA	0 cm	0 cm	1 cm	0 cm
Fontverd	0 cm	0 cm	0 cm	0 cm
Ransol - FEDA	0 cm	0 cm	0 cm	0 cm
Caborreu	0 cm	0 cm	0 cm	0 cm
La Solana	0 cm	0 cm	0 cm	0 cm
Coll Pa	0 cm	0 cm	3 cm	0 cm
Envalira Antenes	0 cm	0 cm	0 cm	0 cm
Vall del Riu FEDA	0 cm	0 cm	2 cm	0 cm