MINISTERO DELLA DIFESA

meteomont Servizio Nazionale di previsione neve e valanghe

EAWS EUROPEAN AVALANCHE WARNING SERVICES

CARABINIERI

# APPENNINO LUCANO

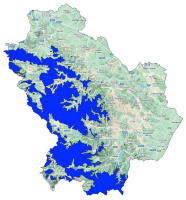

Bollettino Valanghe N. 277/2026 del 20/03/2026 ore 14.00
Validità 48 ore prossima emissione 21/03/2026

**A cura del Servizio METEOMONT dell'ARMA dei CARABINIERI**
**In collaborazione con Servizio Meteorologico dell'Aeronautica militare**

## SITUAZIONE alle 14:00 del 20/03/2026

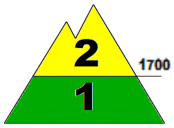


**SITUAZIONE TIPO: neve a debole coesione e vento.**




**SITUAZIONE TIPO: pioggia su neve.**

| | Nord | Sud |
|---|---|---|
| *Quota neve (mslm)* | *1300 - 1400* | *1300 - 1500* |

| | Neve al suolo | Neve Fresca | Quota (mslm) |
|---|---|---|---|
| *Altezza Neve (cm)* | *160* | *002* | *1800* |
| | *021* | *008* | *1560* |

**VALANGHE OSSERVATE: Nessuna valanga.**

## PREVISIONI 21/03/2026

## GRADO DI PERICOLO: MODERATO 2

## SITUAZIONE TIPO: neve a debole coesione e vento.

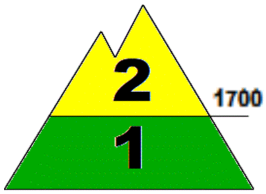





## SITUAZIONE TIPO: pioggia su neve.

**MANTO NEVOSO: La stabilità del manto nevoso è scarsa su alcuni punti (aree) per tutte le esposizioni al di sopra di 1700 mslm, possibili valanghe di dimensioni medie.**
**La stabilità del manto nevoso è discreta su molti punti (aree) per tutte le esposizioni al di sotto di 1700 mslm, possibili valanghe di dimensioni piccole.**

## AVVERTENZE

In considerazione dei recenti apporti di neve fresca, è richiesta una buona valutazione locale della stabilità ed individuazione dell'itinerario.

## SCALA EUROPEA DEL GRADO DI PERICOLO VALANGHE

## LEGENDA PROBLEMA

**Bollettino realizzato su scala sinottica-regionale (standard EAWS). La sua valutazione non può escludere in alcun modo la necessità di una seria e capace valutazione locale del pericolo (singolo pendio) che può essere anche sensibilmente diverso. Le previsioni meteorologiche sono relative all'orario UTC (per l'Italia +1 in inverno e +2 in estate).**

# APPENNINO LUCANO

## PREVISIONE METEO

| Quota | | 21/03/2026 h6:00 | 21/03/2026 h12:00 | 21/03/2026 h18:00 |
|---|---|---|---|---|
| 1000 | Venti | 02 Nodi da N-Est | 03 Nodi da S-Ovest | 01 Nodi da Nord |
| | Temperature | +04 °C | +06 °C | +06 °C |
| | Temp.percepita | 4 °C | 5 °C | 6 °C |
| 2000 | Venti | 04 Nodi da Nord | 04 nodi da N-Ovest | 02 Nodi da Est |
| | Temperature | -02 °C | -03 °C | -03 °C |
| | Temp.percepita | -5 °C | -6 °C | -3 °C |
| 3000 | Venti | 10 Nodi da Nord | 07 Nodi da Nord | 03 nodi da N-Ovest |
| | Temperature | -09 °C | -08 °C | -09 °C |
| | Temp.percepita | -16 °C | -14 °C | -12 °C |
| Zero termico | | 0900-1100 m. | 1500-1700 m. | 1400-1600 m. |
| Fenomeno | | — | — | — |
| Stato del cielo | | | | |

## LEGENDA FENOMENI

— Assenza Fenomeni · Nebbia · Foschia · Pioggia debole · Pioggia moderata · Pioggia forte · Temporali

Nevicata debole · Nevicata moderata · Nevicata forte

## STATO DEL CIELO

Sereno · Poco nuvoloso · Nuvoloso · Molto nuvoloso · Coperto

## Parametri meteonivometrici registrati presso i campi di rilevamento il 20/03/2026.

| Località | Comune | Quota (m.s.l.m.) | Altezza neve (cm) | Neve caduta nelle 24 ore (cm) | Temp. Min (°C) | Temp. Max (°C) | Condizioni del tempo |
|---|---|---|---|---|---|---|---|
| LAUDEMIO | Lagonegro (PZ) | 1532 | 12 | 0 | 0 | +1 | Assenza di precipitazioni |
| PIANO IMPERATORE | Marsicovetere (PZ) | 1560 | 21 | 8 | 0 | +3 | Assenza di precipitazioni |
| PEDARRETO | Rotonda (PZ) | 1380 | 8 | 0 | N.P. | N.P. | Assenza di precipitazioni |

**(*) Rilievi fuori campo**

**L'INFORMAZIONE E' PREVENZIONE - LEGGI L'ATTUALE GRADO DI PERICOLO VALANGHE!**

**IL CAPO DEL CENTRO NAZIONALE METEOMONT**
**(Ten. Col. RFI Emanuela Gini)**
**FIRMA AUTOGRAFA OMESSA AI SENSI**
**DELL'ART.3 DEL D.LGS N.39/1993**

**Bollettino realizzato su scala sinottica-regionale (standard EAWS). La sua valutazione non può escludere in alcun modo la necessità di una seria e capace valutazione locale del pericolo (singolo pendio) che può essere anche sensibilmente diverso. Le previsioni meteorologiche sono relative all'orario UTC (per l'Italia +1 in inverno e +2 in estate).**