Bulletin d'estimation du risque d'avalanche

(valable en dehors des pistes balisées et ouvertes)

MASSIF : Cinto Rotondo

Rédigé le vendredi 20 mars 2026 à 15h

Estimation des risques pour le : SAMEDI 21 MARS

INSTABILITÉS EN ALTITUDE DANS LA NEIGE RECENTE VENTÉE.

2

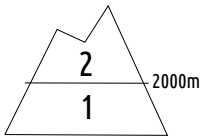

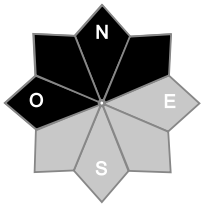

Au-dessus de 2000m indice de risque limité, plus bas indice faible.

Départs spontanés : Peu probable

Déclenchements provoqués : Plaques à vent difficilement sollicitables en altitude au-dessus de 2000 m.

Indices de risque : 5 très fort - 4 fort - 3 marqué - 2 limité - 1 faible -- En noir : les pentes les plus dangereuses

Stabilité du manteau neigeux

Situation avalancheuse typique : neige ventée

Déclenchements provoqués : de rares plaques sont encore en place suite aux récentes chutes de neige et au transport engendré par le vent de nord à nord-est. Elles sont en cours de tassement dans les versants ensoleillés mais restent plus fréquentes dans les versants ne voyant que peu le soleil au dessus de 2000 m environ, là où le manteau neigeux n'est pas encore printanier. Elles deviennent progressivement difficiles à déclencher, mais peuvent encore céder au passage d'un skieur dans les pentes raides allant du Nord-Ouest vers le Nord-Est et sont parfois cachées sous une fine couche de fraîche des averses de mercredi. Elles peuvent engendrer des avalanches de taille petite à moyenne (taille 1 à 2)..

En dessous de 2000 m, la neige fraîche repose sur une sous-couche regelée et plus stable.

Départs spontanés : peu probable, ou rares avalanches de neige humide au fil de la course du soleil sous 1800 m. Taille 1

Autres : Nombreuses des surfaces dures et glacées.

Qualité de la neige

Qualification de l'enneigement : L'enneigement est excellent pour la saison au-dessus de 1600 m. Sur la Maniccia, à 2400 m d'altitude dans le massif du Rotondo, on relève 3m20 de hauteur de neige totale.

Limite d'enneigement skiable : 1500 m.

État de la neige : La neige s'humidifie en surface dans les pentes SE à SO bien exposées au soleil, surtout en-dessous de 2000m. Plus haut, et en pentes plus froides NE à NO, elle reste plus froide et assez légère, ou bien densifiée ou durcie sur les zones qui ont été exposées au Grecale. Le net refroidissement permet une consolidation par regel des couches de neige humide. Des croûtes épaisses et des surfaces dures sont généralisées. À noter également la présence de corniches parfois volumineuses.

Aperçu météo pour le samedi 21 mars

	nuit	matin	après-midi	soir
Pluie-Neige				
Iso 0 °C	2 100 m	2 100 m	2 000 m	1 800 m
Vent 1500 m	15 km/h	15 km/h	15 km/h	10 km/h
Vent 3000 m	30 km/h	20 km/h	20 km/h	20 km/h

Épaisseur de neige hors-piste

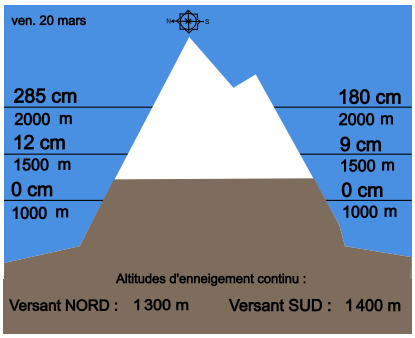

Précipitations à 1800 m

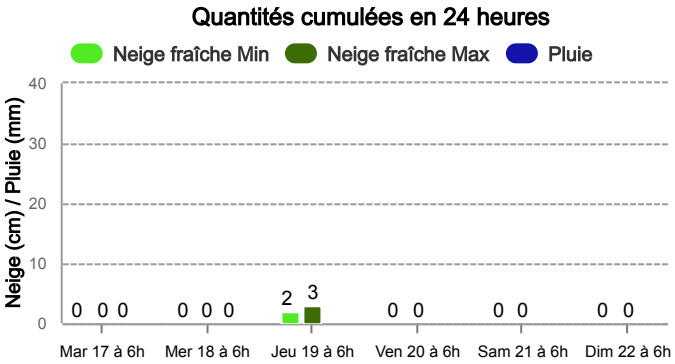

Tendance du dimanche 22 mars

2

Indice de risque limité

Avec des températures froides, persistance de plaques localement sensibles en versants ombragés.

Pour consulter la vigilance en cours, veuillez vous rendre sur le site https://vigilance.meteofrance.fr/fr

Météo-France - 73 avenue de Paris, 94165 Saint-Mandé cedex - Contact : contact@meteo.fr

Rédigé par Météo-France avec la contribution des observateurs du réseau nivo-météorologiques. Partenariat : ANMSM (Maires de Stations de Montagne), DSF (Domaines Skiables de France), ADSP (Directeurs de Pistes et de la Sécurité des Stations de Sports d'Hiver) et autres acteurs de la montagne.

Bulletin neige & avalanches par téléphone au 0 892 68 10 20 Service 0,35 € / min + prix appel

RÉPUBLIQUE FRANÇAISE
Liberté Égalité Fraternité

METEO FRANCE
À VOS CÔTÉS, DANS UN CLIMAT QUI CHANGE

Bulletin d'estimation du risque d'avalanche

(valable en dehors des pistes balisées et ouvertes)

MASSIF : Cinto Rotondo

Rédigé le vendredi 20 mars 2026 à 15h

Conditions nivo-météo des 7 derniers jours

	sam. 14/03				dim. 15/03				lun. 16/03				mar. 17/03				mer. 18/03				jeu. 19/03				ven. 20/03			
	03h	09h	15h	21h	03h	09h	15h	21h	03h	09h	15h	21h	03h	09h	15h	21h	03h	09h	15h	21h	03h	09h	15h	21h	03h	09h	15h	21h
Météo																												
Vent (km/h)	10	30	65	45	45	45	60	60	40	45	30	50	50	45	35	40	45	40	40	55	45	25	50	80	60	40	30	30
à 3000m																												
Vent (km/h)	10	25	50	35	35	35	50	30	35	20	10	10	5	10	5	10	10	30	20	25	40	35	20	30	30	30	20	20
à 1500m																												

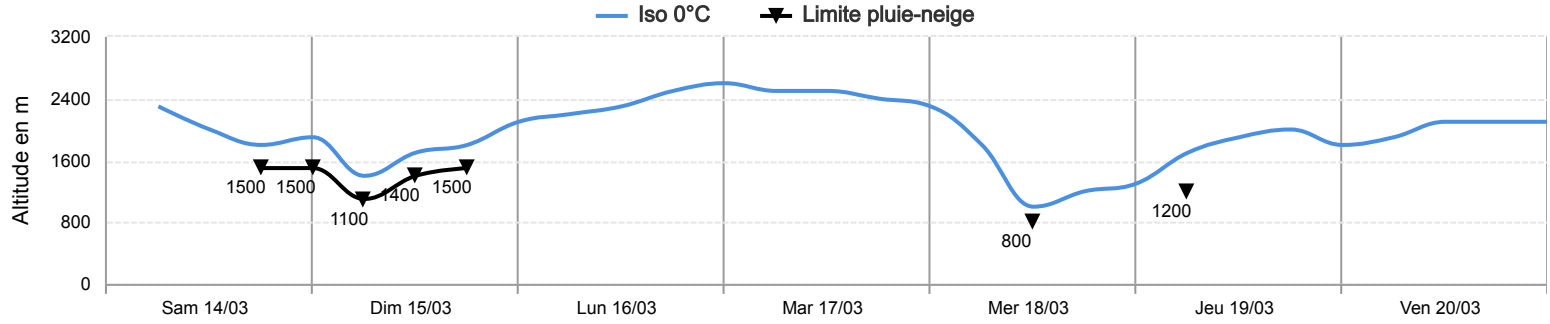

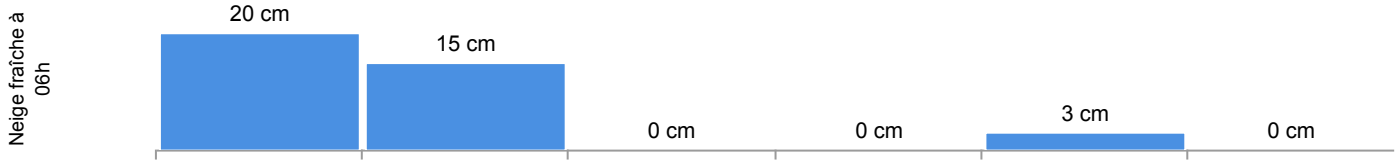

Risque d'avalanche	sam. 14/03	dim. 15/03	lun. 16/03	mar. 17/03	mer. 18/03	jeu. 19/03	ven. 20/03
	2	2	3	2	2	2	2

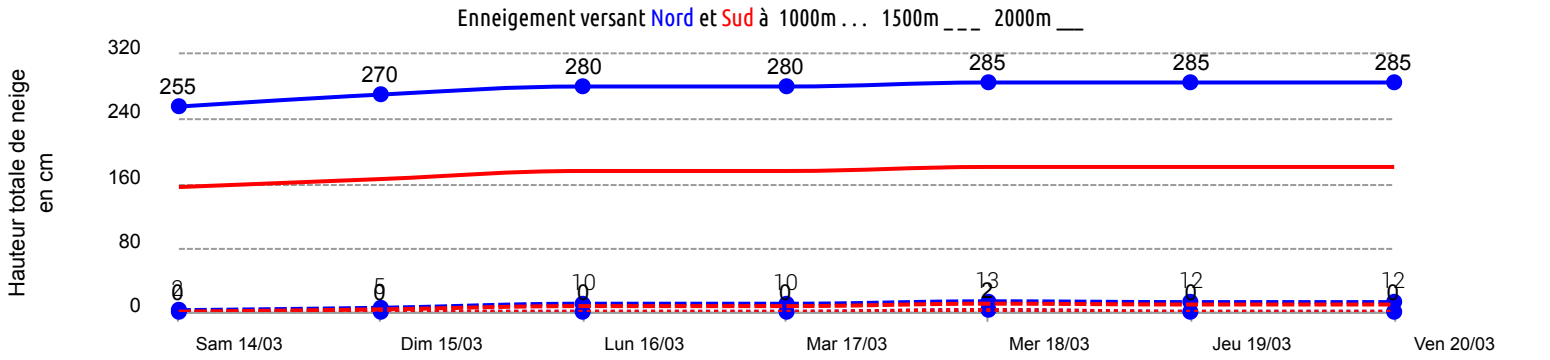

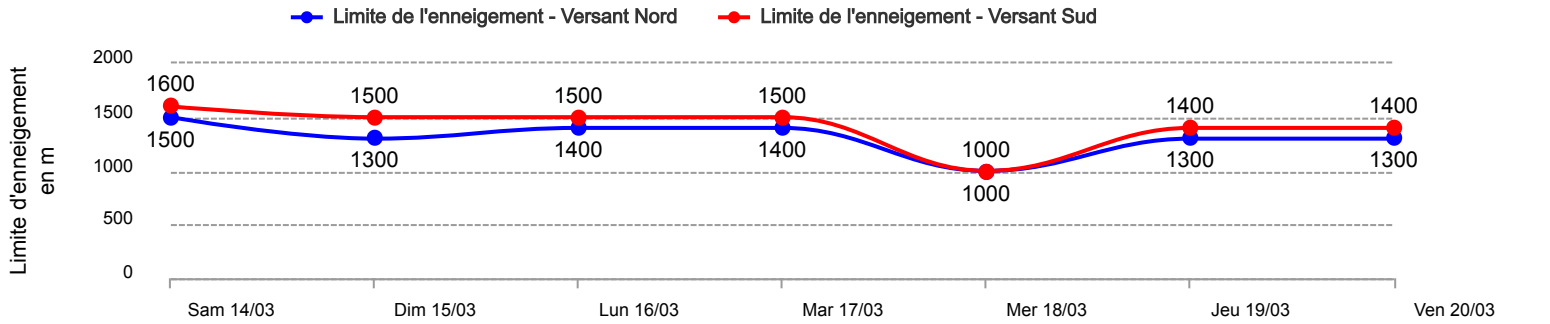

Pour consulter la vigilance en cours, veuillez vous rendre sur le site https://vigilance.meteofrance.fr/fr

Météo-France - 73 avenue de Paris, 94165 Saint-Mandé cedex - Contact : contact@meteo.fr

Rédigé par Météo-France avec la contribution des observateurs du réseau nivo-météorologiques. Partenariat : ANMSM (Maires de Stations de Montagne), DSF (Domaines Skiables de France), ADSP (Directeurs de Pistes et de la Sécurité des Stations de Sports d'Hiver) et autres acteurs de la montagne.

Bulletin neige & avalanches par téléphone au
0 892 68 10 20 Service 0,35 € / min + prix appel