Bulletin d'estimation du risque d'avalanche
(valable en dehors des pistes balisées et ouvertes)

MASSIF : Devoluy

Rédigé le vendredi 20 mars 2026 à 15h

Estimation des risques pour le : SAMEDI 21 MARS

RARES INSTABILITÉS EN UBACS D'ALTITUDE

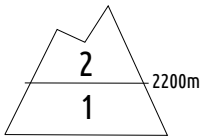

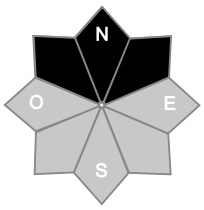

Au-dessus de 2200m indice de risque limité, plus bas indice faible.

Départs spontanés : rares et peu volumineux au soleil

Déclenchements provoqués : possibles dans la neige ventée en versants nord d'altitude

Indices de risque : 5 très fort - 4 fort - 3 marqué - 2 limité - 1 faible -- En noir : les pentes les plus dangereuses

Stabilité du manteau neigeux

Situation avalancheuse typique : neige ventée

Déclenchements provoqués : le manteau neigeux est plutôt bien stabilisé. Les instabilités sont plutôt rares, et localisées en orientations nord-ouest, nord et nord-est d'altitude supérieure à 2200 m environ, plutôt à proximité des crêtes et ruptures de pente. Elles peuvent être déclenchées par un seul skieur et générer des avalanches de taille petite à moyenne (taille 1 à 2). Ces instabilités se présentent sous la forme de plaques de neige ventée, encore parfois d'aspect poudreux. Elles se sont formées lors du transport de neige ventée en début de semaine, mais sont en cours de stabilisation avec le temps calme et ensoleillé.

Départs spontanés : rares et peu volumineux en neige humide. Départs ponctuels, près des rochers. Taille 1.

Qualité de la neige

L'enneigement est excédentaire pour une fin mars.

Limite d'enneigement skiable : vers 1300 m en ubacs, 1700/1800 m en adrets pas trop raides.

État de la neige de surface : neige de printemps en versants ensoleillés avec un très bon regel nocturne. En large versant nord au-dessus de 2200/2300 m, neige restée sèche, travaillée par le vent ou encore d'aspect poudreux.

Aperçu météo pour le samedi 21 mars

	nuit	matin	après-midi	soir
Très bon regel nocturne. Ensoleillé le matin, cumulus l'après-midi. Vent faible				
Pluie-Neige				
Iso 0 °C	2 200 m	2 100 m	2 100 m	2 000 m
Vent 2000 m	5 km/h	10 km/h	20 km/h	15 km/h
Vent 3000 m	15 km/h	25 km/h	25 km/h	25 km/h

Épaisseur de neige hors-piste

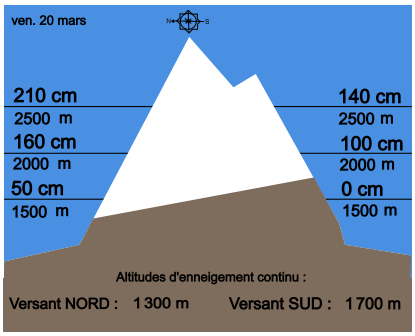

Précipitations à 1800 m

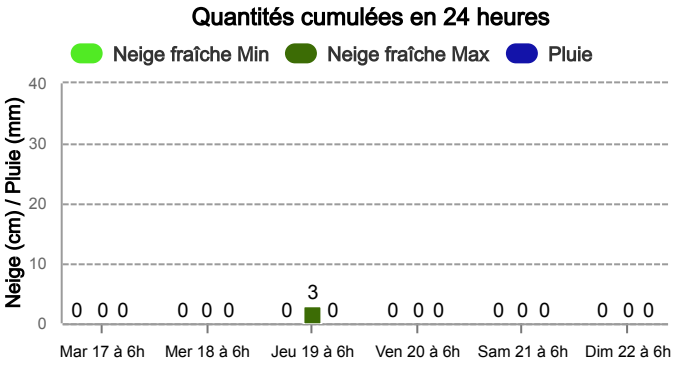

Tendance du dimanche 22 mars

Indice de risque limité

Risque en légère hausse. Neige en faible quantité, tombant froide et peu ventée en altitude, limitant le nombre de nouvelles instabilités. Risque restant limité dimanche.

Pour consulter la vigilance en cours, veuillez vous rendre sur le site https://vigilance.meteofrance.fr/fr

Météo-France - 73 avenue de Paris, 94165 Saint-Mandé cedex - Contact : contact@meteo.fr

Rédigé par Météo-France avec la contribution des observateurs du réseau nivo-météorologiques. Partenariat : ANMSM (Maires de Stations de Montagne), DSF (Domaines Skiables de France), ADSP (Directeurs de Pistes et de la Sécurité des Stations de Sports d'Hiver) et autres acteurs de la montagne.

Bulletin neige & avalanches par téléphone au

0 892 68 10 20 Service 0,35 € / min + prix appel

RÉPUBLIQUE FRANÇAISE
Liberté Égalité Fraternité

METEO FRANCE
À VOS CÔTÉS, DANS UN CLIMAT QUI CHANGE

Bulletin d'estimation du risque d'avalanche

(valable en dehors des pistes balisées et ouvertes)

MASSIF : Devoluy

Rédigé le vendredi 20 mars 2026 à 15h

Conditions nivo-météo des 7 derniers jours

	sam. 14/03				dim. 15/03				lun. 16/03				mar. 17/03				mer. 18/03				jeu. 19/03				ven. 20/03			
	03h	09h	15h	21h	03h	09h	15h	21h	03h	09h	15h	21h	03h	09h	15h	21h	03h	09h	15h	21h	03h	09h	15h	21h	03h	09h	15h	21h
Météo																												
Vent (km/h)	70	5	20	35	30	30	20	5	20	50	60	35	30	25	30	35	35	40	70	70	55	50	30	15	20	20	15	10
à 3000m	↗	↘	↓	↓	↙	←	←	→	↓	↓	↓	↓	↓	↓	↓	↓	↓	↓	↙	←	↖	←	↙	↙	↙	↙	↓	↓
Vent (km/h)	30	10	30	70	90	60	20	30	40	50	50	40	20	10	10	10	10	15	25	20	30	10	15	10	5	5	15	10
à 2000m	↑	↗	↓	↓	↓	↓	↻	↓	↓	↓	↘	↓	↓	↓	↓	↓	↓	↑	←	←	←	←	↓	↓	↙	↗	→	↓

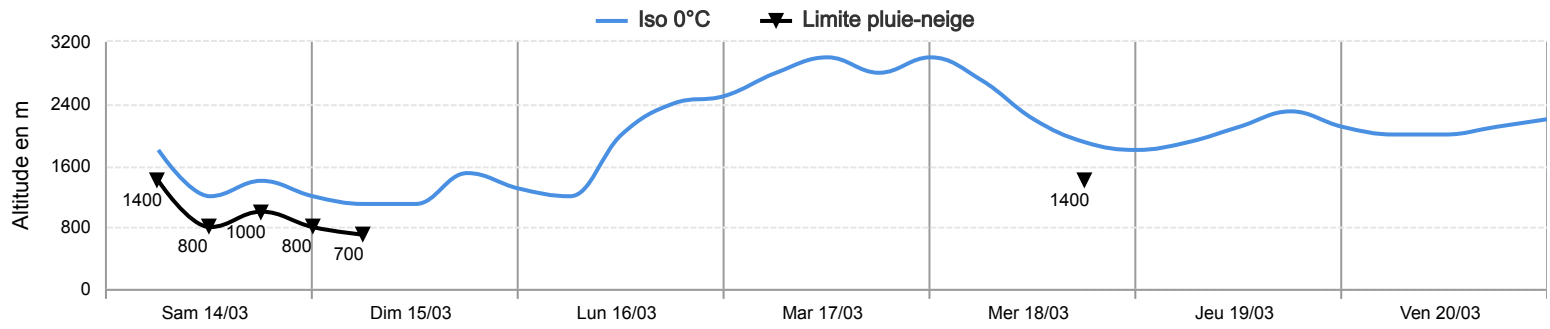

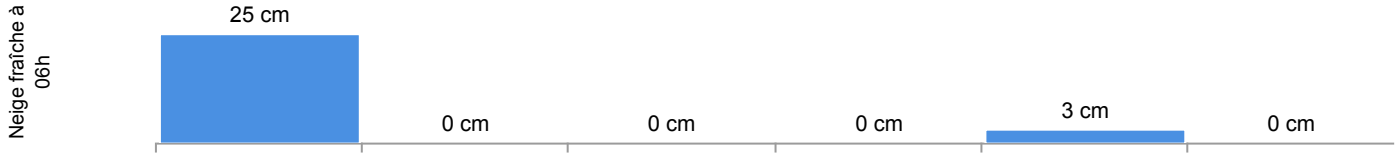

Risque d'avalanche	sam. 14/03	dim. 15/03	lun. 16/03	mar. 17/03	mer. 18/03	jeu. 19/03	ven. 20/03
	3	3	3	3	2	2	2

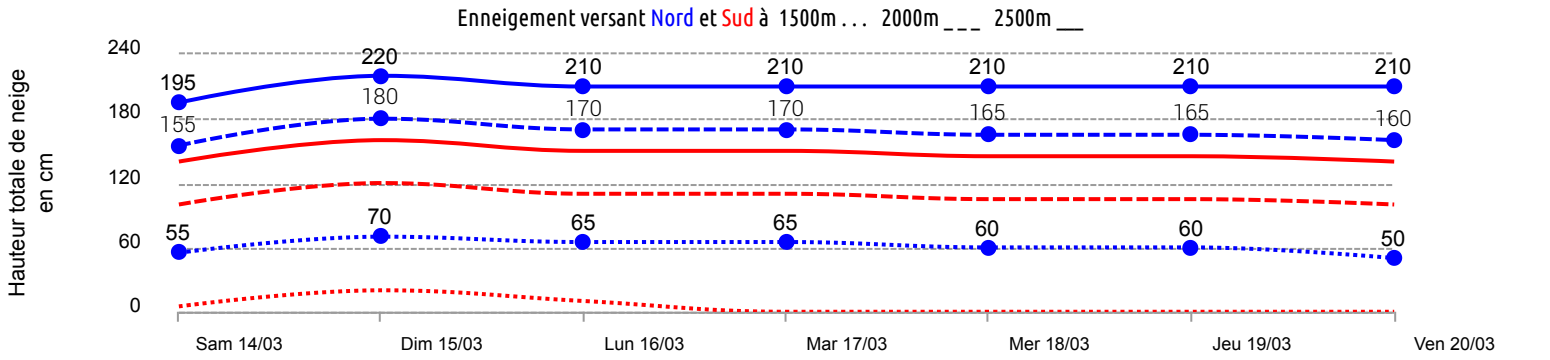

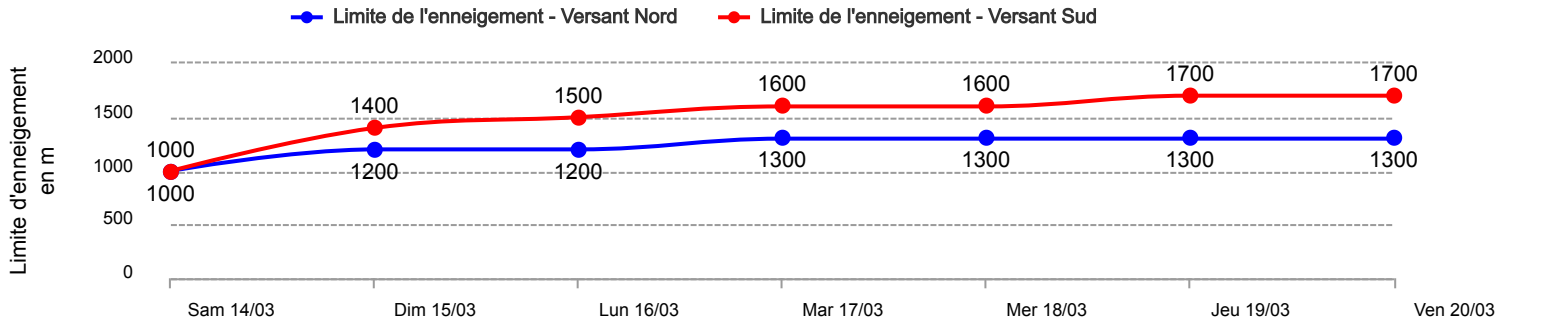

Pour consulter la vigilance en cours, veuillez vous rendre sur le site https://vigilance.meteofrance.fr/fr

Météo-France - 73 avenue de Paris, 94165 Saint-Mandé cedex - Contact : contact@meteo.fr

Rédigé par Météo-France avec la contribution des observateurs du réseau nivo-météorologiques. Partenariat : ANMSM (Maires de Stations de Montagne), DSF (Domaines Skiables de France), ADSP (Directeurs de Pistes et de la Sécurité des Stations de Sports d'Hiver) et autres acteurs de la montagne.

Bulletin neige & avalanches par téléphone au
0 892 68 10 20 Service 0,35 € / min + prix appel