Bulletin d'estimation du risque d'avalanche

(valable en dehors des pistes balisées et ouvertes)

MASSIF : Aure Louron

Rédigé le vendredi 20 mars 2026 à 16h

Estimation des risques pour le : SAMEDI 21 MARS

PLAQUES PRÉSENTES EN NORD AU-DESSUS DE 2200 M, HUMIDIFICATION AILLEURS.

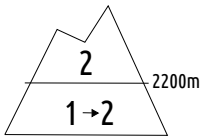

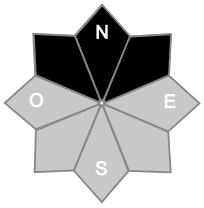

Au-dessus de 2200m indice de risque limité, plus bas indice faible évoluant en limité.

Départs spontanés : En neige humide, avalanches de fond possibles.

Déclenchements provoqués : Des plaques parfois sensibles au-dessus de 2200 m en Nord à NE.

Indices de risque : 5 très fort - 4 fort - 3 marqué - 2 limité - 1 faible -- En noir : les pentes les plus dangereuses

Stabilité du manteau neigeux

Situation avalancheuse typique : neige ventée neige humide

Déclenchements provoqués :
Observation : Plaque de 50 cm déclenchée ce jeudi par skieurs sur le massif voisin du Néouvielle.
- **Au-dessus de 2200 m**, dans les **pentes raides allant du Nord-Ouest vers le Nord-Est**, des plaques à vent sont encore présentes. Elles restent **facilement déclenchables** par un simple skieur et initient alors des **cassures linéaires petites à moyennes** (jusqu'à 30-50 cm, pouvant ensevelir un skieur), plus **rarement de grandes** (taille 3, cassure de 50 cm à 1 m, avalanche descendant jusqu'au bas de la pente) surtout dans les zones d'accumulation les plus importantes. Manteau supérieur avec feuilletage de plaques multiples sur les 30 à 40 premiers centimètres avec des couches fragiles persitantes en **grains anguleux**.
Neige humide chassant sous les skis au soleil.

Départs spontanés :
- Des départs ponctuels dans la neige humide sont attendus dans les pentes raides en toutes orientations et au fil de la journée. Un regel efficace cette nuit de jeudi à vendredi limitera cette activité avalancheuse tôt le matin. Les avalanches sont généralement petites à moyennes (taille 1 à 2) sous 2200 m, de grandes (taille 3) sont possibles au-dessus de 2000/2200 m surtout dans les combes ou zones d'accumulation plus conséquentes. Des avalanches de glissement (tout le manteau) sont probables dans les pentes raides au fil de la journée, engendrant des avalanches souvent moyennes à **parfois grandes** (taille 2 à taille 3).

Autres : Pont de neige et corniches encore en place.

Qualité de la neige

Enneigement : Correct pour la saison au-dessus de 1800 à 2000 m, mais reste assez maigre en versants exposés au vent d'ouest. Manteau skiable à partir de 1600 m en nord, plutôt 1900/2000 m en sud.
État de la neige : Au petit matin, la neige reste encore sèche au-dessus de 2200/2400 m dans les pentes Nord et éventuellement nord-Ouest à Nord-Est, assez travaillée par le vent précédemment. Ailleurs, elle est regelée la nuit et portante au petit jour. Neige rapidement lourde et ramollie en journée sous le soleil.

Aperçu météo pour le samedi 21 mars

	nuit	matin	après-midi	soir

Un soleil généreux et quelques nuages possibles d'évolution diurne en après-midi accrochant le relief. Vent faible à modéré.

Pluie-Neige				
Iso 0 °C	2 600 m	2 500 m	2 500 m	2 400 m
Vent 1500 m	↑ 5 km/h	↙ 5 km/h	↓ 10 km/h	↑ 5 km/h
Vent 3000 m	↙ 10 km/h	← 10 km/h	↓ 15 km/h	↘ 15 km/h

Épaisseur de neige hors-piste

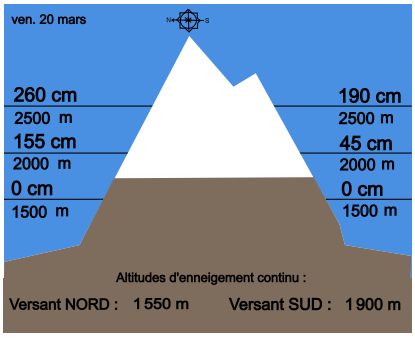

Précipitations à 1800 m

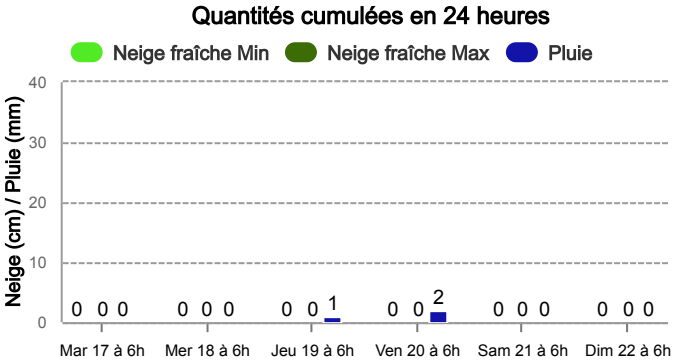

Tendance du dimanche 22 mars

Indice de risque limité

Maintien des risques.

Pour consulter la vigilance en cours, veuillez vous rendre sur le site https://vigilance.meteofrance.fr/fr

Météo-France - 73 avenue de Paris, 94165 Saint-Mandé cedex - Contact : contact@meteo.fr

Rédigé par Météo-France avec la contribution des observateurs du réseau nivo-météorologiques. Partenariat : ANMSM (Maires de Stations de Montagne), DSF (Domaines Skiables de France), ADSP (Directeurs de Pistes et de la Sécurité des Stations de Sports d'Hiver) et autres acteurs de la montagne.

Bulletin neige & avalanches par téléphone au **0 892 68 10 20** Service 0,35 € / min + prix appel

RÉPUBLIQUE FRANÇAISE
Liberté Égalité Fraternité

METEO FRANCE
À VOS CÔTÉS, DANS UN CLIMAT QUI CHANGE

Bulletin d'estimation du risque d'avalanche

(valable en dehors des pistes balisées et ouvertes)

MASSIF : Aure Louron

Rédigé le vendredi 20 mars 2026 à 16h

Conditions nivo-météo des 7 derniers jours

	sam. 14/03				dim. 15/03				lun. 16/03				mar. 17/03				mer. 18/03				jeu. 19/03				ven. 20/03			
	03h	09h	15h	21h	03h	09h	15h	21h	03h	09h	15h	21h	03h	09h	15h	21h	03h	09h	15h	21h	03h	09h	15h	21h	03h	09h	15h	21h
Météo																												
Vent (km/h)	55	60	80	95	95	85	75	55	65	65	40	30	25	20	15	15	15	10	15	25	30	25	20	20	25	25	20	15
à 3000m																												
Vent (km/h)	25	25	45	60	65	60	35	20	25	25	10	5	10	10	10	10	10	2	5	10	15	15	15	10	10	10	5	5
à 1500m																												

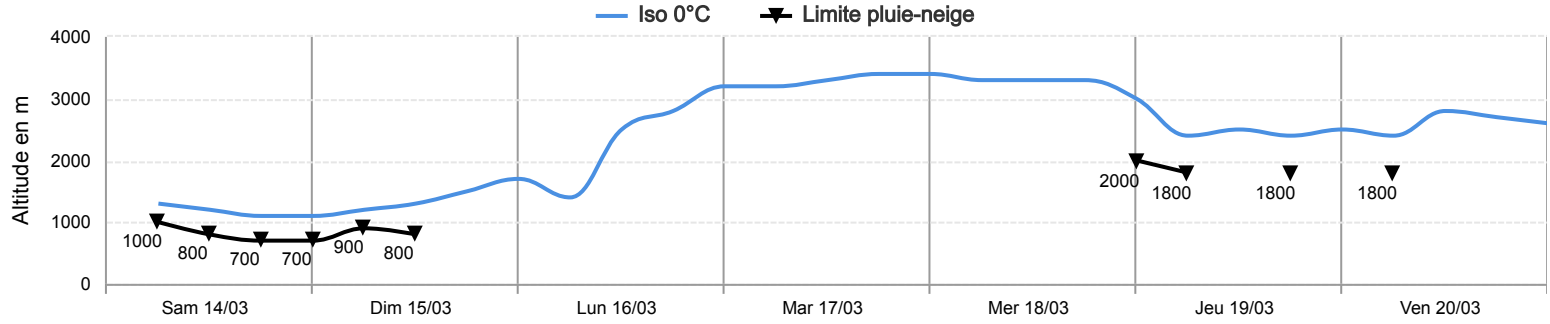

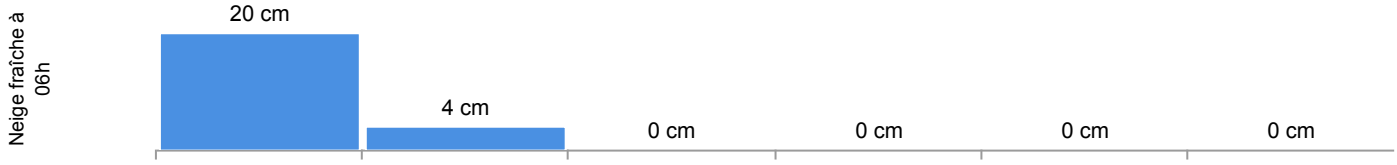

Risque d'avalanche	sam. 14/03	dim. 15/03	lun. 16/03	mar. 17/03	mer. 18/03	jeu. 19/03	ven. 20/03
	3	3	3	3	3	2	2

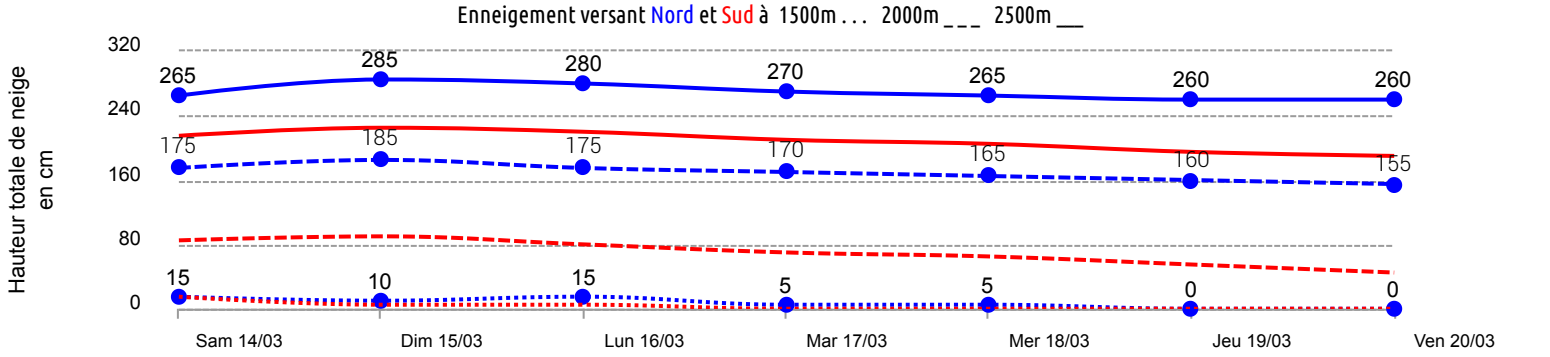

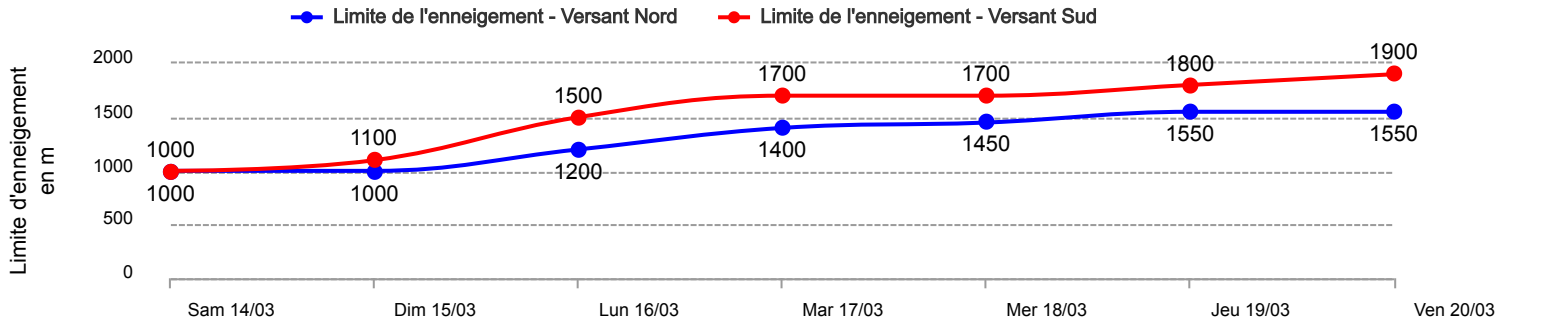

Pour consulter la vigilance en cours, veuillez vous rendre sur le site https://vigilance.meteofrance.fr/fr

Météo-France - 73 avenue de Paris, 94165 Saint-Mandé cedex - Contact : contact@meteo.fr

Rédigé par Météo-France avec la contribution des observateurs du réseau nivo-météorologiques. Partenariat : ANMSM (Maires de Stations de Montagne), DSF (Domaines Skiables de France), ADSP (Directeurs de Pistes et de la Sécurité des Stations de Sports d'Hiver) et autres acteurs de la montagne.

Bulletin neige & avalanches par téléphone au
0 892 68 10 20 Service 0,35 € / min + prix appel