Bulletin d'estimation du risque d'avalanche
(valable en dehors des pistes balisées et ouvertes)

MASSIF : Bauges

Rédigé le vendredi 20 mars 2026 à 16h

Estimation des risques pour le : SAMEDI 21 MARS

PETITES INSTABILITÉS SUR LES PLUS HAUTS SOMMETS.

1

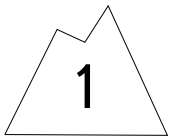

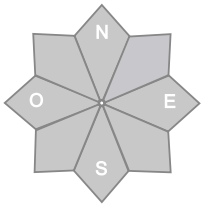

Indice de risque faible.

Départs spontanés : Avalanches de fond. Rares coulées humides.

Déclenchements provoqués : Rares plaques à vent en altitude.

Indices de risque : 5 très fort - 4 fort - 3 marqué - 2 limité - 1 faible -- En noir : les pentes les plus dangereuses

Stabilité du manteau neigeux

Situation avalancheuse typique : avalanches de fond neige ventée

Départs spontanés :
* Des plaques de fond sont toujours possibles, en tous versants, à toute heure du jour et de la nuit, dans les pentes lisses et raides (zones herbeuses, dalles, vires). Taille 2 (moyenne).
* Rares coulées en neige humide toujours possibles au fil de l'ensoleillement. Ces petites avalanches (taille 1) sont un peu plus probables au fil de la journée. Taille 1, rarement 2.

Déclenchements provoqués :
* **Rares plaques à vent**, dans la neige froide **au-dessus de 1800 m**. Elles sont plutôt d'aspect dur et **assez difficile à déclencher**. Elles ont été formées par le vent d'est de mercredi après-midi. Taille 1 à 2 (petite à moyenne).
Observables : accumulation de neige, vaguelettes, fissures sous les skis.
* un peu de neige humide peut couler sous les skis dans les versants ensoleillés aux heures les plus chaudes. Taille 1 (petite).

Qualité de la neige

Enneigement :
L'enneigement passe d'inexistant à relativement bon une fois la limite d'enneigement atteinte.
On peut chausser les skis vers 1200/1300 m en nord et 1400/1500 m en sud.
Grosses corniches présentes.

Qualité de la neige ce samedi :
* Dans les adrets (et les ubacs sous 1800 m), neige de printemps avec un bon regel nocturne. L'humidification est plus lente en nord.
* Dans les ubacs d'altitude, neige froide souvent travaillée par le vent. Dans les couloirs/secteurs encaissés, la neige est restée légère.

Aperçu météo pour le samedi 21 mars

	nuit	matin	après-midi	soir
Journée très ensoleillée. Quelques cumulus sur le relief en cours d'après-midi.				
Pluie-Neige				
Iso 0 °C	2 000 m	1 900 m	1 900 m	1 800 m
Vent 1500 m	↓ 5 km/h	↓ 5 km/h	↘ 15 km/h	↓ 10 km/h
Vent 2000 m	↙ 5 km/h	↓ 10 km/h	↓ 10 km/h	↓ 10 km/h

Épaisseur de neige hors-piste

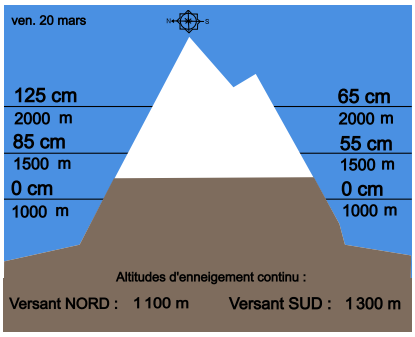

Précipitations à 1800 m

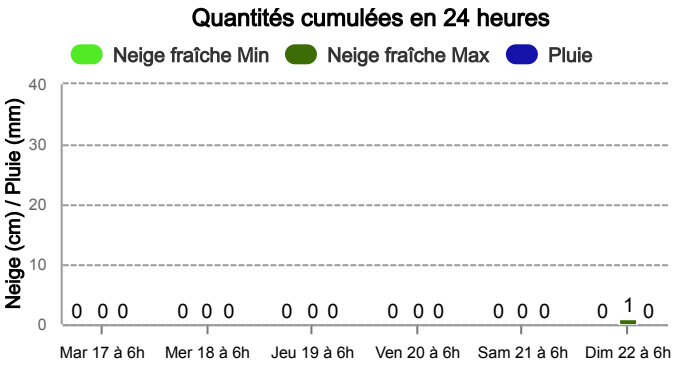

Tendance du dimanche 22 mars

1

Indice de risque faible

Dimanche, faibles chutes de neige en journée (5 cm), venant créer de petites instabilités.

Pour consulter la vigilance en cours, veuillez vous rendre sur le site https://vigilance.meteofrance.fr/fr

Météo-France - 73 avenue de Paris, 94165 Saint-Mandé cedex - Contact : contact@meteo.fr

Rédigé par Météo-France avec la contribution des observateurs du réseau nivo-météorologiques. Partenariat : ANMSM (Maires de Stations de Montagne), DSF (Domaines Skiables de France), ADSP (Directeurs de Pistes et de la Sécurité des Stations de Sports d'Hiver) et autres acteurs de la montagne.

Bulletin neige & avalanches par téléphone au
0 892 68 10 20 Service 0,35 € / min + prix appel

RÉPUBLIQUE FRANÇAISE
Liberté Égalité Fraternité

METEO FRANCE
À VOS CÔTÉS, DANS UN CLIMAT QUI CHANGE

Bulletin d'estimation du risque d'avalanche

(valable en dehors des pistes balisées et ouvertes)

MASSIF : Bauges

Rédigé le vendredi 20 mars 2026 à 16h

Conditions nivo-météo des 7 derniers jours

	sam. 14/03				dim. 15/03				lun. 16/03				mar. 17/03				mer. 18/03				jeu. 19/03				ven. 20/03			
	03h	09h	15h	21h	03h	09h	15h	21h	03h	09h	15h	21h	03h	09h	15h	21h	03h	09h	15h	21h	03h	09h	15h	21h	03h	09h	15h	21h
Météo																												
Vent (km/h)	45	35	25	25	35	25	30	15	15	20	20	15	25	25	30	30	25	20	70	40	40	20	20	20	15	10	5	5
à 2000m																												
Vent (km/h)	35	25	20	20	30	20	25	10	10	15	15	10	15	15	20	20	15	15	40	35	35	15	20	10	5	5	0	0
à 1500m																												

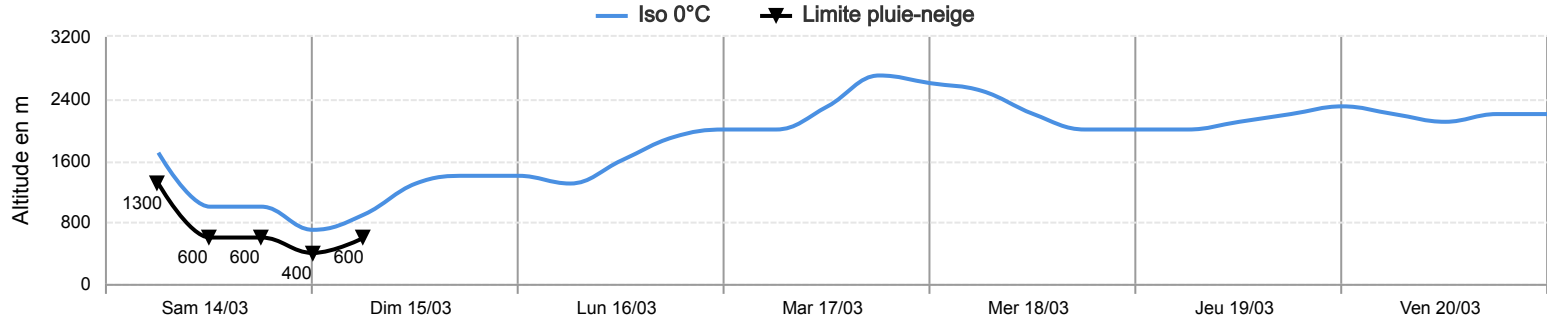

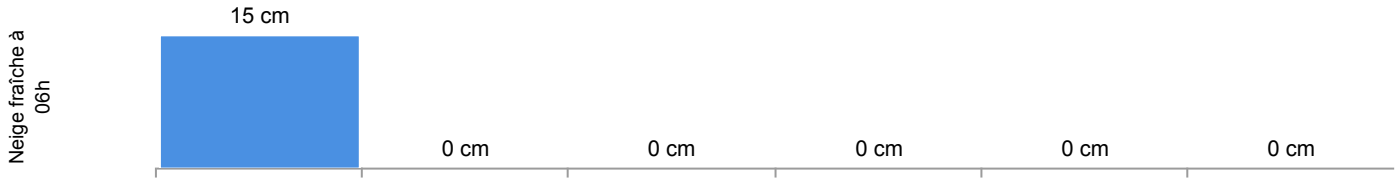

Risque d'avalanche	sam. 14/03	dim. 15/03	lun. 16/03	mar. 17/03	mer. 18/03	jeu. 19/03	ven. 20/03
	3	3	2	2	2	2	2

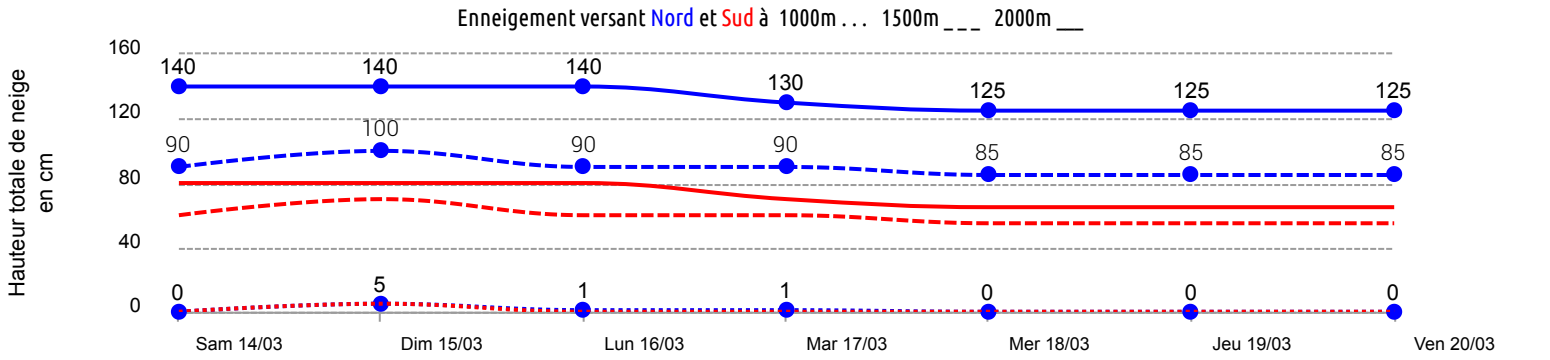

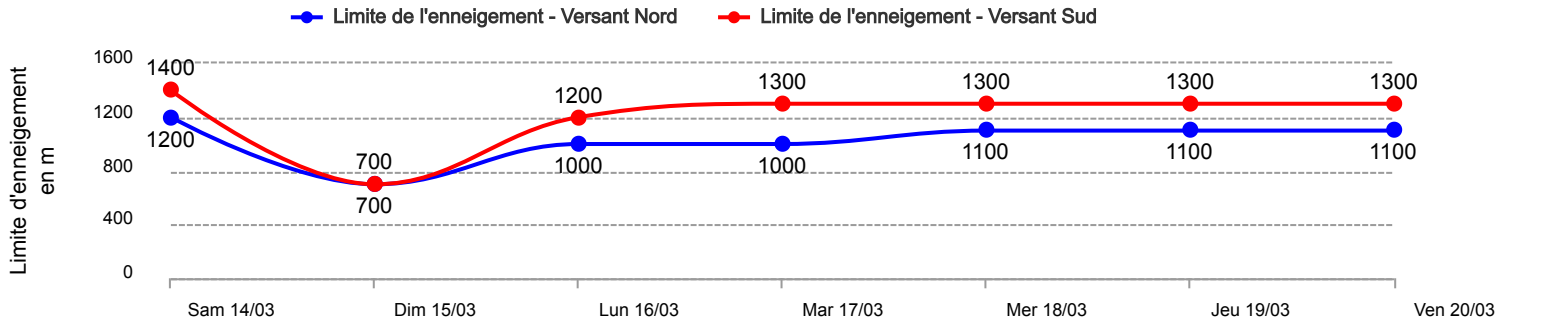

Pour consulter la vigilance en cours, veuillez vous rendre sur le site https://vigilance.meteofrance.fr/fr

Météo-France - 73 avenue de Paris, 94165 Saint-Mandé cedex - Contact : contact@meteo.fr

Rédigé par Météo-France avec la contribution des observateurs du réseau nivo-météorologiques. Partenariat : ANMSM (Maires de Stations de Montagne), DSF (Domaines Skiables de France), ADSP (Directeurs de Pistes et de la Sécurité des Stations de Sports d'Hiver) et autres acteurs de la montagne.

Bulletin neige & avalanches par téléphone au
0 892 68 10 20 Service 0,35 € / min + prix appel