Bulletin d'estimation du risque d'avalanche
(valable en dehors des pistes balisées et ouvertes)

MASSIF : Haut-Var Haut-Verdon

Rédigé le vendredi 20 mars 2026 à 16h

Estimation des risques pour le : SAMEDI 21 MARS

RARES INSTABILITÉS DANS LA NEIGE VENTÉE

2

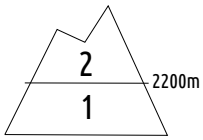

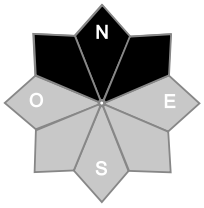

Au-dessus de 2200m indice de risque limité, plus bas indice faible.

Départs spontanés : rares départs de neige humide, de faible ampleur.

Déclenchements provoqués : plaques résiduelles dans la neige ventée.

Indices de risque : 5 très fort - 4 fort - 3 marqué - 2 limité - 1 faible -- En noir : les pentes les plus dangereuses

Stabilité du manteau neigeux

Situation avalancheuse typique : neige ventée

Déclenchements provoqués : plaques résiduelles encore en place en altitude suite au transport de neige par le vent des derniers jours. Elles sont plus fréquentes dans les ubacs au-dessus de 2200/2400 m environ, là où le manteau neigeux n'est pas encore printanier. Elles deviennent progressivement difficiles à déclencher, mais peuvent encore céder au passage d'un skieur. Elles sont facilement identifiables, présentes dans les zones d'accumulation, en contrebas ou derrière les crêtes, les ruptures de pente ou les bosses. Elles provoquent des avalanches de taille petite à moyenne (taille 1 à 2). Une très rare grande avalanche (taille 3) n'est pas exclue en cas de rupture d'une couche fragile persistante plus profondément enfouie, suite à un premier départ de surface par exemple.

Départs spontanés : l'activité en neige humide reste limitée, mais quelques départs sont possibles dans les pentes raides bien ensoleillées. Avalanches petites en général, plus rarement moyennes (taille 1, voire 2).

Qualité de la neige

Enneigement plutôt excédentaire dans le Haut-Verdon, proche des normales dans le Haut Var.
Hauteurs de neige observées : vers 2000 m, 175 cm dans un fond de vallon du Haut-Verdon, 116 cm dans le Haut Var.

Enneigement skiable : vers 1400/1500 m en ubacs, 1700/1800 m en adrets peu pentus.

État de la neige en surface : manteau neigeux printanier dans les adrets, croûté en début de matinée, s'humidifiant au soleil en cours de journée. Des accumulations de neige rapportée par le vent en altitude.
Dans les ubacs, la neige reste froide au-dessus de 2000 m environ, encore assez légère dans les combes ou forêts d'altitude abritées, mais souvent très travaillée ou durcie par le vent dans les secteurs exposés.

Aperçu météo pour le samedi 21 mars

	nuit	matin	après-midi	soir

Ensoleillé le matin puis s'ennuageant. Développement d'averses en cours d'après-midi donnant un peu de neige au-dessus de 1500/1700 m.

Pluie-Neige			1 600 m	1 500 m
Iso 0 °C	2 000 m	2 000 m	2 000 m	1 800 m
Vent 2000 m	5 km/h	10 km/h	20 km/h	10 km/h
Vent 3000 m	10 km/h	15 km/h	20 km/h	15 km/h

Épaisseur de neige hors-piste

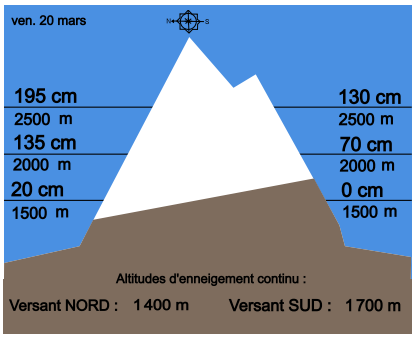

Précipitations à 1800 m

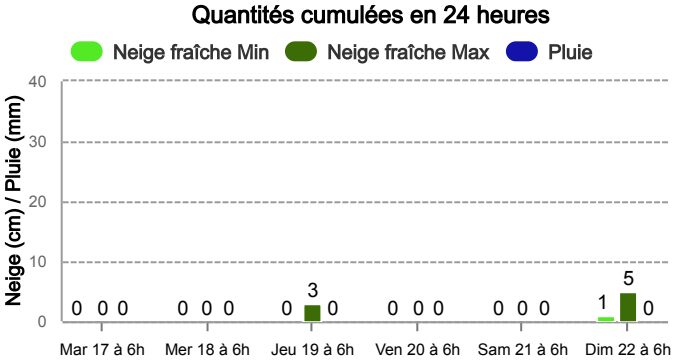

Tendance du dimanche 22 mars

2

Indice de risque limité

Risque en légère hausse avec la mise en place de chutes de neige pouvant entrainer la formation de quelques plaques de faible épaisseur. Maintien probable d'un risque limité.

Pour consulter la vigilance en cours, veuillez vous rendre sur le site https://vigilance.meteofrance.fr/fr

Météo-France - 73 avenue de Paris, 94165 Saint-Mandé cedex - Contact : contact@meteo.fr

Rédigé par Météo-France avec la contribution des observateurs du réseau nivo-météorologiques. Partenariat : ANMSM (Maires de Stations de Montagne), DSF (Domaines Skiables de France), ADSP (Directeurs de Pistes et de la Sécurité des Stations de Sports d'Hiver) et autres acteurs de la montagne.

Bulletin neige & avalanches par téléphone au 0 892 68 10 20 Service 0,35 € / min + prix appel

RÉPUBLIQUE FRANÇAISE
Liberté Égalité Fraternité

METEO FRANCE
À VOS CÔTÉS, DANS UN CLIMAT QUI CHANGE

Bulletin d'estimation du risque d'avalanche

(valable en dehors des pistes balisées et ouvertes)

MASSIF : Haut-Var Haut-Verdon

Rédigé le vendredi 20 mars 2026 à 16h

Conditions nivo-météo des 7 derniers jours

	sam. 14/03				dim. 15/03				lun. 16/03				mar. 17/03				mer. 18/03				jeu. 19/03				ven. 20/03			
	03h	09h	15h	21h	03h	09h	15h	21h	03h	09h	15h	21h	03h	09h	15h	21h	03h	09h	15h	21h	03h	09h	15h	21h	03h	09h	15h	21h
Météo																												
Vent (km/h)	40	50	30	20	60	75	45	35	55	40	35	30	20	15	20	25	20	50	80	80	65	50	30	30	25	15	15	15
à 3000m																												
Vent (km/h)	15	25	20	15	20	55	25	15	20	20	25	15	10	10	15	10	10	25	50	50	45	30	20	15	10	10	15	5
à 2000m																												

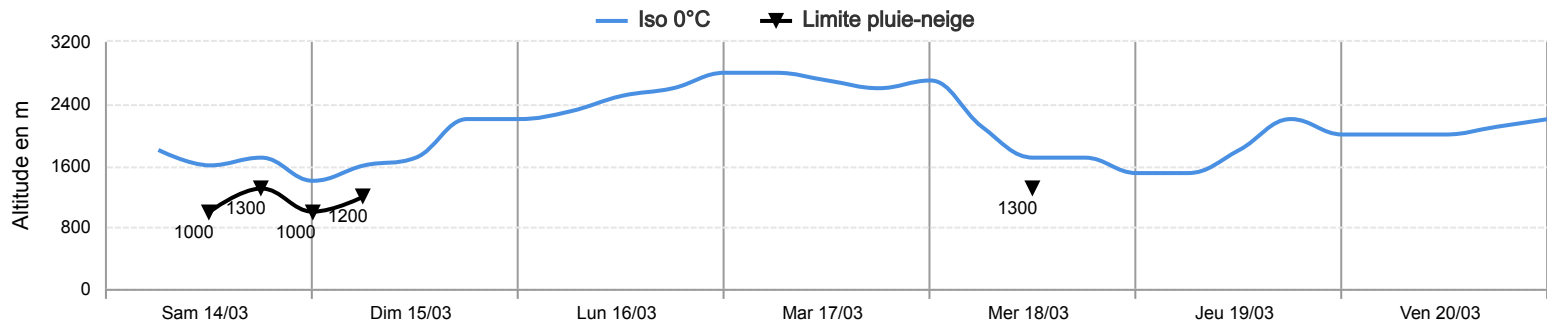

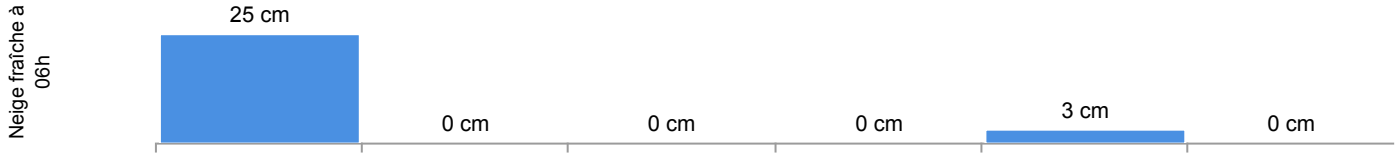

Risque d'avalanche	sam. 14/03	dim. 15/03	lun. 16/03	mar. 17/03	mer. 18/03	jeu. 19/03	ven. 20/03
	3	3	3	2	3	3	2

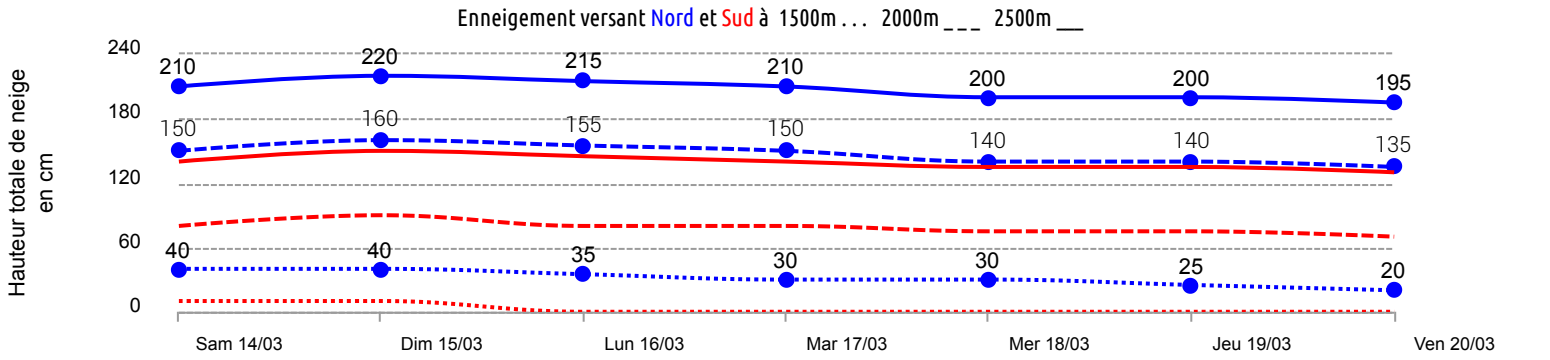

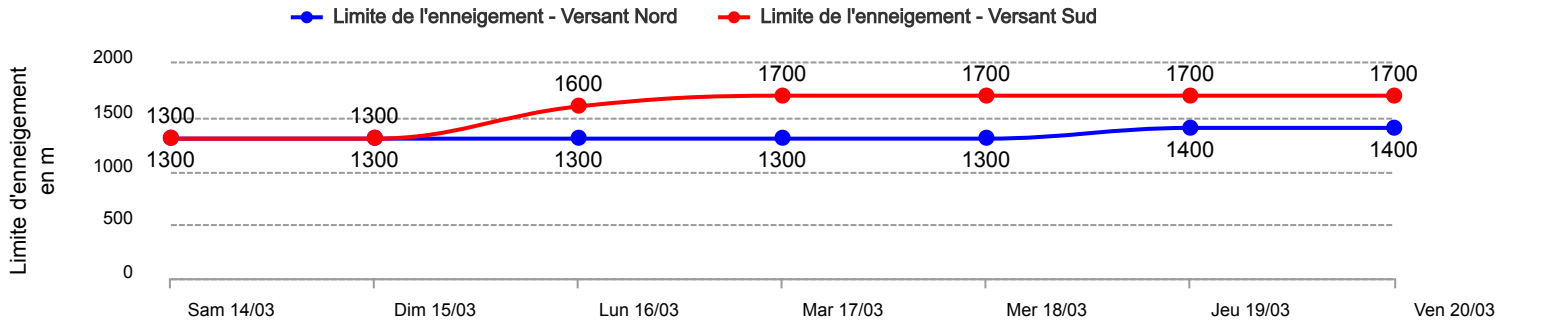

Pour consulter la vigilance en cours, veuillez vous rendre sur le site https://vigilance.meteofrance.fr/fr

Météo-France - 73 avenue de Paris, 94165 Saint-Mandé cedex - Contact : contact@meteo.fr

Rédigé par Météo-France avec la contribution des observateurs du réseau nivo-météorologiques. Partenariat : ANMSM (Maires de Stations de Montagne), DSF (Domaines Skiables de France), ADSP (Directeurs de Pistes et de la Sécurité des Stations de Sports d'Hiver) et autres acteurs de la montagne.

Bulletin neige & avalanches par téléphone au

0 892 68 10 20 Service 0,35 € / min + prix appel