Bulletin d'estimation du risque d'avalanche
(valable en dehors des pistes balisées et ouvertes)

MASSIF : Haute-Ariege

Rédigé le vendredi 20 mars 2026 à 16h

Estimation des risques pour le : SAMEDI 21 MARS

QUELQUES STRUCTURES DE PLAQUES EN ALTITUDE, HUMIDIFICATION AU SOLEIL.

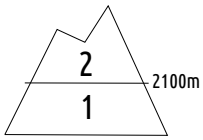

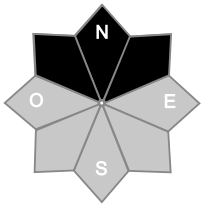

Au-dessus de 2100m indice de risque limité, plus bas indice faible.

Départs spontanés : Reprise de l'humidification en cours de journée, au gré de l'ensoleillement

Déclenchements provoqués : Encore quelques plaques possibles dans les versants froids

Indices de risque : 5 très fort - 4 fort - 3 marqué - 2 limité - 1 faible -- En noir : les pentes les plus dangereuses

Stabilité du manteau neigeux

Situation avalancheuse typique : couche fragile persistante neige humide

Déclenchements provoqués :
- Il reste possiblement quelques structures de plaques en altitude : en versants Nord au-dessus de 2100/2200 m, ainsi que dans d'autres secteurs ayant résisté à l'humidification de ces derniers jours. Ces accumulations en neige sèche sont encore susceptibles de reposer sur du givre de surface ou de la neige roulée avec des cassures typiques de 30/40 cm et peuvent être déclenchés par le passage d'un seul skieur/randonneur.

Observables : neige travaillée par le vent en surface, fissures sous les skis, affaissement accompagné de 'whoomf'.

- Dans les autres secteurs, le risque se limite à des coulées sous les skis en neige humide au fur et à mesure de l'ensoleillement.

Départs spontanés :
- Avalanches de taille petite à moyenne possibles en neige humide, emportant parfois toute l'épaisseur de neige. Après un bon regel nocturne stabilisateur, le risque augmente dès la fin de matinée dans les versants Est et Sud-Est, où les accumulations de neige sont les plus importantes, notamment au dessus de 2100/2200m. L'après-midi, le risque se propage aux autres versants qui s'humidifient progressivement avec l'ensoleillement (sud puis ouest). En dessous de 2100m, les volumes sont plus faibles et le risque se limite à de rares coulées ponctuelles en neige humide dans les pentes ou couloirs raides.

Autre :

Neige dure et parfois glacée aux premières heures du jour dans les zones s'étant humidifiées la veille. Ponts de neige et corniches de moins en moins solides au fil des heures.

Qualité de la neige

Enneigement :
Malgré le redoux de ces derniers jours, l'enneigement reste très correct pour la saison, après plusieurs hivers déficitaires. La fonte est tout de même importante au soleil et en moyenne montagne notamment en versants sud.
La limite skiable évolue peu avec des quantités de neige encore importantes dès 1500/1700m. On peut souvent chausser les skis vers 1500m en versant nord, voire1300/1400 m dans les meilleures configurations, plutôt 1700/1800m en versants sud.

Qualité de la neige :
Samedi matin, en dehors des zones de forêt, la neige devrait être bien dure et regelée après une nuit claire. En cours de journée, la neige s'humidifie progressivement sous 2100 m en tous versants et jusqu'à haute altitude dans les versants ensoleillés. On trouve alors une neige de printemps devenant lourde l'après-midi en Sud. Quelques combes bien ombragées devraient néanmoins être encore poudreuses à partir de 2200/2400 m.

Aperçu météo pour le samedi 21 mars

	nuit	matin	après-midi	soir
Belle matinée, rares averses l'après-midi proche de la crête frontière.				
Pluie-Neige			2 000 m	
Iso 0 °C	2 500 m	2 500 m	2 400 m	2 300 m
Vent 2000 m	5 km/h	5 km/h	5 km/h	10 km/h
Vent 3000 m	10 km/h	10 km/h	10 km/h	10 km/h

Épaisseur de neige hors-piste

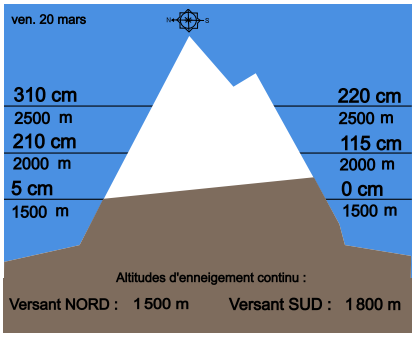

Précipitations à 1800 m

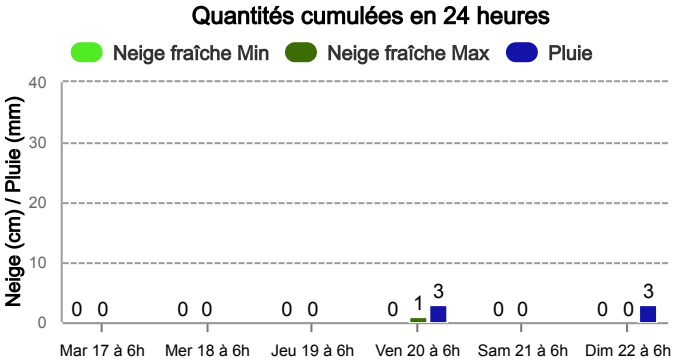

Tendance du dimanche 22 mars

Indice de risque limité

Quelques averses de neige attendues dimanche après-midi, insuffisantes néanmoins pour changer le risque.

Pour consulter la vigilance en cours, veuillez vous rendre sur le site https://vigilance.meteofrance.fr/fr

Météo-France - 73 avenue de Paris, 94165 Saint-Mandé cedex - Contact : contact@meteo.fr

Rédigé par Météo-France avec la contribution des observateurs du réseau nivo-météorologiques. Partenariat : ANMSM (Maires de Stations de Montagne), DSF (Domaines Skiables de France), ADSP (Directeurs de Pistes et de la Sécurité des Stations de Sports d'Hiver) et autres acteurs de la montagne.

Bulletin neige & avalanches par téléphone au **0 892 68 10 20** Service 0,35 € / min + prix appel

RÉPUBLIQUE FRANÇAISE
Liberté Égalité Fraternité

METEO FRANCE
À VOS CÔTÉS, DANS UN CLIMAT QUI CHANGE

Bulletin d'estimation du risque d'avalanche

(valable en dehors des pistes balisées et ouvertes)

MASSIF : Haute-Ariege

Rédigé le vendredi 20 mars 2026 à 16h

Conditions nivo-météo des 7 derniers jours

	sam. 14/03				dim. 15/03				lun. 16/03				mar. 17/03				mer. 18/03				jeu. 19/03				ven. 20/03			
	03h	09h	15h	21h	03h	09h	15h	21h	03h	09h	15h	21h	03h	09h	15h	21h	03h	09h	15h	21h	03h	09h	15h	21h	03h	09h	15h	21h
Météo																												
Vent (km/h)	50	50	55	70	95	95	75	50	40	30	30	20	25	15	15	15	15	15	15	25	30	25	25	15	15	15	20	20
à 3000m																												
Vent (km/h)	30	30	35	45	60	60	50	30	25	20	20	10	15	10	10	10	10	5	5	15	20	20	20	10	10	5	10	10
à 2000m																												

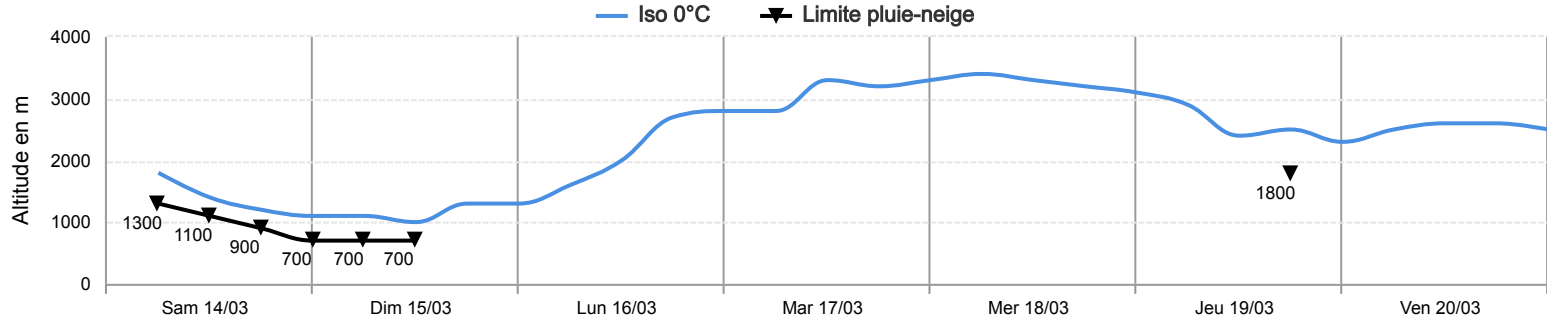

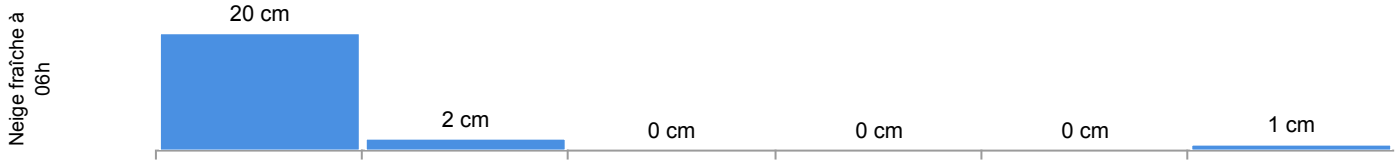

Risque d'avalanche	sam. 14/03	dim. 15/03	lun. 16/03	mar. 17/03	mer. 18/03	jeu. 19/03	ven. 20/03
	3	3	3	3	3	2	2

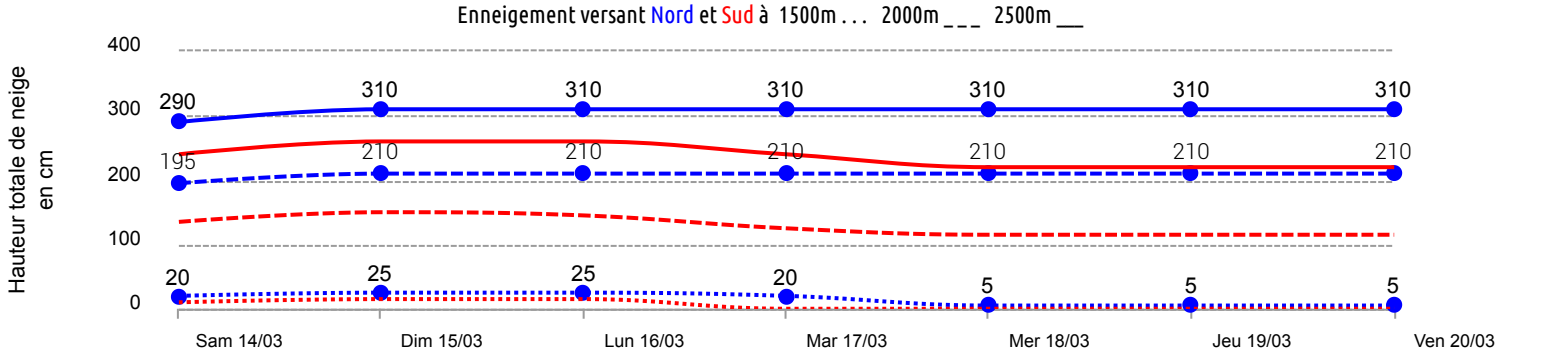

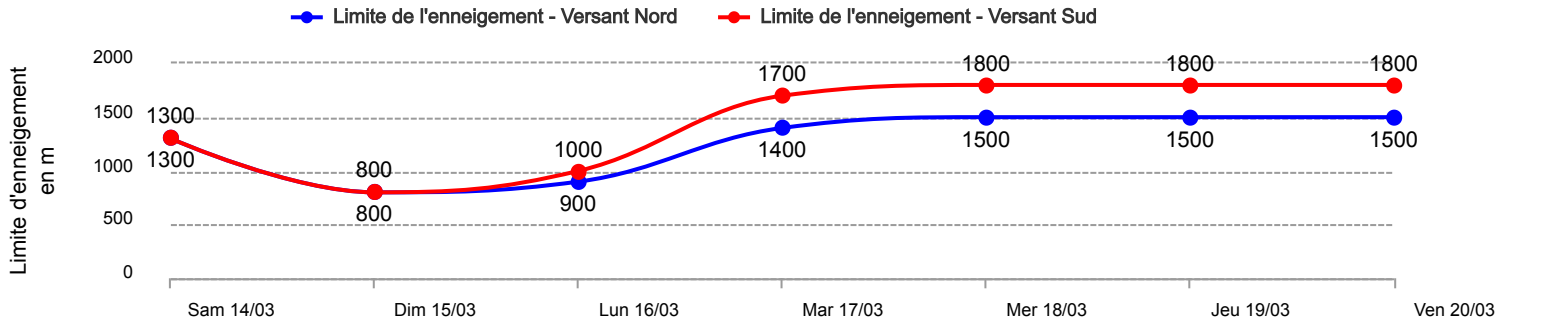

Pour consulter la vigilance en cours, veuillez vous rendre sur le site https://vigilance.meteofrance.fr/fr

Météo-France - 73 avenue de Paris, 94165 Saint-Mandé cedex - Contact : contact@meteo.fr

Rédigé par Météo-France avec la contribution des observateurs du réseau nivo-météorologiques. Partenariat : ANMSM (Maires de Stations de Montagne), DSF (Domaines Skiables de France), ADSP (Directeurs de Pistes et de la Sécurité des Stations de Sports d'Hiver) et autres acteurs de la montagne.

Bulletin neige & avalanches par téléphone au
0 892 68 10 20 Service 0,35 € / min + prix appel