Bulletin d'estimation du risque d'avalanche
(valable en dehors des pistes balisées et ouvertes)

MASSIF : Haute-Tarentaise

Rédigé le vendredi 20 mars 2026 à 16h

Estimation des risques pour le : SAMEDI 21 MARS

MANTEAU PRINTANIER EN SUD, TRÈS TRAVAILLÉ PAR LE VENT EN NORD AVEC QUELQUES INSTABILITÉS

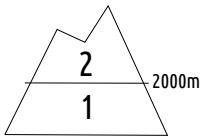

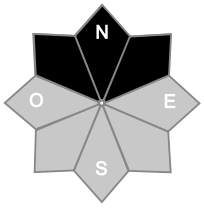

Au-dessus de 2000m indice de risque limité, plus bas indice faible.

Départs spontanés : Rares départs de neige humide dans les versants ensoleillés

Déclenchements provoqués : Quelques plaques à vent dans les versants Nord d'altitude

Indices de risque : 5 très fort - 4 fort - 3 marqué - 2 limité - 1 faible -- En noir : les pentes les plus dangereuses

Stabilité du manteau neigeux

Situation avalancheuse typique : neige ventée

Déclenchements provoqués : Quelques plaques à vent en versant Nord au-dessus de 2000 m, quelques fois facilement déclenchable par un skieur. Elles sont souvent dures et se retrouvent derrière les ruptures de terrain, en milieu, voire aux pieds des pentes. Le haut des pentes étant souvent décapé par le vent.
Observables : accumulation de neige ventée derrière une rupture de pente, test de stabilité, fissures devant les skis, éventuellement encore quelques woumfs possible.

Départs spontanés : Rares départs ponctuels en neige humide dans les versants raides ensoleillés, en dessous de 2000 m. Ces départs se retrouvent souvent aux pieds des rochers ou falaises surchauffés par le soleil. Taille 1.

Qualité de la neige

Enneigement : Encore un peu au dessus de la moyenne, sauf aux plus basses altitudes où les hauteurs de neige sont tout juste correctes pour la saison.

Limite skiable : 1300m au mieux en Nord. Plutôt 1600 m en sud pas trop raide.

Qualité de la neige : En Sud, neige de printemps, regelée en matinée puis humide l'après-midi.
En Nord au-dessus de 2000 m, neige sèche souvent travaillée par le vent, cartonnée voire dure proche des crêtes. On trouve encore de rares combes protégées du vent en poudre.
En versant Ouest et Est, neige croutée en matinée devenant humide sous l'effet du soleil. Il manque encore quelques cycles de gel/dégel pour arriver à une parfaite neige de printemps.

Aperçu météo pour le samedi 21 mars

nuit	matin	après-midi	soir

Largement ensoleillé, quelques cumulus instables l'après-midi dans les massifs.

Pluie-Neige				
Iso 0 °C	2 200 m	2 300 m	2 300 m	1 800 m
Vent 2500 m	↘ 5 km/h	↘ 10 km/h	→ 15 km/h	↗ 10 km/h
Vent 3500 m	↘ 20 km/h	↓ 15 km/h	↘ 20 km/h	↘ 20 km/h

Épaisseur de neige hors-piste

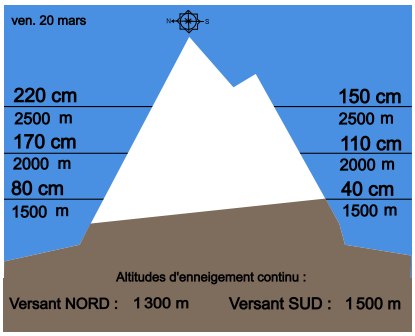

Précipitations à 1800 m

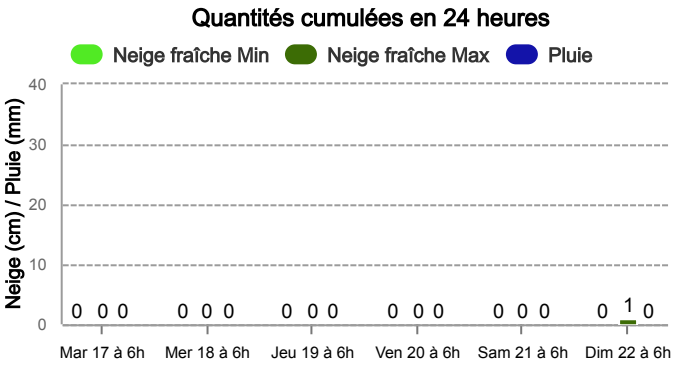

Tendance du dimanche 22 mars

Indice de risque limité

Plus nuageux avec de faibles chutes de neige. Cumuls modestes avec peu de nouvelles instabilités.

Pour consulter la vigilance en cours, veuillez vous rendre sur le site https://vigilance.meteofrance.fr/fr

Météo-France - 73 avenue de Paris, 94165 Saint-Mandé cedex - Contact : contact@meteo.fr

Rédigé par Météo-France avec la contribution des observateurs du réseau nivo-météorologiques. Partenariat : ANMSM (Maires de Stations de Montagne), DSF (Domaines Skiables de France), ADSP (Directeurs de Pistes et de la Sécurité des Stations de Sports d'Hiver) et autres acteurs de la montagne.

Bulletin neige & avalanches par téléphone au **0 892 68 10 20** Service 0,35 € / min + prix appel

RÉPUBLIQUE FRANÇAISE
Liberté Égalité Fraternité

METEO FRANCE
À VOS CÔTÉS, DANS UN CLIMAT QUI CHANGE

Bulletin d'estimation du risque d'avalanche

(valable en dehors des pistes balisées et ouvertes)

MASSIF : Haute-Tarentaise

Rédigé le vendredi 20 mars 2026 à 16h

Conditions nivo-météo des 7 derniers jours

	sam. 14/03				dim. 15/03				lun. 16/03				mar. 17/03				mer. 18/03				jeu. 19/03				ven. 20/03			
	03h	09h	15h	21h	03h	09h	15h	21h	03h	09h	15h	21h	03h	09h	15h	21h	03h	09h	15h	21h	03h	09h	15h	21h	03h	09h	15h	21h
Météo																												
Vent (km/h)	50	15	25	30	20	40	20	20	25	40	40	25	25	30	30	30	35	45	60	55	40	20	15	15	30	35	15	15
à 3500m																												
Vent (km/h)	30	5	15	20	10	30	15	10	10	20	30	15	15	15	15	15	20	30	50	40	30	15	10	10	10	10	5	0
à 2500m																												

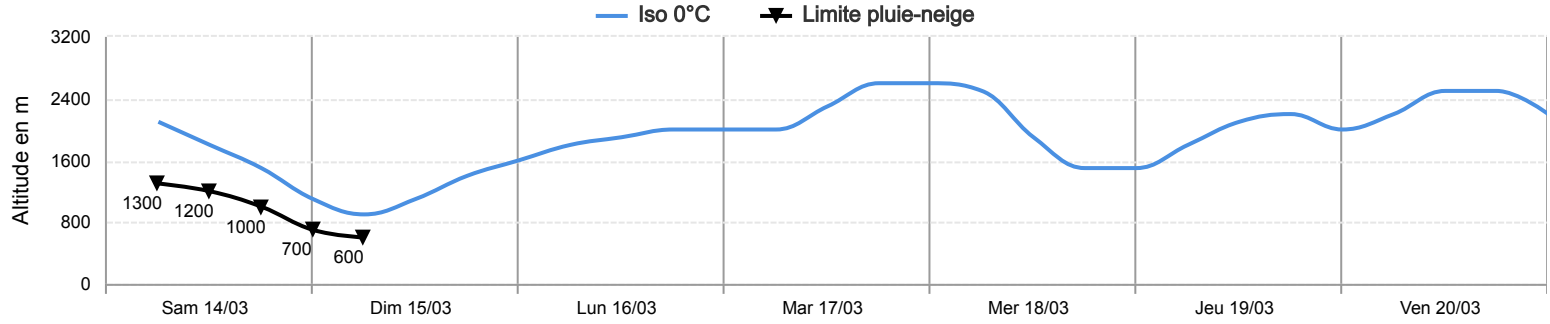

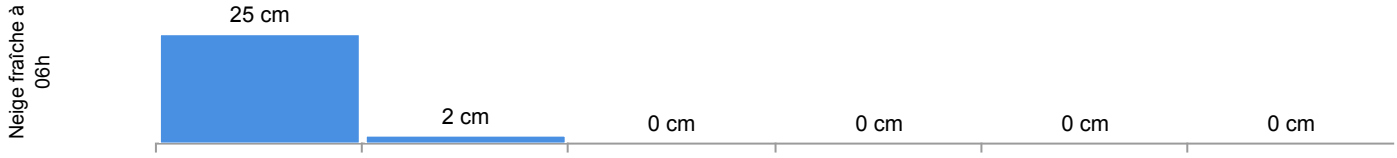

Risque d'avalanche	sam. 14/03	dim. 15/03	lun. 16/03	mar. 17/03	mer. 18/03	jeu. 19/03	ven. 20/03
	3	3	3	2	3	3	2



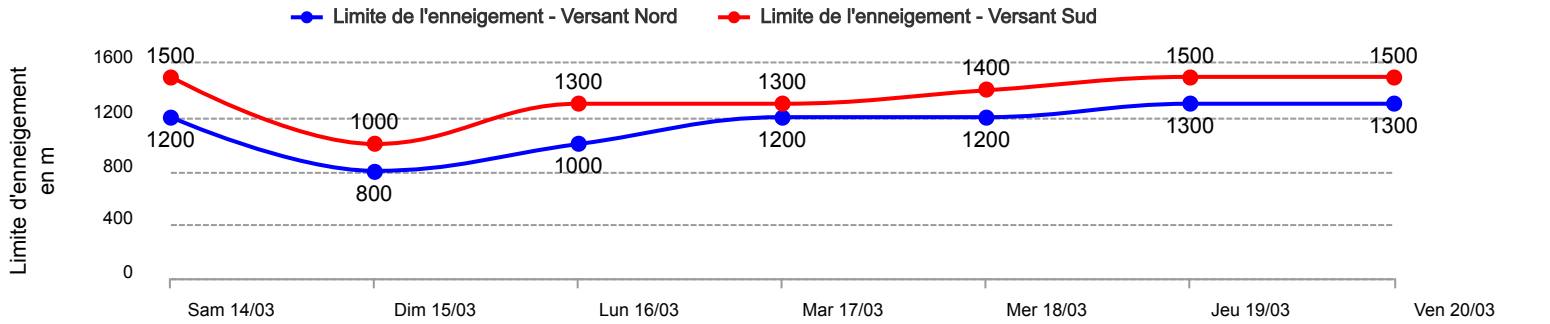

Pour consulter la vigilance en cours, veuillez vous rendre sur le site https://vigilance.meteofrance.fr/fr

Météo-France - 73 avenue de Paris, 94165 Saint-Mandé cedex - Contact : contact@meteo.fr

Rédigé par Météo-France avec la contribution des observateurs du réseau nivo-météorologiques. Partenariat : ANMSM (Maires de Stations de Montagne), DSF (Domaines Skiables de France), ADSP (Directeurs de Pistes et de la Sécurité des Stations de Sports d'Hiver) et autres acteurs de la montagne.

Bulletin neige & avalanches par téléphone au
0 892 68 10 20 Service 0,35 € / min + prix appel