GOBIERNO DE ESPAÑA
VICEPRESIDENCIA TERCERA DEL GOBIERNO
MINISTERIO PARA LA TRANSICIÓN ECOLÓGICA Y EL RETO DEMOGRÁFICO

Boletín de información nivológica y de peligro de aludes

Pirineo Navarro y Aragonés

aemet Agencia Estatal de Meteorología

sábado, 21 de marzo de 2026

Pronóstico hasta las 24 horas del domingo, día 22 de marzo

(Válido fuera de pistas de esquí balizadas y abiertas)

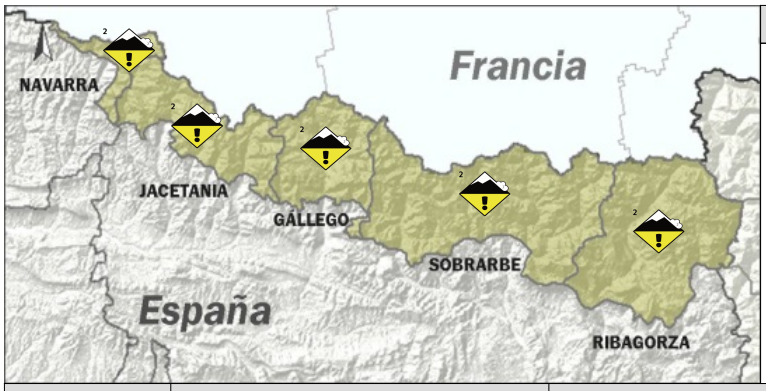

Problemas de aludes

Nieve húmeda

Capas débiles persistentes

Macizo	Peligro	Problemas de aludes, cota, orientación, tamaño	Innivación observada (m)
Navarra	2 **Limitado** — Horas centrales (1→2)	**Nieve húmeda** — 2	2026-03-21 — Cota más baja caras N
Jacetania	2 **Limitado** — Durante el día (2 / 1→2, 2400)	**Nieve húmeda** — 2; **Capas débiles persistentes** — 2 (2400)	2026-03-21 — Cota más baja caras N
Gállego	2 **Limitado** — Durante el día (2 / 1→2, 2400)	**Nieve húmeda** — 2; **Capas débiles persistentes** — 2 (2400)	2026-03-21 — Cota más baja caras N
Sobrarbe	2 **Limitado** — Durante el día (2 / 1→2, 2400)	**Nieve húmeda** — 2; **Capas débiles persistentes** — 2 (2400)	2026-03-21 — Cota más baja caras N

AEMET. Se autoriza la reproducción de su contenido citando la fuente.

Boletín de información nivológica y de peligro de aludes

Pirineo Navarro y Aragonés

Ribagorza	Durante el día **Limitado**	**Nieve húmeda**  **Capas débiles persistentes** 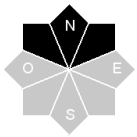 	2026-03-21 Cota más baja caras N

Estado del manto y observaciones recientes

Continúan los procesos de fusión y apelmazamiento de la nieve, con unos espesores que durante las últimas 24 horas han disminuido entre 1 y 5 cm en los diferentes puntos de observación. El manto sigue presentando continuidad desde medianías, a mayor altitud en orientaciones sur. Los espesores rondan los 40 a 140 cm en torno a 1.800 metros y van aumentando conforme ascendemos, de tal manera que pueden superarse en algunas áreas los 180 a 200 cm en cota 2.100.

La nieve se encuentra muy humedecida en zonas medias y bajas, y también superficialmente en solanas de cotas altas. Generalmente, de cotas medias hacia arriba, está sometida al ciclo de fusión diurna y rehielo nocturno. En las altas umbrías predomina la nieve más seca, venteada y encostrada, pudiendo existir estratos débiles en el interior del manto localizados a no demasiada profundidad y que han dado muestras de actividad en algunos puntos. En dichas umbrías, todavía se observan las antiguas capas débiles persistentes a mayor profundidad, aunque sin indicios de reactividad en los tests por el momento.

Evolución del manto y peligro de aludes para el domingo, día 22

Problema de nieve húmeda. Problema de capas débiles persistentes y placas de viento en cotas altas.

Tras un nuevo ciclo de rehielo nocturno, amanecerá con un manto estable a primeras horas en cotas medias y umbrías de cotas altas. Conforme avance el día, serán probables algunas purgas de nieve húmeda en pendientes con la suficiente inclinación. Prevalecerán las bolas y coladas, con tamaños pequeños de alud. Localmente, se podrá producir alguno de placa húmeda y tamaño mediano, ya sea natural o accidental, si el agua percolante llega a afectar algún estrato débil interno. Del mismo modo, no se descarta algún deslizamiento basal en zonas de terreno liso o herboso que pueda alcanzar un tamaño mayor.

En umbrías de cotas altas, existen estructuras de placa sobre capa débil de manera aislada, a menudo cerca de crestas y cordales. Estas serán susceptibles de colapsar ante sobrecargas débiles, dando lugar a aludes de tamaño pequeño o mediano, muy raramentemente grande.

Por último, cabe prestar atención al peligro de resbalones sobre la costra de rehielo a primeras horas.

AEMET. Se autoriza la reproducción de su contenido citando la fuente.

Predicción meteorológica para el domingo, día 22

Pirineo navarro:
Poco nuboso o despejado, con tendencia a muy nuboso o cubierto con nubosidad baja al final del día. No se descartan precipitaciones débiles durante la segunda mitad del día en la divisoria fronteriza, asociadas a la nubosidad baja. Cota de nieve bajando de 1600 a 1400 metros aproximadamente. Temperaturas mínimas con pocos cambios, y máximas en descenso. Heladas débiles, localmente moderadas en cotas altas. Viento moderado de componente norte, con intervalos de intensidad fuerte en cotas altas y zonas expuestas a partir de la tarde.

Pirineo aragonés:
Predominio de poco nuboso o despejado, salvo por algunos bancos de nubes bajas o nieblas matinales, con nubosidad de evolución diurna por la tarde. En la divisoria fronteriza tenderá a muy nuboso o cubierto al final del día, con nubosidad baja de retención. No se descartan precipitaciones débiles a partir de la tarde en la divisoria fronteriza, asociadas a la nubosidad baja. Cota de nieve bajando de 1700 a 1400 metros aproximadamente. Temperaturas en ligero o moderado descenso, más acusado de las mínimas. Heladas débiles, moderadas o localmente fuertes en cotas altas. Viento flojo de dirección variable, tendiendo a moderado de componente norte a partir de la tarde, con intervalos de fuerte en cotas altas y zonas expuestas. No se descartan rachas muy fuertes de manera localizada al final del día.

Datos en la atmósfera libre:

Altitud de la isoterma de 0 ºC: 2200 m
Altitud de la isoterma de -10 ºC: 4200 m

Viento a 1500 m: VRB 5 km/h
Viento a 3000 m: NW 25 km/h

Evolución para el lunes día 23

Nivel de peligro con pocos cambios.

(Información elaborada a partir de los datos recibidos de los refugios de Linza, Lizara, Panticosa, Bachimaña, Góriz, Pineta, Estós, Angel Orús, La Renclusa, Cap de Llauset y Belagua, de las estaciones de esquí de Candanchú, Astún, Formigal y Panticosa (lagos), de la estación de esquí de fondo de Llanos del Hospital y de Ordesa Pradera)

Escala europea de peligro de aludes

Débil | Limitado | Notable | Fuerte | Muy Fuerte

Problemas de aludes

Nieve reciente | Placas de viento | Capas débiles persistentes | Nieve húmeda | Deslizamientos basales | Sin problema evidente

Nota1: Se recuerda que, siempre que haya nieve, la ausencia total de peligro no existe. Hay que tener presente que en circunstancias desfavorables, con aludes de tamaño 1 (alud pequeño o colada) y tamaño 2 (alud mediano), se pueden sufrir severos daños personales.

Nota2: Los BPA se elaboran en base a información meteorológica así como al estado del manto nivoso a través de sondeos puntuales. Se advierte a los usuarios de la variabilidad de esta información al extrapolarla a zonas extensas de montaña. Por ello, AEMET no se hace responsable de su uso para la toma de decisiones que conciernen a la seguridad personal, ni de los riesgos físicos o materiales de ellas derivadas.

AEMET. Se autoriza la reproducción de su contenido citando la fuente.