ICGC Institut Cartogràfic i Geològic de Catalunya

Servei Meteorològic de Catalunya meteo.cat

Boletín de peligro de aludes para el Pirineo de Catalunya
Del 21/03/2026 al 23/03/2026

(Válido fuera pistas de esquí y zonas no controladas)

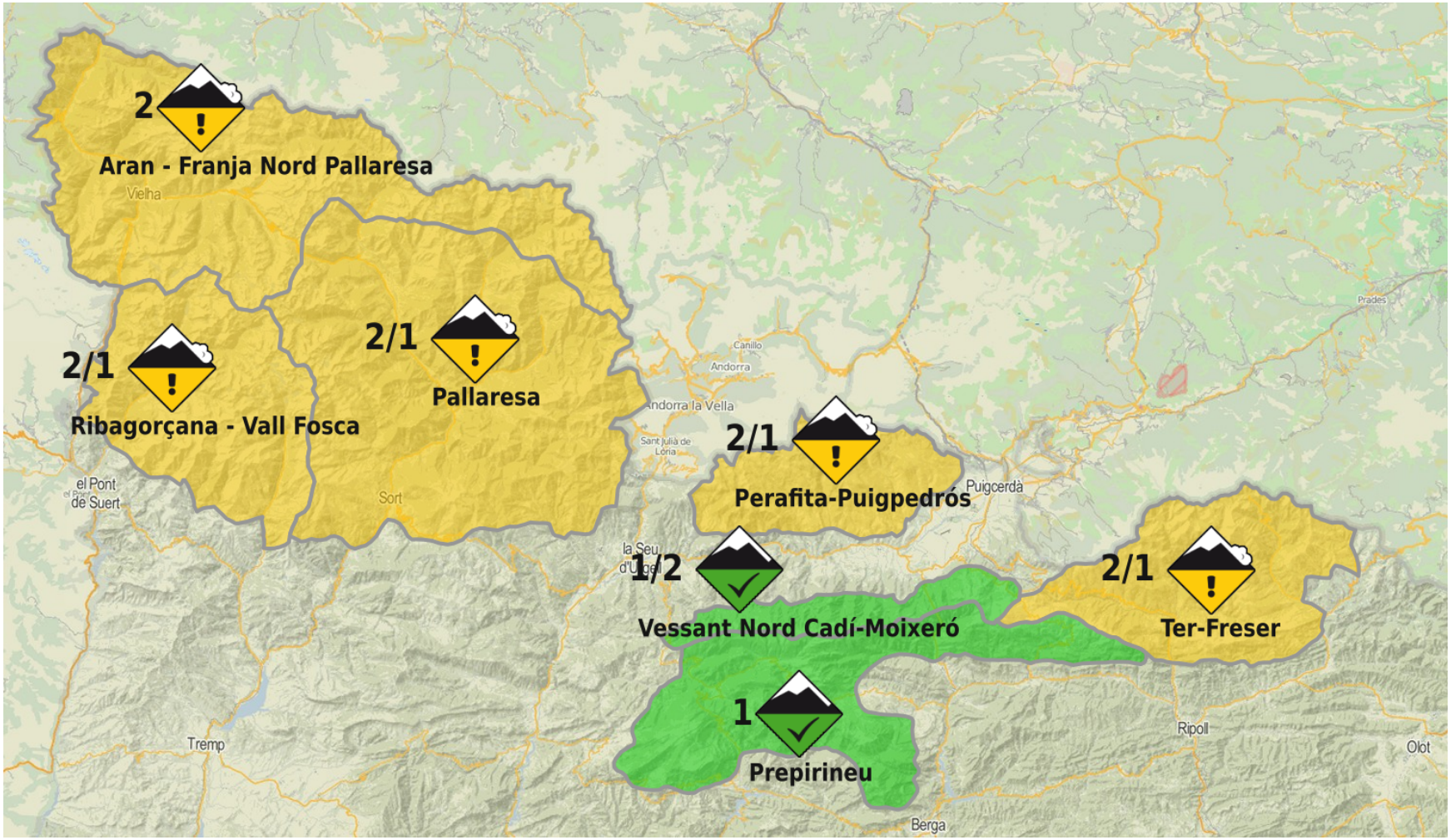

5 MUY FUERTE	4 FUERTE	3 NOTABLE	2 LIMITADO	1 DÉBIL

ICGC Institut Cartogràfic i Geològic de Catalunya

Servei Meteorològic de Catalunya meteo.cat

Boletín de peligro de aludes Aran - Franja Nord Pallaresa Del 21/03/2026 al 23/03/2026

(Válido fuera pistas de esquí y zonas no controladas)

LIMITADO (2).

Situación primaria

Capas débiles persistentes

Distribución

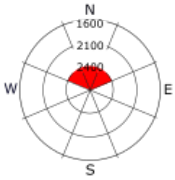

Tamaño

Origen

Tendencia

Situación secundaria

Nieve húmeda

Distribución

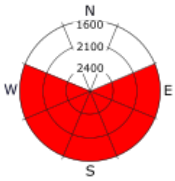

Tamaño

Origen

Tendencia

Estado del manto nivoso

Para el domingo encontraremos un manto rehelado a primera hora y bien asentado, con costras superficiales duras y resbaladizas. En umbrías, en cambio, el manto todavía presenta una estabilidad pobre, especialmente las placas antiguas que permanecen sobre facetas o escarcha. Los lugares más delicados están en las umbrías, en las laderas con cambios abruptos del terreno, poco frecuentados y en canales, por encima de los 2.500 m. En estos lugares podremos desencadenar aludes de tamaño 2 (medio), con capacidad de enterrar a una persona e, incluso, de tamaño 3 (grande), suficiente para enterrar a un grupo de montañeros. El lunes habrá nevado un poco, con viento de N, y se formarán placas de viento nuevas, de pequeño tamaño, bajo collados y crestas en S y E. Son probables también aludes de nieve húmeda, a partir de mediodía, de hasta tamaño 2 (medio), en todas las cotas, en las solanas y hasta cota media. No se descarta algún deslizamiento basal, en solanas, de hasta tamaño 3 (grande).

Distribución del manto nivoso

Hay nieve por encima de unos 1.500 m en umbrías y 1.800 m en solanas. Los espesores a unos 2.200 m son ligeramente superiores a los normales en la Franja Nord de la Pallaresa y en la mitad sur de Arán donde rondan los 180-220 cm. En la mitad norte de Arán son los normales por estas fechas con unos 120-140 cm de espesor total.

Tendencia para las próximas 48-72h

Las placas de viento de nueva formación se mostrarán reactivas. Seguirán las capas débiles persistentes en umbrías. Peligro: EN ASCENSO.

El próximo boletín será emitido el día 2026-03-23

5 MUY FUERTE	4 FUERTE	3 NOTABLE	2 LIMITADO	1 DÉBIL

EAWS EUROPEAN AVALANCHE WARNING SERVICES

ICGC Institut Cartogràfic i Geològic de Catalunya

meteo.cat Servei Meteorològic de Catalunya

Boletín de peligro de aludes Ribagorçana - Vall Fosca Del 21/03/2026 al 23/03/2026

(Válido fuera pistas de esquí y zonas no controladas)

LIMITADO (2), durante las horas centrales del día y por encima de 2.400 m.
DÉBIL (1), en el resto.

Situación primaria

Nieve húmeda

Distribución

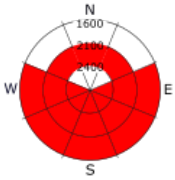

Tamaño

Origen

Tendencia

Situación secundaria

Capas débiles persistentes

Distribución

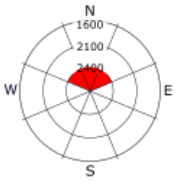

Tamaño

Origen

Tendencia

Estado del manto nivoso

Para el domingo esperamos un manto bien asentado, con una mañana de buen rehielo y una transformación de la nieve a mediodía a causa de la radiación. Con el humedecimiento de las costras superficiales pueden caer aludes de fusión de forma natural oa nuestro paso, esquiando, que llegarán a tamaño 1 (pequeño), sin capacidad para enterrarnos. El terreno más afectado por aludes de fusión son las salidas de puntos oscuros (rocas y árboles) y las canales a solanas. En umbrías elevadas, en el límite norte del sector, podemos encontrar, localmente, alguna placa antigua que con una carga fuerte, podría acabar cayendo, y generar aludes de tamaño 2 (medio), con capacidad de enterrar un montañero. Los lugares delicados están bajo collados y cordales, por encima de 2.500 m y también en umbrías protegidas. El lunes habrá nevado, con viento de norte, y se formarán placas nuevas a sotavento (S y E), pequeñas. Habrá que vigilar con los resbalones a primera hora, por la presencia de costras duras.

Distribución del manto nivoso

Hay nieve en el suelo a 1.600 m en terreno umbrío, y por encima de unos 1.900 m en laderas soleadas. El manto es esquiable por encima de unos 1.800-1.900 ma umbrías. Los grosores alcanzan los 105-135 cm a unos 2.200 m. Estos valores son superiores a los normales para la época.

Tendencia para las próximas 48-72h

Las nuevas placas se mantendrán reactivas. Peligro: SIN CAMBIOS o EN LEVE ASCENSO.

El próximo boletín será emitido el día 2026-03-23

5 MUY FUERTE	4 FUERTE	3 NOTABLE	2 LIMITADO	1 DÉBIL

EAWS EUROPEAN AVALANCHE WARNING SERVICES

ICGC Institut Cartogràfic i Geològic de Catalunya

Servei Meteorològic de Catalunya

Boletín de peligro de aludes Pallaresa
Del 21/03/2026 al 23/03/2026

(Válido fuera pistas de esquí y zonas no controladas)

LIMITADO (2), durante las horas centrales del día y por encima de 2.400 m.
DÉBIL (1), en el resto.

Situación primaria

Nieve húmeda

Distribución

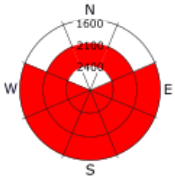

Tamaño

Origen

Tendencia

Situación secundaria

Capas débiles persistentes

Distribución

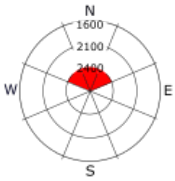

Tamaño

Origen

Tendencia

Estado del manto nivoso

Para el domingo esperamos un manto bien asentado, con una mañana de buen rehielo y una transformación de la nieve a mediodía a causa de la radiación. Con el humedecimiento de las costras superficiales pueden caer aludes de fusión de forma natural a nuestro paso, esquiando, que llegarán a tamaño 1 (pequeño), sin capacidad para enterrar a una persona. El terreno más afectado por aludes de fusión son las salidas de puntos oscuros (rocas y árboles) y las canales a solanas. En umbrías elevadas, en cambio, el manto todavía presenta una estabilidad algo pobre, especialmente las placas antiguas que permanecen sobre facetas o escarcha. Los lugares más delicados son las laderas con cambios abruptos del terreno, poco frecuentados y en canales, por encima de los 2.500 m. El lunes habrá nevado, con viento de norte, y se formarán placas nuevas a sotavento (S y E), pequeñas. Habrá que vigilar con los resbalones a primera hora, por la presencia de costras duras.

Distribución del manto nivoso

Hay nieve en el suelo a 1.600 m en N, y a 1.800-1.900 m en S. El manto es esquiable por encima de unos 1.800-1.900 m en umbrías. Los espesores alcanzan los 115-155 cm en cotas medias, variable según los efectos del viento.

Tendencia para las próximas 48-72h

Las placas nuevas se mantendrán reactivas. Peligro: SIN CAMBIOS o EN LEVE ASCENSO.

El próximo boletín será emitido el día 2026-03-23

5 MUY FUERTE	4 FUERTE	3 NOTABLE	2 LIMITADO	1 DÉBIL

EAWS EUROPEAN AVALANCHE WARNING SERVICES

ICGC Institut Cartogràfic i Geològic de Catalunya

Servei Meteorològic de Catalunya

Boletín de peligro de aludes Perafita-Puigpedrós Del 21/03/2026 al 23/03/2026

(Válido fuera pistas de esquí y zonas no controladas)

LIMITADO (2), durante las horas centrales del día y el lunes. DÉBIL (1), el domingo por la mañana.

Situación primaria

Nieve húmeda

Distribución

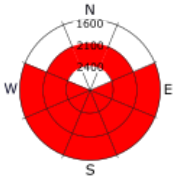

Tamaño

Origen

Tendencia

Situación secundaria

Nieve venteada

Distribución

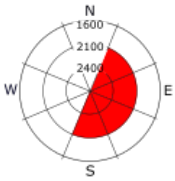

Tamaño

Origen

Tendencia

Estado del manto nivoso

Para el domingo esperamos un manto bien asentado, con una mañana de buen rehielo y una transformación de la nieve a mediodía a causa de la radiación. Con el humedecimiento de las costras superficiales pueden caer aludes de fusión de forma natural a nuestro paso, esquiando, que llegarán a tamaño 1 (pequeño), sin capacidad para enterrarnos. El terreno más afectado por aludes de fusión son las salidas de puntos oscuros (rocas y árboles) y las canales a solanas. En umbrías elevadas, en el límite norte del sector, podemos encontrar, localmente, alguna placa antigua que con una carga fuerte, podría acabar cayendo, y generar aludes de tamaño 2 (medio), con capacidad de enterrar un montañero. Los lugares delicados están bajo collados y cordales, por encima de 2.500 m y también en las orientaciones. El lunes habrá nevado, con viento de norte, y se formarán placas nuevas a sotavento (S y E), pequeñas. Habrá que vigilar con los resbalones a primera hora, por la presencia de costras duras.

Distribución del manto nivoso

En umbrías hay nieve por encima de 1.400-1.500 m, y en las solanas está presente por encima de 1.700 m. Los espesores, aunque irregulares, rondan los 85-105 cm en cotas medias. Son grosores por encima de los habituales para la época.

Tendencia para las próximas 48-72h

Las placas nuevas se mantendrán reactivas. Peligro: SIN CAMBIOS o EN LEVE ASCENSO.

El próximo boletín será emitido el día 2026-03-23

5 MUY FUERTE	4 FUERTE	3 NOTABLE	2 LIMITADO	1 DÉBIL

EAWS EUROPEAN AVALANCHE WARNING SERVICES

ICGC Institut Cartogràfic i Geològic de Catalunya

Servei Meteorològic de Catalunya

Boletín de peligro de aludes
Vessant Nord Cadí-Moixeró
Del 21/03/2026 al 23/03/2026

(Válido fuera pistas de esquí y zonas no controladas)

DÉBIL (1), LIMITADO (2), durante las horas centrales del día por encima de los 2.200 m.

Situación primaria

Nieve húmeda

Distribución

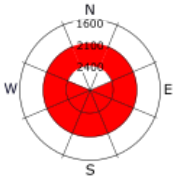

Tamaño

Origen

Tendencia

Estado del manto nivoso

El domingo se espera un manto rehelado y endurecido a primera hora. Con el avance de la jornada, el humedecimiento superficial del manto ablandará las costras y pueden caer aludes pequeños de fusión de forma natural y también a nuestro paso, esquiando, sin capacidad para enterrar a una persona, excepto en terreno trampa donde habrá que evitar pasar mientras la nieve no regele. El terreno más afectado por aludes de fusión son las zonas de salida de puntos oscuros como rocas y árboles. El lunes habrá nevado, con viento en altura, que podrá mover y transportar la nieve reciente, con la formación de alguna pequeña placa de viento. Habrá que vigilar los resbalones, sobre todo en lo alto de las Canals y bajo collados y crestas más elevadas.

Distribución del manto nivoso

En umbrías hay presencia discontinua de nieve por encima de 1.600 m y es esquiable por encima de 1.900 m. Los grosores están alrededor de 160-180 cm a 2.200 m. Estos valores son muy excedentarios para la época del año.

Tendencia para las próximas 48-72h

Se podrán formar algunas placas, pequeñas, bajo collados o cordales, con los chubascos con viento previstos. Peligro: SIN CAMBIOS o EN LEVE ASCENSO.

El próximo boletín será emitido el día 2026-03-23

5 MUY FUERTE	4 FUERTE	3 NOTABLE	2 LIMITADO	1 DÉBIL

EAWS EUROPEAN AVALANCHE WARNING SERVICES

ICGC Institut Cartogràfic i Geològic de Catalunya

Servei Meteorològic de Catalunya

Boletín de peligro de aludes Prepirineu
Del 21/03/2026 al 23/03/2026

(Válido fuera pistas de esquí y zonas no controladas)

DÉBIL (1).

Situación primaria

Nieve húmeda

Distribución

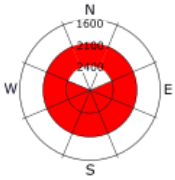

Tamaño

Origen

Tendencia

Estado del manto nivoso

El manto se muestra bastante asentado y endurecido internamente, con presencia de costras duras, grano fino y algunas formas mixtas. Para el domingo se espera rehielo, después de una madrugada serena, y el manto se mostrará asentado. Con el humedecimiento, a partir de mediodía, debido a la transformación de la nieve por la radiación solar, no se descarta la caída de bolas o de algún alud húmedo, pequeño, que no tendrá capacidad para enterrar a una persona, excepto en terreno trampa donde habrá que evitar pasar mientras la nieve no rehiele. Las orientaciones más sensibles a la caída de aludes de nieve húmeda son las orientadas a Este, Sur y Oeste, así como las umbrías de cota media. El lunes habrá nevado un poco, con viento en altura, que podrá mover y transportar la nieve reciente, con la formación de alguna placa de viento, pequeña, bajo los collados y crestas más elevadas. Habrá que vigilar con los resbalones, sobre todo por la mañana.

Distribución del manto nivoso

En umbrías hay nieve por encima de 1700 m. En solanas la nieve está presente por encima de 1.900 m. Los espesores, aunque irregulares, rondan los 65-85 cm en cotas medias.

Tendencia para las próximas 48-72h

Seguiremos con un manto asentado y endurecido. Los chubascos no cambiarán las condiciones previstas. Peligro: SIN CAMBIOS.

El próximo boletín será emitido el día 2026-03-23

5 MUY FUERTE	4 FUERTE	3 NOTABLE	2 LIMITADO	1 DÉBIL

EAWS EUROPEAN AVALANCHE WARNING SERVICES

ICGC Institut Cartogràfic i Geològic de Catalunya

Servei Meteorològic de Catalunya

Boletín de peligro de aludes Ter-Freser
Del 21/03/2026 al 23/03/2026

(Válido fuera pistas de esquí y zonas no controladas)

LIMITADO (2), durante las horas centrales del día y el lunes. DÉBIL (1), el domingo por la mañana.

Situación primaria

Nieve húmeda

Distribución

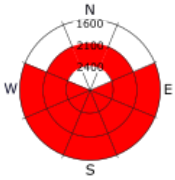

Tamaño

Origen

Tendencia

Situación secundaria

Nieve venteada

Distribución

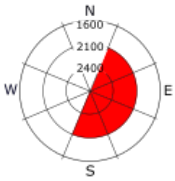

Tamaño

Origen

Tendencia

Estado del manto nivoso

El domingo seguiremos con una dinámica primaveral. A primera hora el manto se mostrará asentado y endurecido superficialmente a causa del rehielo, pero el humedecimiento avanzará con el paso de las horas debido a la radiación solar. En solanas o en umbrías de cota media, en terreno con fuerte inclinación, pueden caer aludes naturales de fusión de forma natural o en nuestro paso esquiando que llegarán a tamaño 1(pequeño), sin capacidad para enterrar a una persona. Entre el domingo por la tarde y el lunes, con la nevada prevista (10 cm) con viento de norte, se formarán placas nuevas a sotavento (S y E), que serán reactivas. El lunes se esperan aludes naturales ya nuestro paso, en forma de placa de viento, que pueden llegar, por lo general, a tamaño 1 (pequeño), y localmente, hasta tamaño 2 (medio), con capacidad de enterrar a una persona. Habrá que vigilar con los resbalones a primera hora del domingo por la presencia de costras duras.

Distribución del manto nivoso

Hay nieve en el suelo por encima de 1.700 m. El manto es esquiable a umbrías a partir de unos 1.700 m. Los grosores son muy excedentarios para la época del año y en lugares no afectados por el viento oscilan entre 85-105 cm a unos 2.000 m y más de 150 cm por encima de 2.400 m.

Tendencia para las próximas 48-72h

Las placas nuevas se mantendrán reactivas. Peligro: EN LEVE ASCENSO.

El próximo boletín será emitido el día 2026-03-23

5 MUY FUERTE	4 FUERTE	3 NOTABLE	2 LIMITADO	1 DÉBIL

EAWS EUROPEAN AVALANCHE WARNING SERVICES