APPENNINO UMBRO-MARCHIGIANO SETTENTRIONALE

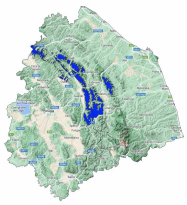

Bollettino Valanghe N. 155/2026 del 21/03/2026 ore 14.00
Validità 48 ore prossima emissione 22/03/2026

A cura del Servizio METEOMONT dell'ARMA dei CARABINIERI
In collaborazione con Servizio Meteorologico dell'Aeronautica militare

SITUAZIONE alle 14:00 del 21/03/2026

SITUAZIONE TIPO: nessuna situazione tipo evidente.

Quota neve (mslm)	Nord	Sud
	1400	1600

Altezza Neve (cm)	Neve al suolo	Neve Fresca	Quota (mslm)
	005	000	1450

VALANGHE OSSERVATE: Nessuna valanga.

PREVISIONI 22/03/2026

GRADO DI PERICOLO: DEBOLE 1

SITUAZIONE TIPO: nessuna situazione tipo evidente.



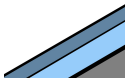

MANTO NEVOSO: La stabilità del manto nevoso è buona su pochissimi punti (aree) per isolati pendii, possibili valanghe di dimensioni piccole.

AVVERTENZE

Meteomont rammenta ARTVA, pala e sonda sempre al seguito.

SCALA EUROPEA DEL GRADO DI PERICOLO VALANGHE

LEGENDA PROBLEMA

Bollettino realizzato su scala sinottica-regionale (standard EAWS). La sua valutazione non può escludere in alcun modo la necessità di una seria e capace valutazione locale del pericolo (singolo pendio) che può essere anche sensibilmente diverso. Le previsioni meteorologiche sono relative all'orario UTC (per l'Italia +1 in inverno e +2 in estate).

MINISTERO DELLA DIFESA

meteomont
Servizio Nazionale di previsione neve e valanghe

EAWS EUROPEAN AVALANCHE WARNING SERVICES

CARABINIERI

In collaborazione con: MARCHE

APPENNINO UMBRO-MARCHIGIANO SETTENTRIONALE

PREVISIONE METEO

Quota		22/03/2026 h6:00	22/03/2026 h12:00	22/03/2026 h18:00
1000	Venti	03 Nodi da N-Est	03 Nodi da Est	03 Nodi da Est
	Temperature	+03 °C	+05 °C	+04 °C
	Temp.percepita	2 °C	4 °C	3 °C
2000	Venti	05 Nodi da Est	01 Nodi da Sud	01 Nodi da Nord
	Temperature	-04 °C	-04 °C	-02 °C
	Temp.percepita	-8 °C	-4 °C	-2 °C
3000	Venti	02 Nodi da Nord	02 nodi da N-Ovest	05 nodi da N-Ovest
	Temperature	-11 °C	-10 °C	-10 °C
	Temp.percepita	-11 °C	-10 °C	-15 °C
Zero termico		1100-1300 m.	1400-1600 m.	1400-1600 m.
Fenomeno		—	—	—
Stato del cielo				

LEGENDA FENOMENI

— Assenza Fenomeni · Nebbia · Foschia · Pioggia debole · Pioggia moderata · Pioggia forte · Temporali

Nevicata debole · Nevicata moderata · Nevicata forte

STATO DEL CIELO

Sereno · Poco nuvoloso · Nuvoloso · Molto nuvoloso · Coperto

Parametri meteonivometrici registrati presso i campi di rilevamento il 21/03/2026.

Località	Comune	Quota (m.s.l.m.)	Altezza neve (cm)	Neve caduta nelle 24 ore (cm)	Temp. Min (°C)	Temp. Max (°C)	Condizioni del tempo
MONTE ACUTO	Frontone (PU)	1450	6	0	-2	+1	Assenza di precipitazioni

(*) Rilievi fuori campo

L'INFORMAZIONE E' PREVENZIONE - LEGGI L'ATTUALE GRADO DI PERICOLO VALANGHE!

IL CAPO DEL CENTRO NAZIONALE METEOMONT
(Ten. Col. RFI Emanuela Gini)
FIRMA AUTOGRAFA OMESSA AI SENSI
DELL'ART.3 DEL D.LGS N.39/1993

Bollettino realizzato su scala sinottica-regionale (standard EAWS). La sua valutazione non può escludere in alcun modo la necessità di una seria e capace valutazione locale del pericolo (singolo pendio) che può essere anche sensibilmente diverso. Le previsioni meteorologiche sono relative all'orario UTC (per l'Italia +1 in inverno e +2 in estate).