MINISTERO DELLA DIFESA

meteomont Servizio Nazionale di previsione neve e valanghe

EAWS EUROPEAN AVALANCHE WARNING SERVICES

CARABINIERI

In collaborazione con: MARCHE

APPENNINO UMBRO-MARCHIG. MERID. - MONTI SIBILLINI

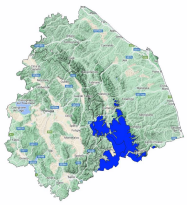

Bollettino Valanghe N. 333/2026 del 20/03/2026 ore 14.00
Validità 48 ore prossima emissione 21/03/2026

A cura del Servizio METEOMONT dell'ARMA dei CARABINIERI
In collaborazione con Servizio Meteorologico dell'Aeronautica militare

SITUAZIONE alle 14:00 del 20/03/2026

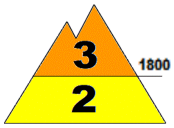

SITUAZIONE TIPO: neve a debole coesione e vento.



SITUAZIONE TIPO: neve a debole coesione e vento.

Quota neve (mslm)	Nord	Sud
	1100 - 1200	1100 - 1400

Altezza Neve (cm)	Neve al suolo	Neve Fresca	Quota (mslm)
	050-140	000	2000
	010 - 030	000	1500

VALANGHE OSSERVATE: Alcune valanghe di medie dimensioni, Valanghe non accertabili.

PREVISIONI 21/03/2026

GRADO DI PERICOLO: MARCATO 3

SITUAZIONE TIPO: neve a debole coesione e vento.

SITUAZIONE TIPO: neve a debole coesione e vento.

MANTO NEVOSO: La stabilità del manto nevoso è scarsa su molti punti (aree) per tutte le esposizioni al di sopra di 1800 mslm, possibili valanghe di dimensioni grandi.
La stabilità del manto nevoso è scarsa su alcuni punti (aree) per tutte le esposizioni al di sotto di 1800 mslm, possibili valanghe di dimensioni medie.

AVVERTENZE

In considerazione dei recenti apporti di neve fresca, è richiesta un'ottima valutazione locale della stabilità ed individuazione dell'itinerario.

SCALA EUROPEA DEL GRADO DI PERICOLO VALANGHE

LEGENDA PROBLEMA

Bollettino realizzato su scala sinottica-regionale (standard EAWS). La sua valutazione non può escludere in alcun modo la necessità di una seria e capace valutazione locale del pericolo (singolo pendio) che può essere anche sensibilmente diverso. Le previsioni meteorologiche sono relative all'orario UTC (per l'Italia +1 in inverno e +2 in estate).

MINISTERO DELLA DIFESA

meteomont
Servizio Nazionale di previsione neve e valanghe

EAWS EUROPEAN AVALANCHE WARNING SERVICES

CARABINIERI

In collaborazione con: MARCHE

APPENNINO UMBRO-MARCHIG. MERID. - MONTI SIBILLINI

PREVISIONE METEO

Quota		21/03/2026 h6:00	21/03/2026 h12:00	21/03/2026 h18:00
1000	Venti	01 Nodi da N-Est	02 Nodi da N-Est	01 Nodi da Est
	Temperature	-03 °C	+00 °C	-01 °C
	Temp.percepita	-3 °C	0 °C	-1 °C
2000	Venti	05 Nodi da N-Est	03 Nodi da N-Est	03 Nodi da Est
	Temperature	-05 °C	-05 °C	-05 °C
	Temp.percepita	-9 °C	-8 °C	-8 °C
3000	Venti	05 Nodi da N-Est	01 Nodi da S-Ovest	03 Nodi da Ovest
	Temperature	-09 °C	-09 °C	-10 °C
	Temp.percepita	-14 °C	-9 °C	-13 °C
Zero termico		1000-1200 m.	1400-1600 m.	1300-1500 m.
Fenomeno		—	—	—
Stato del cielo				

LEGENDA FENOMENI

— Assenza Fenomeni · Nebbia · Foschia · Pioggia debole · Pioggia moderata · Pioggia forte · Temporali

Nevicata debole · Nevicata moderata · Nevicata forte

STATO DEL CIELO

Sereno · Poco nuvoloso · Nuvoloso · Molto nuvoloso · Coperto

Parametri meteonivometrici registrati presso i campi di rilevamento il 20/03/2026.

Località	Comune	Quota (m.s.l.m.)	Altezza neve (cm)	Neve caduta nelle 24 ore (cm)	Temp. Min (°C)	Temp. Max (°C)	Condizioni del tempo
FORCA DI GUALDO *	Castelsantangelo sul Nera (MC)	1496	30	0	N.P.	N.P.	Assenza di precipitazioni
LA VALLETTA	Bolognola (MC)	1352	32	0	-2	+6	Assenza di precipitazioni
COLLE	Montegallo (AP)	1036	12	0	-1	+8	Rovescio a grandine o neve arrotondata
PARCO GUARNIERI	Montemonaco (AP)	980	Tracce di neve	0	+1	+7	Assenza di precipitazioni
RIFUGIO PERUGIA	Norcia (PG)	1500	12	2	N.P.	N.P.	Scaccianeve (tormenta) sulla stazione
BELVEDERE DI FRONTIGNANO *	Ussita (MC)	1602	30	0	N.P.	N.P.	Nevicata debole intermittente
MONTE CORNACCIONE *	Castelsantangelo sul Nera (MC)	1862	68	N.P.	N.P.	N.P.	Nevicata debole intermittente

(*) Rilievi fuori campo

L'INFORMAZIONE E' PREVENZIONE - LEGGI L'ATTUALE GRADO DI PERICOLO VALANGHE!

IL CAPO DEL CENTRO NAZIONALE METEOMONT
(Ten. Col. RFI Emanuela Gini)
FIRMA AUTOGRAFA OMESSA AI SENSI
DELL'ART.3 DEL D.LGS N.39/1993

Bollettino realizzato su scala sinottica-regionale (standard EAWS). La sua valutazione non può escludere in alcun modo la necessità di una seria e capace valutazione locale del pericolo (singolo pendio) che può essere anche sensibilmente diverso. Le previsioni meteorologiche sono relative all'orario UTC (per l'Italia +1 in inverno e +2 in estate).