Bulletin d'estimation du risque d'avalanche
(valable en dehors des pistes balisées et ouvertes)

MASSIF : Haute-Tarentaise

Rédigé le samedi 21 mars 2026 à 15h

Estimation des risques pour le : DIMANCHE 22 MARS

PETITE CHUTE DE NEIGE SUR UN MANTEAU GLOBALEMENT BIEN STABILISÉ

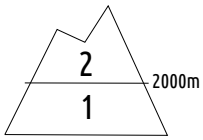

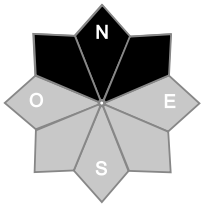

Au-dessus de 2000m indice de risque limité, plus bas indice faible.

Départs spontanés : Peu probable

Déclenchements provoqués : Quelques plaques à vent dans les versants Nord d'altitude

Indices de risque : 5 très fort - 4 fort - 3 marqué - 2 limité - 1 faible -- En noir : les pentes les plus dangereuses

Stabilité du manteau neigeux

Situation avalancheuse typique : neige ventée

Déclenchements provoqués : Quelques plaques restent présentes en versant Nord au-dessus de 2000 m, elles sont très localement encore facilement déclenchable par un skieur. Elles sont souvent dures et se retrouvent derrière les ruptures de terrain, en milieu, voire aux pieds des pentes. Le haut des pentes étant souvent décapé par le vent.
Observables : accumulation de neige ventée derrière une rupture de pente, test de stabilité, fissures devant les skis.

Les 5/10 cm de fraiche attendus en cours de journée le plus souvent sans vent ne viendront à priori pas créer de nouvelles instabilités. Sauf éventuellement en cours d'après midi avec le foehn qui va se lever et qui pourrait créer de nouvelles petites plaques peu épaisses

Départs spontanés : Peu probable hormis quelques rares petites purges de neige fraiche l'après midi dans les rares pentes très raides et rocheuses qui verront assez de soleil pour chauffer suffisamment la neige fraiche.

Qualité de la neige

Enneigement : Encore un peu au dessus de la moyenne, sauf aux plus basses altitudes où les hauteurs de neige sont tout juste correctes pour la saison.

Limite skiable : 1300m au mieux en Nord. Plutôt 1600 m en sud pas trop raide.

Qualité de la neige :
Léger saupoudrage dimanche matin devenant un peu plus conséquent (5/10cm) en fin de matinée.
Ces quelques cm de fraiche reposant sur un manteau souvent dur: croute de regel portante en Sud, croute parfois cassante en Est et Ouest et neige venté le plus souvent cartonnée en Nord.

Aperçu météo pour le dimanche 22 mars

	nuit	matin	après-midi	soir

Petite chute de neige nuit et matinée, rares trouées l'après midi avec le foehn (40/50 km/h) qui se lève en fond de vallée de Tarentaise

Pluie-Neige	1 400 m	1 200 m	1 200 m	
Iso 0 °C	1 800 m	1 500 m	1 800 m	1 500 m
Vent 2500 m	↗ 10 km/h	← 15 km/h	↙ 25 km/h	↙ 20 km/h
Vent 3500 m	↘ 20 km/h	↖ 25 km/h	↖ 35 km/h	← 30 km/h

Épaisseur de neige hors-piste

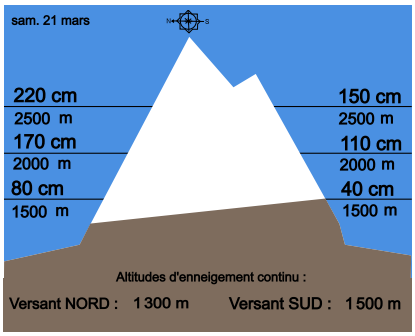

Précipitations à 1800 m

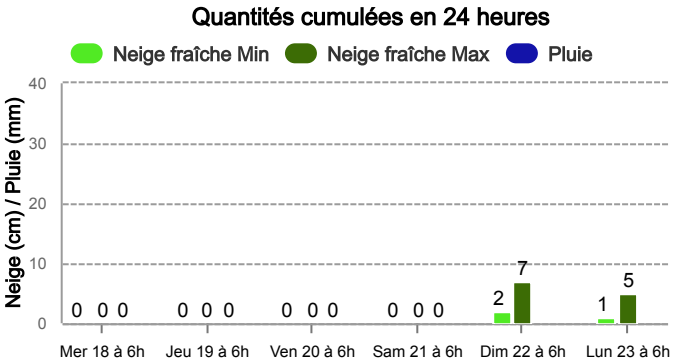

Tendance du lundi 23 mars

Indice de risque limité

Belle journée ensoleillée. Purges de neige fraiche s'humidifiant dans les faces raides au soleil, rares plaques toujours en place en versant ombragé.

Pour consulter la vigilance en cours, veuillez vous rendre sur le site https://vigilance.meteofrance.fr/fr

Météo-France - 73 avenue de Paris, 94165 Saint-Mandé cedex - Contact : contact@meteo.fr

Rédigé par Météo-France avec la contribution des observateurs du réseau nivo-météorologiques. Partenariat : ANMSM (Maires de Stations de Montagne), DSF (Domaines Skiables de France), ADSP (Directeurs de Pistes et de la Sécurité des Stations de Sports d'Hiver) et autres acteurs de la montagne.

Bulletin neige & avalanches par téléphone au
0 892 68 10 20 Service 0,35 € / min + prix appel

RÉPUBLIQUE FRANÇAISE
Liberté Égalité Fraternité

METEO FRANCE
À VOS CÔTÉS, DANS UN CLIMAT QUI CHANGE

Bulletin d'estimation du risque d'avalanche

(valable en dehors des pistes balisées et ouvertes)

MASSIF : Haute-Tarentaise

Rédigé le samedi 21 mars 2026 à 15h

Conditions nivo-météo des 7 derniers jours

	dim. 15/03				lun. 16/03				mar. 17/03				mer. 18/03				jeu. 19/03				ven. 20/03				sam. 21/03			
	03h	09h	15h	21h	03h	09h	15h	21h	03h	09h	15h	21h	03h	09h	15h	21h	03h	09h	15h	21h	03h	09h	15h	21h	03h	09h	15h	21h
Météo																												
Vent (km/h)	20	40	20	20	25	40	40	25	25	30	30	30	35	45	60	55	40	20	15	15	30	35	15	15	20	15	20	20
à 3500m																												
Vent (km/h)	10	30	15	10	10	20	30	15	15	15	15	15	20	30	50	40	30	15	10	10	10	10	5	0	5	10	10	10
à 2500m																												

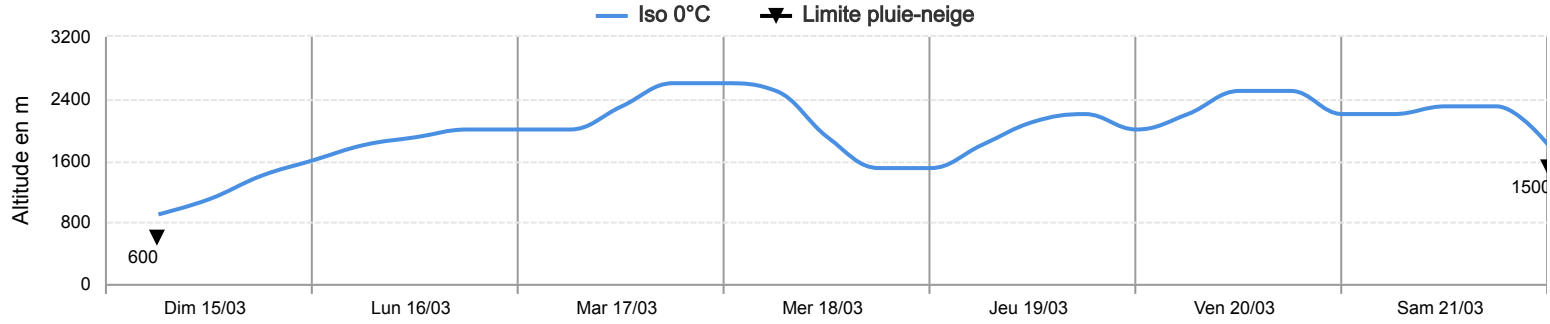

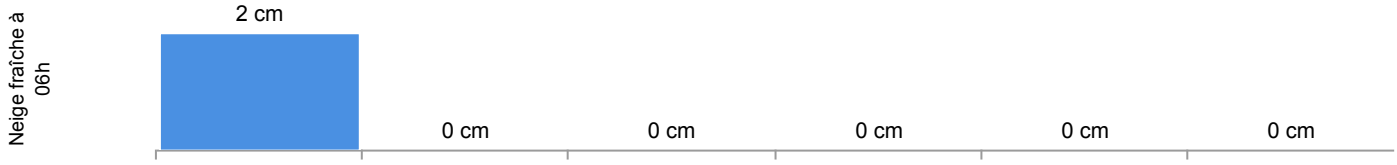

Risque d'avalanche	dim. 15/03	lun. 16/03	mar. 17/03	mer. 18/03	jeu. 19/03	ven. 20/03	sam. 21/03
	3	3	2	3	3	2	2

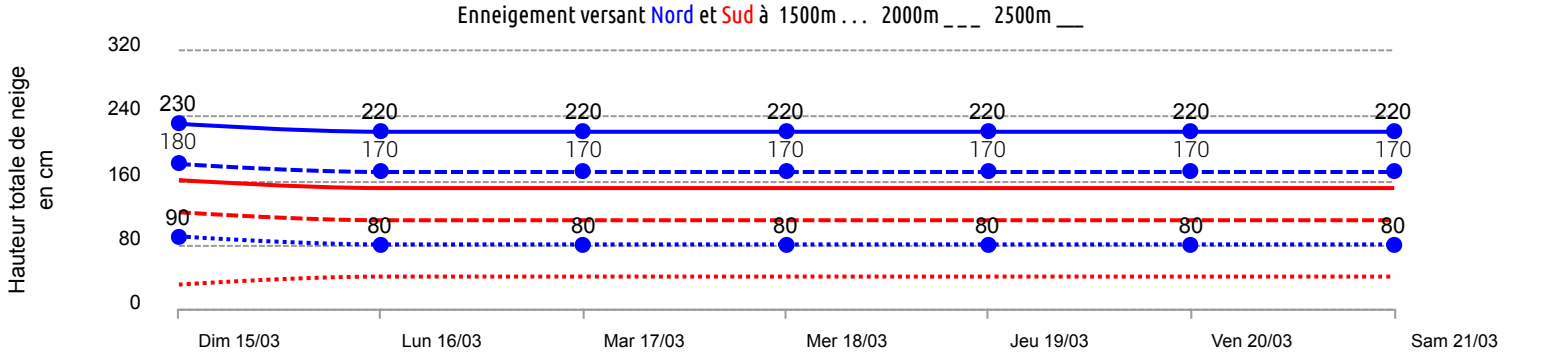

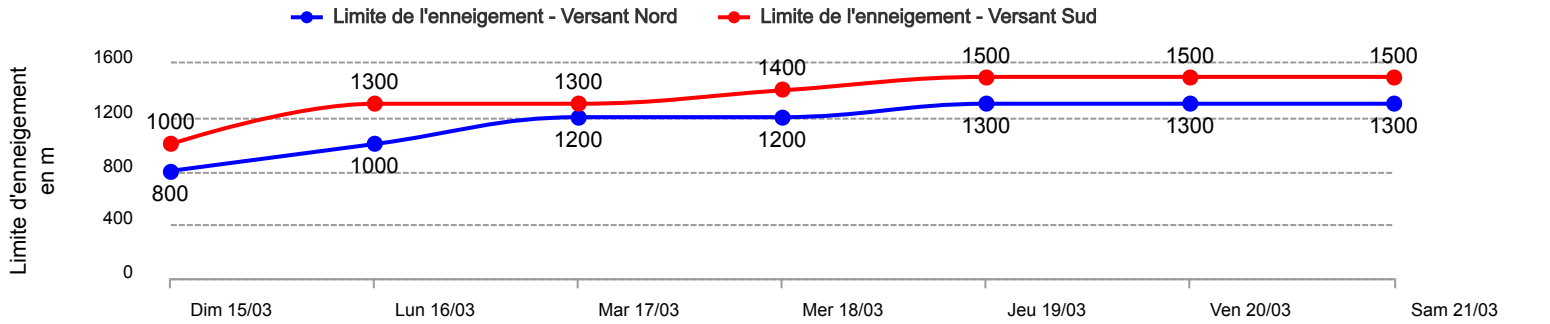

Pour consulter la vigilance en cours, veuillez vous rendre sur le site https://vigilance.meteofrance.fr/fr

Météo-France - 73 avenue de Paris, 94165 Saint-Mandé cedex - Contact : contact@meteo.fr

Rédigé par Météo-France avec la contribution des observateurs du réseau nivo-météorologiques. Partenariat : ANMSM (Maires de Stations de Montagne), DSF (Domaines Skiables de France), ADSP (Directeurs de Pistes et de la Sécurité des Stations de Sports d'Hiver) et autres acteurs de la montagne.

Bulletin neige & avalanches par téléphone au
0 892 68 10 20 Service 0,35 € / min + prix appel