Bulletin d'estimation du risque d'avalanche
(valable en dehors des pistes balisées et ouvertes)

MASSIF : Maurienne

Rédigé le samedi 21 mars 2026 à 15h

Estimation des risques pour le : DIMANCHE 22 MARS

MANTEAU PRINTANIER EN SUD, TRÈS TRAVAILLÉ PAR LE VENT EN NORD AVEC QUELQUES INSTABILITÉS

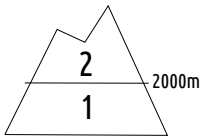

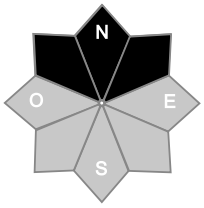

Au-dessus de 2000m indice de risque limité, plus bas indice faible.

Départs spontanés : Peu probable

Déclenchements provoqués : Quelques plaques à vent dans les versants Nord d'altitude

Indices de risque : 5 très fort - 4 fort - 3 marqué - 2 limité - 1 faible -- En noir : les pentes les plus dangereuses

Stabilité du manteau neigeux

Situation avalancheuse typique : neige ventée

Déclenchements provoqués : Quelques plaques à vent en versant Nord au-dessus de 1600 m, quelques fois facilement déclenchable par un skieur. Elles sont souvent d'aspect dure et se retrouvent proche des crêtes, quelques fois jusqu'en milieu de pentes.
Observables : accumulation de neige ventée derrière une rupture de pente, test de stabilité, fissures devant les skis.

Départs spontanés : Peu probable

Qualité de la neige

Enneigement : Encore un peu au dessus de la moyenne, sauf aux plus basses altitudes où les hauteurs de neige sont tout juste correctes pour la saison.

Limite skiable : 1300m au mieux en Nord. Plutôt 1600 m en sud pas trop raide.

Qualité de la neige : En Sud, neige de printemps, restant dure toute la journée.
En Nord au-dessus de 1600 m, neige sèche travaillée par le vent ou cartonnée proche des crêtes. Dans les secteurs peu ventés, la neige est encore poudreuse.
En versant Ouest et Est, neige croutée cassante.

Ce manteau plutôt dur/crouté sera légèrement saupoudré de quelques cm de fraiche en cours de journée avec les petites chutes attendues.

Aperçu météo pour le dimanche 22 mars

	nuit	matin	après-midi	soir
	Couvert en matinée avec quelques averses de neige en cours de matinée et après midi. Vent restant globalement calme.			
Pluie-Neige	1 400 m	1 200 m	1 200 m	
Iso 0 °C	1 800 m	1 700 m	1 800 m	1 600 m
Vent 2000 m	↑ 10 km/h	↖ 15 km/h	↑ 20 km/h	↖ 15 km/h
Vent 3000 m	↘ 30 km/h	↖ 30 km/h	↖ 30 km/h	↖ 25 km/h

Épaisseur de neige hors-piste

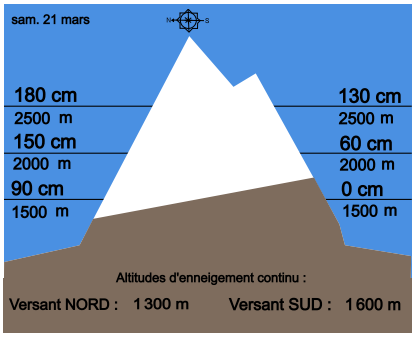

Précipitations à 1800 m

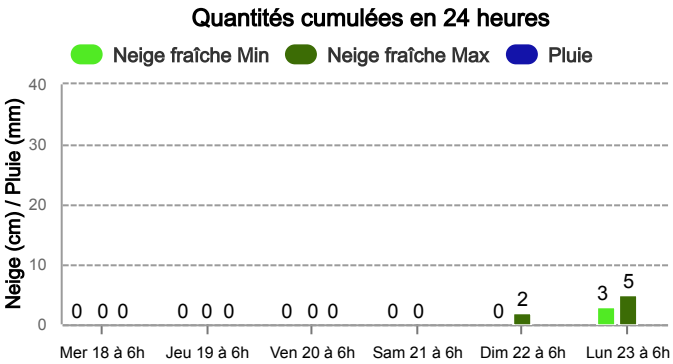

Tendance du lundi 23 mars

Indice de risque limité

Belle journée ensoleillée. Purges de neige fraiche s'humidifiant dans les faces raides au soleil, rares plaques toujours en place en versant ombragé.

Pour consulter la vigilance en cours, veuillez vous rendre sur le site https://vigilance.meteofrance.fr/fr

Météo-France - 73 avenue de Paris, 94165 Saint-Mandé cedex - Contact : contact@meteo.fr

Rédigé par Météo-France avec la contribution des observateurs du réseau nivo-météorologiques. Partenariat : ANMSM (Maires de Stations de Montagne), DSF (Domaines Skiables de France), ADSP (Directeurs de Pistes et de la Sécurité des Stations de Sports d'Hiver) et autres acteurs de la montagne.

Bulletin neige & avalanches par téléphone au **0 892 68 10 20** Service 0,35 € / min + prix appel

RÉPUBLIQUE FRANÇAISE
Liberté Égalité Fraternité

METEO FRANCE
À VOS CÔTÉS, DANS UN CLIMAT QUI CHANGE

Bulletin d'estimation du risque d'avalanche
(valable en dehors des pistes balisées et ouvertes)
MASSIF : Maurienne

Rédigé le samedi 21 mars 2026 à 15h

Conditions nivo-météo des 7 derniers jours

	dim. 15/03				lun. 16/03				mar. 17/03				mer. 18/03				jeu. 19/03				ven. 20/03				sam. 21/03			
	03h	09h	15h	21h	03h	09h	15h	21h	03h	09h	15h	21h	03h	09h	15h	21h	03h	09h	15h	21h	03h	09h	15h	21h	03h	09h	15h	21h
Météo																												
Vent (km/h)	35	45	20	20	30	40	40	30	20	30	30	20	20	35	60	50	35	20	20	20	15	15	10	5	15	20	25	30
à 3000m																												
Vent (km/h)	25	30	15	5	10	20	30	10	10	15	15	10	10	20	40	35	20	10	10	10	5	5	5	0	5	5	15	10
à 2000m																												

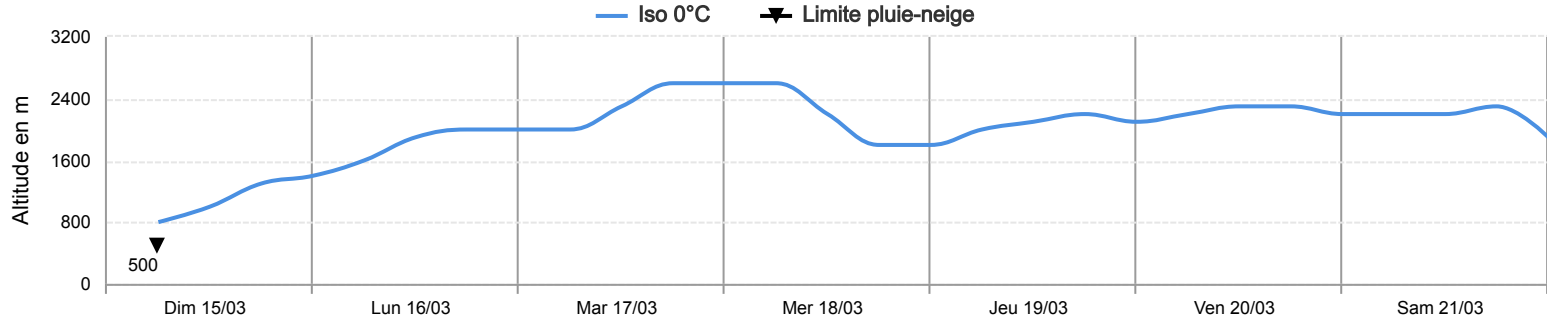

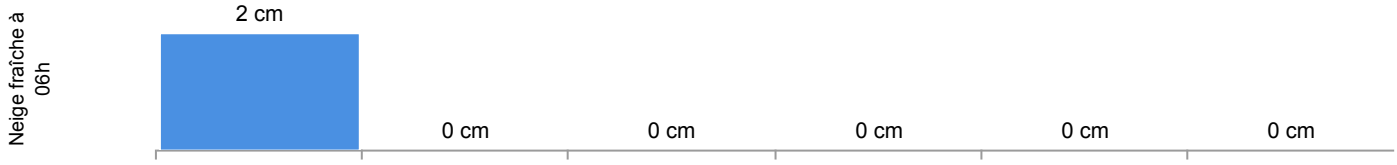

Risque d'avalanche	dim. 15/03	lun. 16/03	mar. 17/03	mer. 18/03	jeu. 19/03	ven. 20/03	sam. 21/03
	3	3	2	3	3	2	2

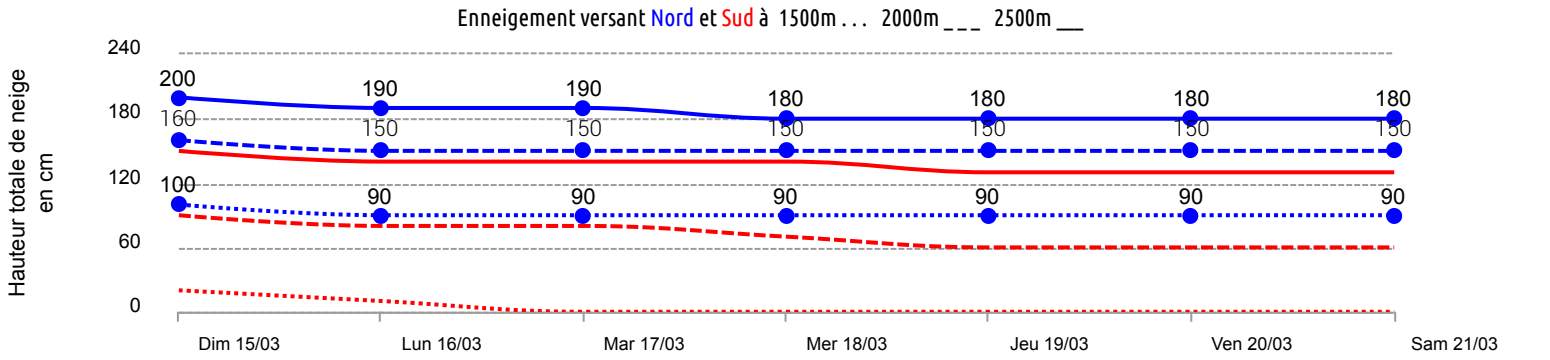

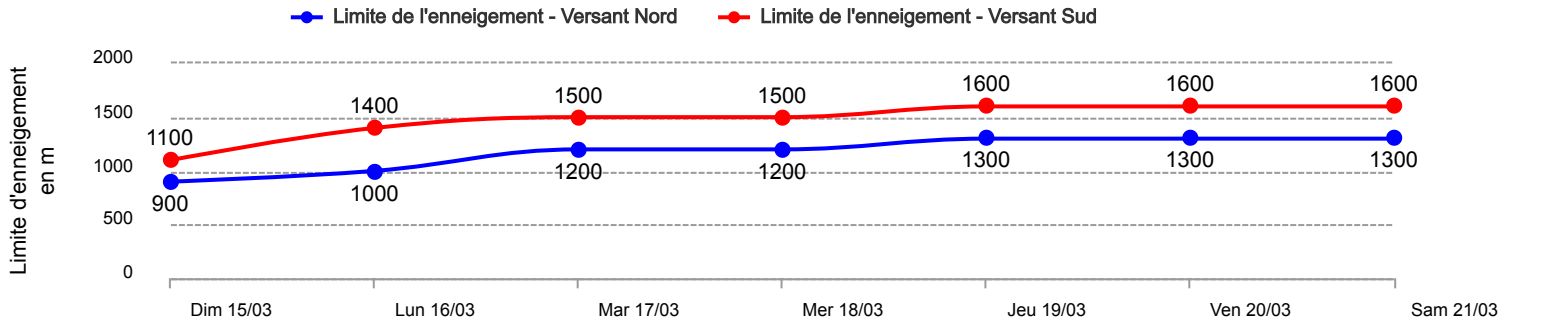

Pour consulter la vigilance en cours, veuillez vous rendre sur le site https://vigilance.meteofrance.fr/fr

Météo-France - 73 avenue de Paris, 94165 Saint-Mandé cedex - Contact : contact@meteo.fr

Rédigé par Météo-France avec la contribution des observateurs du réseau nivo-météorologiques. Partenariat : ANMSM (Maires de Stations de Montagne), DSF (Domaines Skiables de France), ADSP (Directeurs de Pistes et de la Sécurité des Stations de Sports d'Hiver) et autres acteurs de la montagne.

Bulletin neige & avalanches par téléphone au
0 892 68 10 20 Service 0,35 € / min + prix appel