Bulletin d'estimation du risque d'avalanche
(valable en dehors des pistes balisées et ouvertes)

MASSIF : Renoso Incudine

Rédigé le samedi 21 mars 2026 à 15h

Estimation des risques pour le : DIMANCHE 22 MARS

QUELQUES DÉPARTS PENDANT LES NOUVELLES CHUTES DE NEIGE, PERSISTANCE D'INSTABILITÉS EN ALTITUDE DANS LA NEIGE RÉCENTE VENTÉE.

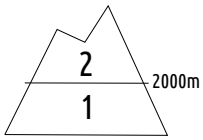

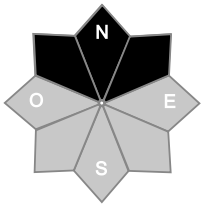

Au-dessus de 2000m indice de risque limité, plus bas indice faible.

Départs spontanés : Coulées de neige fraîche pendant les chutes de neige, voire quelques avalanches de taille moyenne

Déclenchements provoqués : Plaques à vent difficilement sollicitables, encore présentes en altitude au-dessus de 2000 m

Indices de risque : 5 très fort - 4 fort - 3 marqué - 2 limité - 1 faible -- En noir : les pentes les plus dangereuses

Stabilité du manteau neigeux

Situation avalancheuse typique : neige ventée

Déclenchements provoqués : De rares plaques sont encore en place suite aux dernières chutes de neige et au transport engendré par le vent. Elles se sont généralement bien tassées dans les versants ensoleillés mais restent plus fréquentes dans les versants ne voyant que peu le soleil, au-dessus de 2000 m environ, là où le manteau neigeux n'est pas encore printanier. Certaines instabilités peuvent encore céder au passage d'un skieur dans les pentes raides orientées Nord-Ouest à Nord-Est, parfois cachées sous une fine couche de neige fraîche. Elles peuvent engendrer des avalanches de taille petite à moyenne (taille 1 à 2).
En dessous de 2000 m, la neige fraîche repose sur une sous-couche regelée et plus stable.
Départs spontanés : À partir de dimanche après-midi, des chutes de neige se produisent sous forme d'averses. Dans certains secteurs concernés par des intensités un peu plus marquées ou par une succession d'averses de neige, des coulées se déclenchent dans les pentes raides, voire quelques avalanches de taille moyenne (taille 1 à 2).
Autres : Nombreuses surfaces dures et glacées, pouvant être recouvertes de quelques centimètres de neige fraîche.
Présence de corniches parfois volumineuses, dont certaines commencent à se détacher (apparition de fissures).

Qualité de la neige

Qualification de l'enneigement : L'enneigement est excellent pour la saison au-dessus de 1600 m. Au Val d'Ese, on relève 2m00 de neige à 1800 m. À Ghisoni Capanelle, on mesure environ 3m00 dans les combes abritées.
Limite d'enneigement skiable : 1500 à 1600 m selon le versant.
État de la neige : La neige s'humidifie en surface dans les pentes SE à SO bien exposées au soleil, surtout en dessous de 2000m. Plus haut, et en pentes plus froides NE à NO, elle reste plus froide et assez légère, ou bien densifiée ou durcie sur les zones qui ont été exposées au Grecale. Le net refroidissement permet une consolidation par regel des couches de neige humide. Les croûtes épaisses et les surfaces dures sont très fréquentes. À noter également la présence de corniches parfois volumineuses.

Aperçu météo pour le dimanche 22 mars

	nuit	matin	après-midi	soir
Pluie-Neige			1 200 m	1 100 m
Iso 0 °C	1 600 m	1 600 m	1 600 m	1 500 m
Vent 1500 m	5 km/h	5 km/h	5 km/h	5 km/h
Vent 2000 m	10 km/h	10 km/h	10 km/h	10 km/h

Dimanche à partir de la mi-journée, sous un ciel couvert, des averses de neige se déclenchent, d'intensité faible à modéré. Les quantités attendues sont très hétérogènes.

Épaisseur de neige hors-piste

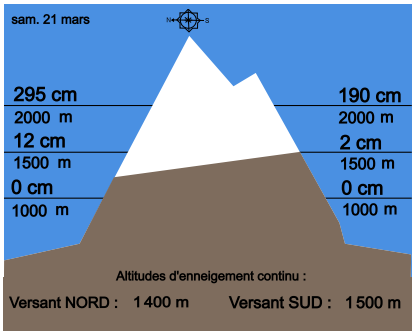

Précipitations à 1800 m

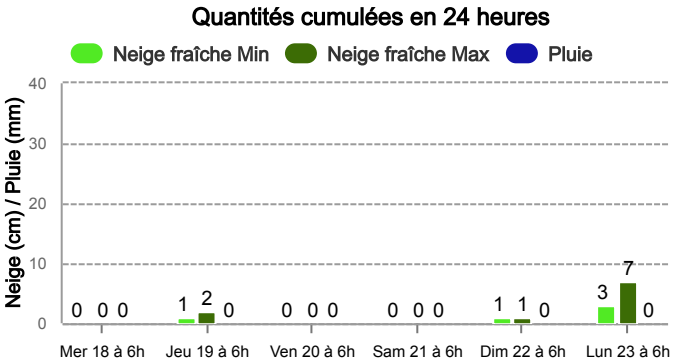

Tendance du lundi 23 mars

Indice de risque limité

Avec des températures froides, persistance de plaques localement sensibles en versants ombragés. L'après-midi, de nouvelles averses de neige peuvent occasionner quelques départs spontanés.

Pour consulter la vigilance en cours, veuillez vous rendre sur le site https://vigilance.meteofrance.fr/fr

Météo-France - 73 avenue de Paris, 94165 Saint-Mandé cedex - Contact : contact@meteo.fr

Rédigé par Météo-France avec la contribution des observateurs du réseau nivo-météorologiques. Partenariat : ANMSM (Maires de Stations de Montagne), DSF (Domaines Skiables de France), ADSP (Directeurs de Pistes et de la Sécurité des Stations de Sports d'Hiver) et autres acteurs de la montagne.

Bulletin neige & avalanches par téléphone au
0 892 68 10 20 Service 0,35 € / min + prix appel

RÉPUBLIQUE FRANÇAISE
Liberté Égalité Fraternité

METEO FRANCE
À VOS CÔTÉS, DANS UN CLIMAT QUI CHANGE

Bulletin d'estimation du risque d'avalanche

(valable en dehors des pistes balisées et ouvertes)

MASSIF : Renoso Incudine

Rédigé le samedi 21 mars 2026 à 15h

Conditions nivo-météo des 7 derniers jours

	dim. 15/03				lun. 16/03				mar. 17/03				mer. 18/03				jeu. 19/03				ven. 20/03				sam. 21/03			
	03h	09h	15h	21h	03h	09h	15h	21h	03h	09h	15h	21h	03h	09h	15h	21h	03h	09h	15h	21h	03h	09h	15h	21h	03h	09h	15h	21h
Météo																												
Vent (km/h)	25	40	70	60	60	45	15	35	30	45	15	10	20	40	45	70	60	30	40	60	50	50	40	30	30	20	15	15
à 2000m																												
Vent (km/h)	45	40	65	45	50	40	10	15	10	15	10	5	10	25	35	40	55	40	25	20	30	40	30	30	30	20	10	15
à 1500m																												

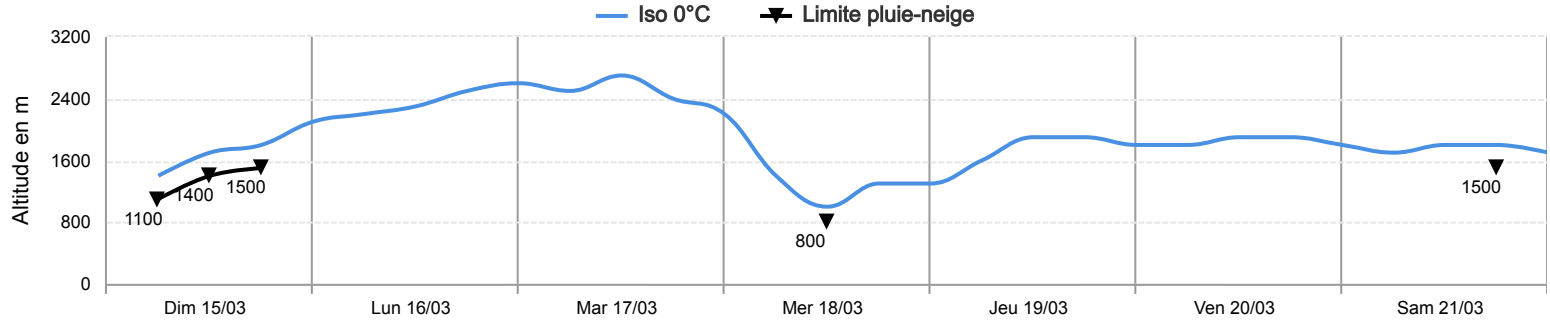

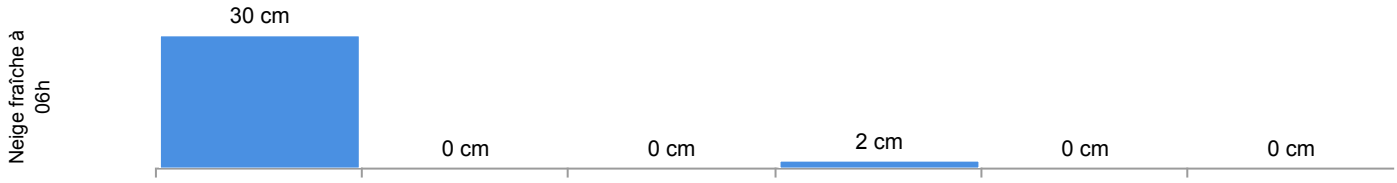

Risque d'avalanche							
	2	3	2	2	2	2	2
	dim. 15/03	lun. 16/03	mar. 17/03	mer. 18/03	jeu. 19/03	ven. 20/03	sam. 21/03

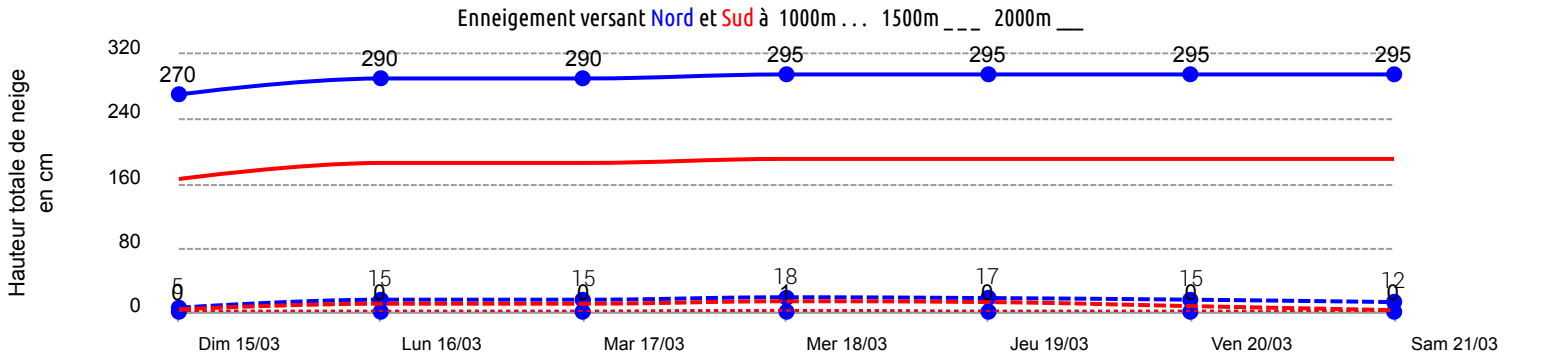

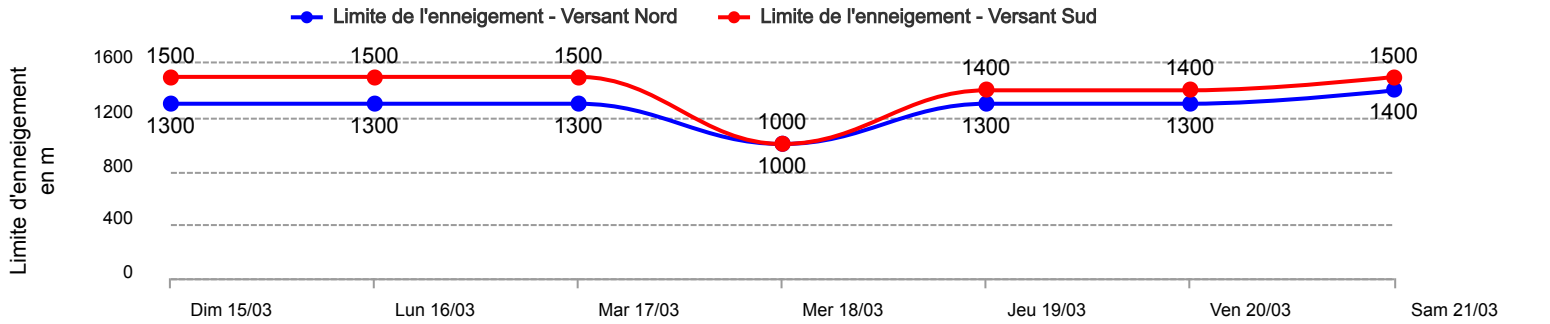

Pour consulter la vigilance en cours, veuillez vous rendre sur le site https://vigilance.meteofrance.fr/fr

Météo-France - 73 avenue de Paris, 94165 Saint-Mandé cedex - Contact : contact@meteo.fr

Rédigé par Météo-France avec la contribution des observateurs du réseau nivo-météorologiques. Partenariat : ANMSM (Maires de Stations de Montagne), DSF (Domaines Skiables de France), ADSP (Directeurs de Pistes et de la Sécurité des Stations de Sports d'Hiver) et autres acteurs de la montagne.

Bulletin neige & avalanches par téléphone au

0 892 68 10 20 Service 0,35 € / min + prix appel