Bulletin d'estimation du risque d'avalanche

(valable en dehors des pistes balisées et ouvertes)

MASSIF : Bauges

Rédigé le samedi 21 mars 2026 à 16h

Estimation des risques pour le : DIMANCHE 22 MARS

NOUVELLES INSTABILITÉS DANS LA NEIGE FRAICHE

2

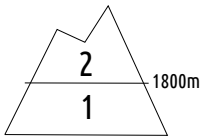

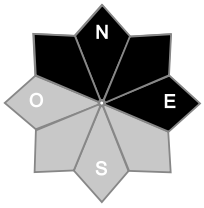

Au-dessus de 1800m indice de risque limité, plus bas indice faible.

Départs spontanés : Instabilités dans la neige fraiche

Déclenchements provoqués : Instabilités dans la neige fraiche

Indices de risque : 5 très fort - 4 fort - 3 marqué - 2 limité - 1 faible -- En noir : les pentes les plus dangereuses

Stabilité du manteau neigeux

Situation avalancheuse typique : neige fraîche neige ventée

Déclenchements provoqués :

* **Quelques instabilités dans la neige fraiche dès 1800/2000 m**. Elles se forment dans la nuit de samedi à dimanche et dimanche en matinée. Elles sont plus nombreuses sous le vent de sud-ouest puis de sud-est, et peuvent être réactives au passage d'un skieur. Taille 1 à 2 (petite à moyenne).

Observables : accumulation de neige, vaguelettes, fissures sous les skis.

Départs spontanés :

* Départs dans la neige fraiche au cours des chutes ou à cause du vent en journée. Taille 1 à 2.
* Peu probable, plaques de fond, en tous versants, à toute heure du jour et de la nuit, dans les pentes lisses et raides (zones herbeuses, dalles, vires). Taille 2.

Qualité de la neige

Enneigement :

L'enneigement passe d'inexistant à relativement bon une fois la limite d'enneigement atteinte.
On peut chausser les skis vers 1200/1300 m en nord et 1400/1500 m en sud.
Grosses corniches présentes.

Qualité de la neige ce dimanche :

* Dans les adrets (et les ubacs sous 1800 m), 5/10 cm (localement) de neige fraiche reposant sur une neige de printemps.
* Dans les ubacs d'altitude, 5/10 cm (localement) de neige fraiche sur de la neige froide souvent travaillée par le vent. Dans les couloirs/secteurs encaissés, la neige est restée légère.

Aperçu météo pour le dimanche 22 mars

Averses de neige dans la nuit et en matinée, nuageux l'après-midi avec un léger vent de sud-ouest.

	nuit	matin	après-midi	soir
Pluie-Neige	1 200 m	1 100 m		
Iso 0 °C	1 500 m	1 400 m	1 700 m	1 600 m
Vent 1500 m	10 km/h	15 km/h	10 km/h	5 km/h
Vent 2000 m	20 km/h	25 km/h	15 km/h	5 km/h

Épaisseur de neige hors-piste

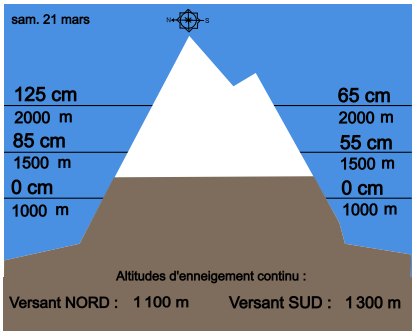

Précipitations à 1800 m

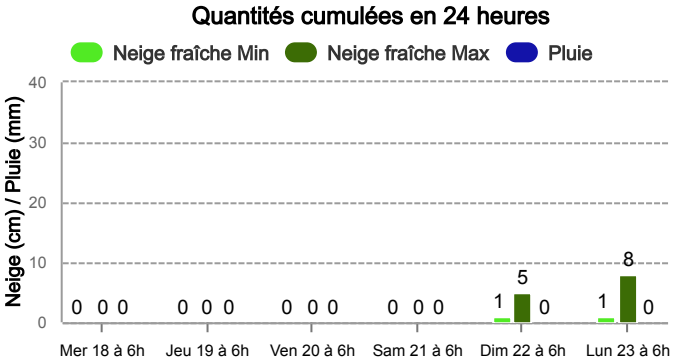

Tendance du lundi 23 mars

1

Indice de risque faible

Journée ensoleillée, encore quelques instabilités dans la neige récente et coulées de neige humide.

Pour consulter la vigilance en cours, veuillez vous rendre sur le site https://vigilance.meteofrance.fr/fr

Météo-France - 73 avenue de Paris, 94165 Saint-Mandé cedex - Contact : contact@meteo.fr

Rédigé par Météo-France avec la contribution des observateurs du réseau nivo-météorologiques. Partenariat : ANMSM (Maires de Stations de Montagne), DSF (Domaines Skiables de France), ADSP (Directeurs de Pistes et de la Sécurité des Stations de Sports d'Hiver) et autres acteurs de la montagne.

Bulletin neige & avalanches par téléphone au

0 892 68 10 20 Service 0,35 € / min + prix appel

RÉPUBLIQUE FRANÇAISE
Liberté Égalité Fraternité

METEO FRANCE
À VOS CÔTÉS, DANS UN CLIMAT QUI CHANGE

Bulletin d'estimation du risque d'avalanche

(valable en dehors des pistes balisées et ouvertes)

MASSIF : Bauges

Rédigé le samedi 21 mars 2026 à 16h

Conditions nivo-météo des 7 derniers jours

	dim. 15/03				lun. 16/03				mar. 17/03				mer. 18/03				jeu. 19/03				ven. 20/03				sam. 21/03			
	03h	09h	15h	21h	03h	09h	15h	21h	03h	09h	15h	21h	03h	09h	15h	21h	03h	09h	15h	21h	03h	09h	15h	21h	03h	09h	15h	21h
Météo																												
Vent (km/h)	35	25	30	15	15	20	20	15	25	25	30	30	25	20	70	40	40	20	20	20	15	10	5	5	5	10	10	10
à 2000m																												
Vent (km/h)	30	20	25	10	10	15	15	10	15	15	20	20	15	15	40	35	35	15	20	10	5	5	0	0	0	5	5	5
à 1500m																												

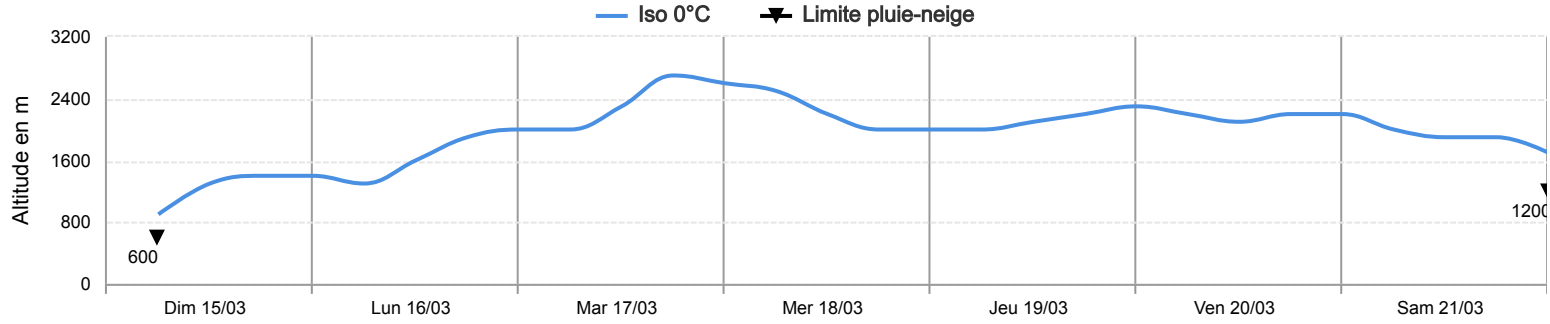

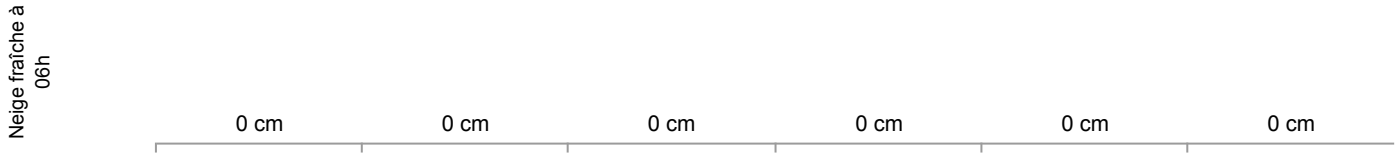

Risque d'avalanche	dim. 15/03	lun. 16/03	mar. 17/03	mer. 18/03	jeu. 19/03	ven. 20/03	sam. 21/03
	3	2	2	2	2	2	1

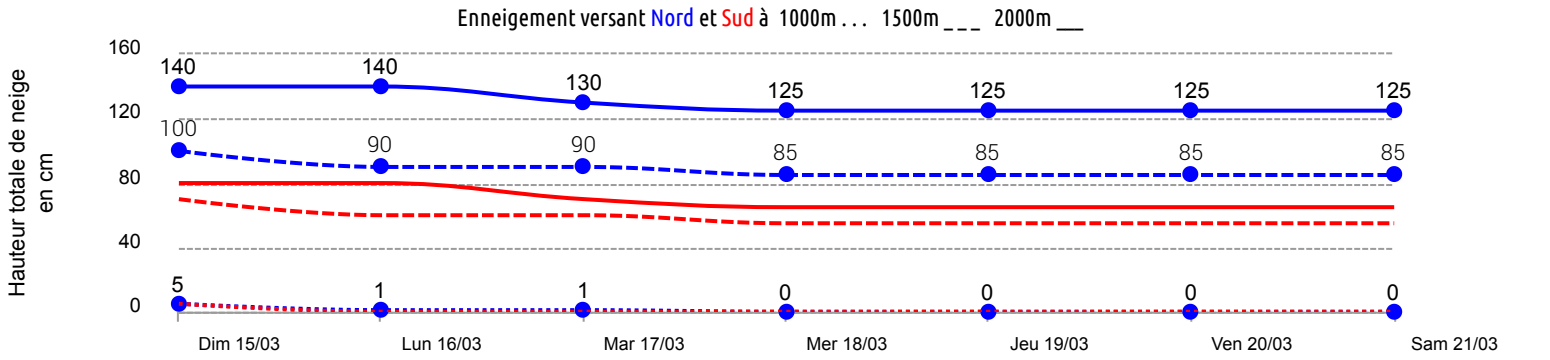

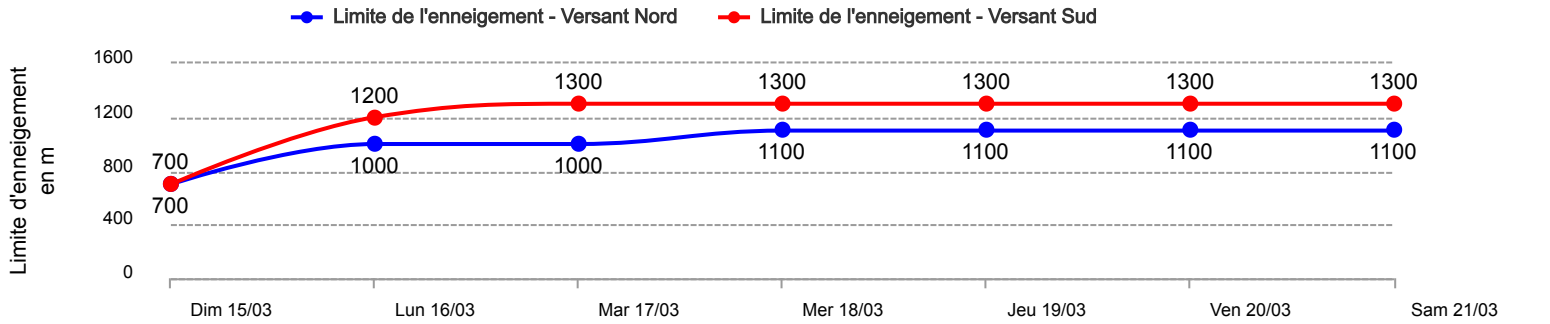

Pour consulter la vigilance en cours, veuillez vous rendre sur le site https://vigilance.meteofrance.fr/fr

Météo-France - 73 avenue de Paris, 94165 Saint-Mandé cedex - Contact : contact@meteo.fr

Rédigé par Météo-France avec la contribution des observateurs du réseau nivo-météorologiques. Partenariat : ANMSM (Maires de Stations de Montagne), DSF (Domaines Skiables de France), ADSP (Directeurs de Pistes et de la Sécurité des Stations de Sports d'Hiver) et autres acteurs de la montagne.

Bulletin neige & avalanches par téléphone au

0 892 68 10 20 Service 0,35 € / min + prix appel