Bulletin d'estimation du risque d'avalanche
(valable en dehors des pistes balisées et ouvertes)

MASSIF : Champsaur

Rédigé le samedi 21 mars 2026 à 16h

Estimation des risques pour le : DIMANCHE 22 MARS

NOUVELLES PLAQUES EN FORMATION AVEC LES CHUTES DE NEIGE

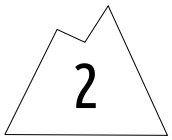

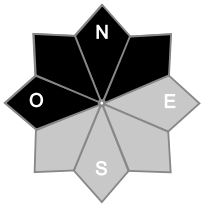

Indice de risque limité.

Départs spontanés : dans la neige fraîche pendant les chutes. Taille limitée.

Déclenchements provoqués : plaques à vent en formation dans la neige fraîche, sensibles en versants froids d'altitude

Indices de risque : 5 très fort - 4 fort - 3 marqué - 2 limité - 1 faible -- En noir : les pentes les plus dangereuses

Stabilité du manteau neigeux

Situation avalancheuse typique : neige ventée

Déclenchements provoqués : plaques en formation dans la neige fraîche sous l'action de chutes de neige peu ventées. Plaques souvent peu épaisses mais facilement déclenchables dans un large secteur nord d'altitude supérieure à 2200 m environ, plutôt à proximité des crêtes et ruptures de pente. Elles peuvent générer des avalanches de taille petite à moyenne (taille 1 à 2) en général, rarement grande (taille 3) en cas de rupture d'une couche fragile persistante plus profondément enfouie, suite à un premier départ en surface par exemple.

Départs spontanés : petites avalanches (taille 1) de neige fraîche en pentes raides au fil des chutes de neige. En fin de journée, des avalanches moyennes (taille 2) deviennent possibles dans un couloir chargé.

Qualité de la neige

L'enneigement est proche des normales pour une fin mars, à légèrement excédentaire en altitude.
Hauteurs de neige observées : 24 cm au hameau des Portes dans le Valgaudemar à 1270 m, 126 cm à la Nivôse d'Orcières à 2280 m, et 170 cm au-dessus de Prapic à 2480 m.

Limite d'enneigement skiable : vers 1400 m en ubacs, 1700/1800 m en adrets pas trop raides.

État de la neige de surface : on retrouve en surface 10/15 cm de neige froide, qui repose sur un manteau neigeux printanier bien croûté en sud. En large versant nord au-dessus de 2200/2300 m, elle repose sur une neige plus sèche, travaillée par le vent ou encore d'aspect poudreux.

Aperçu météo pour le dimanche 22 mars

	nuit	matin	après-midi	soir

Chutes de neige apportant une dizaine de cm, localement 15 cm sous une averse modérée.

Pluie-Neige	1 400 m	1 200 m	1 100 m	
Iso 0 °C	1 900 m	1 600 m	1 600 m	1 600 m
Vent 2000 m	↘ 5 km/h	↖ 10 km/h	← 25 km/h	← 20 km/h
Vent 3000 m	→ 15 km/h	← 20 km/h	← 35 km/h	← 30 km/h

Épaisseur de neige hors-piste

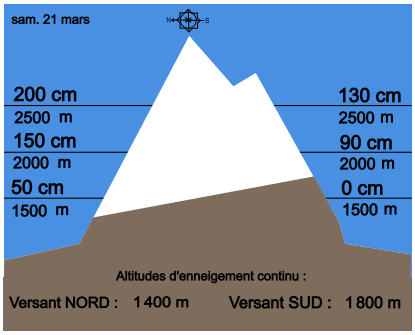

Précipitations à 1800 m

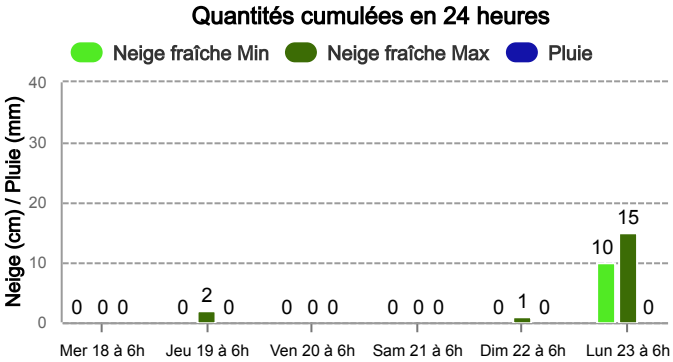

Tendance du lundi 23 mars

Indice de risque limité

Maintien probable d'un risque limité en altitude avec la présence de plaques dans la neige récente. Avec le retour du soleil, activité en neige humide en sud.

Pour consulter la vigilance en cours, veuillez vous rendre sur le site https://vigilance.meteofrance.fr/fr

Météo-France - 73 avenue de Paris, 94165 Saint-Mandé cedex - Contact : contact@meteo.fr

Rédigé par Météo-France avec la contribution des observateurs du réseau nivo-météorologiques. Partenariat : ANMSM (Maires de Stations de Montagne), DSF (Domaines Skiables de France), ADSP (Directeurs de Pistes et de la Sécurité des Stations de Sports d'Hiver) et autres acteurs de la montagne.

Bulletin neige & avalanches par téléphone au 0 892 68 10 20 Service 0,35 € / min + prix appel

RÉPUBLIQUE FRANÇAISE
Liberté Égalité Fraternité

METEO FRANCE
À VOS CÔTÉS, DANS UN CLIMAT QUI CHANGE

Bulletin d'estimation du risque d'avalanche

(valable en dehors des pistes balisées et ouvertes)

MASSIF : Champsaur

Rédigé le samedi 21 mars 2026 à 16h

Conditions nivo-météo des 7 derniers jours

	dim. 15/03				lun. 16/03				mar. 17/03				mer. 18/03				jeu. 19/03				ven. 20/03				sam. 21/03			
	03h	09h	15h	21h	03h	09h	15h	21h	03h	09h	15h	21h	03h	09h	15h	21h	03h	09h	15h	21h	03h	09h	15h	21h	03h	09h	15h	21h
Météo																												
Vent (km/h)	60	80	50	10	10	50	30	30	20	10	10	10	15	35	70	75	55	50	30	20	15	10	10	10	10	10	10	10
à 3000m																												
Vent (km/h)	70	80	50	5	10	40	20	15	10	5	10	5	5	10	40	55	55	25	15	10	10	5	10	5	5	5	10	5
à 2000m																												

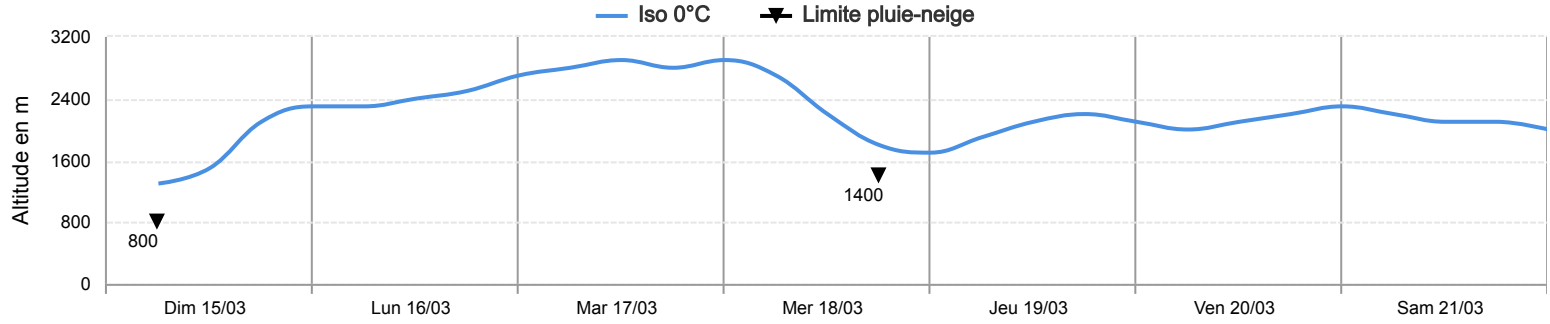

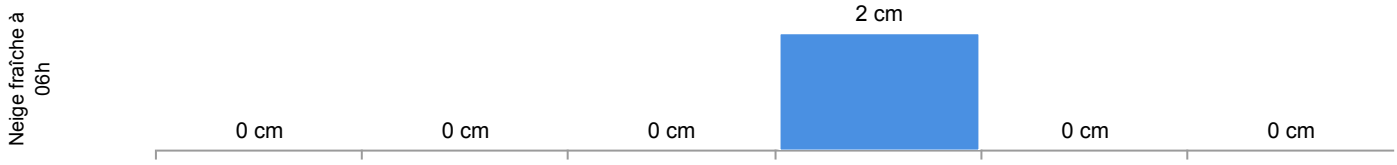

Risque d'avalanche	dim. 15/03	lun. 16/03	mar. 17/03	mer. 18/03	jeu. 19/03	ven. 20/03	sam. 21/03
	3	3	3	3	3	2	2

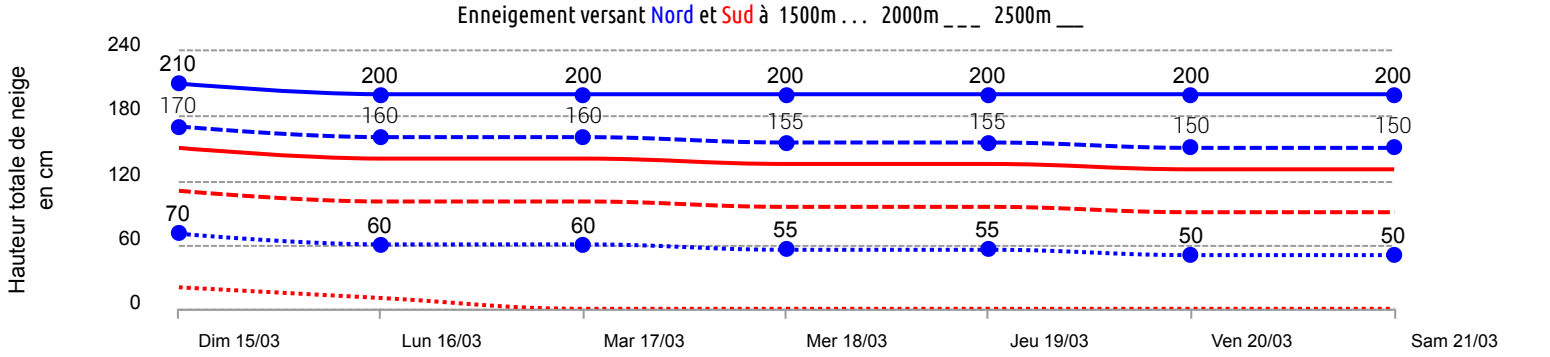

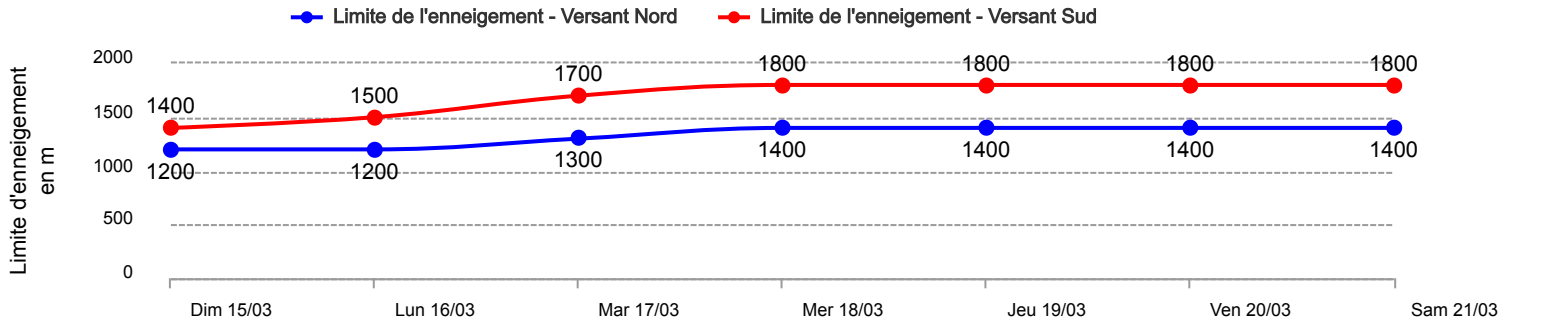

Pour consulter la vigilance en cours, veuillez vous rendre sur le site https://vigilance.meteofrance.fr/fr

Météo-France - 73 avenue de Paris, 94165 Saint-Mandé cedex - Contact : contact@meteo.fr

Rédigé par Météo-France avec la contribution des observateurs du réseau nivo-météorologiques. Partenariat : ANMSM (Maires de Stations de Montagne), DSF (Domaines Skiables de France), ADSP (Directeurs de Pistes et de la Sécurité des Stations de Sports d'Hiver) et autres acteurs de la montagne.

Bulletin neige & avalanches par téléphone au

0 892 68 10 20 Service 0,35 € / min + prix appel