Bulletin d'estimation du risque d'avalanche

(valable en dehors des pistes balisées et ouvertes)

MASSIF : Couserans

Rédigé le samedi 21 mars 2026 à 16h

Estimation des risques pour le : DIMANCHE 22 MARS

RARES STRUCTURES DE PLAQUES EN ALTITUDE.

2

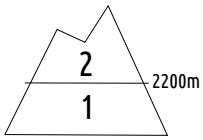

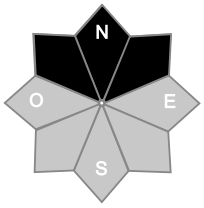

Au-dessus de 2200m indice de risque limité, plus bas indice faible.

Départs spontanés : Peu probable avec la dégradation en cours de journée.

Déclenchements provoqués : Encore quelques plaques possibles dans les versants froids

Indices de risque : 5 très fort - 4 fort - 3 marqué - 2 limité - 1 faible -- En noir : les pentes les plus dangereuses

Stabilité du manteau neigeux

Situation avalancheuse typique : couche fragile persistante

Déclenchements provoqués :

- Il reste possiblement quelques structures de plaques en altitude : en versants Nord au-dessus de 2200/2300 m, ainsi que dans d'autres secteurs ayant résisté à l'humidification de ces derniers jours donc souvent au dessus de 2500 à 2700m. Ces accumulations en neige sèche sont encore susceptibles de reposer des accumulations de neige roulée pouvant faire office de couche fragile avec des cassures typiques de 30/40 cm. Les déclenchements au passage d'un seul skieur/randonneur restent possibles surtout à la descente où les contraintes sont généralement plus importantes.

Observables : neige travaillée par le vent en surface, changement brutal de qualité de neige, fissures sous les skis, affaissement accompagné de 'whoomf'.

Départs spontanés :

- Avalanches de taille petite à moyenne possibles en neige humide, emportant parfois toute l'épaisseur de neige. Après un bon regel nocturne stabilisateur, le risque augmente dès la fin de matinée dans les versants Est et Sud-Est, où les accumulations de neige sont les plus importantes, notamment au dessus de 2100/2200m. L'après-midi, le risque diminue avec l'arrivée de nuages accompagnés d'une baisse des températures.

Autre :

Neige dure et parfois glacée aux premières heures du jour dans les zones s'étant humidifiées la veille. Ponts de neige et corniches de moins en moins solides au fil des heures.

Qualité de la neige

Enneigement :

Malgré le redoux de ces derniers jours, l'enneigement reste très correct pour la saison, après plusieurs hivers déficitaires. La fonte est tout de même importante au soleil et en moyenne montagne notamment en versants sud.

La limite skiable évolue peu avec des quantités de neige encore importantes dès 1500/1700m. On peut souvent chausser les skis vers 1500m en versant nord, voire1300/1400 m dans les meilleures configurations, plutôt 1700/1800m en versants sud. En altitude, les cumuls sont souvent conséquents mais les crêtes et sommets exposés au vent d'Ouest à Nord-ouest sont parfois complètement déneigés.

Qualité de la neige :

Dimanche matin, en dehors des zones forestières, la neige devrait être bien dure et regelée après une nuit claire. En cours de matinée, la neige s'humidifie rapidement sous 2000 m puis jusqu'à haute altitude dans les versants ensoleillés. L'arrivée de nuages l'après-midi associée à une baisse de l'isotherme 0 °C vers 2000m favorise un regel de la neige avant l'arrivée des averses. Quelques combes bien ombragées et abrit&ées du vent devraient recéler encore de la neige poudreuse au dessus de 2200/2400 m.

Aperçu météo pour le dimanche 22 mars

	nuit	matin	après-midi	soir
Soleil matinal, averses neigeuses en fin de journée.				
Pluie-Neige			1 600 m	1 200 m
Iso 0 °C	2 100 m	2 000 m	2 000 m	1 800 m
Vent 2000 m	10 km/h	15 km/h	30 km/h	35 km/h
Vent 3000 m	20 km/h	25 km/h	35 km/h	50 km/h

Pour consulter la vigilance en cours, veuillez vous rendre sur le site https://vigilance.meteofrance.fr/fr

Météo-France - 73 avenue de Paris, 94165 Saint-Mandé cedex - Contact : contact@meteo.fr

Rédigé par Météo-France avec la contribution des observateurs du réseau nivo-météorologiques. Partenariat : ANMSM (Maires de Stations de Montagne), DSF (Domaines Skiables de France), ADSP (Directeurs de Pistes et de la Sécurité des Stations de Sports d'Hiver) et autres acteurs de la montagne.

Bulletin neige & avalanches par téléphone au 0 892 68 10 20 Service 0,35 € / min + prix appel

Bulletin d'estimation du risque d'avalanche

(valable en dehors des pistes balisées et ouvertes)

MASSIF : Couserans

Rédigé le samedi 21 mars 2026 à 16h

Épaisseur de neige hors-piste

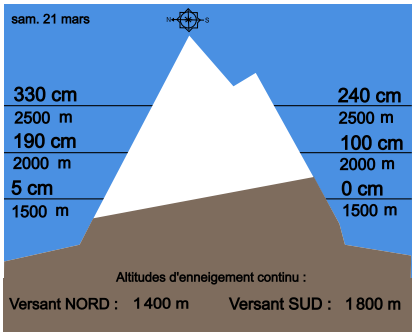

Précipitations à 1800 m

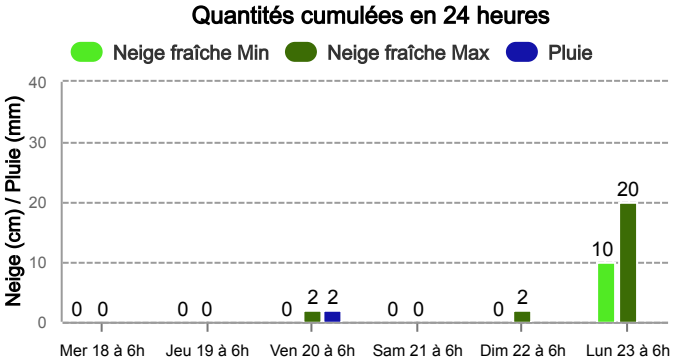

Tendance du lundi 23 mars

Indice de risque limité

Risque potentiellement en hausse suivant l'activité neigeuse de dimanche soir.

Pour consulter la vigilance en cours, veuillez vous rendre sur le site https://vigilance.meteofrance.fr/fr

Météo-France - 73 avenue de Paris, 94165 Saint-Mandé cedex - Contact : contact@meteo.fr

Rédigé par Météo-France avec la contribution des observateurs du réseau nivo-météorologiques. Partenariat : ANMSM (Maires de Stations de Montagne), DSF (Domaines Skiables de France), ADSP (Directeurs de Pistes et de la Sécurité des Stations de Sports d'Hiver) et autres acteurs de la montagne.

Bulletin neige & avalanches par téléphone au

0 892 68 10 20 Service 0,35 € / min + prix appel

RÉPUBLIQUE FRANÇAISE
Liberté Égalité Fraternité

METEO FRANCE
À VOS CÔTÉS, DANS UN CLIMAT QUI CHANGE

Bulletin d'estimation du risque d'avalanche

(valable en dehors des pistes balisées et ouvertes)

MASSIF : Couserans

Rédigé le samedi 21 mars 2026 à 16h

Conditions nivo-météo des 7 derniers jours

	dim. 15/03				lun. 16/03				mar. 17/03				mer. 18/03				jeu. 19/03				ven. 20/03				sam. 21/03			
	03h	09h	15h	21h	03h	09h	15h	21h	03h	09h	15h	21h	03h	09h	15h	21h	03h	09h	15h	21h	03h	09h	15h	21h	03h	09h	15h	21h
Météo																												
Vent (km/h)	95	95	75	50	40	30	30	20	25	15	15	15	15	15	20	25	40	35	30	20	15	20	20	15	20	15	20	15
à 3000m																												
Vent (km/h)	60	60	50	30	25	20	20	10	15	10	10	10	10	5	10	20	30	25	20	10	10	10	10	15	10	10	15	10
à 2000m																												

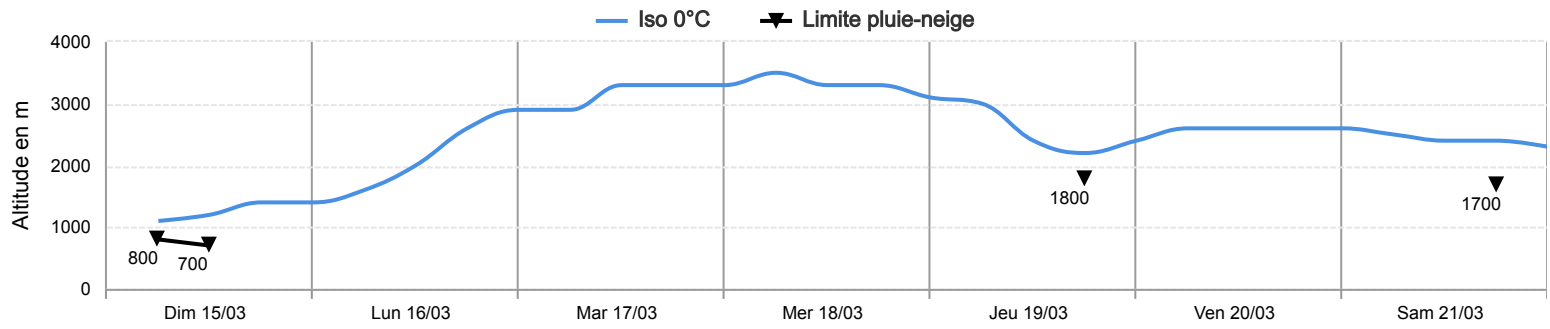

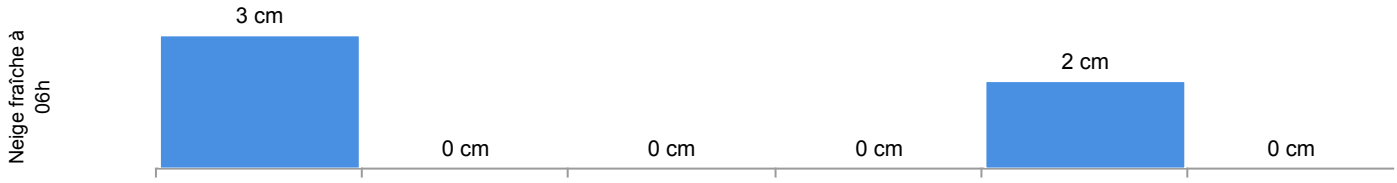

Risque d'avalanche	dim. 15/03	lun. 16/03	mar. 17/03	mer. 18/03	jeu. 19/03	ven. 20/03	sam. 21/03
	3	3	3	3	2	2	2

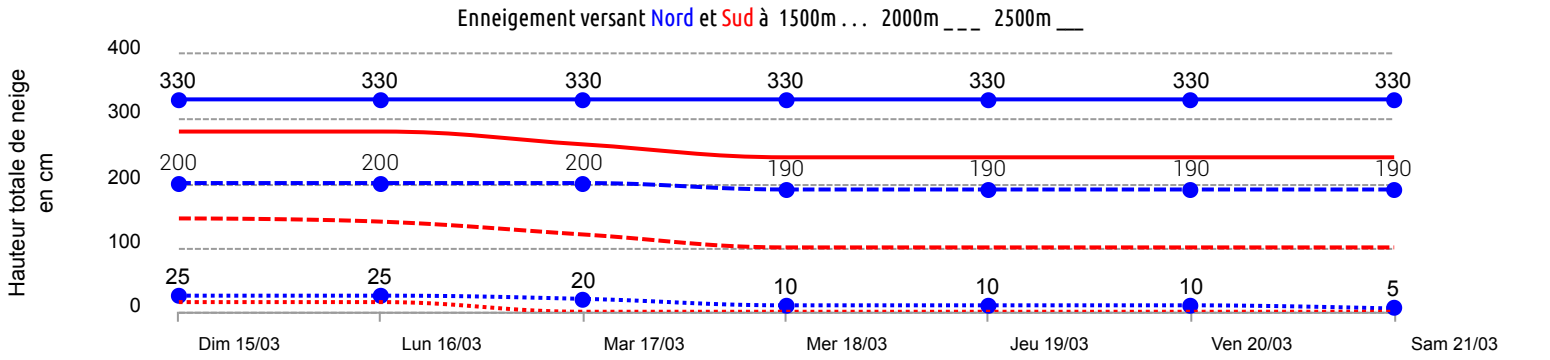

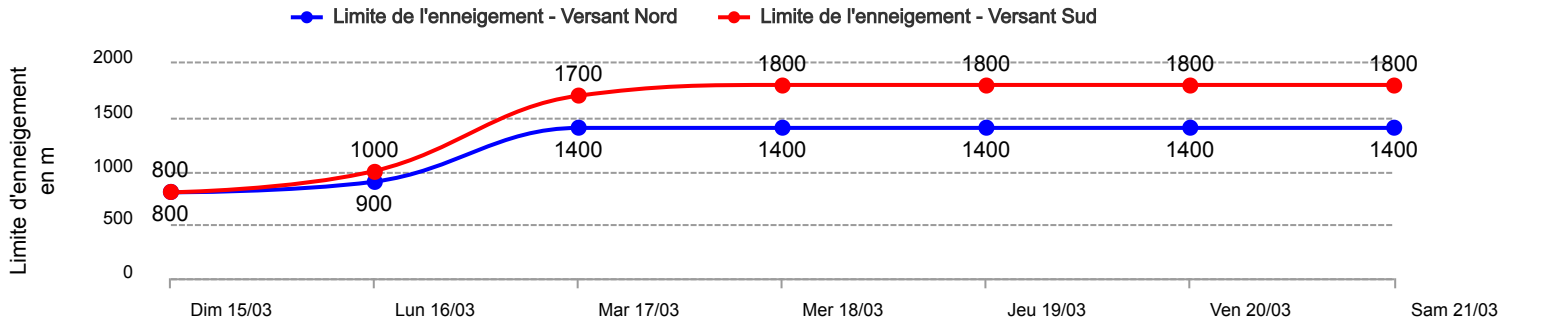

Pour consulter la vigilance en cours, veuillez vous rendre sur le site https://vigilance.meteofrance.fr/fr

Météo-France - 73 avenue de Paris, 94165 Saint-Mandé cedex - Contact : contact@meteo.fr

Rédigé par Météo-France avec la contribution des observateurs du réseau nivo-météorologiques. Partenariat : ANMSM (Maires de Stations de Montagne), DSF (Domaines Skiables de France), ADSP (Directeurs de Pistes et de la Sécurité des Stations de Sports d'Hiver) et autres acteurs de la montagne.

Bulletin neige & avalanches par téléphone au

0 892 68 10 20 Service 0,35 € / min + prix appel