Bulletin d'estimation du risque d'avalanche
(valable en dehors des pistes balisées et ouvertes)

MASSIF : Mont-Blanc

Rédigé le samedi 21 mars 2026 à 16h

Estimation des risques pour le : DIMANCHE 22 MARS

NOUVELLES INSTABILITÉS DANS LA NEIGE FRAICHE

2

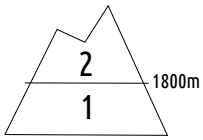

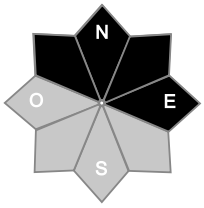

Au-dessus de 1800m indice de risque limité, plus bas indice faible.

Départs spontanés : Instabilités dans la neige fraiche

Déclenchements provoqués : Instabilités dans la neige fraiche

Indices de risque : 5 très fort - 4 fort - 3 marqué - 2 limité - 1 faible -- En noir : les pentes les plus dangereuses

Stabilité du manteau neigeux

Situation avalancheuse typique : neige fraîche — neige ventée

Déclenchements provoqués :

* **Quelques instabilités dans la neige fraiche dès 1800/2000 m**. Elles se forment dans la nuit de samedi à dimanche et dimanche en matinée. Elles sont plus nombreuses sous le vent de sud-ouest puis de sud-est, et sont parfois réactives au passage d'un skieur. D'anciennes plaques, souvent dures sont encore présentes sur un large secteur nord (formée par l'épisode de foehn mercredi dernier), elles sont parfois loin des crêtes, dans les pentes. Taille 1 à 2 (petite à moyenne).
Observables : accumulation de neige, vaguelettes, fissures sous les skis.
* Dans les adrets d'altitude et en ubacs au-dessus de 2100 m, une couche fragile persistante est encore enfouie, mais ne semble pas vraiment déclenchable par un skieur. Toutefois, par une forte surcharge (avalanche en cascade, chutes de corniches, chutes de séracs), elle pourrait être sollicitée et engendrer une avalanche de taille 2 à 3 (moyenne à grande).

Départs spontanés :

* Départs dans la neige fraiche au cours des chutes ou à cause du vent en journée. Taille 1 à 2.
* Peu probable, plaques de fond, en tous versants, à toute heure du jour et de la nuit, dans les pentes lisses et raides (zones herbeuses, dalles, vires). Taille 2.

Qualité de la neige

Enneigement :
L'enneigement passe d'inexistant à relativement bon une fois la limite d'enneigement atteinte.
On peut chausser les skis vers 1200/1300 m en nord et 1400/1500 m en sud.
Grosses corniches présentes.

Qualité de la neige ce dimanche :

* Dans les adrets sous 2000 m (et les ubacs sous 1800 m), 5/10 cm (localement) de neige fraiche reposant sur une neige de printemps.
* Plus haut en altitude, neige froide souvent travaillée par le vent. Dans les couloirs/secteurs encaissés, la neige reste légère. Plus on monte en altitude, plus la neige est dure.
* En haute-montagne, le travail du vent est très visible et ainsi la neige est souvent très difficile à skier (notamment dans les bassins glaciaires).

Aperçu météo pour le dimanche 22 mars

Averses de neige dans la nuit et en matinée, nuageux l'après-midi avec une tendance Foehn.

	nuit	matin	après-midi	soir
Pluie-Neige	1 200 m	1 100 m		
Iso 0 °C	1 500 m	1 400 m	1 700 m	1 600 m
Vent 2000 m	15 km/h	25 km/h	10 km/h	5 km/h
Vent 4000 m	30 km/h	40 km/h	20 km/h	15 km/h

Épaisseur de neige hors-piste

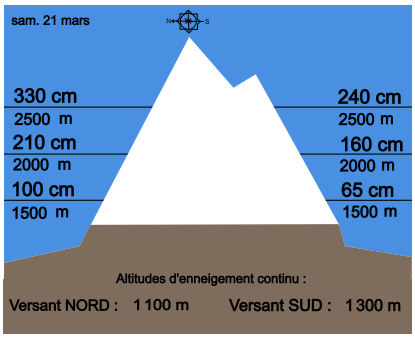

Précipitations à 1800 m

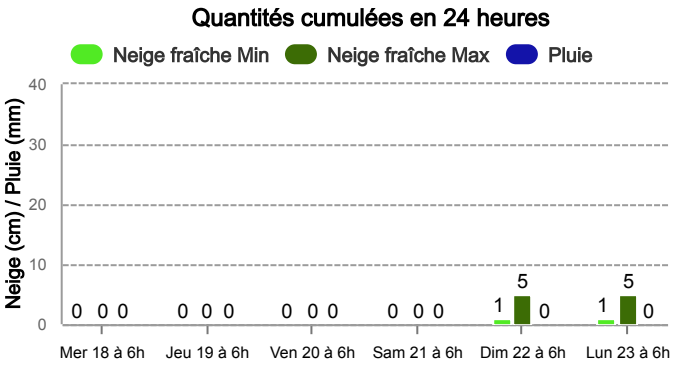

Tendance du lundi 23 mars

2

Indice de risque limité

Journée ensoleillée, encore quelques instabilités dans la neige récente et coulées de neige humide.

Pour consulter la vigilance en cours, veuillez vous rendre sur le site https://vigilance.meteofrance.fr/fr

Météo-France - 73 avenue de Paris, 94165 Saint-Mandé cedex - Contact : contact@meteo.fr

Rédigé par Météo-France avec la contribution des observateurs du réseau nivo-météorologiques. Partenariat : ANMSM (Maires de Stations de Montagne), DSF (Domaines Skiables de France), ADSP (Directeurs de Pistes et de la Sécurité des Stations de Sports d'Hiver) et autres acteurs de la montagne.

Bulletin neige & avalanches par téléphone au 0 892 68 10 20 Service 0,35 € / min + prix appel

RÉPUBLIQUE FRANÇAISE
Liberté Égalité Fraternité

METEO FRANCE
À VOS CÔTÉS, DANS UN CLIMAT QUI CHANGE

Bulletin d'estimation du risque d'avalanche

(valable en dehors des pistes balisées et ouvertes)

MASSIF : Mont-Blanc

Rédigé le samedi 21 mars 2026 à 16h

Conditions nivo-météo des 7 derniers jours

	dim. 15/03				lun. 16/03				mar. 17/03				mer. 18/03				jeu. 19/03				ven. 20/03				sam. 21/03			
	03h	09h	15h	21h	03h	09h	15h	21h	03h	09h	15h	21h	03h	09h	15h	21h	03h	09h	15h	21h	03h	09h	15h	21h	03h	09h	15h	21h
Météo																												
Vent (km/h)	30	35	40	60	70	80	60	70	65	65	70	70	80	100	100	80	60	50	50	60	40	30	20	15	20	25	30	30
à 4000m																												
Vent (km/h)	25	10	10	10	10	20	15	20	20	20	25	20	15	40	80	40	20	30	10	20	5	5	15	10	10	10	10	10
à 2000m																												

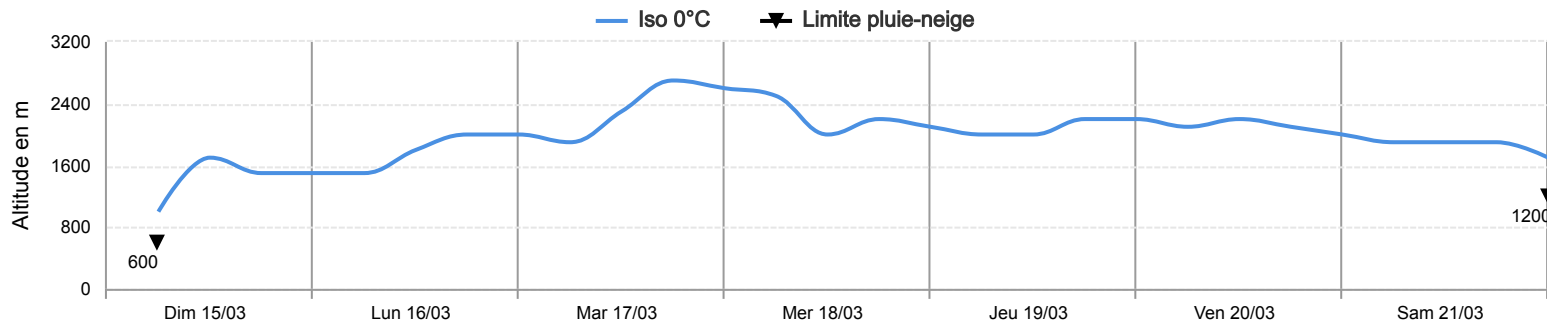

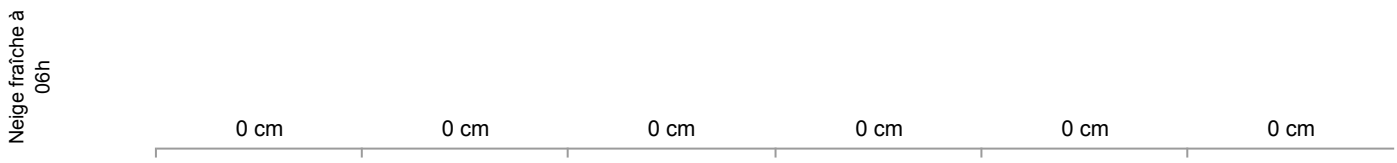

Risque d'avalanche	dim. 15/03	lun. 16/03	mar. 17/03	mer. 18/03	jeu. 19/03	ven. 20/03	sam. 21/03
	3	3	3	3	3	2	2

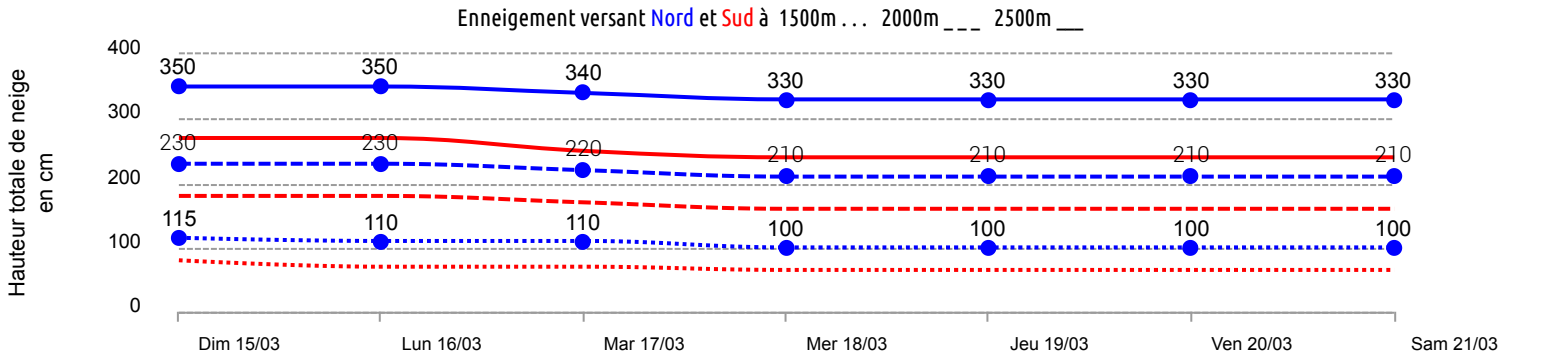

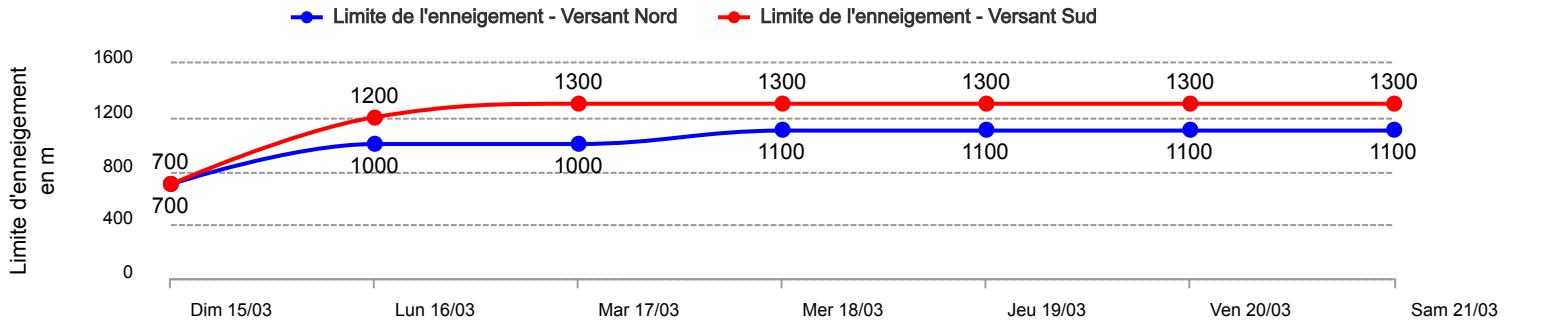

Pour consulter la vigilance en cours, veuillez vous rendre sur le site https://vigilance.meteofrance.fr/fr

Météo-France - 73 avenue de Paris, 94165 Saint-Mandé cedex - Contact : contact@meteo.fr

Rédigé par Météo-France avec la contribution des observateurs du réseau nivo-météorologiques. Partenariat : ANMSM (Maires de Stations de Montagne), DSF (Domaines Skiables de France), ADSP (Directeurs de Pistes et de la Sécurité des Stations de Sports d'Hiver) et autres acteurs de la montagne.

Bulletin neige & avalanches par téléphone au

0 892 68 10 20 Service 0,35 € / min + prix appel