Bulletin d'estimation du risque d'avalanche

(valable en dehors des pistes balisées et ouvertes)

MASSIF : Ubaye

Rédigé le samedi 21 mars 2026 à 16h

Estimation des risques pour le : DIMANCHE 22 MARS

PLAQUES EN FORMATION DANS LA NEIGE FRAICHE VENTÉE EN FIN DE JOURNÉE

3

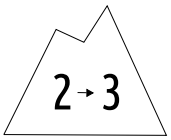

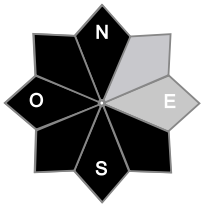

Indice de risque limité évoluant en marqué.

Départs spontanés : rares départs superficiels de neige fraiche, plus fréquents en fin de journée.

Déclenchements provoqués : rares plaques en journée, devenant nombreuses en fin de journée vers les crêtes avec la levé du vent de nord-est.

Indices de risque : 5 très fort - 4 fort - 3 marqué - 2 limité - 1 faible -- En noir : les pentes les plus dangereuses

Stabilité du manteau neigeux

Situation avalancheuse typique : neige ventée

Déclenchements provoqués : rares plaques en place en ubacs d'altitude en journée. De nouvelles plaques à vent se forment en fin d'après-midi avec la poursuite des chutes de neige et la levée du vent de nord-est. Plaques très faciles à déclencher au passage d'un skieur, présentes plutôt aux abords des crêtes dans un large versant nord-ouest à sud-est, et générant des avalanches de taille petites à moyenne (taille 1 à 2).
En versant nord au-dessus de 2200 m environ, des départs plus volumineux sont possibles au passage d'un skieur par déstabilisation d'une plaque plus ancienne et épaisse. Avalanche de taille moyenne (taille 2), rarement grande (taille 3).

Départs spontanés : rares départs superficiels de neige fraiche, devenant un peu plus fréquent en fin de journée avec la levée du vent de nord-est. Avalanches de taille petites à moyenne (taille 1 à 2).

Qualité de la neige

Enneigement proche des normales.
Hauteurs de neige observées : 77 cm à la Nivôse de Restefond à 2550 m (secteur venté), 85 cm au-dessus de Larche à 2270 m en adret.

Enneigement skiable : vers 1500 m en ubacs, 1800/1900 m en adrets peu pentus.

État de la neige en surface : on retrouve le matin une petite couche de neige fraiche peu ventée, reposant sur un manteau neigeux généralement dure/regelé, excepté en ubacs au-dessus de 2000/2200 m environ, où la couche de neige légère peut être plus importante dans les combes abritées du vent. Couche de neige fraiche s'épaississant en journée et devenant légèrement soufflé par le vent proche des crêtes.

Aperçu météo pour le dimanche 22 mars

	nuit	matin	après-midi	soir
Chutes de neige en journée, donnant 10 à 15 cm au dessus de 1300/1400 m.				
Pluie-Neige	1 100 m	1 100 m	1 200 m	
Iso 0 °C	1 500 m	1 400 m	1 600 m	1 600 m
Vent 2000 m	↗ 10 km/h	← 15 km/h	← 25 km/h	← 30 km/h
Vent 3000 m	→ 15 km/h	↖ 25 km/h	← 35 km/h	← 40 km/h

Épaisseur de neige hors-piste

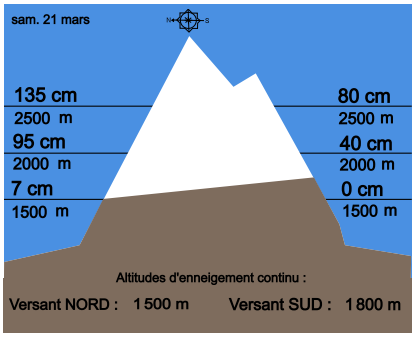

Précipitations à 1800 m

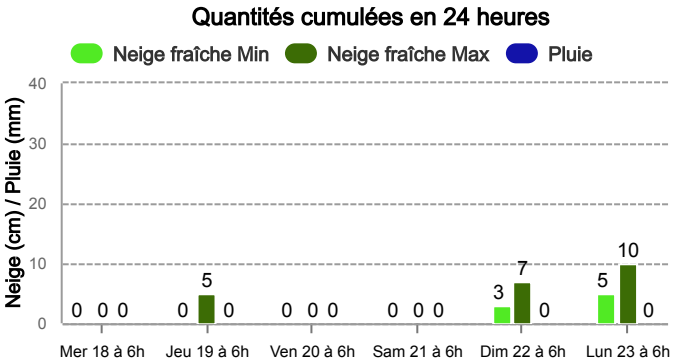

Tendance du lundi 23 mars

3 **Indice de risque marqué**

Nombreuses plaques superficielles encore sensibles dans la neige fraiche, formées avec le transport de neige par le vent de nord-est en cours de nuit de dimanche à lundi.

Pour consulter la vigilance en cours, veuillez vous rendre sur le site https://vigilance.meteofrance.fr/fr

Météo-France - 73 avenue de Paris, 94165 Saint-Mandé cedex - Contact : contact@meteo.fr

Rédigé par Météo-France avec la contribution des observateurs du réseau nivo-météorologiques. Partenariat : ANMSM (Maires de Stations de Montagne), DSF (Domaines Skiables de France), ADSP (Directeurs de Pistes et de la Sécurité des Stations de Sports d'Hiver) et autres acteurs de la montagne.

Bulletin neige & avalanches par téléphone au
0 892 68 10 20 Service 0,35 € / min + prix appel

RÉPUBLIQUE FRANÇAISE
Liberté Égalité Fraternité

METEO FRANCE
À VOS CÔTÉS, DANS UN CLIMAT QUI CHANGE

Bulletin d'estimation du risque d'avalanche

(valable en dehors des pistes balisées et ouvertes)

MASSIF : Ubaye

Rédigé le samedi 21 mars 2026 à 16h

Conditions nivo-météo des 7 derniers jours

	dim. 15/03				lun. 16/03				mar. 17/03				mer. 18/03				jeu. 19/03				ven. 20/03				sam. 21/03			
	03h	09h	15h	21h	03h	09h	15h	21h	03h	09h	15h	21h	03h	09h	15h	21h	03h	09h	15h	21h	03h	09h	15h	21h	03h	09h	15h	21h
Météo																												
Vent (km/h)	65	75	45	35	50	40	35	35	25	30	25	20	25	50	70	80	70	50	30	30	20	15	15	10	15	15	20	15
à 3000m																												
Vent (km/h)	20	40	20	10	15	20	25	15	10	10	15	10	10	30	50	50	45	30	20	15	10	10	15	5	5	10	20	10
à 2000m																												

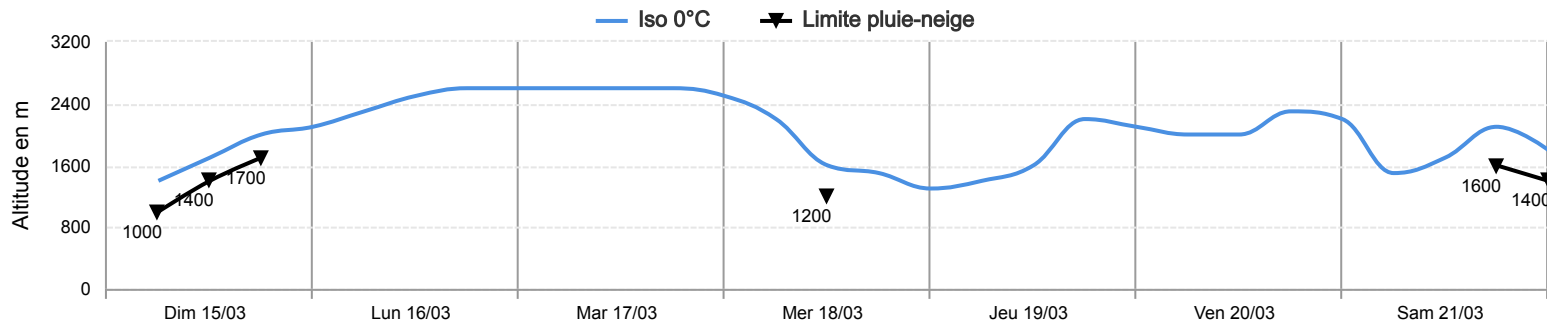

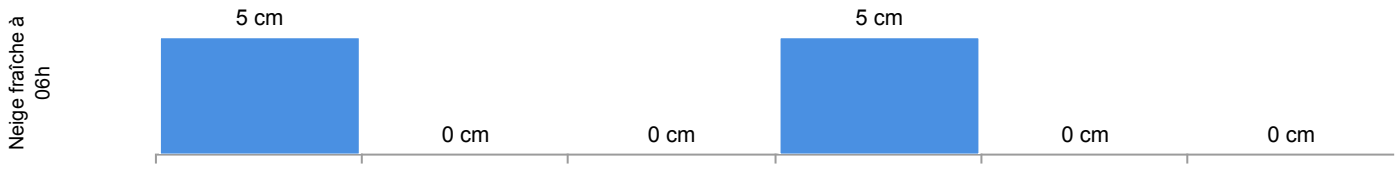

Risque d'avalanche						
3	3	2	3	3	2	2
dim. 15/03	lun. 16/03	mar. 17/03	mer. 18/03	jeu. 19/03	ven. 20/03	sam. 21/03

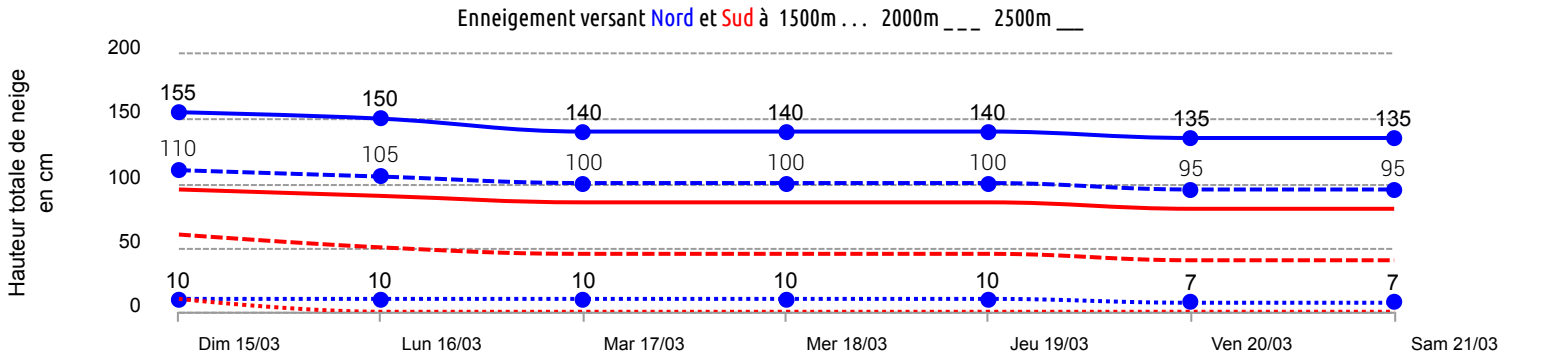

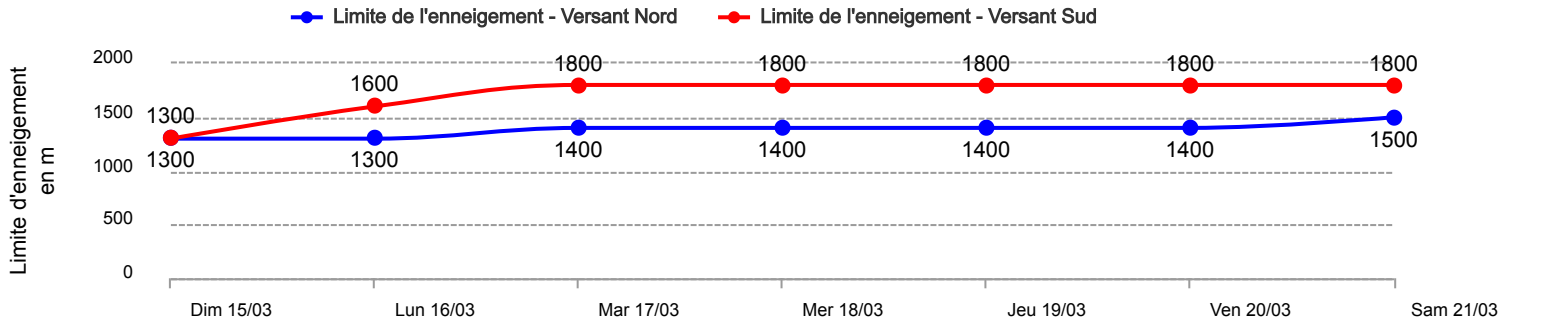

Pour consulter la vigilance en cours, veuillez vous rendre sur le site https://vigilance.meteofrance.fr/fr

Météo-France - 73 avenue de Paris, 94165 Saint-Mandé cedex - Contact : contact@meteo.fr

Rédigé par Météo-France avec la contribution des observateurs du réseau nivo-météorologiques. Partenariat : ANMSM (Maires de Stations de Montagne), DSF (Domaines Skiables de France), ADSP (Directeurs de Pistes et de la Sécurité des Stations de Sports d'Hiver) et autres acteurs de la montagne.

Bulletin neige & avalanches par téléphone au

0 892 68 10 20 Service 0,35 € / min + prix appel