Bulletin d'estimation du risque d'avalanche
(valable en dehors des pistes balisées et ouvertes)

MASSIF : Luchonnais

Rédigé le samedi 21 mars 2026 à 17h

Estimation des risques pour le : DIMANCHE 22 MARS

RARES PLAQUES ENCORE DÉCLENCHABLES AU-DESSUS DE 2200 M, MANTEAU PRINTANIER AILLEURS.

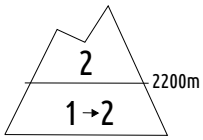

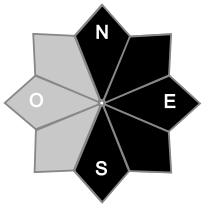

Plaques et soleil

Indices de risque : 5 très fort - 4 fort - 3 marqué - 2 limité - 1 faible -- En noir : les pentes les plus dangereuses

Au-dessus de 2200m indice de risque limité, plus bas indice faible évoluant en limité.

Départs spontanés : En neige humide, avalanches de fond possibles.

Déclenchements provoqués : De rares plaques encore parfois sensibles au-dessus de 2200 m en Nord à Nord-est

Stabilité du manteau neigeux

Situation avalancheuse typique : neige ventée neige humide

Déclenchements provoqués :
- **Au-dessus de 2200 m**, dans les **pentes raides Nord à Nord-Est**, des plaques à vent et des couches fragiles sont présentes. Elles sont le plus souvent devenues difficilement déclenchables, recouvertes par une croûte et détruites par les nuits claires. Rarement, certaines peuvent encore être plus facilement sollicitées au passage d'un skieur, là où la croûte est cassante et où les plaques sont plus épaisses (en zones d'accumulations), l'épaisseur ralentissant la métamorphose des plaques. Des déclenchements accidentels ont été rapportés jusqu'à jeudi.
- Ailleurs, en versants ensoleillés, le passage d'un skieur dans une pente raide en neige très humide peut favoriser un petit départ ponctuel.

Départs spontanés :
Peu ou pas d'activité en tout début de journée grâce à un regel efficace, puis des départs ponctuels dans la neige humide sont attendus dans les pentes raides au fil de l'ensoleillement (d'abord en est, puis sud, puis ouest), devenant plus fréquentes au fil de la journée. Les avalanches sont généralement petites à moyennes, quelques avalanches de fond sont possibles, parfois annoncées par l'ouverture de fissures, atteignant (rarement) une grande taille surtout dans les expositions sud-est où des accumulations sont présentes.
L'activité devrait cesser en milieu d'après-midi avec l'arrivée des nuages et d'une masse d'air plus fraîche.

Autres : Pont de neige et corniches encore en place, devenant fragiles au fil de l'humidification.

Qualité de la neige

Enneigement : Correct pour la saison au-dessus de 1800 à 2000 m, mais reste assez maigre en versants exposés au vent d'ouest. Manteau skiable à partir de 1600 m en nord, plutôt 2000 m en sud.
État de la neige : Neige croutée en versants nord, cassante au-dessus de 2000m, n'évoluant pas en journée. Ailleurs, elle est regelée et portante au petit jour. Neige rapidement dégelée en surface, mais lentement en profondeur au-dessus de 2000m, donnant de bonnes conditions de ski de printemps au soleil.

Aperçu météo pour le dimanche 22 mars

	nuit	matin	après-midi	soir

Belle matinée, arrivée dans l'après-midi de nuages bouchant le relief, donnant quelques centimètres de neige en fin de journée.

Pluie-Neige			1 700 m	1 500 m
Iso 0 °C	2 100 m	2 200 m	2 000 m	1 700 m
Vent 2000 m	→ 5 km/h	↓ 10 km/h	↓ 25 km/h	↓ 25 km/h
Vent 3000 m	↘ 30 km/h	↘ 35 km/h	↘ 45 km/h	↓ 45 km/h

Épaisseur de neige hors-piste

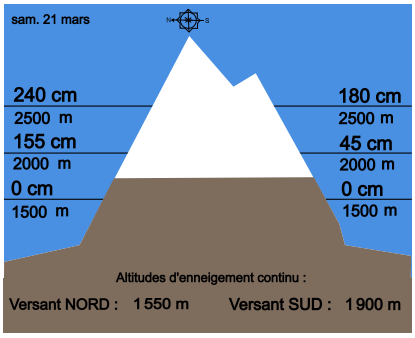

Précipitations à 1800 m

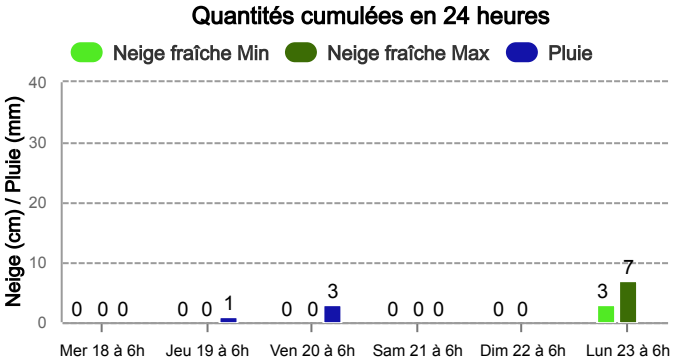

Tendance du lundi 23 mars

Indice de risque limité

Risque stationnaire

Pour consulter la vigilance en cours, veuillez vous rendre sur le site https://vigilance.meteofrance.fr/fr

Météo-France - 73 avenue de Paris, 94165 Saint-Mandé cedex - Contact : contact@meteo.fr

Rédigé par Météo-France avec la contribution des observateurs du réseau nivo-météorologiques. Partenariat : ANMSM (Maires de Stations de Montagne), DSF (Domaines Skiables de France), ADSP (Directeurs de Pistes et de la Sécurité des Stations de Sports d'Hiver) et autres acteurs de la montagne.

Bulletin neige & avalanches par téléphone au **0 892 68 10 20** Service 0,35 € / min + prix appel

RÉPUBLIQUE FRANÇAISE
Liberté Égalité Fraternité

METEO FRANCE
À VOS CÔTÉS, DANS UN CLIMAT QUI CHANGE

Bulletin d'estimation du risque d'avalanche

(valable en dehors des pistes balisées et ouvertes)

MASSIF : Luchonnais

Rédigé le samedi 21 mars 2026 à 17h

Conditions nivo-météo des 7 derniers jours

	dim. 15/03				lun. 16/03				mar. 17/03				mer. 18/03				jeu. 19/03				ven. 20/03				sam. 21/03			
	03h	09h	15h	21h	03h	09h	15h	21h	03h	09h	15h	21h	03h	09h	15h	21h	03h	09h	15h	21h	03h	09h	15h	21h	03h	09h	15h	21h
Météo																												
Vent (km/h)	75	75	65	75	70	50	40	30	25	20	15	15	15	10	15	30	35	25	20	20	25	20	15	10	10	10	15	15
à 3000m																												
Vent (km/h)	50	45	30	35	30	10	5	10	10	10	10	10	5	2	5	10	15	15	15	10	15	15	10	10	10	10	10	10
à 2000m																												

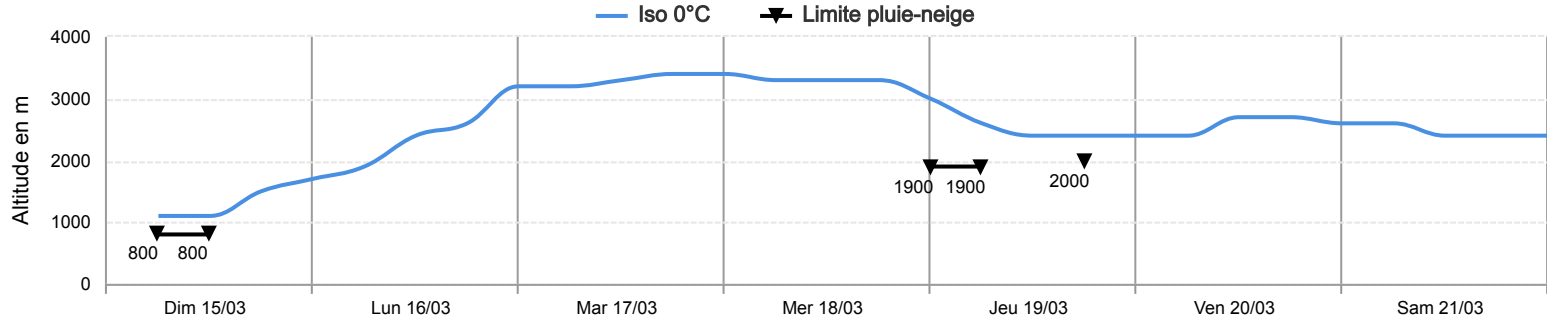

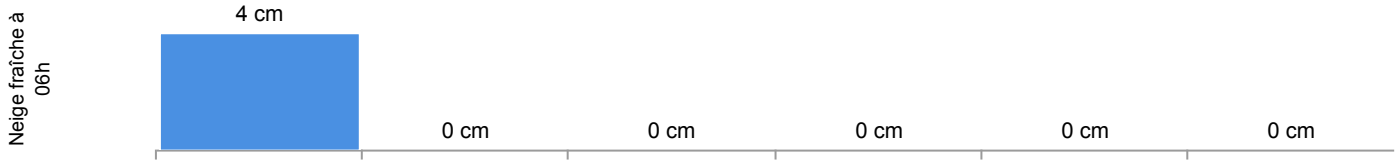

Risque d'avalanche	dim. 15/03	lun. 16/03	mar. 17/03	mer. 18/03	jeu. 19/03	ven. 20/03	sam. 21/03
	3	3	3	3	2	2	2

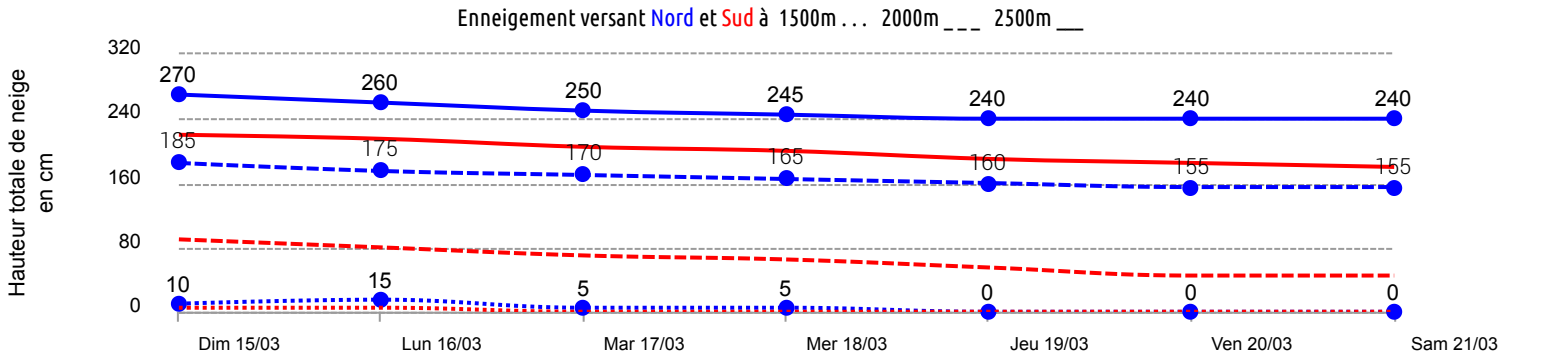

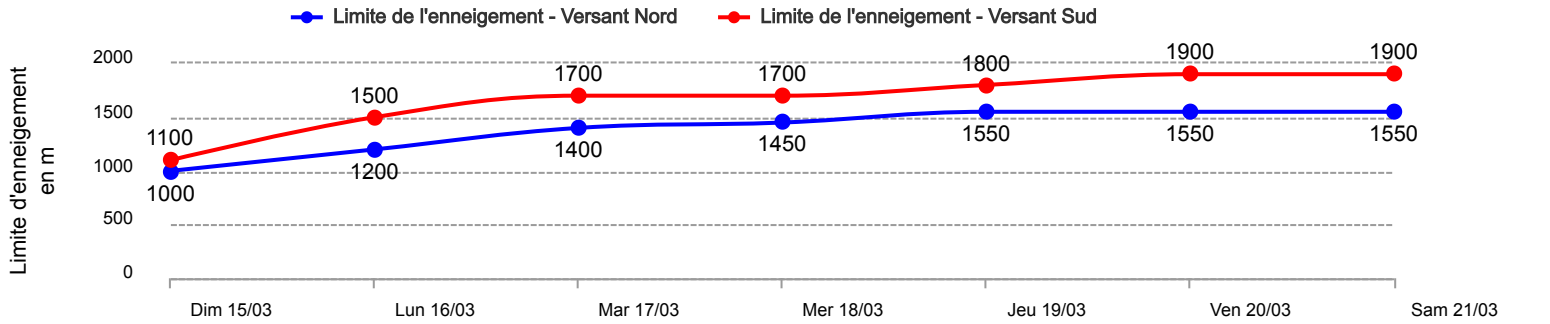

Pour consulter la vigilance en cours, veuillez vous rendre sur le site https://vigilance.meteofrance.fr/fr

Météo-France - 73 avenue de Paris, 94165 Saint-Mandé cedex - Contact : contact@meteo.fr

Rédigé par Météo-France avec la contribution des observateurs du réseau nivo-météorologiques. Partenariat : ANMSM (Maires de Stations de Montagne), DSF (Domaines Skiables de France), ADSP (Directeurs de Pistes et de la Sécurité des Stations de Sports d'Hiver) et autres acteurs de la montagne.

Bulletin neige & avalanches par téléphone au
0 892 68 10 20 Service 0,35 € / min + prix appel