GOBIERNO DE ESPAÑA
VICEPRESIDENCIA TERCERA DEL GOBIERNO
MINISTERIO PARA LA TRANSICIÓN ECOLÓGICA Y EL RETO DEMOGRÁFICO

Boletín de información nivológica y de peligro de aludes

Pirineo Navarro y Aragonés

aemet Agencia Estatal de Meteorología

domingo, 22 de marzo de 2026

Pronóstico hasta las 24 horas del lunes, día 23 de marzo

(Válido fuera de pistas de esquí balizadas y abiertas)

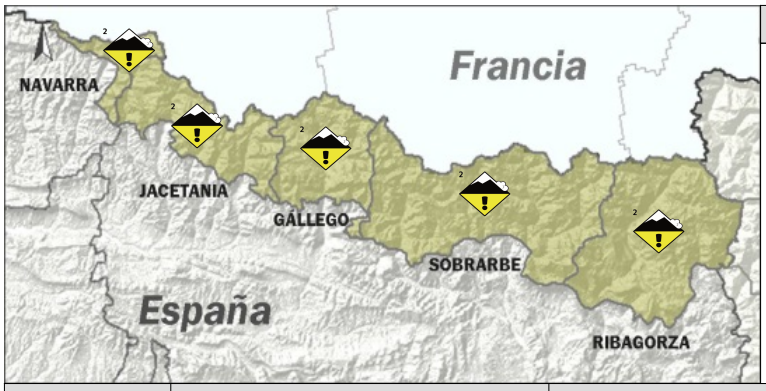

Problemas de aludes

- Nieve húmeda
- Capas débiles persistentes
- Placas de viento

Macizo	Peligro	Problemas de aludes, cota, orientación, tamaño	Innivación observada (m)
Navarra	2 — **Limitado**	**Nieve húmeda** — N, O, E, S — 2 **Placas de viento** — 2100 — N, O, E, S — 1	2026-03-22 N / S Cota más baja caras N
Jacetania	2 — **Limitado**	**Nieve húmeda** — N, O, E, S — 2 **Capas débiles persistentes** — 2400 — N, O, E, S — 2	2026-03-22 N / S Cota más baja caras N
Gállego	2 — **Limitado**	**Nieve húmeda** — N, O, E, S — 2 **Capas débiles persistentes** — 2400 — N, O, E, S — 2	2026-03-22 N / S Cota más baja caras N

AEMET. Se autoriza la reproducción de su contenido citando la fuente.

Boletín de información nivológica y de peligro de aludes

Pirineo Navarro y Aragonés

Sobrarbe	**Limitado**	**Nieve húmeda** 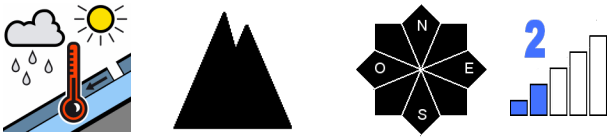 **Capas débiles persistentes** 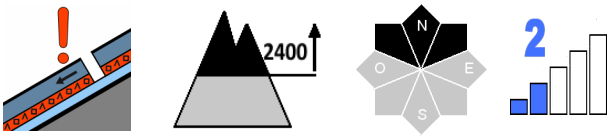	2026-03-22 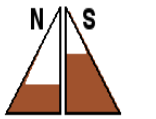 Cota más baja caras N
Ribagorza	**Limitado**	**Nieve húmeda** **Capas débiles persistentes** 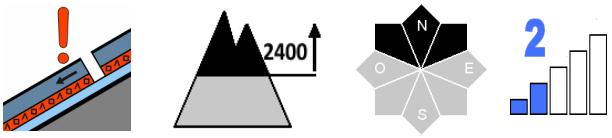	2026-03-22 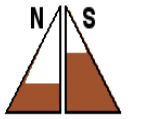 Cota más baja caras N

Estado del manto y observaciones recientes

Continúan los procesos de fusión y apelmazamiento de la nieve, con unos espesores que durante las últimas 24 horas han disminuido entre 1 y 5 cm en los diferentes puntos de observación. El manto sigue presentando continuidad desde medianías, a mayor altitud en orientaciones sur. Los espesores rondan los 40 a 140 cm en torno a 1.800 metros y van aumentando conforme ascendemos, de tal manera que pueden superarse en algunas áreas los 180 a 200 cm en cota 2.100.

La nieve se encuentra muy humedecida en zonas medias y bajas, y también superficialmente en solanas de cotas altas. Generalmente, de cotas medias hacia arriba, está sometida al ciclo de fusión diurna y rehielo nocturno. En las altas umbrías predomina la nieve más seca, venteada y encostrada, pudiendo existir estratos débiles en el interior del manto localizados a no demasiada profundidad y que han dado muestras de actividad en algunos puntos. En dichas umbrías, todavía se observan las antiguas capas débiles persistentes a mayor profundidad, aunque sin indicios de reactividad en los tests por el momento.

Evolución del manto y peligro de aludes para el lunes, día 23

Problema de nieve húmeda. Problema de capas débiles persistentes y placas de viento en cotas altas.

Mañana, con el ascenso de las temperaturas mínimas y la presencia de nubosidad baja durante la noche, se espera que el rehielo efectivo quede más limitado a solanas de cotas altas, estabilizándose solo allí el manto a primeras horas.

Conforme avance el día, serán más probables las purgas de nieve húmeda en pendientes con la suficiente inclinación, sobre todo solanas. Prevalecerán las bolas y coladas, aunque localmente se pueda producir alguno de tamaño mediano, ya sea natural o accidental. Del

AEMET. Se autoriza la reproducción de su contenido citando la fuente.

mismo modo, no se descarta algún deslizamiento basal en zonas de terreno liso o herboso que pueda alcanzar un tamaño mayor.

En umbrías de cotas altas, existen estructuras de placa sobre capa débil de manera aislada, a menudo cerca de crestas y cordales. Estas serán susceptibles de colapsar ante sobrecargas débiles, dando lugar a aludes de tamaño pequeño o mediano, muy raramentemente grande.

En puntos del Pirineo navarro, así como del norte de la Jacetania y la Ribagorza, se podrán formar algunas placas de viento aisladas durante la noche, en cotas altas de orientación sur. Estas permanecerán frágiles y serán susceptibles de provocar aludes de tamaño pequeño.

Predicción meteorológica para el lunes, día 23

Pirineo navarro:
Muy nuboso o cubierto con nubosidad baja, sobre todo en la divisoria fronteriza, tendiendo a despejar en el transcurso del día. Probables precipitaciones débiles en la divisoria fronteriza a primeras horas. Cota de nieve en torno a 1400 metros. Temperaturas con pocos cambios. Las mínimas se podrán dar al final del día. Heladas débiles, localmente moderadas en cotas altas. Viento moderado de componente norte, con intervalos de fuerte en cotas altas y zonas expuestas, tendiendo a flojo de dirección variable a últimas horas.

Pirineo aragonés:
Predominio de poco nuboso o despejado, salvo en la divisoria fronteriza donde se espera nubosidad baja de retención sobre todo de madrugada. No se descartan precipitaciones débiles de madrugada, en puntos de la divisoria fronteriza, más probablemente en Jacetania y Ribagorza. Cota de nieve en torno a 1300 metros.
Temperaturas mínimas en ligero o moderado ascenso, pudiendo darse al final del día. Máximas sin cambios o en ligero descenso. Heladas débiles, localmente moderadas en cotas altas. Viento flojo o moderado de componente norte, con intervalos de fuerte en cotas altas y zonas expuestas a primeras horas, disminuyendo a flojo por la tarde. No se descartan rachas muy fuertes de manera localizada de madrugada.

Datos en la atmósfera libre:

Altitud de la isoterma de 0 ºC: 2200 m
Altitud de la isoterma de -10 ºC: 4100 m

Viento a 1500 m: VRB 5 km/h
Viento a 3000 m: NE 20 km/h

Evolución para el martes día 24

Nivel de peligro con pocos cambios. Ligero aumento de los problemas de nieve húmeda y rehielo nocturno efectivo.

(Información elaborada a partir de los datos recibidos de los refugios de Linza, Lizara, Panticosa, Bachimaña, Góriz, Pineta, Estós, Angel Orús, La Renclusa, Cap de Llauset y Belagua, de las estaciones de esquí de Candanchú, Astún, Formigal y Panticosa (lagos), de la estación de esquí de fondo de Llanos del Hospital y de Ordesa Pradera)

AEMET. Se autoriza la reproducción de su contenido citando la fuente.

Boletín de información nivológica y de peligro de aludes

Pirineo Navarro y Aragonés

Escala europea de peligro de aludes

Débil | Limitado | Notable | Fuerte | Muy Fuerte

Problemas de aludes

Nieve reciente | Placas de viento | Capas débiles persistentes | Nieve húmeda | Deslizamientos basales | Sin problema evidente

Nota1: Se recuerda que, siempre que haya nieve, la ausencia total de peligro no existe. Hay que tener presente que en circunstancias desfavorables, con aludes de tamaño 1 (alud pequeño o colada) y tamaño 2 (alud mediano), se pueden sufrir severos daños personales.

Nota2: Los BPA se elaboran en base a información meteorológica así como al estado del manto nivoso a través de sondeos puntuales. Se advierte a los usuarios de la variabilidad de esta información al extrapolarla a zonas extensas de montaña. Por ello, AEMET no se hace responsable de su uso para la toma de decisiones que conciernen a la seguridad personal, ni de los riesgos físicos o materiales de ellas derivadas.

AEMET. Se autoriza la reproducción de su contenido citando la fuente.