aineva.it

Montag 23.03.2026

Veröffentlicht am 22.03.2026 um 17:00

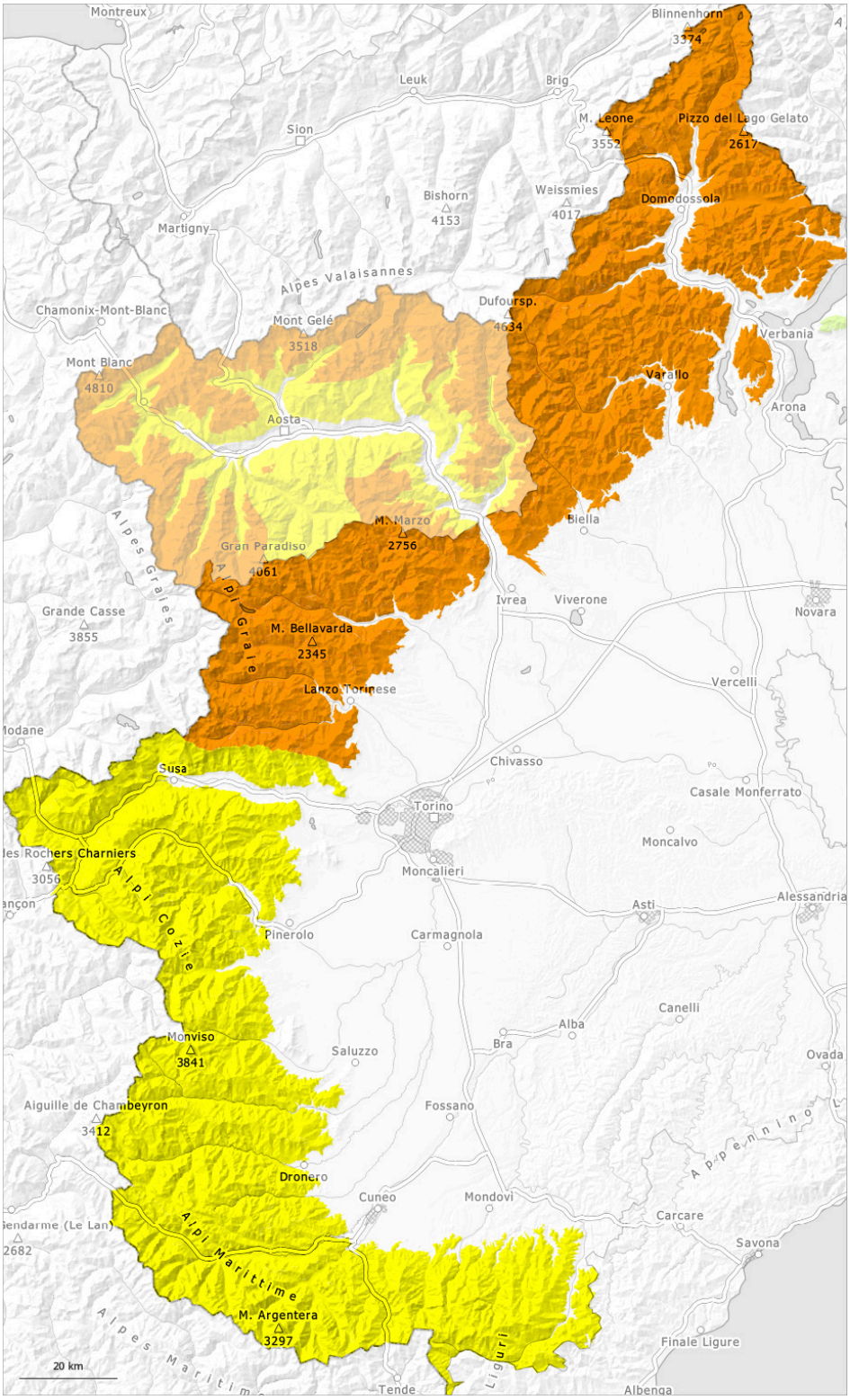

1	2	3	4	5
gering	mäßig	erheblich	groß	sehr groß

Gefahrenstufe 3 - Erheblich

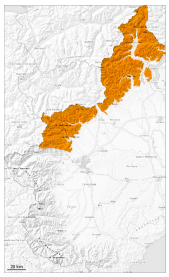

Tendenz: Lawinengefahr bleibt gleich
am Dienstag, den 24.03.2026

Neuschnee

2000m

Nassschnee

2200m

Neuschnee vorsichtig beurteilen.

Es fielen oberhalb von rund 1100 m 20 bis 30 cm Schnee, lokal auch mehr. Der Neuschnee ist vielerorts schlecht mit dem Altschnee verbunden. Die Gefahrenstellen sind überschneit und schwer zu erkennen. Lawinen können v.a. an steilen Schattenhängen im Altschnee anreißen und groß werden. Dies vor allem besonders in mittleren und hohen Lagen.
Mit der tageszeitlichen Erwärmung und der Sonneneinstrahlung sind im Tagesverlauf feuchte und nasse Lawinen möglich, auch große. Dies vor allem an steilen Grashängen in tiefen Lagen sowie an steilen Sonnenhängen in mittleren und hohen Lagen. Touren erfordern eine vorsichtige Routenwahl.

Schneedecke

Gefahrenmuster gm.6: lockerer schnee und wind

In den letzten zwei Tagen fiel Schnee oberhalb von rund 800 m.
Vor allem tiefe und mittlere Lagen, steile Sonnenhänge: Der Neuschnee überlagert eine recht günstige Altschneedecke.
Hohe Lagen und Hochgebirge: Der Neuschnee liegt verbreitet auf einer weichen Altschneeoberfläche.
Sonne und Wärme führen im Tagesverlauf vor allem in tiefen und mittleren Lagen zu einer zunehmenden Anfeuchtung der Schneedecke.

Gefahrenstufe 2 - Mäßig

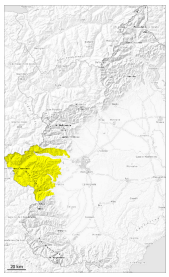

Tendenz: Lawinengefahr bleibt gleich
am Dienstag, den 24.03.2026

Neuschnee

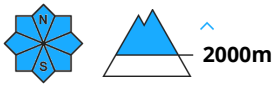

Nassschnee

Trockene Lawinen und feuchte Rutsche im Tagesverlauf sind möglich.

Es fielen oberhalb von rund 1500 m 10 bis 20 cm Schnee. Die Gefahrenstellen sind überschneit und schwer zu erkennen. Lawinen können v.a. an steilen Schattenhängen im Altschnee anreißen und vereinzelt groß werden. Dies vor allem an Übergängen von wenig zu viel Schnee wie z.B. bei der Einfahrt in Rinnen und Mulden in hohen Lagen und im Hochgebirge. Lawinen können vereinzelt schon von einzelnen Wintersportlern ausgelöst werden.
Mit der tageszeitlichen Erwärmung und der Sonneneinstrahlung sind im Tagesverlauf feuchte und nasse Lawinen möglich, vor allem solche mittlerer Größe. Touren erfordern eine vorsichtige Routenwahl.

Schneedecke

Gefahrenmuster gm.6: lockerer schnee und wind

Es fiel Schnee oberhalb von rund 700 m.
Vor allem tiefe und mittlere Lagen, steile Sonnenhänge: Der Neuschnee überlagert eine recht günstige Altschneedecke.
Hohe Lagen und Hochgebirge: Der Neuschnee liegt teilweise auf einer weichen Altschneeoberfläche. Sonne und Wärme führen im Tagesverlauf vor allem in tiefen und mittleren Lagen zu einer zunehmenden Anfeuchtung der Schneedecke.

Gefahrenstufe 2 - Mäßig

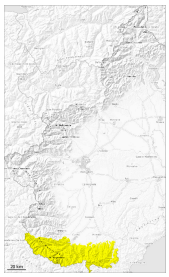

Tendenz: Lawinengefahr bleibt gleich
am Dienstag, den 24.03.2026

Neuschnee

2000m

Nassschnee

Die Gefahrenstellen sind überschneit und schwer zu erkennen.

Es fielen oberhalb von rund 2000 m 5 bis 15 cm Schnee. Die Gefahrenstellen sind überschneit und schwer zu erkennen. Die schon etwas älteren Triebschneeansammlungen können an steilen Schattenhängen in hohen Lagen und im Hochgebirge vor allem mit großer Zusatzbelastung ausgelöst werden. Dies vor allem an Übergängen von wenig zu viel Schnee wie z.B. bei der Einfahrt in Rinnen und Mulden. Mit der tageszeitlichen Erwärmung und der Sonneneinstrahlung sind im Tagesverlauf feuchte und nasse Lawinen möglich, vor allem solche mittlerer Größe.

Schneedecke

Gefahrenmuster gm.6: lockerer schnee und wind

Es fiel Schnee oberhalb von rund 900 m.
Vor allem tiefe und mittlere Lagen, steile Sonnenhänge: Der Neuschnee überlagert eine recht günstige Altschneedecke.
Hohe Lagen und Hochgebirge: Der Neuschnee liegt teilweise auf einer weichen Altschneeoberfläche. V.a. in der Höhe liegen je nach Windeinfluss sehr unterschiedliche Schneehöhen. Sonne und Wärme führen im Tagesverlauf vor allem in tiefen und mittleren Lagen zu einer zunehmenden Anfeuchtung der Schneedecke.

Gefahrenstufe 2 - Mäßig

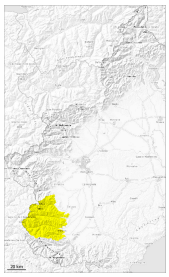

Tendenz: Lawinengefahr bleibt gleich
am Dienstag, den 24.03.2026

Neuschnee

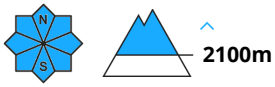

Nassschnee

Trockene Lawinen und feuchte Rutsche im Tagesverlauf sind möglich.

Es fielen oberhalb von rund 2000 m 15 bis 25 cm Schnee. Die Gefahrenstellen sind überschneit und schwer zu erkennen. Lawinen können v.a. an steilen Schattenhängen im Altschnee anreißen und vereinzelt groß werden. Dies vor allem an Übergängen von wenig zu viel Schnee wie z.B. bei der Einfahrt in Rinnen und Mulden in hohen Lagen und im Hochgebirge. Lawinen können vereinzelt schon von einzelnen Wintersportlern ausgelöst werden. Entlang der Grenze zu Frankreich ist die Situation etwas gefährlicher. Mit der tageszeitlichen Erwärmung und der Sonneneinstrahlung sind im Tagesverlauf feuchte und nasse Lawinen möglich, vor allem solche mittlerer Größe. Touren erfordern eine vorsichtige Routenwahl.

Schneedecke

Gefahrenmuster gm.6: lockerer schnee und wind

Es fiel Schnee oberhalb von rund 700 m.
Vor allem tiefe und mittlere Lagen, steile Sonnenhänge: Der Neuschnee überlagert eine recht günstige Altschneedecke.
Hohe Lagen und Hochgebirge: Der Neuschnee liegt teilweise auf einer weichen Altschneeoberfläche. Sonne und Wärme führen im Tagesverlauf vor allem in tiefen und mittleren Lagen zu einer zunehmenden Anfeuchtung der Schneedecke.