Lunedì 23.03.2026

Pubblicato il 22.03.2026 alle ore 17:00

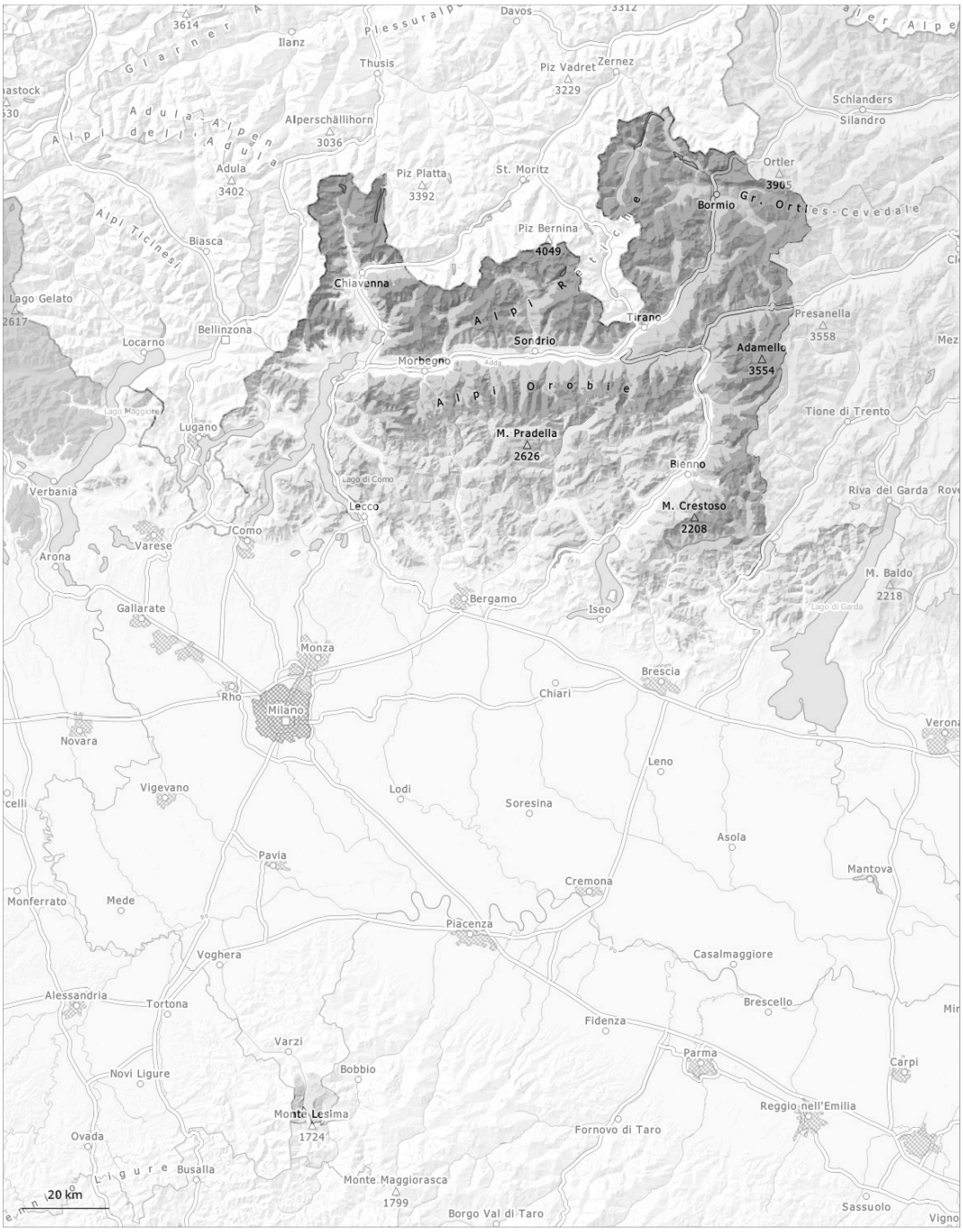

1	2	3	4	5
debole	moderato	marcato	forte	molto forte

Grado di pericolo 3 - Marcato

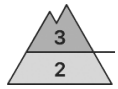

Limite del bosco

Tendenza: pericolo valanghe stabile
per Martedì il 24.03.2026

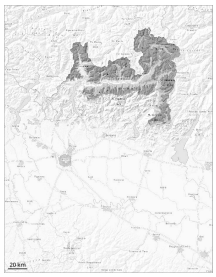

Lastrone da vento

Limite del bosco

Strati deboli persistenti

1900m

A livello locale sono caduti localmente sino a 15 cm di neve. La poca neve fresca e gli accumuli di neve ventata devono essere valutati con attenzione a tutte le esposizioni. La neve ventata è la principale fonte di pericolo.

A livello locale, da sabato è caduta neve sino a 1200 m. Gli accumuli di neve ventata dell'ultima settimana rappresentano la principale fonte di pericolo. Gli accumuli di neve ventata devono essere valutati con attenzione a tutte le esposizioni. Essi possono subire molto facilmente un distacco provocato. Questi ultimi si sono formati principalmente nelle conche, nei canaloni e dietro ai cambi di pendenza. Sui pendii esposti a nord ovest, nord e nord est, all'interno del manto di neve vecchia si trovano strati fragili. Le valanghe possono coinvolgere il manto di neve vecchia, soprattutto sui pendii esposti a nord ovest, nord e nord est, raggiungere grandi dimensioni.
Le attività sportive fuoripista richiedono esperienza e la massima prudenza.

Manto nevoso

Situazione tipo st.6: neve a debole coesione e vento | st.1: strato debole persistente basale

La poca neve fresca del fine settimana e soprattutto gli accumuli di neve ventata che si sono formati con il vento di forte intensità poggiano su una sfavorevole superficie del manto di neve vecchia.
Il forte vento ha causato il trasporto della neve. Principalmente sui pendii ombreggiati, all'interno del manto di neve vecchia si trovano isolati strati fragili. In alcuni punti, le valanghe possono subire un distacco negli strati profondi del manto nevoso soprattutto sui pendii esposti a nord ovest, nord e nord est.

Grado di pericolo 2 - Moderato

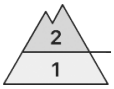

1500m

Tendenza: pericolo valanghe in diminuzione
per Martedì il 24.03.2026

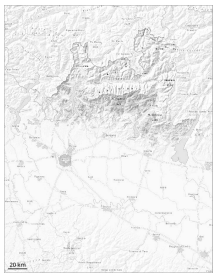

Lastrone da vento

1500m

Neve bagnata

1300m

Neve ventata e neve bagnata sono la principale fonte di pericolo.

Con il rialzo termico diurno, sono possibili isolate valanghe bagnate di dimensioni medio-piccole al di sopra dei 1300 m circa.
In prossimità delle cime, la situazione valanghiva è a livello locale pericolosa. Gli ultimi accumuli di neve ventata sono ben individuabili e possono facilmente subire un distacco.
Le valanghe possono trascinare l'interno manto nevoso e in parte raggiungere dimensioni medie.

Manto nevoso

Situazione tipo st.10: situazione primaverile | st.6: neve a debole coesione e vento

Nel corso della giornata l'irradiazione solare causerà un rapido inumidimento del manto nevoso.

Grado di pericolo 1 - Debole

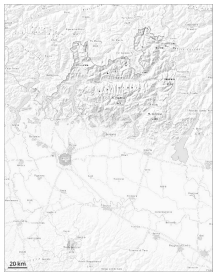

Tendenza: pericolo valanghe stabile
per Martedì il 24.03.2026

Neve bagnata

1300m

La neve bagnata è la principale fonte di pericolo.

Con il rialzo termico diurno, nel corso della giornata il pericolo di valanghe bagnate aumenterà. Al di sopra dei 1300 m circa sono possibili valanghe umide e bagnate di piccole dimensioni.

Manto nevoso

Situazione tipo st.10: situazione primaverile

Il manto nevoso è umido a livello generale.