BUTLLETÍ DEL PERILL D'ALLAUS DEL PRINCIPAT D'ANDORRA

Servei meteorològic nacional
Principat d'Andorra

Elaborat el 22/03/2026 16:00
Propera actualització 23/03/2026 a les 16h

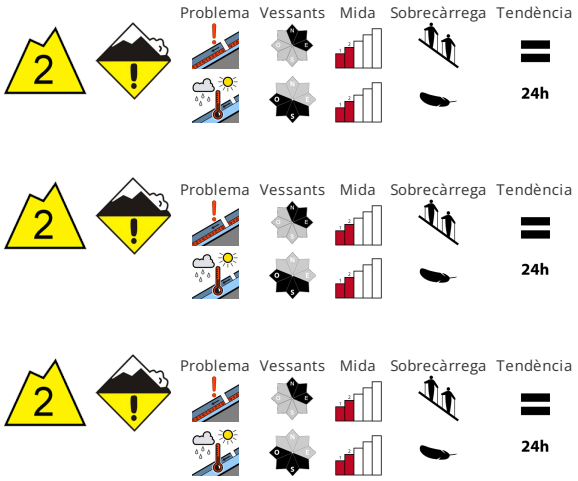

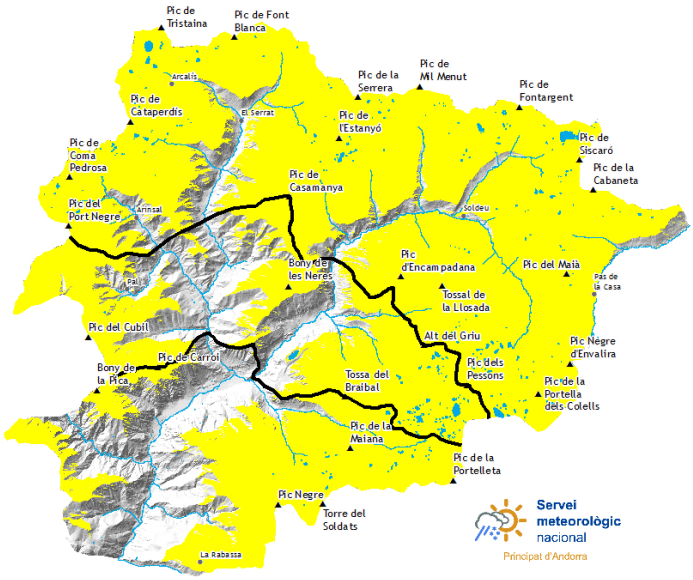

ESTABILITAT DEL MANTELL NIVAL

A cotes altes als vessants obacs : A la part superior del mantell de neu hi ha, de manera aïllada, capes febles. Aquestes poden ser desencadenades sobretot per una sobrecàrrega forta i assolir mida mitjana. En el transcurs de la nit , amb la neu recent i el vent de nord moderat , es formaran plaques de vent de mida petita localment. Amb la humidificació, en el transcurs de la jornada són possibles allaus de neu humida , però majoritàriament petites. Això es dona especialment en vessants assolellats inclinats per sota dels 2200 m aproximadament.

QUALITAT DE LA NEU

Fins al dilluns caurà una mica de neu sobretot als al nord. A partir del matí el temps serà força assolellat. A cotes baixes i mitges :. La superfície del mantell de neu es refredarà tot just durant la nit ennuvolada i s'estovarà al llarg del dia. Prop de les carenes els gruixos de neu varien molt per la influència del vent. Les capes febles a la part superior del mantell de neu requereixen cautela. Es recomana mantenir la distància entre els components.

GRUIXOS DEL MANTELL NIVAL FORA DE PISTA

Zona nord		Gruix neu		
Mantell Nival		1500m	2000m	2500m
N	1600 m	0 cm	150 cm	200 cm
S	1900 m	0 cm	100 cm	150 cm

Zona centre		Gruix neu		
Mantell Nival		1500m	2000m	2500m
N	1600 m	0 cm	150 cm	200 cm
S	1900 m	0 cm	100 cm	150 cm

Zona sud		Gruix neu		
Mantell Nival		1500m	2000m	2500m
N	1600 m	0 cm	120 cm	150 cm
S	1900 m	0 cm	60 cm	100 cm

Govern d'Andorra

EAWS EUROPEAN AVALANCHE WARNING SERVICES

Aquest butlletí ha estat elaborat seguint les normes i recomanacions de l'**European Avalanche Warning Services**, del qual el **Servei meteorològic Nacional** n'és membre

BUTLLETÍ DEL PERILL D'ALLAUS DEL PRINCIPAT D'ANDORRA

Servei meteorològic nacional
Principat d'Andorra

Informació detallada per espais naturals protegits

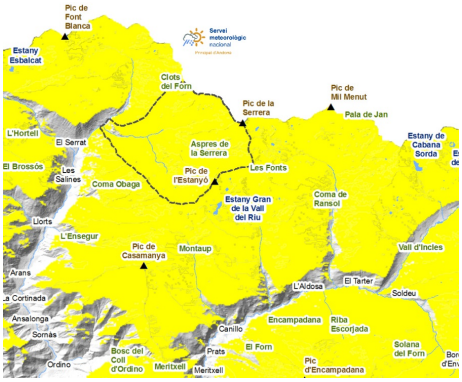

SORTENY

Les febles nevades de la tarda del diumenge no canviaran l´estabilitat del mantell. Haurem de continuar mantenint la cautela en els vessants nord i est on poden haver-hi capes febles persistents. En el transcurs de la jornada i amb la penetració de la humitat, tornarem a tenir neu tova i humida per sota de 2.200 metres.

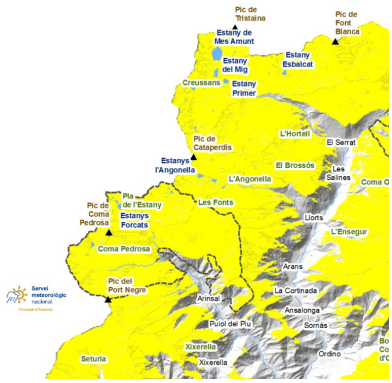

COMAPEDROSA

Com a tot el país, als vessants nord i est trobem capes febles encara sol·licitables, amb les que haurem de fer atenció. A mida que avanci el dia també haurem de prestar atenció als problemes de neu humida en els vessants assolellats més inclinats i als peus de parets rocoses. Esperem activitat d´allaus de fons amb les esquerdes obertes.

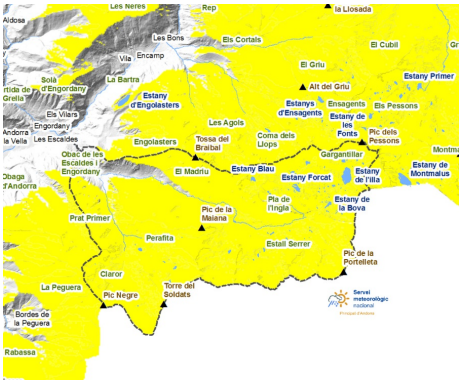

MADRIU-PERAFITA-CLAROR

Amb la precipitació i humitat de la nit de diumenge la neu patirà un retrocés important a cotes baixes, tot i que encara hi ha neu suficient per fer nombroses rutes. Haurem de ser cautelosos als vessants amb problemes de capes febles persistents.

Govern d'Andorra

EAWS
EUROPEAN AVALANCHE WARNING SERVICES

Aquest butlletí ha estat elaborat seguint les normes i recomanacions de l'**European Avalanche Warning Services**, del qual el **Servei meteorològic Nacional** n'és membre

BUTLLETÍ DEL PERILL D'ALLAUS DEL PRINCIPAT D'ANDORRA

Servei meteorològic nacional
Principat d'Andorra

Gruixos de neu nova dels darrers dies (de les últimes 24h mesurat a les 06:00h UTC)

	18/03/2026	19/03/2026	20/03/2026	21/03/2026
FEDA (Central)	0 cm	0 cm	0 cm	0 cm
Engolasters - FEDA	0 cm	0 cm	0 cm	0 cm
Ransol - FEDA	0 cm	0 cm	0 cm	0 cm
Fontverd	0 cm	0 cm	0 cm	0 cm
Bony de les Neres	0 cm	0 cm	0 cm	0 cm
Grau Roig - FEDA	1 cm	0 cm	0 cm	0 cm
Caborreu	0 cm	0 cm	0 cm	0 cm
Sorteny	0 cm	0 cm	0 cm	0 cm
Coll Pa	3 cm	0 cm	0 cm	0 cm
Perafita	0 cm	0 cm	0 cm	0 cm
Tossa Espiolets	0 cm	0 cm	0 cm	0 cm
La Solana	0 cm	0 cm	0 cm	0 cm
Vall del Riu FEDA	2 cm	0 cm	0 cm	0 cm
Envalira Antenes	0 cm	0 cm	0 cm	0 cm
Les Fonts d'Arinsal	0 cm	0 cm	0 cm	0 cm