BUTLLETÍ DEL PERILL D'ALLAUS DEL PRINCIPAT D'ANDORRA

Elaborado el 22/03/2026 16:00
Proxima actualización 23/03/2026 a las 16h

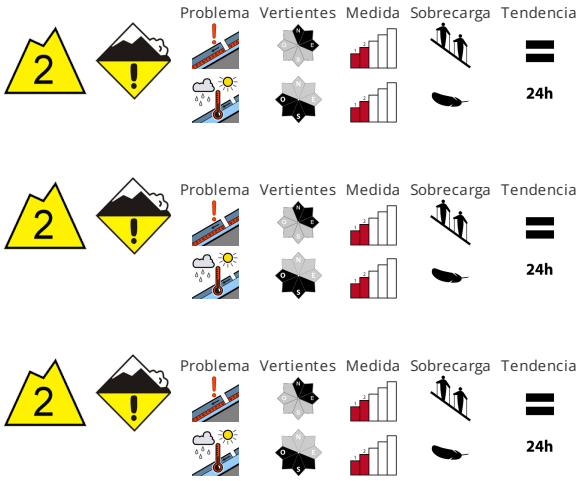

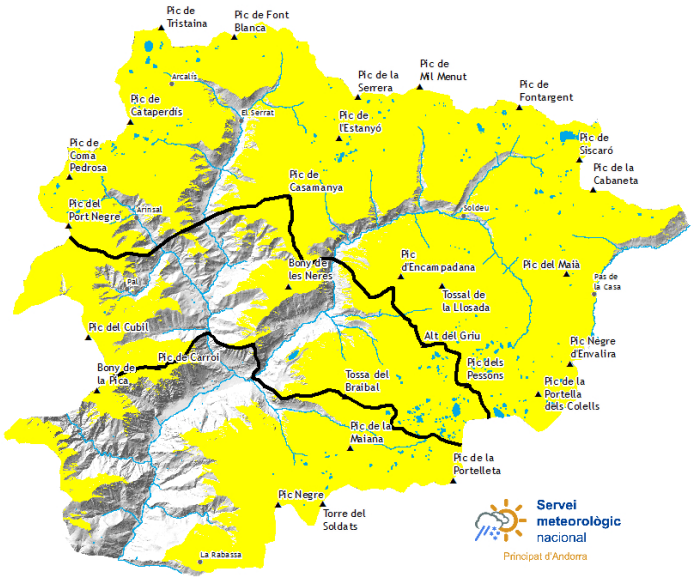

CALIDAD DE LA NIEVE

En cotas altas en las laderas umbrías :. En la parte superior del manto de nieve hay, de manera aislada, capas débiles. Estos pueden ser desencadenadas sobre todo por una sobrecarga fuerte y alcanzar un tamaño mediano. En el transcurso de la noche , con , se formarán pequeñas placas de viento localmente. Con la humidificación, en el transcurso de la jornada son posibles avalanchas de nieve húmeda , pero en su mayoría pequeñas. Esto se da especialmente en las laderas solanas inclinadas por debajo de los 2200 m aproximadamente.

ESTABILIDAD DEL MANTO NIVOSO

Hasta el lunes caerá un poco de nieve sobre todo en los norte. A partir de la mañana el tiempo será bastante soleado. En cotas bajas y medias :. La superficie del manto de nieve se enfriará apenas durante la noche nublada y se ablandará durante el día. Cerca de los cordales los espesores de nieve varían mucho por la influencia del viento. Las capas débiles en la parte superior del manto de nieve requieren cautela. Se recomienda mantener la distancia de seguridad entre los miembros del grupo.

ESPESORES DEL MANTO NIVOSO FUERA DE PISTA

Zona norte		Espesor nieve		
Manto Nival		1500m	2000m	2500m
N	1600 m	0 cm	150 cm	200 cm
S	1900 m	0 cm	100 cm	150 cm

zona centro		Espesor nieve		
Manto Nival		1500m	2000m	2500m
N	1600 m	0 cm	150 cm	200 cm
S	1900 m	0 cm	100 cm	150 cm

Zona sur		Espesor nieve		
Manto Nival		1500m	2000m	2500m
N	1600 m	0 cm	120 cm	150 cm
S	1900 m	0 cm	60 cm	100 cm

Govern d'Andorra

Aquest butlletí ha estat elaborat seguint les normes i recomanacions de l'**European Avalanche Warning Services**, del qual el **Servei meteorològic Nacional** n'és membre

BUTLLETÍ DEL PERILL D'ALLAUS DEL PRINCIPAT D'ANDORRA

Servei meteorològic nacional
Principat d'Andorra

Información detallada por espacios naturales protegidos

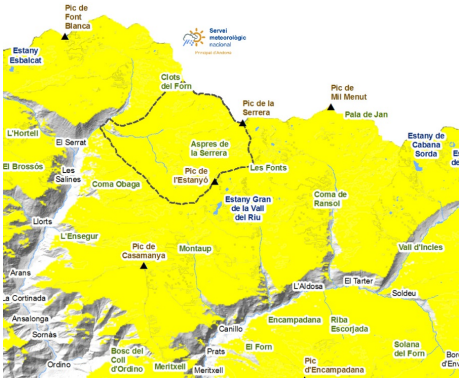

SORTENY

Las débiles nevadas de la tarde del domingo no cambiarán la estabilidad del manto. Deberemos continuar manteniendo la cautela en las vertientes norte y este donde pueden existir capas débiles persistentes. En el transcurso de la jornada y con la penetración de la humedad, volveremos a tener nieve blanda y húmeda por debajo de 2.200 metros.

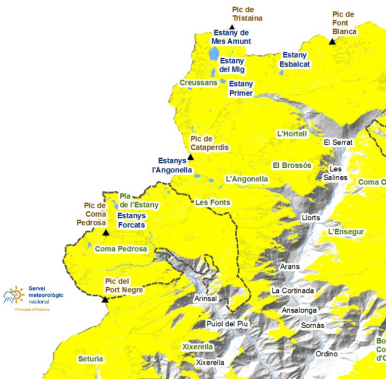

COMAPEDROSA

Como en todo el país, en las vertientes norte y este encontramos capas débiles todavía solicitables, con las que deberemos prestar atención. A medida que avance el día también deberemos prestar atención a los problemas de nieve húmeda en las vertientes soleadas más inclinadas ya los pies de paredes rocosas. Esperamos actividad de aludes de fondo con las grietas abiertas.

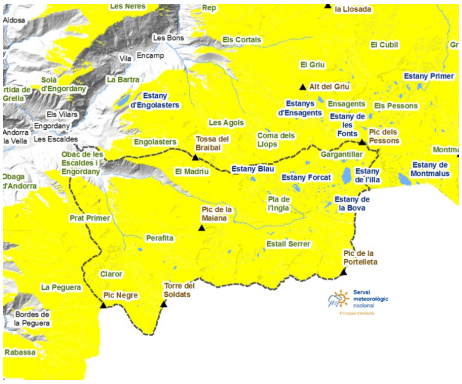

MADRIU-PERAFITA-CLAROR

Con la precipitación y humedad de la noche del domingo la nieve sufrirá un retroceso importante en cotas bajas, aunque todavía hay nieve suficiente para realizar numerosas rutas. Deberemos ser cautelosos en las laderas con problemas de capas débiles persistentes.

Govern d'Andorra

EAWS
EUROPEAN AVALANCHE WARNING SERVICES

Aquest butlletí ha estat elaborat seguint les normes i recomanacions de l'**European Avalanche Warning Services**, del qual el **Servei meteorològic Nacional** n'és membre

BUTLLETÍ DEL PERILL D'ALLAUS DEL PRINCIPAT D'ANDORRA

Servei meteorològic nacional
Principat d'Andorra

Espesores de nieve nueva de los últimos días (de las ultimas 24h mesurado a las 06:00h UTC)

	18/03/2026	19/03/2026	20/03/2026	21/03/2026
FEDA (Central)	0 cm	0 cm	0 cm	0 cm
Engolasters - FEDA	0 cm	0 cm	0 cm	0 cm
Ransol - FEDA	0 cm	0 cm	0 cm	0 cm
Fontverd	0 cm	0 cm	0 cm	0 cm
Bony de les Neres	0 cm	0 cm	0 cm	0 cm
Grau Roig - FEDA	1 cm	0 cm	0 cm	0 cm
Caborreu	0 cm	0 cm	0 cm	0 cm
Sorteny	0 cm	0 cm	0 cm	0 cm
Coll Pa	3 cm	0 cm	0 cm	0 cm
Perafita	0 cm	0 cm	0 cm	0 cm
Tossa Espiolets	0 cm	0 cm	0 cm	0 cm
La Solana	0 cm	0 cm	0 cm	0 cm
Vall del Riu FEDA	2 cm	0 cm	0 cm	0 cm
Envalira Antenes	0 cm	0 cm	0 cm	0 cm
Les Fonts d'Arinsal	0 cm	0 cm	0 cm	0 cm