BUTLLETÍ DEL PERILL D'ALLAUS DEL PRINCIPAT D'ANDORRA

Préparé le 22/03/2026 16:00
Prochaine mise à jour le 23/03/2026 à 16h

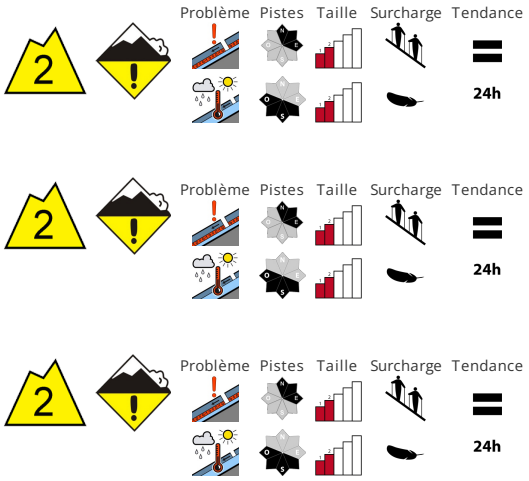

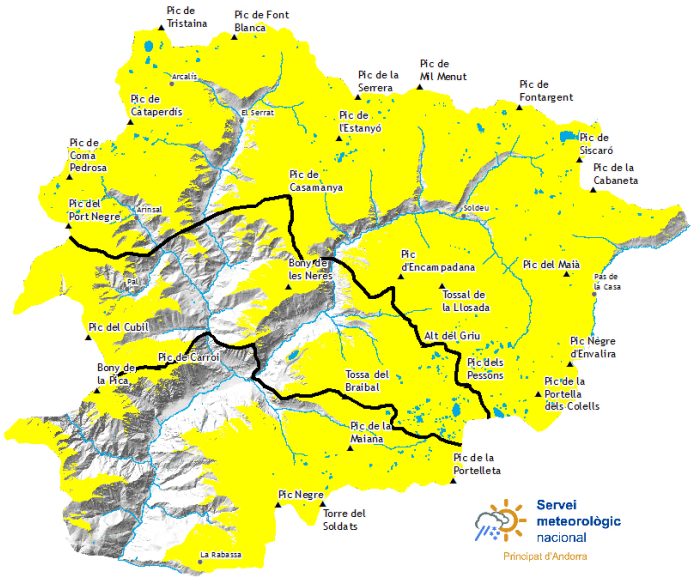

STABILITÉ DU MANTEAU NEIGEUX

À haute altitude sur les pentes à l'ombre (-):. Dans la partie supérieure du manteau neigeux des couches fragiles très isolées sont présentes ils se rencontrent. Celles-ci peuvent peut être déchaîné surtout avec une surcharge importante et atteindre une taille moyenne.. De petites accumulations de neige soufflée de petites se forment avec en cours de nuit localement. Avec l'humidification en cours de journée des avalanches humides sont possibles ils sont , mais en général uniquement de petite taille. Ceci surtout sur les pentes raides ensoleillées en dessous d'environ 2200 m.

QUALITÈ DE LA NEIGE

Jusqu'à lundi il tombera un peu de neige surtout au nord. À partir du matin il fait un temps généralement ensoleillé. À basses et moyennes altitudes (-):. La surface de la neige ne se refroidit qu'à peine pendant la nuit couverte et se ramollit en cours de journée.. À proximité des crêtes on trouve suivant l'influence du vent des hauteurs de neiges très différentes. Des couches fragiles en partie supérieure du manteau neigeux demandent de la prudence.. Des distances de délestage sont recommandées..

EPAISSEUR DE NEIGE HORS PISTE

Zone nord		Epaisseur de neige		
Nival manteau		1500m	2000m	2500m
N	1600 m	0 cm	150 cm	200 cm
S	1900 m	0 cm	100 cm	150 cm

Zone centre		Epaisseur de neige		
Nival manteau		1500m	2000m	2500m
N	1600 m	0 cm	150 cm	200 cm
S	1900 m	0 cm	100 cm	150 cm

Zone sud		Epaisseur de neige		
Nival manteau		1500m	2000m	2500m
N	1600 m	0 cm	120 cm	150 cm
S	1900 m	0 cm	60 cm	100 cm

Govern d'Andorra

EAWS EUROPEAN AVALANCHE WARNING SERVICES

Aquest butlletí ha estat elaborat seguint les normes i recomanacions de l'**European Avalanche Warning Services**, del qual el **Servei meteorològic Nacional** n'és membre

BUTLLETÍ DEL PERILL D'ALLAUS DEL PRINCIPAT D'ANDORRA

Servei meteorològic nacional
Principat d'Andorra

Des informations détaillées par espace naturel protégé

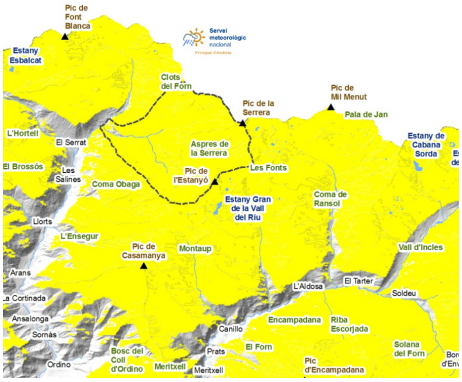

SORTENY

La légère neige de dimanche après-midi ne modifiera pas la stabilité du manteau. Il faudra continuer à rester prudent sur les versants Nord et Est où des couches faibles persistantes pourraient persister. Au cours de la journée et avec la pénétration de l'humidité, nous aurons à nouveau de la neige molle et mouillée en dessous de 2 200 mètres. , , , , ,

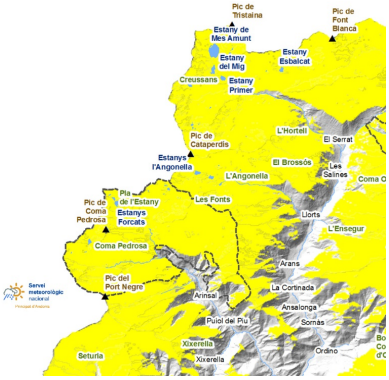

COMAPEDROSA

Comme dans tout le pays, sur les versants nord et est, nous trouvons des couches faibles encore applicables, auxquelles nous devrons faire attention. Au fil de la journée, il faudra également faire attention aux problèmes de neige mouillée sur les pentes plus raides et ensoleillées et au pied des parois rocheuses. Nous nous attendons à une activité avalancheuse en arrière-plan avec les fissures ouvertes. , , , , ,

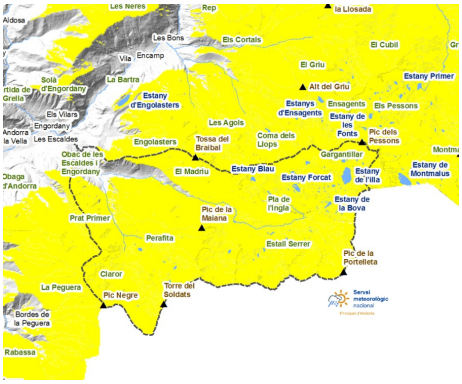

MADRIU-PERAFITA-CLAROR

Avec les précipitations et l'humidité de dimanche soir, la neige reculera considérablement à basse altitude, même s'il reste encore suffisamment de neige pour couvrir de nombreux itinéraires. Il faudra être prudent sur les pentes présentant des problèmes persistants de couches fragiles. , , ,

Govern d'Andorra

EAWS
EUROPEAN AVALANCHE WARNING SERVICES

Aquest butlletí ha estat elaborat seguint les normes i recomanacions de l'**European Avalanche Warning Services**, del qual el **Servei meteorològic Nacional** n'és membre

BUTLLETÍ DEL PERILL D'ALLAUS DEL PRINCIPAT D'ANDORRA

Servei meteorològic nacional
Principat d'Andorra

Couche de neige fraiche des derniers jours (De 24 h mesurée à 06:00 h UTC)

	18/03/2026	19/03/2026	20/03/2026	21/03/2026
FEDA (Central)	0 cm	0 cm	0 cm	0 cm
Engolasters - FEDA	0 cm	0 cm	0 cm	0 cm
Ransol - FEDA	0 cm	0 cm	0 cm	0 cm
Fontverd	0 cm	0 cm	0 cm	0 cm
Bony de les Neres	0 cm	0 cm	0 cm	0 cm
Grau Roig - FEDA	1 cm	0 cm	0 cm	0 cm
Caborreu	0 cm	0 cm	0 cm	0 cm
Sorteny	0 cm	0 cm	0 cm	0 cm
Coll Pa	3 cm	0 cm	0 cm	0 cm
Perafita	0 cm	0 cm	0 cm	0 cm
Tossa Espiolets	0 cm	0 cm	0 cm	0 cm
La Solana	0 cm	0 cm	0 cm	0 cm
Vall del Riu FEDA	2 cm	0 cm	0 cm	0 cm
Envalira Antenes	0 cm	0 cm	0 cm	0 cm
Les Fonts d'Arinsal	0 cm	0 cm	0 cm	0 cm