RÉPUBLIQUE FRANÇAISE
Liberté Égalité Fraternité

METEO FRANCE
À VOS CÔTÉS, DANS UN CLIMAT QUI CHANGE

Bulletin d'estimation du risque d'avalanche
(valable en dehors des pistes balisées et ouvertes)

MASSIF : Queyras

Rédigé le dimanche 22 mars 2026 à 10h

Estimation des risques pour le : DIMANCHE 22 MARS

NOUVELLES PLAQUES EN FORMATION LOCALEMENT ÉPAISSES AVEC LES CHUTES DE NEIGE

3

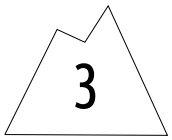

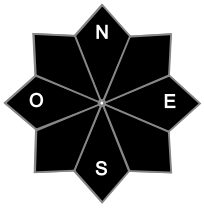

Indice de risque marqué.

Départs spontanés : dans la neige fraîche pendant les chutes.

Déclenchements provoqués : plaques à vent en formation dans la neige fraîche, localement épaisses

Indices de risque : 5 très fort - 4 fort - 3 marqué - 2 limité - 1 faible -- En noir : les pentes les plus dangereuses

Stabilité du manteau neigeux

Situation avalancheuse typique : neige fraîche neige ventée

Déclenchements provoqués : plaques en formation dans toutes les orientations dans la neige fraîche, sous l'action de chutes de neige accompagnées d'une Lombarde modérée. Plaques localement épaisses et facilement déclenchables, plutôt à proximité des crêtes et ruptures de pente. Elles peuvent générer des avalanches de taille moyenne (taille 2) en général, voire grande (taille 3) dans un couloir chargé.

Départs spontanés : petites ou moyennes avalanches (taille 1 à 2) de neige fraîche en pentes raides au fil des chutes de neige.

Qualité de la neige

L'enneigement est proche des normales pour une mi-mars.
Hauteurs de neige observées : 160 cm en versant nord du col Izoard à 2300 m, 146 cm au-dessus de St Véran à 2700 m, 94 cm à la Nivôse du Col Agnel à 2630 m, 59 cm à Ristolas à 1670 m.

Limite d'enneigement skiable : au plus bas à 1600 m en ubacs bien protégés ou sur pistes forestières, plutôt 2000 m en adrets.

État de la neige de surface : on retrouve en surface 10/15 cm localement 20/30 cm de neige froide, qui repose sur un manteau neigeux printanier bien croûté en sud. En large versant nord au-dessus de 2200/2300 m, elle repose sur une neige plus sèche, travaillée par le vent ou encore d'aspect poudreux.

Aperçu météo pour le dimanche 22 mars

	nuit	matin	après-midi	soir

Chutes de neige apportant une dizaine de cm, localement 20/30 cm dans le secteur de Ceillac/St Véran/Col Agnel.

Pluie-Neige	1 400 m	1 200 m	1 100 m	
Iso 0 °C	1 800 m	1 500 m	1 500 m	1 400 m
Vent 2000 m	← 15 km/h	← 25 km/h	↙ 30 km/h	↙ 15 km/h
Vent 3000 m	→ 20 km/h	← 30 km/h	← 35 km/h	← 20 km/h

Épaisseur de neige hors-piste

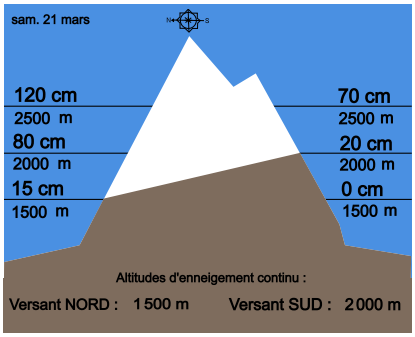

Précipitations à 1800 m

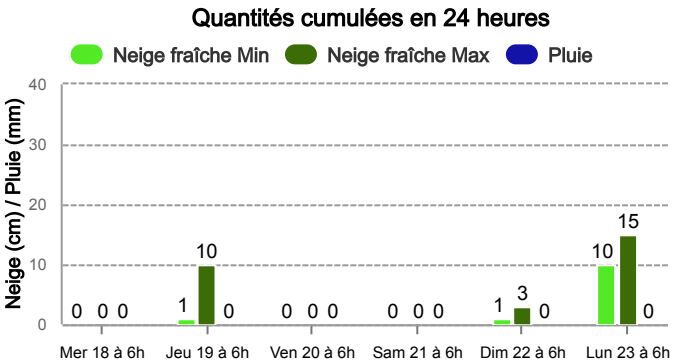

Tendance du lundi 23 mars

3

Indice de risque marqué

Maintien probable d'un risque marqué avec la présence de plaques dans la neige récente. Avec le retour du soleil, activité en neige humide en sud.

Pour consulter la vigilance en cours, veuillez vous rendre sur le site https://vigilance.meteofrance.fr/fr

Météo-France - 73 avenue de Paris, 94165 Saint-Mandé cedex - Contact : contact@meteo.fr

Rédigé par Météo-France avec la contribution des observateurs du réseau nivo-météorologiques. Partenariat : ANMSM (Maires de Stations de Montagne), DSF (Domaines Skiables de France), ADSP (Directeurs de Pistes et de la Sécurité des Stations de Sports d'Hiver) et autres acteurs de la montagne.

Bulletin neige & avalanches par téléphone au
0 892 68 10 20 Service 0,35 € / min + prix appel

RÉPUBLIQUE FRANÇAISE
Liberté Égalité Fraternité

METEO FRANCE
À VOS CÔTÉS, DANS UN CLIMAT QUI CHANGE

Bulletin d'estimation du risque d'avalanche

(valable en dehors des pistes balisées et ouvertes)

MASSIF : Queyras

Rédigé le dimanche 22 mars 2026 à 10h

Conditions nivo-météo des 7 derniers jours

	dim. 15/03				lun. 16/03				mar. 17/03				mer. 18/03				jeu. 19/03				ven. 20/03				sam. 21/03			
	03h	09h	15h	21h	03h	09h	15h	21h	03h	09h	15h	21h	03h	09h	15h	21h	03h	09h	15h	21h	03h	09h	15h	21h	03h	09h	15h	21h
Météo																												
Vent (km/h)	40	50	30	10	20	30	30	25	25	15	20	15	20	40	70	70	55	35	30	25	20	15	5	10	15	15	15	15
à 3000m																												
Vent (km/h)	15	30	25	10	10	20	30	15	10	10	15	10	10	30	40	30	25	20	20	15	15	10	15	5	5	10	15	10
à 2000m																												

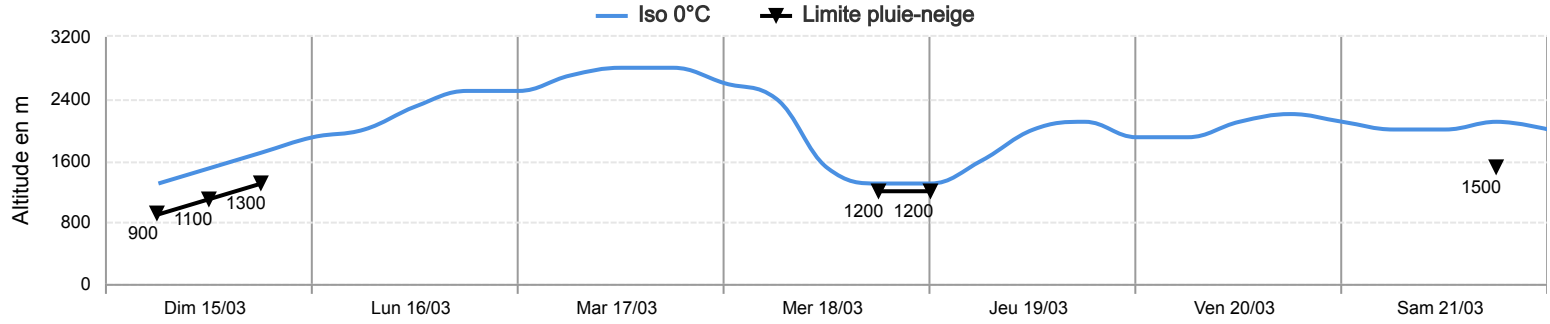

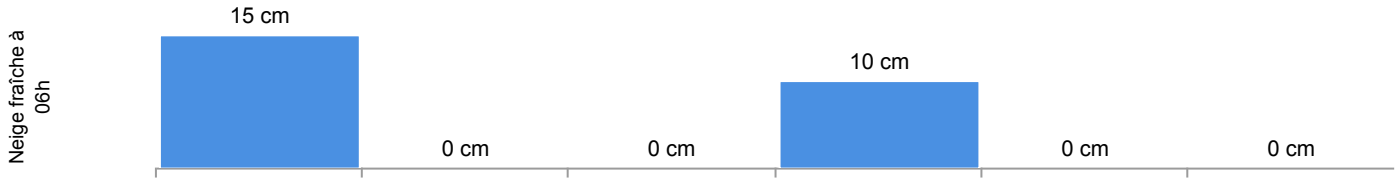

Risque d'avalanche	dim. 15/03	lun. 16/03	mar. 17/03	mer. 18/03	jeu. 19/03	ven. 20/03	sam. 21/03
		3	3	3	3	2	2

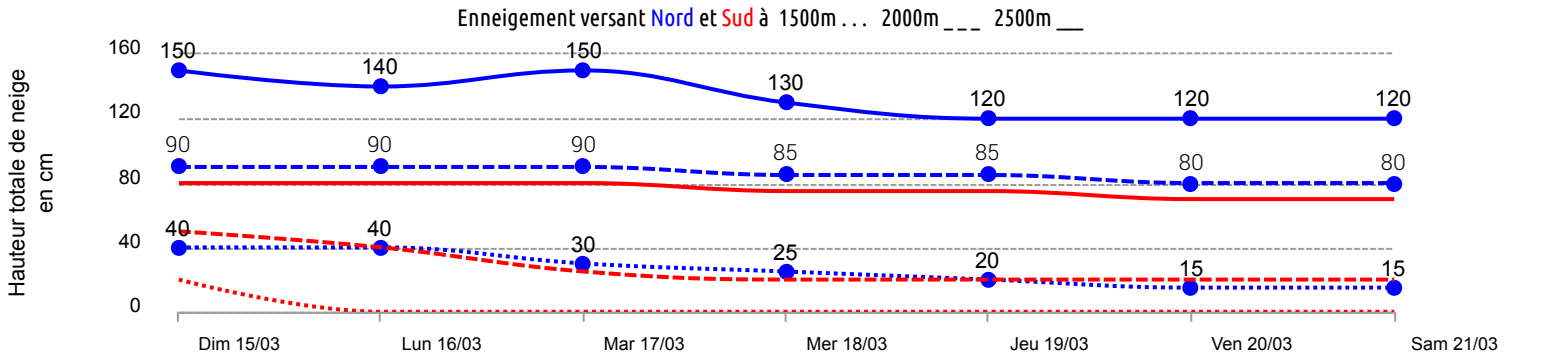

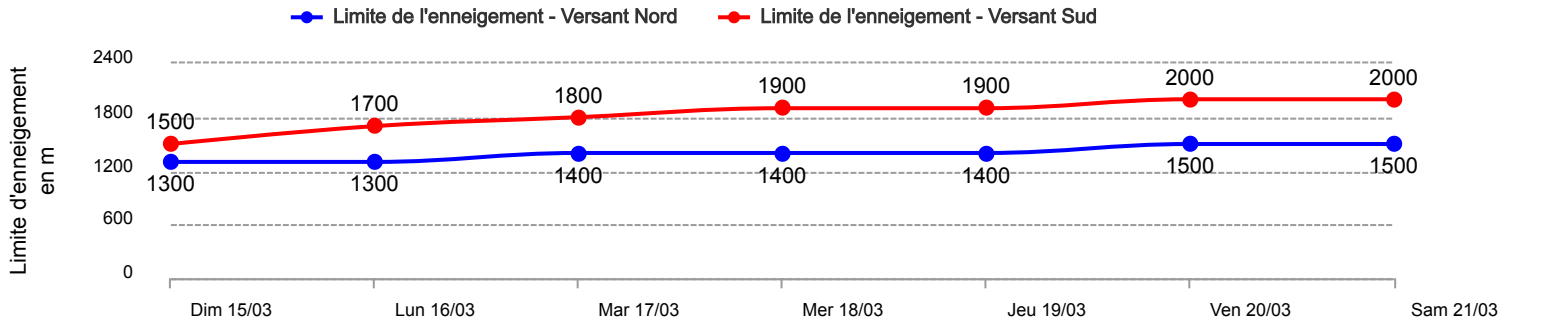

Pour consulter la vigilance en cours, veuillez vous rendre sur le site https://vigilance.meteofrance.fr/fr

Météo-France - 73 avenue de Paris, 94165 Saint-Mandé cedex - Contact : contact@meteo.fr

Bulletin neige & avalanches par téléphone au

0 892 68 10 20 Service 0,35 € / min + prix appel

Rédigé par Météo-France avec la contribution des observateurs du réseau nivo-météorologiques. Partenariat : ANMSM (Maires de Stations de Montagne), DSF (Domaines Skiables de France), ADSP (Directeurs de Pistes et de la Sécurité des Stations de Sports d'Hiver) et autres acteurs de la montagne.