Bulletin d'estimation du risque d'avalanche
(valable en dehors des pistes balisées et ouvertes)

MASSIF : Aravis

Rédigé le dimanche 22 mars 2026 à 16h

Estimation des risques pour le : LUNDI 23 MARS

INSTABILITÉS DANS LA NEIGE RÉCENTE, NOUVELLES PLAQUES À VENT

2

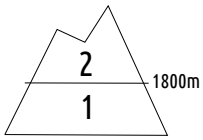

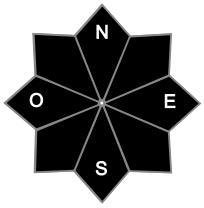

Au-dessus de 1800m indice de risque limité, plus bas indice faible.

Départs spontanés : Départ en plaque à cause du transport de neige par le vent

Déclenchements provoqués : Instabilités dans la neige fraiche et neige ventée

Indices de risque : 5 très fort - 4 fort - 3 marqué - 2 limité - 1 faible -- En noir : les pentes les plus dangereuses

Stabilité du manteau neigeux

Situation avalancheuse typique : neige fraîche neige ventée

Déclenchements provoqués :
* Quelques instabilités dans la neige fraiche au-dessus de 1800 m sont encore présentes, réactives au passage d'un skieur. Taille 1 voir 2 (petite voir moyenne).
* Plaques à vent formées sous le vent de SO/SE dimanche, de nouvelles plaques se forment sous le vent de NE lundi en journée. Elles sont d'aspect friable, parfois dur plus en altitude, facilement déclenchables au passage d'un skieur. On les retrouve au voisinage des crêtes. Taille 1 à 2.
Observables : accumulation de neige, vaguelettes, fissures sous les skis.
* Dans les adrets d'altitude et en ubacs au-dessus de 2100 m, une couche fragile persistante est encore enfouie, mais ne semble pas vraiment déclenchable par un skieur. Toutefois, par une forte surcharge (avalanche en cascade, chutes de corniches), elle pourrait être sollicitée et engendrer une avalanche de taille 2 à 3 (moyenne à grande).

Départs spontanés :
* Départs dans la neige récente à cause du vent de NE en journée. Taille 1 à 2.
* Sous 2000 m, quelques coulées de neige humide dans les versants ensoleillés au fil du réchauffement (secteur sans vent). Taille 1.
* Peu probable, plaques de fond, en tous versants, à toute heure du jour et de la nuit, dans les pentes lisses et raides (zones herbeuses, dalles, vires). Taille 1 à 2.

Qualité de la neige

Enneigement :
L'enneigement passe d'inexistant à relativement bon une fois la limite d'enneigement atteinte.
On peut chausser les skis vers 1200/1300 m en nord et 1400/1500 m en sud.
Grosses corniches présentes.

Qualité de la neige ce lundi :
* 5/10 cm de neige récente, ventée près des crêtes. Elle s'humidifie en surface dans les versants ensoleillés et reste froide à l'ombre. Elle repose sur un fond dur : croûte en versant S/E/O et sur de la neige froide souvent cartonnée en Nord (ou de la vielle poudre dans les secteurs abrités en altitude).

Aperçu météo pour le lundi 23 mars

nuit	matin	après-midi	soir

Belles éclaircies, des nuages sur le relief en journée. Légère remontée de l'isotherme 0°C. Vent de nord-est.

Pluie-Neige				
Iso 0 °C	1 600 m	1 900 m	2 000 m	1 900 m
Vent 2000 m	15 km/h	30 km/h	30 km/h	10 km/h
Vent 2500 m	20 km/h	30 km/h	30 km/h	20 km/h

Épaisseur de neige hors-piste

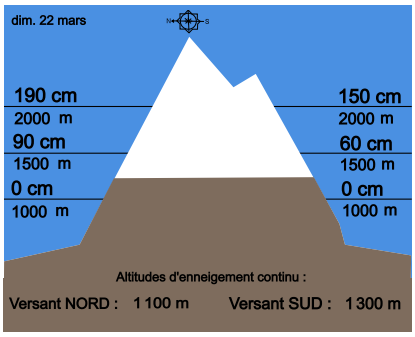

Précipitations à 1800 m

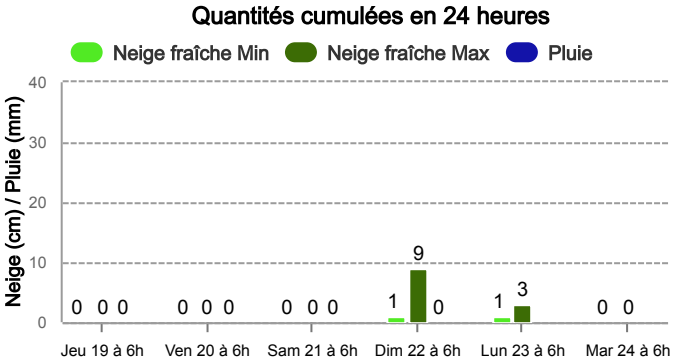

Tendance du mardi 24 mars

2

Indice de risque limité

Les plaques formées sous le vent de nord-est sont encore présentes en altitude, en cours de stabilisation.

Pour consulter la vigilance en cours, veuillez vous rendre sur le site https://vigilance.meteofrance.fr/fr

Météo-France - 73 avenue de Paris, 94165 Saint-Mandé cedex - Contact : contact@meteo.fr

Rédigé par Météo-France avec la contribution des observateurs du réseau nivo-météorologiques. Partenariat : ANMSM (Maires de Stations de Montagne), DSF (Domaines Skiables de France), ADSP (Directeurs de Pistes et de la Sécurité des Stations de Sports d'Hiver) et autres acteurs de la montagne.

Bulletin neige & avalanches par téléphone au 0 892 68 10 20 Service 0,35 € / min + prix appel

RÉPUBLIQUE FRANÇAISE
Liberté Égalité Fraternité

METEO FRANCE
À VOS CÔTÉS, DANS UN CLIMAT QUI CHANGE

Bulletin d'estimation du risque d'avalanche

(valable en dehors des pistes balisées et ouvertes)

MASSIF : Aravis

Rédigé le dimanche 22 mars 2026 à 16h

Conditions nivo-météo des 7 derniers jours

	lun. 16/03				mar. 17/03				mer. 18/03				jeu. 19/03				ven. 20/03				sam. 21/03				dim. 22/03			
	03h	09h	15h	21h	03h	09h	15h	21h	03h	09h	15h	21h	03h	09h	15h	21h	03h	09h	15h	21h	03h	09h	15h	21h	03h	09h	15h	21h
Météo																												
Vent (km/h)	15	20	20	20	25	30	30	35	45	20	60	50	25	30	25	30	30	20	10	10	10	15	15	15	30	35	40	15
à 2500m																												
Vent (km/h)	5	10	10	10	10	15	15	15	15	10	50	30	10	20	15	20	20	10	5	5	5	10	10	5	20	25	25	5
à 2000m																												

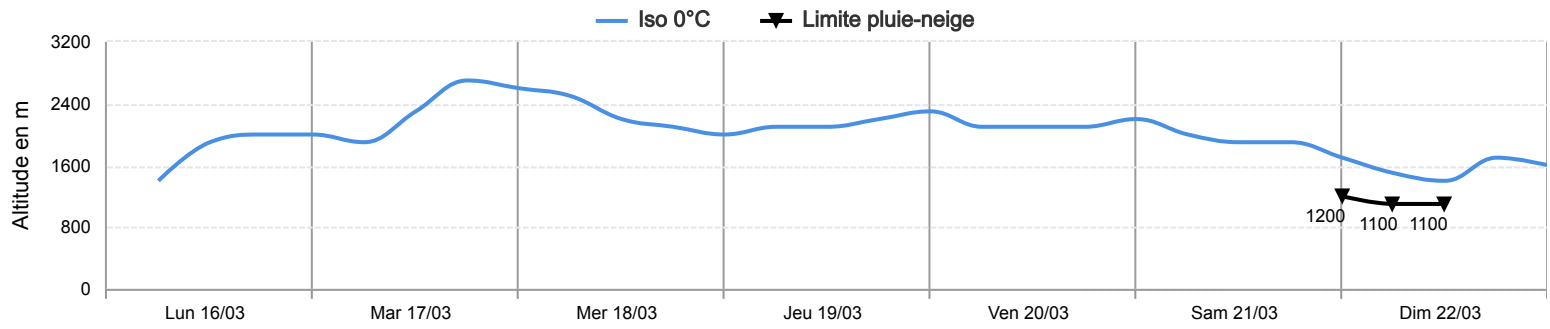

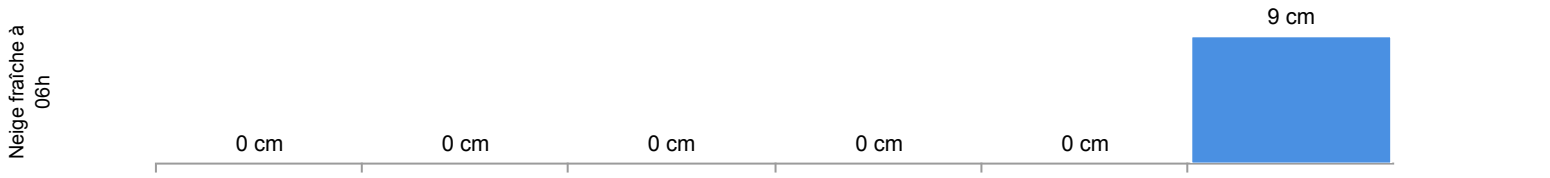

Risque d'avalanche	lun. 16/03	mar. 17/03	mer. 18/03	jeu. 19/03	ven. 20/03	sam. 21/03	dim. 22/03
	3	2	3	3	2	2	2

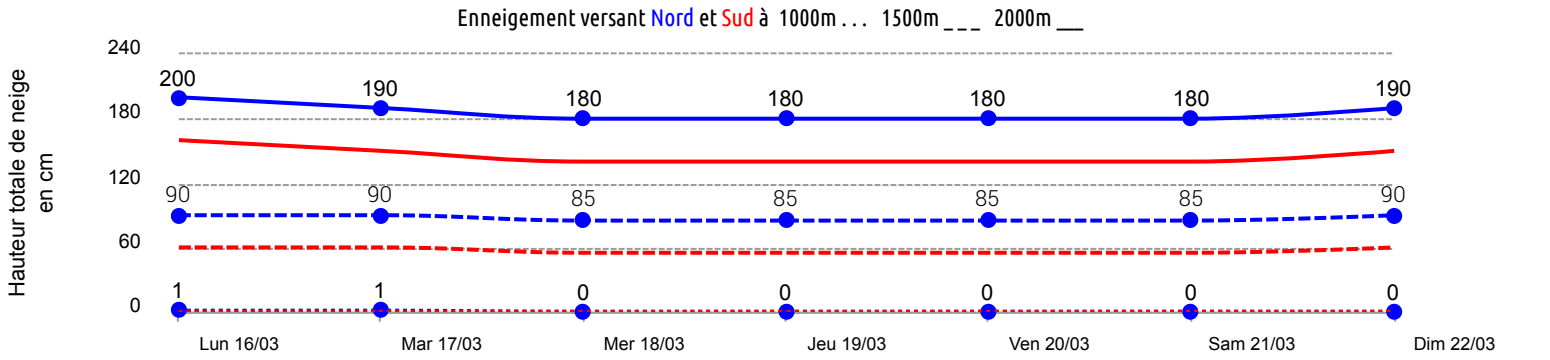

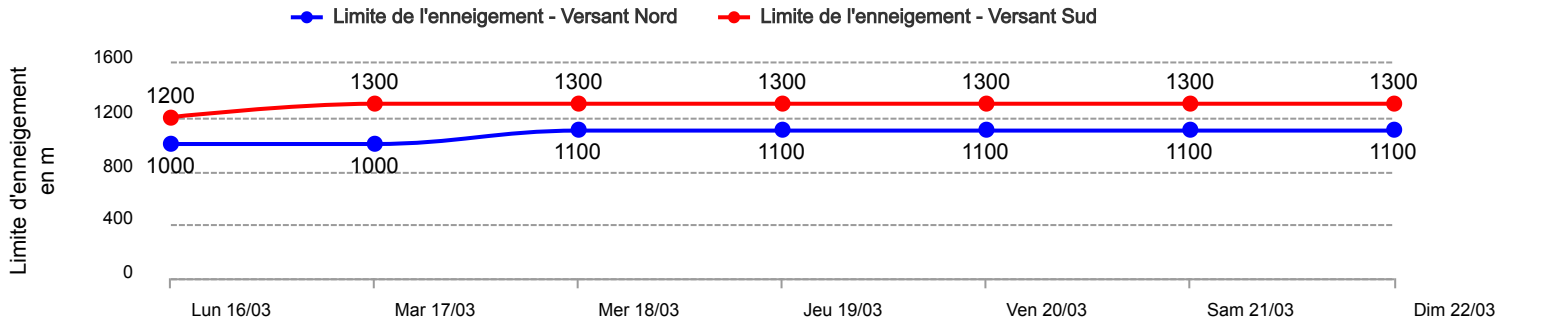

Pour consulter la vigilance en cours, veuillez vous rendre sur le site https://vigilance.meteofrance.fr/fr

Météo-France - 73 avenue de Paris, 94165 Saint-Mandé cedex - Contact : contact@meteo.fr

Rédigé par Météo-France avec la contribution des observateurs du réseau nivo-météorologiques. Partenariat : ANMSM (Maires de Stations de Montagne), DSF (Domaines Skiables de France), ADSP (Directeurs de Pistes et de la Sécurité des Stations de Sports d'Hiver) et autres acteurs de la montagne.

Bulletin neige & avalanches par téléphone au
0 892 68 10 20 Service 0,35 € / min + prix appel