Bulletin d'estimation du risque d'avalanche

(valable en dehors des pistes balisées et ouvertes)

MASSIF : Beaufortain

Rédigé le dimanche 22 mars 2026 à 16h

Estimation des risques pour le : LUNDI 23 MARS

INSTABILITÉS TEMPORAIRES FORMÉES PAR LE VENT DANS LA NEIGE LÉGÈRE.

2

2

N O E S

Indice de risque limité.

Départs spontanés : purges au soleil.

Déclenchements provoqués : quelques plaques, parfois réactives.

Indices de risque : 5 très fort - 4 fort - 3 marqué - 2 limité - 1 faible -- En noir : les pentes les plus dangereuses

Stabilité du manteau neigeux

Situation avalancheuse typique : neige ventée neige fraîche

Déclenchements provoqués : Quelques plaques sont en place suite à l'épisode transport de neige par le vent d'Est à Sud de ce dimanche. Elles sont globalement en perte de réactivité mais encore déclenchable : en Nord là où il restait un peu de poudre, derrière les ruptures de pente et près des crêtes, en altitude (où elles sont aussi plus nombreuses), là où le vent de Nord-Est se fait sentir (en altitude sur le Nord-Ouest du massif). Taille 1 à 2 avec des cassures de 15 à 30 cm.
Observables : accumulation de neige derrière une rupture de pente, test de stabilité, fissures devant les skis.

Départs spontanés : Quelques petits départs en poire sont possibles dans les pentes raides qui chauffent au soleil. Taille 1, rarement 2 si la pente le permet.
Très rarement, sur le Nord et l'Ouest du massif, un départ linéaire est possible spontanément par surcharge de neige transportée par le vent de Nord Est en cours. Taille 1 à 2.

Qualité de la neige

Enneigement : Encore un peu au dessus de la moyenne, sauf aux plus basses altitudes où les hauteurs de neige sont tout juste correctes pour la saison.

Limite skiable : 1100 m au mieux en Nord. Plutôt 1400/1500 m en sud pas trop raide.

Qualité de la neige : 10/15 cm de neige fraîche vers 1800 m localement 20/25 cm en altitude. Le vent a redistribué la neige : on peut trouver des zones pelées et d'autres avec le double d'épaisseur. Cette neige est croutée sous 1500/1700 m. Elle s'alourdit par humidification en journée. Sous-couche souvent dure : croute de regel en Sud, Est et Ouest (sauf très haut) et souvent cartonnée par le vent en Nord.

Aperçu météo pour le lundi 23 mars

nuit	matin	après-midi	soir

Très belle journée. Cumulus parfois volumineux sur les sommets en fin d'après-midi.

Pluie-Neige				
Iso 0 °C	1 600 m	1 800 m	2 200 m	1 900 m
Vent 2000 m	10 km/h	10 km/h	15 km/h	10 km/h
Vent 3000 m	20 km/h	25 km/h	20 km/h	20 km/h

Épaisseur de neige hors-piste

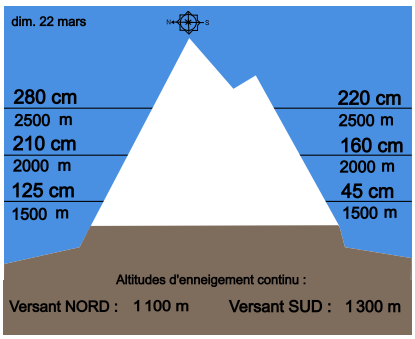

Précipitations à 1800 m

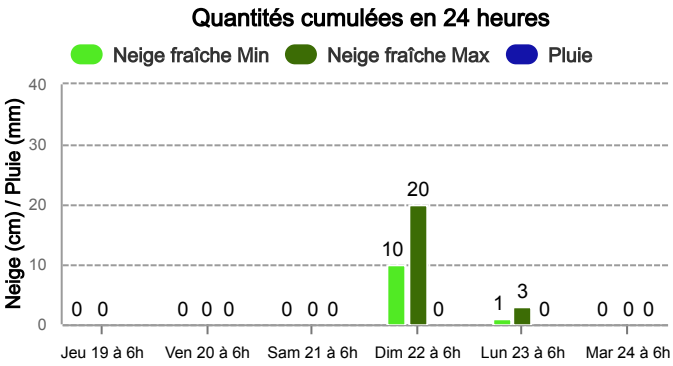

Tendance du mardi 24 mars

2

Indice de risque limité

Risque en baisse. Météo calme permettant la neutralisation des instabilités.

Pour consulter la vigilance en cours, veuillez vous rendre sur le site https://vigilance.meteofrance.fr/fr

Météo-France - 73 avenue de Paris, 94165 Saint-Mandé cedex - Contact : contact@meteo.fr

Rédigé par Météo-France avec la contribution des observateurs du réseau nivo-météorologiques. Partenariat : ANMSM (Maires de Stations de Montagne), DSF (Domaines Skiables de France), ADSP (Directeurs de Pistes et de la Sécurité des Stations de Sports d'Hiver) et autres acteurs de la montagne.

Bulletin neige & avalanches par téléphone au 0 892 68 10 20 Service 0,35 € / min + prix appel

Bulletin d'estimation du risque d'avalanche

(valable en dehors des pistes balisées et ouvertes)

MASSIF : Beaufortain

Rédigé le dimanche 22 mars 2026 à 16h

Conditions nivo-météo des 7 derniers jours

	lun. 16/03				mar. 17/03				mer. 18/03				jeu. 19/03				ven. 20/03				sam. 21/03				dim. 22/03			
	03h	09h	15h	21h	03h	09h	15h	21h	03h	09h	15h	21h	03h	09h	15h	21h	03h	09h	15h	21h	03h	09h	15h	21h	03h	09h	15h	21h
Météo																												
Vent (km/h)	20	30	30	20	20	20	20	20	20	35	60	50	35	20	20	20	25	25	15	10	15	25	20	15	15	25	20	10
à 3000m																												
Vent (km/h)	10	15	20	10	10	10	10	10	10	20	40	35	20	10	10	10	5	5	0	0	5	10	20	10	10	30	25	15
à 2000m																												

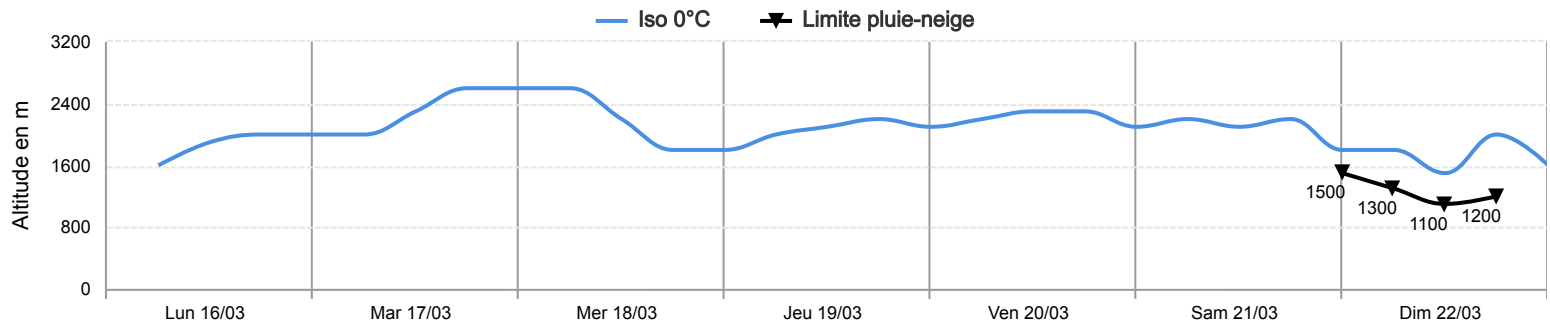

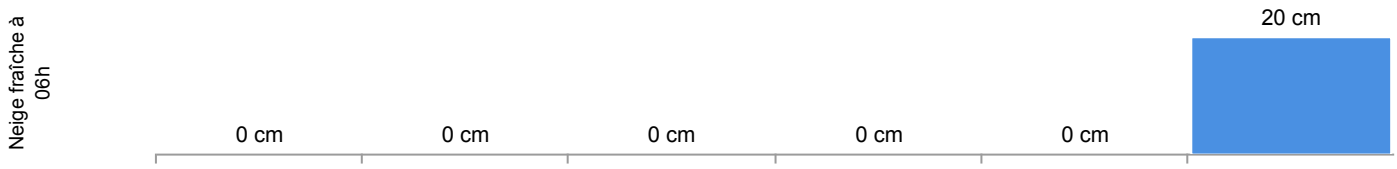

Risque d'avalanche	lun. 16/03	mar. 17/03	mer. 18/03	jeu. 19/03	ven. 20/03	sam. 21/03	dim. 22/03
	3	2	3	3	2	2	2

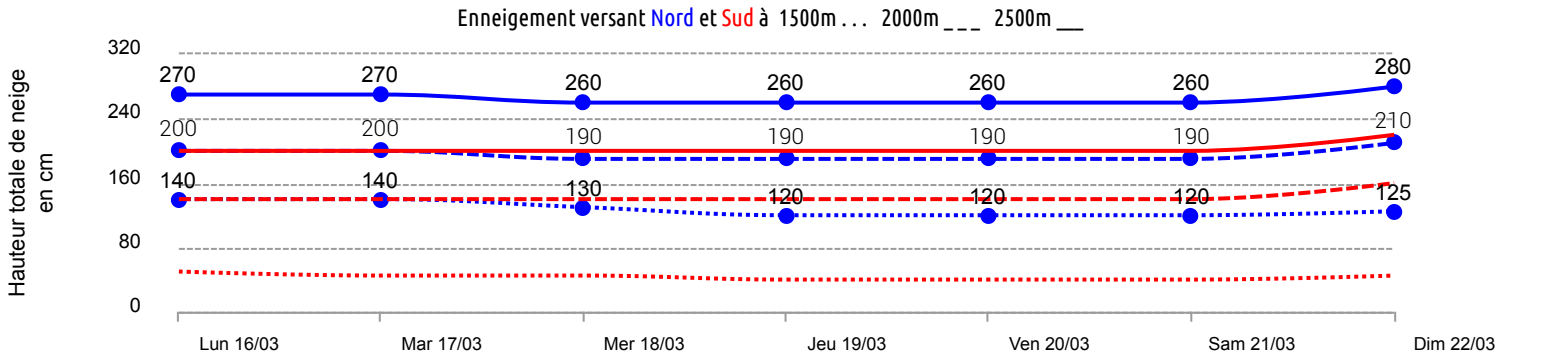

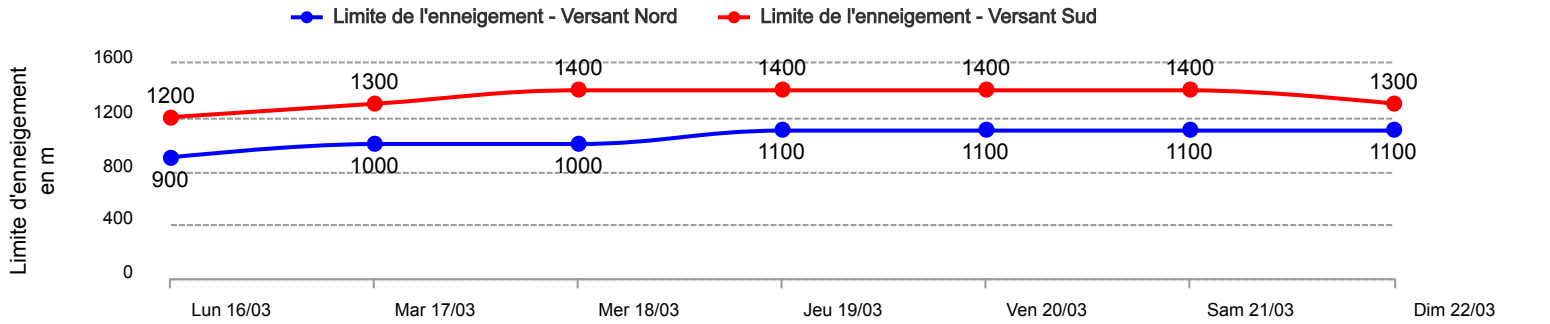

Pour consulter la vigilance en cours, veuillez vous rendre sur le site https://vigilance.meteofrance.fr/fr

Météo-France - 73 avenue de Paris, 94165 Saint-Mandé cedex - Contact : contact@meteo.fr

Rédigé par Météo-France avec la contribution des observateurs du réseau nivo-météorologiques. Partenariat : ANMSM (Maires de Stations de Montagne), DSF (Domaines Skiables de France), ADSP (Directeurs de Pistes et de la Sécurité des Stations de Sports d'Hiver) et autres acteurs de la montagne.

Bulletin neige & avalanches par téléphone au

0 892 68 10 20 Service 0,35 € / min + prix appel