Bulletin d'estimation du risque d'avalanche
(valable en dehors des pistes balisées et ouvertes)

MASSIF : Belledonne

Rédigé le dimanche 22 mars 2026 à 16h

Estimation des risques pour le : LUNDI 23 MARS

NEIGE FRAICHE EN ALTITUDE

2

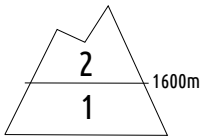

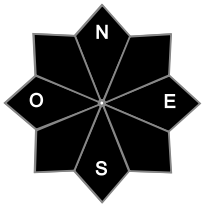

neige fraiche

Au-dessus de 1600m indice de risque limité, plus bas indice faible.

Départs spontanés : Avalanches de neige fraiche, surtout au-dessus de 1600/1800m. Purges au soleil l'après-midi.

Déclenchements provoqués : Plaques en altitude dans la neige récente.

Indices de risque : 5 très fort - 4 fort - 3 marqué - 2 limité - 1 faible -- En noir : les pentes les plus dangereuses

Stabilité du manteau neigeux

Situation avalancheuse typique : neige fraîche — neige ventée

Déclenchements provoqués : Le manteau neigeux s'est bien stabilisé depuis les dernières chutes de neige et les nouvelles chutes de dimanche ont amené des instabilités temporaires. Le risque de déclenchement est lié à des plaques la plupart du temps peu épaisses disséminées dans la neige fraiche. Au-dessus de 1800/2000m, à proximité des zones d'accumulation des crêtes et cols, elles peuvent etre de taille moyenne. Le vent de Nord-est parfois sensible peut avoir favoriser la formation de petites plaques à vent qui généralise un peu plus ce risque sur les secteurs exposés. Avec le retour du soleil, on peut aussi attendre des départs en neige humide en surface sous les skis, ils restent de petites tailles mais parfois généralisés l'après-midi en versant ensoleillé.

Départs spontanés : Avec les nouvelles chutes de neige qui ont eu lieu dimanche, une avalanche de neige fraiche de petite taille est encore possible en matinée, l'après-midi et plutôt en versants ensoleillés on peut s'attendre à des départs en neige humide de petite taille.

Qualité de la neige

Qualification de l'enneigement : L'enneigement est bon pour la saison en versants ombragés au dessus de 1300 m. Il est correct en Sud au dessus de 1500 m.
Limites skiables : Vers 1300/1700 m selon les versants.

Qualité de la neige lundi : Dès 1200/1300m, on peut attendre une belle couche de neige fraiche de 5/10cm et 15/20cm au-dessus de 1500m. En sous-couche, la neige est parfois très dure et dense, parfois travaillée par le vent dans les ubacs. Cependant, cette neige s'alourdit et se tasse rapidement en matinée pour devenir lourde dans la plupart des versants l'après-midi. Au-dessus de 1800/2000m en versants ombragés, la neige reste froide et légère.

Aperçu météo pour le lundi 23 mars

Belle journée ensoleillée mais fraiche avec des averses possibles l'après-midi.

	nuit	matin	après-midi	soir
Pluie-Neige	1 100 m			
Iso 0 °C	1 500 m	1 700 m	1 900 m	1 900 m
Vent 2000 m	15 km/h	20 km/h	15 km/h	15 km/h
Vent 3000 m	20 km/h	30 km/h	25 km/h	25 km/h

Épaisseur de neige hors-piste

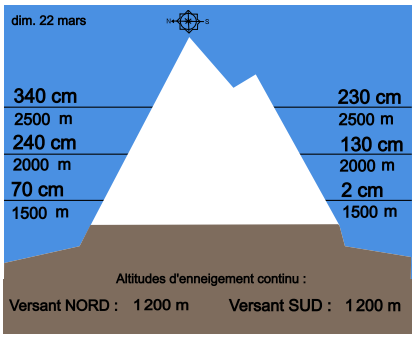

Précipitations à 1800 m

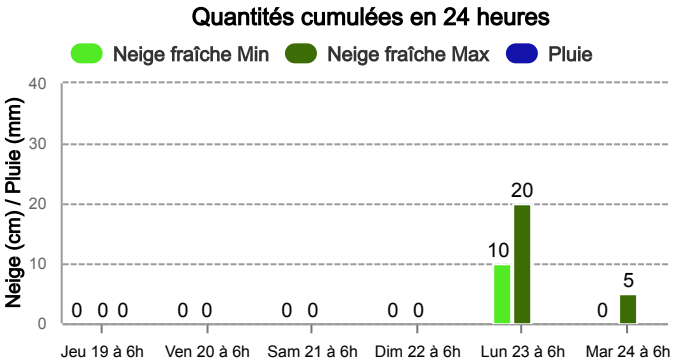

Tendance du mardi 24 mars

2

Indice de risque limité

Risque en légère baisse avec le retour d'un temps sec.

Pour consulter la vigilance en cours, veuillez vous rendre sur le site https://vigilance.meteofrance.fr/fr

Météo-France - 73 avenue de Paris, 94165 Saint-Mandé cedex - Contact : contact@meteo.fr

Rédigé par Météo-France avec la contribution des observateurs du réseau nivo-météorologiques. Partenariat : ANMSM (Maires de Stations de Montagne), DSF (Domaines Skiables de France), ADSP (Directeurs de Pistes et de la Sécurité des Stations de Sports d'Hiver) et autres acteurs de la montagne.

Bulletin neige & avalanches par téléphone au
0 892 68 10 20 Service 0,35 € / min + prix appel

RÉPUBLIQUE FRANÇAISE
Liberté Égalité Fraternité

METEO FRANCE
À VOS CÔTÉS, DANS UN CLIMAT QUI CHANGE

Bulletin d'estimation du risque d'avalanche

(valable en dehors des pistes balisées et ouvertes)

MASSIF : Belledonne

Rédigé le dimanche 22 mars 2026 à 16h

Conditions nivo-météo des 7 derniers jours

	lun. 16/03				mar. 17/03				mer. 18/03				jeu. 19/03				ven. 20/03				sam. 21/03				dim. 22/03			
	03h	09h	15h	21h	03h	09h	15h	21h	03h	09h	15h	21h	03h	09h	15h	21h	03h	09h	15h	21h	03h	09h	15h	21h	03h	09h	15h	21h
Météo																												
Vent (km/h)	45	45	45	35	35	25	25	40	45	40	40	45	40	20	25	20	25	25	15	10	15	25	25	15	15	15	15	15
à 3000m	↓	↓	↓	↓	↓	↓	↓	↓	↓	↓	↖	↖	↖	←	↙	↙	↙	↙	↓	↘	↓	↓	↓	↘	→	↗	↑	↙
Vent (km/h)	30	35	30	20	15	10	15	15	15	15	30	35	40	20	15	5	10	10	5	5	10	15	10	5	15	10	20	15
à 2000m	↓	↓	↓	↓	↙	←	↘	↙	↙	↘	↑	↖	↖	←	↘	↙	↓	↙	↓	↓	↓	↓	↘	↓	↘	↗	↖	←

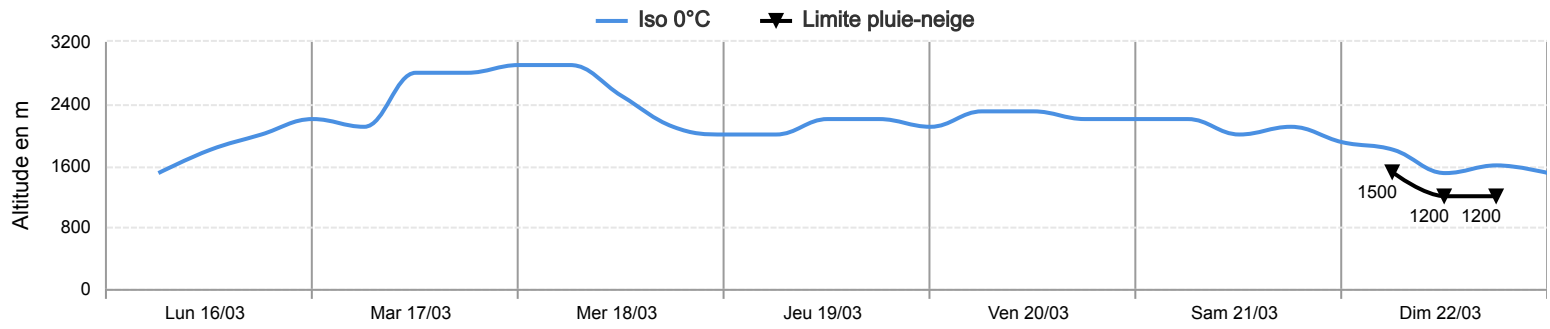

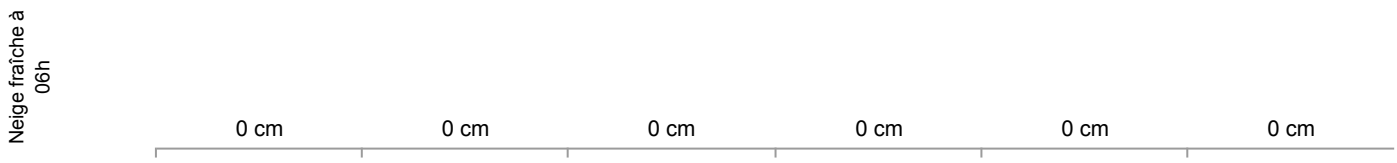

Risque d'avalanche	lun. 16/03	mar. 17/03	mer. 18/03	jeu. 19/03	ven. 20/03	sam. 21/03	dim. 22/03
	3	3	3	2	2	2	2

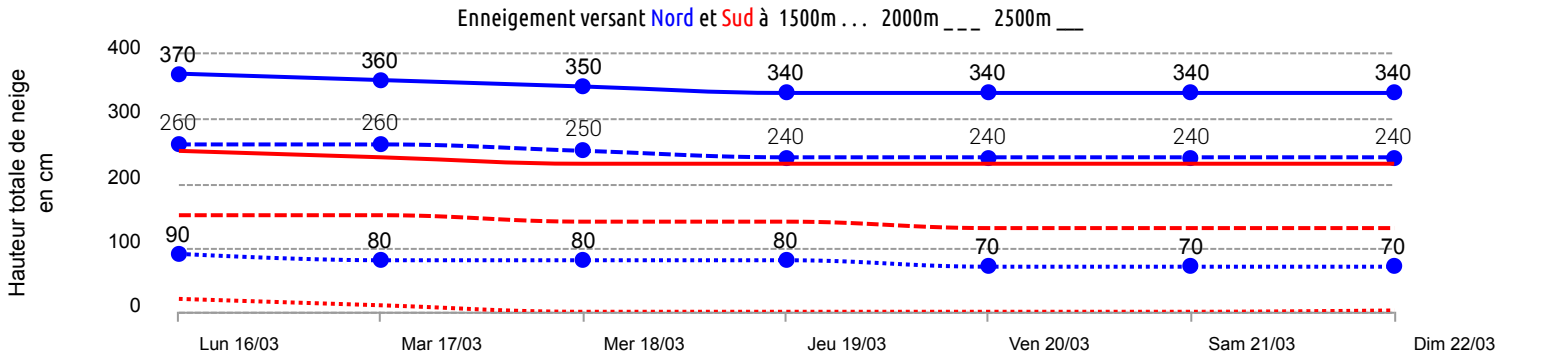

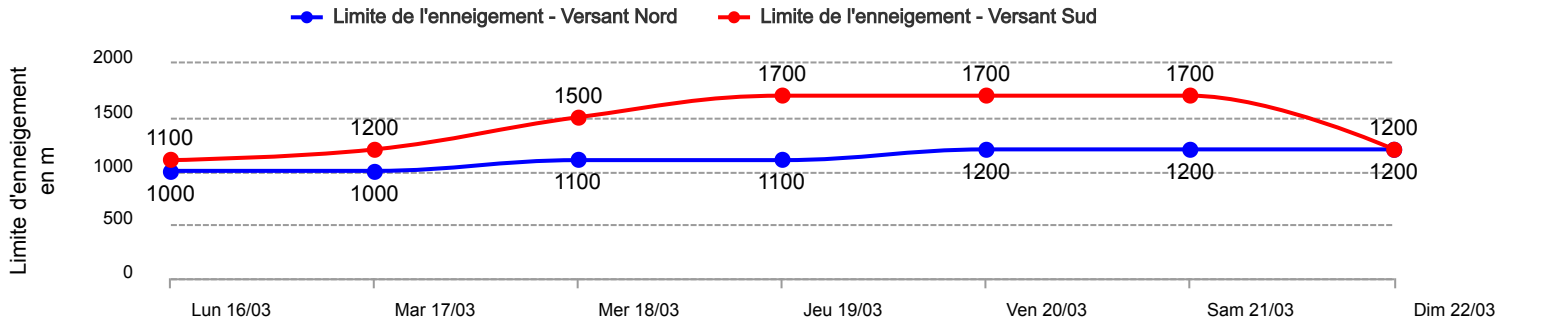

Pour consulter la vigilance en cours, veuillez vous rendre sur le site https://vigilance.meteofrance.fr/fr

Météo-France - 73 avenue de Paris, 94165 Saint-Mandé cedex - Contact : contact@meteo.fr

Rédigé par Météo-France avec la contribution des observateurs du réseau nivo-météorologiques. Partenariat : ANMSM (Maires de Stations de Montagne), DSF (Domaines Skiables de France), ADSP (Directeurs de Pistes et de la Sécurité des Stations de Sports d'Hiver) et autres acteurs de la montagne.

Bulletin neige & avalanches par téléphone au
0 892 68 10 20 Service 0,35 € / min + prix appel