RÉPUBLIQUE FRANÇAISE
Liberté Égalité Fraternité

METEO FRANCE
À VOS CÔTÉS, DANS UN CLIMAT QUI CHANGE

Bulletin d'estimation du risque d'avalanche
(valable en dehors des pistes balisées et ouvertes)

MASSIF : Cerdagne Canigou

Rédigé le dimanche 22 mars 2026 à 16h

Estimation des risques pour le : LUNDI 23 MARS

COULÉES AU SOLEIL, QUELQUES STRUCTURES DE PLAQUES EN ALTITUDE.

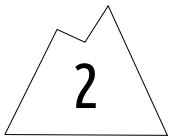

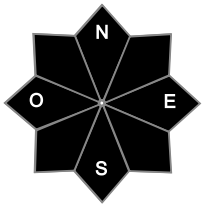

toutes orientations

Indice de risque limité.

Départs spontanés : Nombreuses coulées de surface au soleil.

Déclenchements provoqués : Rares plaques possibles dans les versants froids

Indices de risque : 5 très fort - 4 fort - 3 marqué - 2 limité - 1 faible -- En noir : les pentes les plus dangereuses

Stabilité du manteau neigeux

Situation avalancheuse typique : neige humide neige ventée

Déclenchements provoqués :

- Les chutes de neige attendues ce dimanche soir forment une nouvelle couche irrégulière de 5 à 10 cm d'épaisseur en général mais localement plus. Cette neige parfois ventée peut reposer soit sur un peu de givre de surface dans les pentes Nord soit sur de la neige fraîche sans cohésion et peut ainsi constituer des structures très fragiles, pouvant céder au passage d'un simple randonneur. Il s'agit essentiellement de petites avalanches (taille 1) risquant surtout de déstabiliser un randonneur mais, suivant les accumulation localisées, des cassures de 15 à 20 cm sont possibles pouvant dans certaines configurations (couloirs étroits) devenir plus dangereuses.
Observables : neige récente travaillée par le vent, enfoncement des bâtons supérieur à 20 cm, fissures devant les skis.

Départs spontanés :

- Nombreuses coulées de neige fraiche. Avec le retour matinal du soleil, de nombreuses petites avalanches vont se produire dans les pentes raides (purges) emportant souvent l'ensemble de la neige tombée la veille. D'abord en orientation Est puis Sud et enfin Ouest. Seules les pentes Nord en altitude (>2300m) devraient être moins concernées. La taille de ces avalanches devraient rester modestes (taille 1, rarement 2)

Autre :

Neige dure et parfois glacée aux premières heures du jour dans les zones soufflées.

Qualité de la neige

Enneigement :
L'enneigement reste excellent pour la saison, après plusieurs hivers déficitaires. De nouvelles chutes de neige blanchissent la montagne dès 1400m d'altitude mais il faut atteindre en général 1600 à 1700m pour trouver une sous-couche voire 1900m en versant Sud.

Qualité de la neige :
Lundi matin on trouve donc une petite couche de neige fraîche (5/10 cm) au gré des averses de la nuit passée.
Elle repose sur une couche de neige souvent dure et regelée. Cette neige fraîche reste poudreuse dans les pentes nord mais elle s'humidifie au soleil devenant rapidement collante sous les skis.

Aperçu météo pour le lundi 23 mars

	nuit	matin	après-midi	soir
	Belles éclaircies			
Pluie-Neige	1 500 m			
Iso 0 °C	1 800 m	2 000 m	2 200 m	2 300 m
Vent 2000 m	↓ 30 km/h	↓ 35 km/h	↘ 30 km/h	↘ 20 km/h
Vent 3000 m	↓ 50 km/h	↓ 50 km/h	↓ 35 km/h	↓ 30 km/h

Épaisseur de neige hors-piste

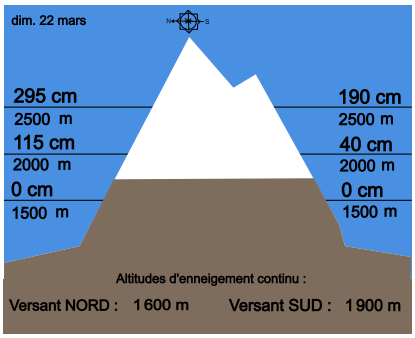

Précipitations à 1800 m

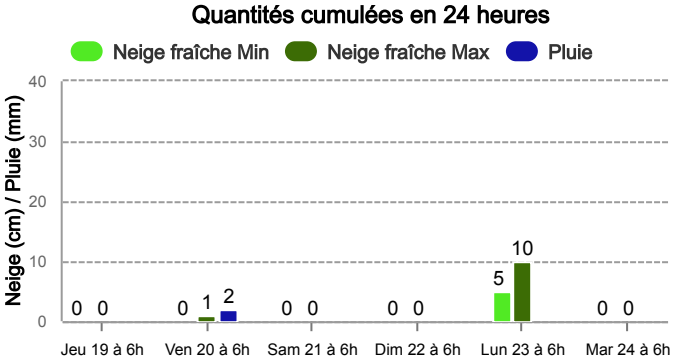

Tendance du mardi 24 mars

Indice de risque limité

Stabilisation progressive.

Pour consulter la vigilance en cours, veuillez vous rendre sur le site https://vigilance.meteofrance.fr/fr

Météo-France - 73 avenue de Paris, 94165 Saint-Mandé cedex - Contact : contact@meteo.fr

Rédigé par Météo-France avec la contribution des observateurs du réseau nivo-météorologiques. Partenariat : ANMSM (Maires de Stations de Montagne), DSF (Domaines Skiables de France), ADSP (Directeurs de Pistes et de la Sécurité des Stations de Sports d'Hiver) et autres acteurs de la montagne.

Bulletin neige & avalanches par téléphone au
0 892 68 10 20 Service 0,35 € / min + prix appel

RÉPUBLIQUE FRANÇAISE
Liberté Égalité Fraternité

METEO FRANCE
À VOS CÔTÉS, DANS UN CLIMAT QUI CHANGE

Bulletin d'estimation du risque d'avalanche

(valable en dehors des pistes balisées et ouvertes)

MASSIF : Cerdagne Canigou

Rédigé le dimanche 22 mars 2026 à 16h

Conditions nivo-météo des 7 derniers jours

	lun. 16/03				mar. 17/03				mer. 18/03				jeu. 19/03				ven. 20/03				sam. 21/03				dim. 22/03			
	03h	09h	15h	21h	03h	09h	15h	21h	03h	09h	15h	21h	03h	09h	15h	21h	03h	09h	15h	21h	03h	09h	15h	21h	03h	09h	15h	21h
Météo																												
Vent (km/h)	70	60	55	40	45	25	15	15	15	15	20	30	35	35	30	25	20	20	20	25	15	15	20	20	25	20	30	50
à 3000m																												
Vent (km/h)	50	45	35	25	25	15	10	10	10	10	15	20	25	25	20	10	10	10	10	10	10	10	15	10	15	15	25	30
à 2000m																												

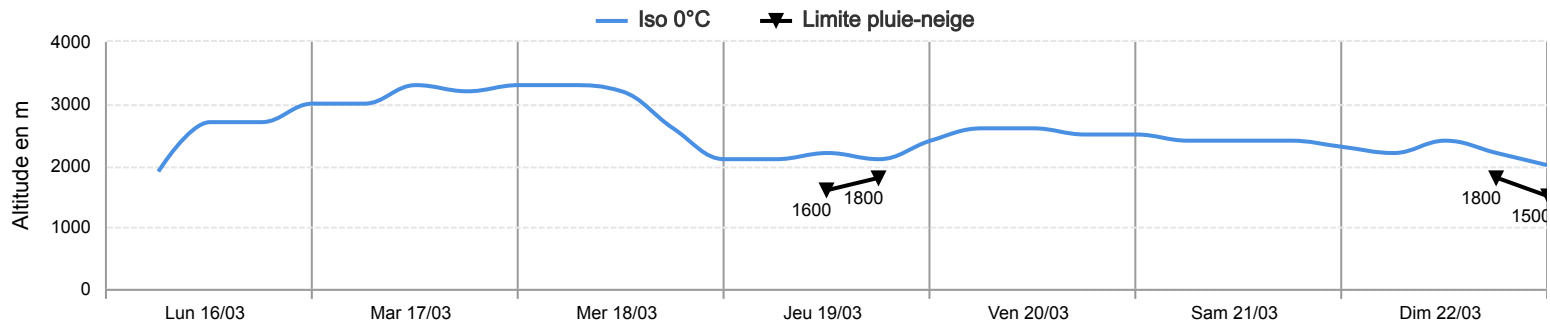

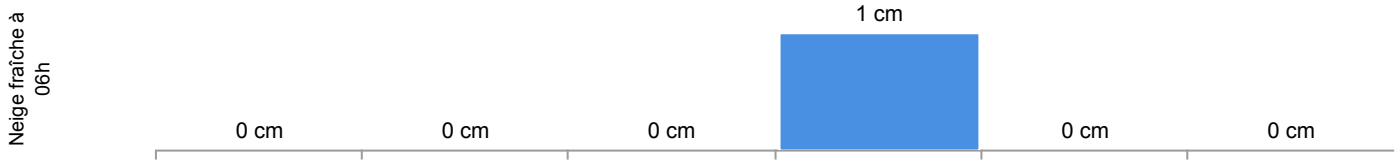

Risque d'avalanche	lun. 16/03	mar. 17/03	mer. 18/03	jeu. 19/03	ven. 20/03	sam. 21/03	dim. 22/03
	3	3	3	2	2	2	2

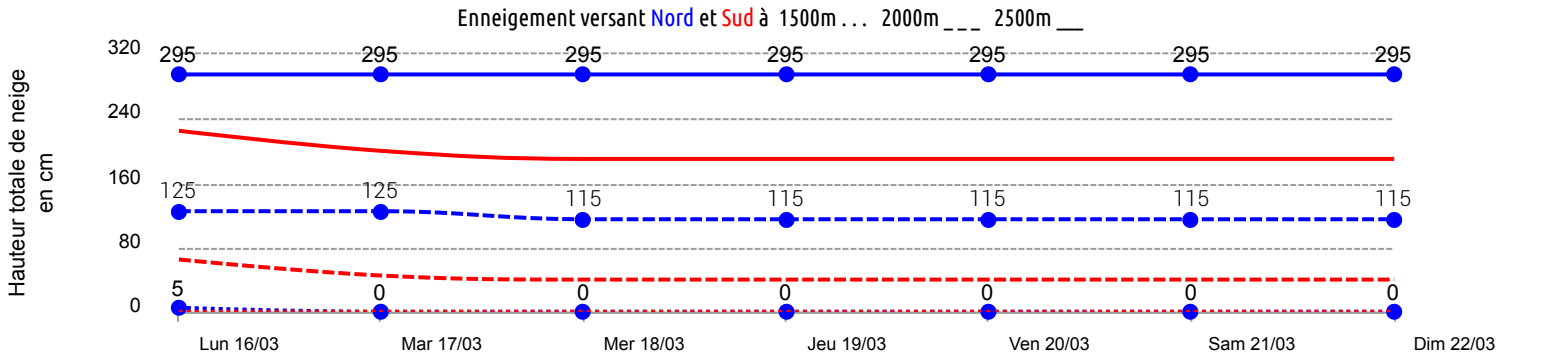

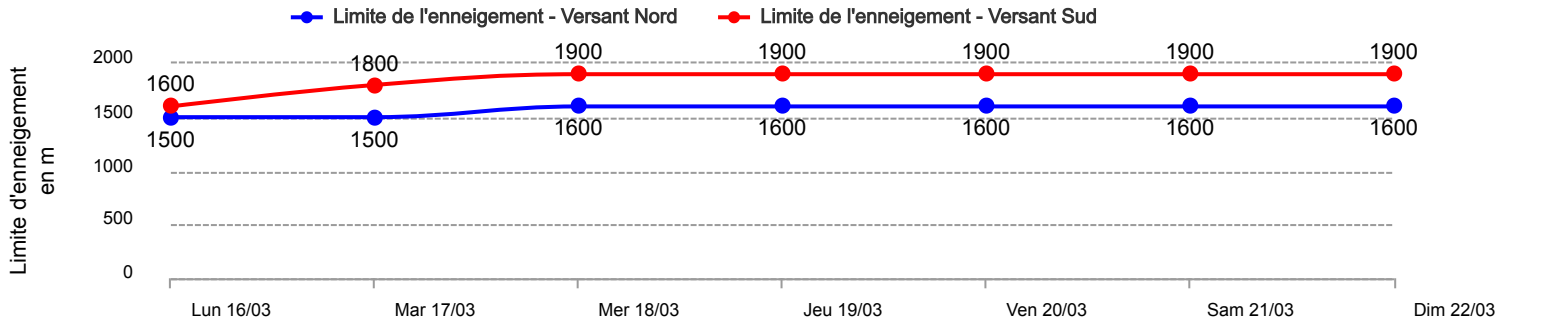

Pour consulter la vigilance en cours, veuillez vous rendre sur le site https://vigilance.meteofrance.fr/fr

Météo-France - 73 avenue de Paris, 94165 Saint-Mandé cedex - Contact : contact@meteo.fr

Rédigé par Météo-France avec la contribution des observateurs du réseau nivo-météorologiques. Partenariat : ANMSM (Maires de Stations de Montagne), DSF (Domaines Skiables de France), ADSP (Directeurs de Pistes et de la Sécurité des Stations de Sports d'Hiver) et autres acteurs de la montagne.

Bulletin neige & avalanches par téléphone au

0 892 68 10 20 Service 0,35 € / min + prix appel