# Bulletin d'estimation du risque d'avalanche

(valable en dehors des pistes balisées et ouvertes)

# MASSIF : Couserans

Rédigé le dimanche 22 mars 2026 à 16h

## Estimation des risques pour le : LUNDI 23 MARS

**RISQUE MARQUÉ SUIVANT L'ACTIVITÉ NEIGEUSE DE DIMANCHE SOIR.**

3

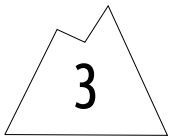


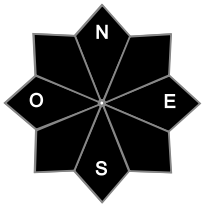


Toutes orientations

Indices de risque : 5 très fort - 4 fort - 3 marqué - 2 limité - 1 faible -- En noir : les pentes les plus dangereuses

Indice de risque marqué.

**Départs spontanés :** Nombreuses petites avalanches au soleil.

**Déclenchements provoqués :** Nouvelles plaques friables en toutes orientations facilement déclenchables

## Stabilité du manteau neigeux

**Situation avalancheuse typique :** neige fraîche neige humide

**Déclenchements provoqués :**

- Les chutes de neige attendues ce dimanche soir forment une nouvelle couche irrégulière de 10 à 15 cm d'épaisseur en général mais localement plus (20 à 25 sur le Haut Couserans) . Cette neige parfois ventée peut reposer soit sur un peu de givre de surface dans les pentes Nord soit sur de la neige fraîche sans cohésion et peut ainsi constituer des structures très fragiles, pouvant céder au passage d'un simple randonneur. Il s'agit essentiellement de petites avalanches (taille 1) mais, suivant les accumulation localisées, des cassures de 20 à 40 cm sont possibles et une avalanche moyenne est alors envisageable (taille 2).

*Observables : neige récente travaillée par le vent, enfoncement des bâtons supérieur à 20/30 cm, fissures devant les skis.*

**Départs spontanés :**

- Nombreuses avalanches de neige fraiche. Avec le retour matinal du soleil, de nombreuses petites avalanches vont se produire dans les pentes raides (purges) emportant souvent l'ensemble de la neige tombée la veille. D'abord en orientation Est puis Sud et enfin Ouest. Seules les pentes Nord en altitude (>2300m) devraient être moins concernées. La taille de ces avalanches devraient rester modestes (1 à 2).

**Autre :**

## Qualité de la neige

**Enneigement** :

Enneigement reste très correct pour la saison, après plusieurs hivers déficitaires.
Une nouvelle couche de neige fraîche est présente lundi matin dès 1200/1300m mais il faut atteindre 1500m en Nord et 1800m en Sud pour trouver une sous-couche qui prend rapidement de l'épaisseur.
En altitude, les cumuls sont souvent conséquents mais les crêtes et sommets exposés au vent d'Ouest à Nord-ouest sont parfois complètement déneigés.

**Qualité de la neige** :

Lundi matin, on trouve en surface une jolie couche de neige fraîche, un peu humide entre 1200 et 1500m puis rapidement poudreuse de 10 à 20 cm d'épaisseur vers 2000m. Cette neige a pu être un peu travaillée par le vent et on pourra aussi trouver quelques accumulations de neige roulée (averses). Cette neige reste froide en altitude et à l'ombre mais elle s'humidifie au soleil en surface la rendant collante en dessous de 2200m.

## Aperçu météo pour le lundi 23 mars

| | nuit | matin | après-midi | soir |
|---|---|---|---|---|
| | | | | |
| | Belle éclaircies | | | |
| **Pluie-Neige** | 1 200 m | | | |
| **Iso 0 °C** | 1 800 m | 1 800 m | 2 000 m | 1 900 m |
| **Vent 2000 m** | → 30 km/h | ↙ 15 km/h | ↘ 20 km/h | ↓ 10 km/h |
| **Vent 3000 m** | ↓ 40 km/h | ↓ 35 km/h | ↓ 30 km/h | ↓ 20 km/h |

## Épaisseur de neige hors-piste

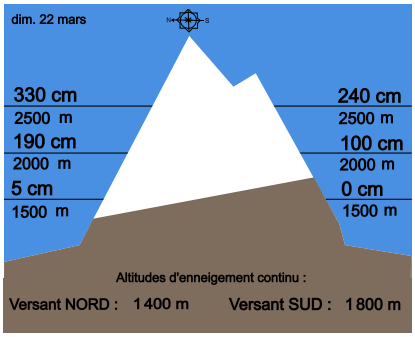


## Précipitations à 1800 m

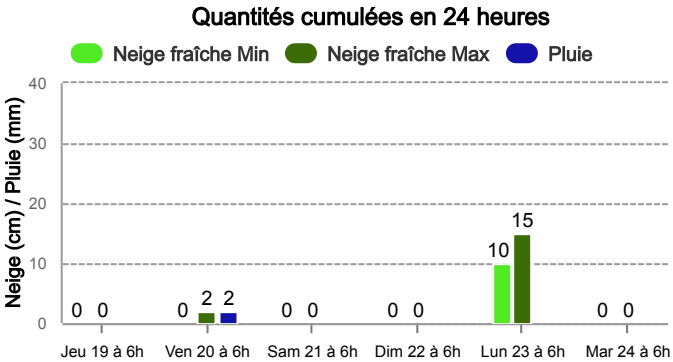


## Tendance du mardi 24 mars

2

**Indice de risque limité**

Stabilisation assez rapide de la neige récente.

Pour consulter la vigilance en cours, veuillez vous rendre sur le site https://vigilance.meteofrance.fr/fr

Météo-France - 73 avenue de Paris, 94165 Saint-Mandé cedex - Contact : contact@meteo.fr

Bulletin neige & avalanches par téléphone au **0 892 68 10 20** Service 0,35 € / min + prix appel

Rédigé par Météo-France avec la contribution des observateurs du réseau nivo-météorologiques. Partenariat : ANMSM (Maires de Stations de Montagne), DSF (Domaines Skiables de France), ADSP (Directeurs de Pistes et de la Sécurité des Stations de Sports d'Hiver) et autres acteurs de la montagne.

RÉPUBLIQUE FRANÇAISE
*Liberté Égalité Fraternité*

METEO FRANCE
À VOS CÔTÉS, DANS UN CLIMAT QUI CHANGE

# Bulletin d'estimation du risque d'avalanche
## (valable en dehors des pistes balisées et ouvertes)

# MASSIF : Couserans

Rédigé le dimanche 22 mars 2026 à 16h

## Conditions nivo-météo des 7 derniers jours

| | lun. 16/03 | | | | mar. 17/03 | | | | mer. 18/03 | | | | jeu. 19/03 | | | | ven. 20/03 | | | | sam. 21/03 | | | | dim. 22/03 | | | |
|---|---|---|---|---|---|---|---|---|---|---|---|---|---|---|---|---|---|---|---|---|---|---|---|---|---|---|---|---|
| | 03h | 09h | 15h | 21h | 03h | 09h | 15h | 21h | 03h | 09h | 15h | 21h | 03h | 09h | 15h | 21h | 03h | 09h | 15h | 21h | 03h | 09h | 15h | 21h | 03h | 09h | 15h | 21h |
| Météo | | | | | | | | | | | | | | | | | | | | | | | | | | | | |
| Vent (km/h) | 40 | 30 | 30 | 20 | 25 | 15 | 15 | 15 | 15 | 15 | 20 | 25 | 40 | 35 | 30 | 20 | 15 | 20 | 20 | 15 | 20 | 15 | 20 | 15 | 20 | 25 | 35 | 50 |
| à 3000m | | | | | | | | | | | | | | | | | | | | | | | | | | | | |
| Vent (km/h) | 25 | 20 | 20 | 10 | 15 | 10 | 10 | 10 | 10 | 5 | 10 | 20 | 30 | 25 | 20 | 10 | 10 | 10 | 10 | 15 | 10 | 10 | 15 | 10 | 10 | 15 | 30 | 35 |
| à 2000m | | | | | | | | | | | | | | | | | | | | | | | | | | | | |

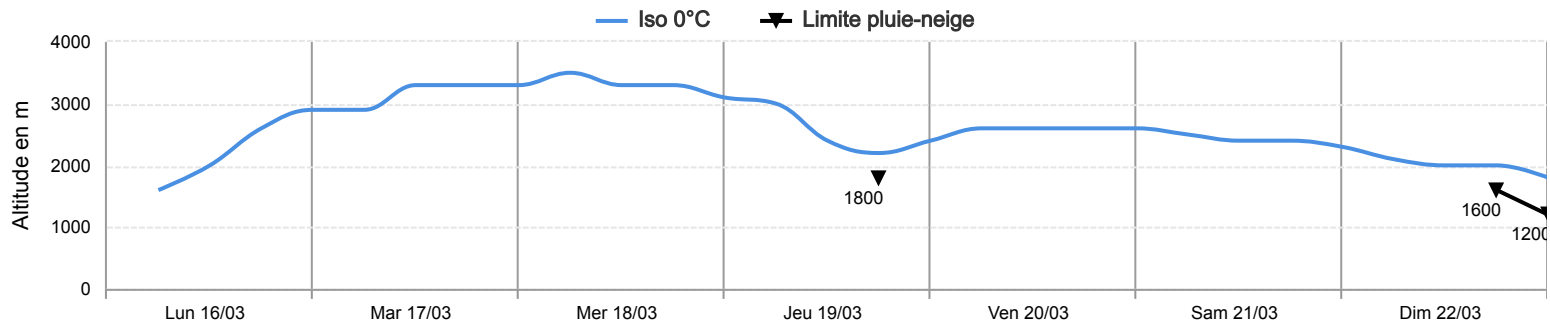


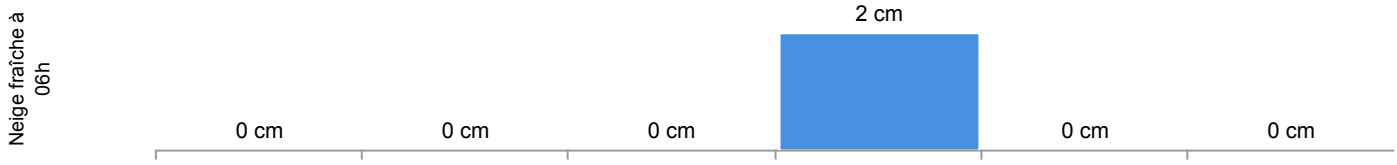


| Risque d'avalanche | lun. 16/03 | mar. 17/03 | mer. 18/03 | jeu. 19/03 | ven. 20/03 | sam. 21/03 | dim. 22/03 |
|---|---|---|---|---|---|---|---|
| | 3 | 3 | 3 | 2 | 2 | 2 | 2 |

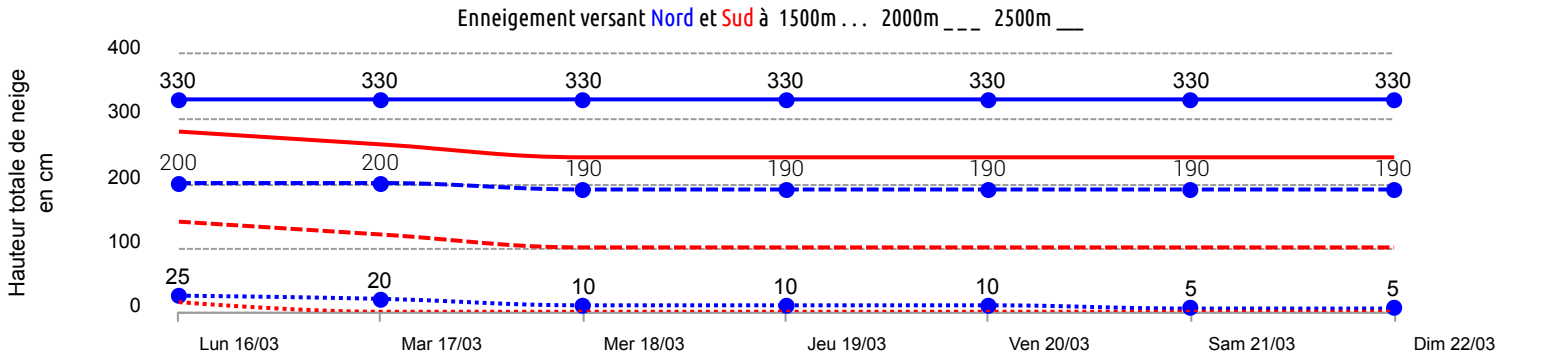


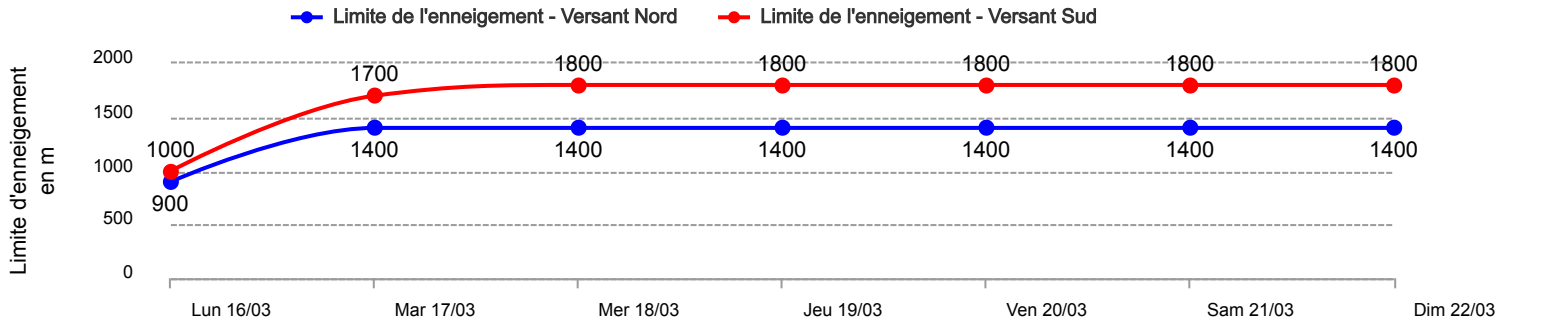


Pour consulter la vigilance en cours, veuillez vous rendre sur le site https://vigilance.meteofrance.fr/fr


Météo-France - 73 avenue de Paris, 94165 Saint-Mandé cedex - Contact : contact@meteo.fr


Bulletin neige & avalanches par téléphone au
0 892 68 10 20 Service 0,35 € / min + prix appel


Rédigé par Météo-France avec la contribution des observateurs du réseau nivo-météorologiques. Partenariat : ANMSM (Maires de Stations de Montagne), DSF (Domaines Skiables de France), ADSP (Directeurs de Pistes et de la Sécurité des Stations de Sports d'Hiver) et autres acteurs de la montagne.