Bulletin d'estimation du risque d'avalanche
(valable en dehors des pistes balisées et ouvertes)

MASSIF : Haute-Maurienne

Rédigé le dimanche 22 mars 2026 à 16h

Estimation des risques pour le : LUNDI 23 MARS

INSTABILITÉS TEMPORAIREMENT RÉACTIVES FORMÉES PAR LE VENT DANS LA NEIGE LÉGÈRE.

3

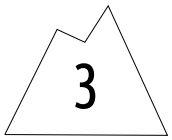

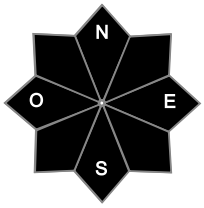

Indice de risque marqué.

Départs spontanés : purges au soleil.

Déclenchements provoqués : quelques plaques réactives.

Indices de risque : 5 très fort - 4 fort - 3 marqué - 2 limité - 1 faible -- En noir : les pentes les plus dangereuses

Stabilité du manteau neigeux

Situation avalancheuse typique : neige ventée neige fraîche

Déclenchements provoqués : Quelques plaques sont en place suite à l'épisode transport de neige par le vent d'Est à Sud de ce dimanche. Elles sont globalement en perte de réactivité mais encore sensible : en Nord là où il restait un peu de poudre, derrière les ruptures de pente et près des crêtes, en altitude (où elles sont aussi plus nombreuses). Taille 1 à 2 avec des cassures de 20 à 30 cm, localement 50/80 cm vers l'Italie et en altitude (cumul plus important et transport plus efficace).
Observables : accumulation de neige derrière une rupture de pente, test de stabilité, fissures devant les skis.

Départs spontanés : Quelques petits départs en poire sont possibles dans les pentes raides qui chauffent au soleil. Taille 1, rarement 2 si la pente le permet.

Qualité de la neige

Enneigement : Encore un peu au dessus de la moyenne, sauf aux plus basses altitudes où les hauteurs de neige sont tout juste correctes pour la saison.

Limite skiable : 1300 m au mieux en Nord. Plutôt 1600 m en sud pas trop raide.

Qualité de la neige : 10/20 cm de neige fraîche vers 1800 m localement 20/30 cm en allant vers l'Italie. Le vent a redistribué la neige : on peut trouver des zones pelées et d'autres avec le double d'épaisseur. Cette neige est croutée sous 1500/1700 m. Elle s'alourdit par humidification en journée. Sous-couche souvent dure : croute de regel en Sud, Est et Ouest (sauf très haut) et souvent cartonnée par le vent en Nord.

Aperçu météo pour le lundi 23 mars

	nuit	matin	après-midi	soir

Très belle journée. Cumulus parfois volumineux sur les sommets en fin d'après-midi.

Pluie-Neige				
Iso 0 °C	1 400 m	1 800 m	2 000 m	1 900 m
Vent 2500 m	← 15 km/h	↑ 10 km/h	↘ 15 km/h	↘ 10 km/h
Vent 3500 m	↖ 15 km/h	↙ 20 km/h	↓ 20 km/h	↙ 20 km/h

Épaisseur de neige hors-piste

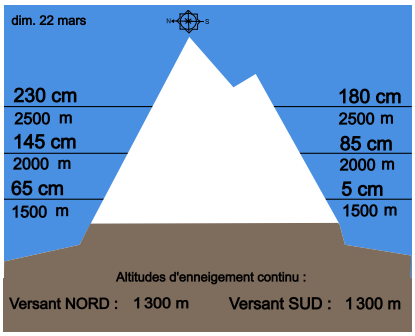

Précipitations à 1800 m

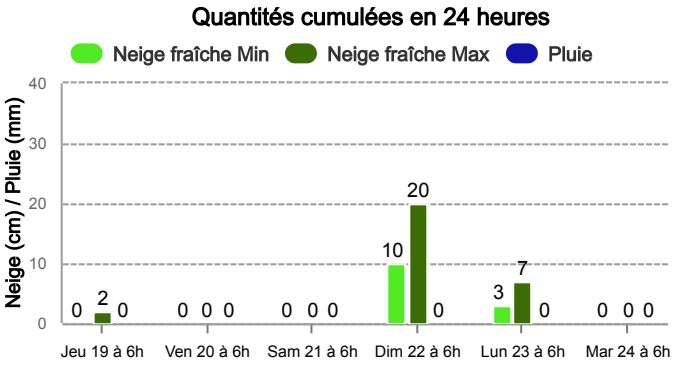

Tendance du mardi 24 mars

Indice de risque limité

Risque en baisse. Météo calme permettant la neutralisation des instabilités.

Pour consulter la vigilance en cours, veuillez vous rendre sur le site https://vigilance.meteofrance.fr/fr

Météo-France - 73 avenue de Paris, 94165 Saint-Mandé cedex - Contact : contact@meteo.fr

Rédigé par Météo-France avec la contribution des observateurs du réseau nivo-météorologiques. Partenariat : ANMSM (Maires de Stations de Montagne), DSF (Domaines Skiables de France), ADSP (Directeurs de Pistes et de la Sécurité des Stations de Sports d'Hiver) et autres acteurs de la montagne.

Bulletin neige & avalanches par téléphone au
0 892 68 10 20 Service 0,35 € / min + prix appel

RÉPUBLIQUE FRANÇAISE
Liberté Égalité Fraternité

METEO FRANCE
À VOS CÔTÉS, DANS UN CLIMAT QUI CHANGE

Bulletin d'estimation du risque d'avalanche
(valable en dehors des pistes balisées et ouvertes)
MASSIF : Haute-Maurienne

Rédigé le dimanche 22 mars 2026 à 16h

Conditions nivo-météo des 7 derniers jours

	lun. 16/03				mar. 17/03				mer. 18/03				jeu. 19/03				ven. 20/03				sam. 21/03				dim. 22/03			
	03h	09h	15h	21h	03h	09h	15h	21h	03h	09h	15h	21h	03h	09h	15h	21h	03h	09h	15h	21h	03h	09h	15h	21h	03h	09h	15h	21h
Météo																												
Vent (km/h)	20	50	50	30	30	30	30	30	35	45	60	50	40	20	15	15	20	20	15	10	15	20	15	20	15	20	20	10
à 3500m	↘	↓	↓	↓	↓	↓	↓	↓	↓	←	←	←	←	←	↙	↙	↙	↙	↓	→	↘	↓	↘	↓	↘	↖	↖	←
Vent (km/h)	10	40	40	20	20	20	20	15	20	30	50	40	30	15	10	10	10	10	5	5	10	10	20	10	10	25	25	15
à 2500m	↘	↘	↘	↘	↘	↘	↓	↓	←	↙	←	←	←	↙	↓	↙	↙	↙	→	→	↙	→	→	↘	↖	←	←	←

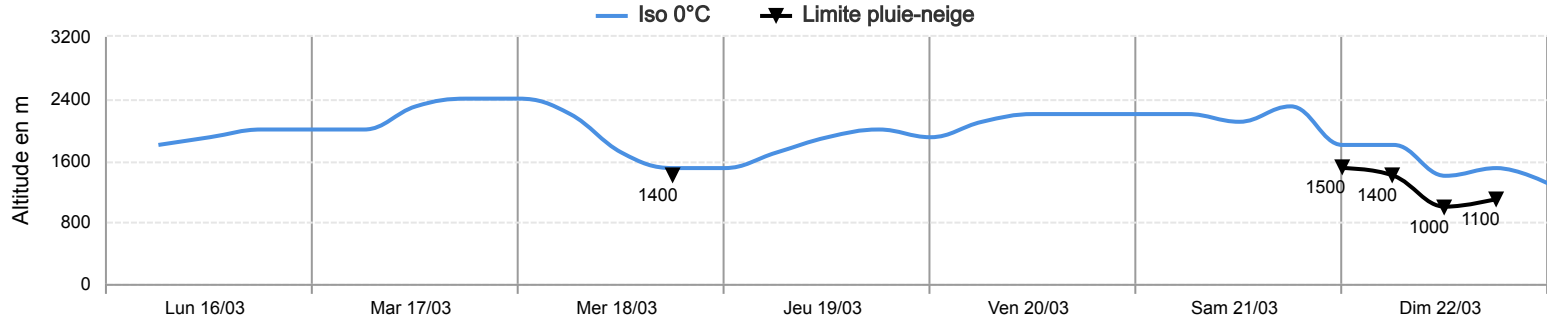

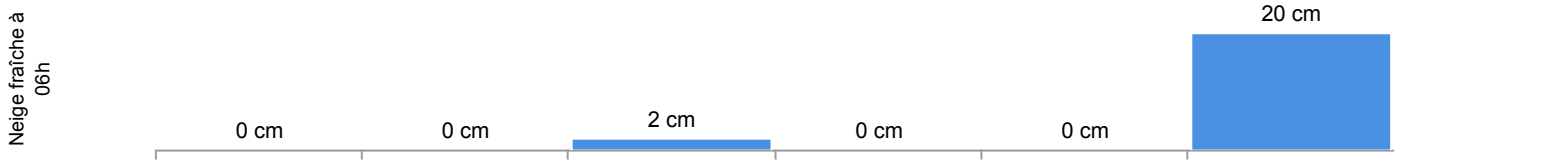

Risque d'avalanche	lun. 16/03	mar. 17/03	mer. 18/03	jeu. 19/03	ven. 20/03	sam. 21/03	dim. 22/03
	3	3	3	3	2	2	3

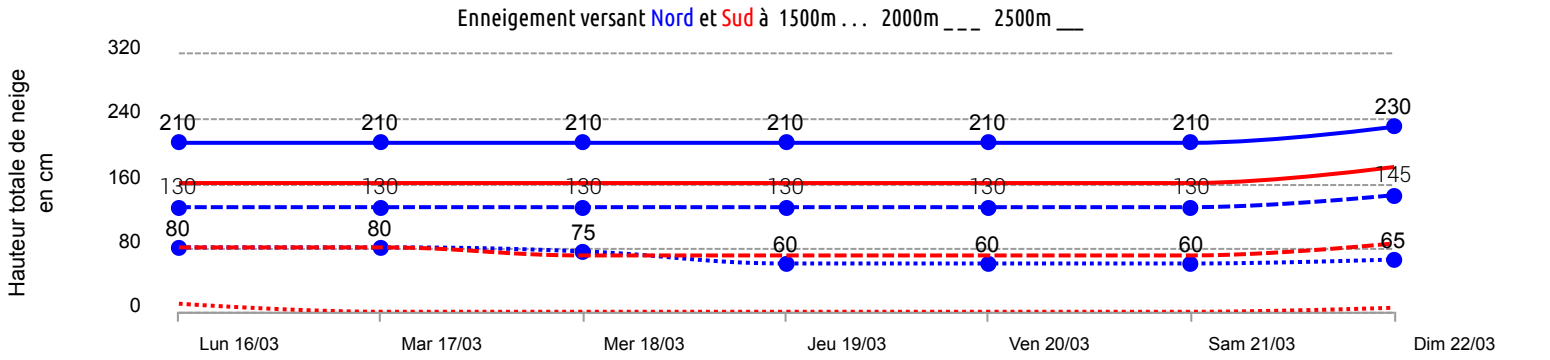

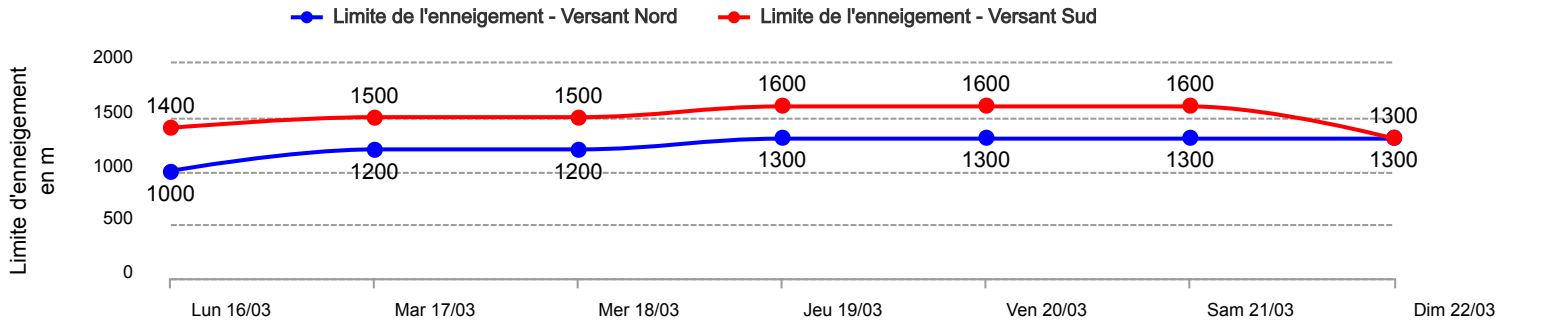

Pour consulter la vigilance en cours, veuillez vous rendre sur le site https://vigilance.meteofrance.fr/fr

Météo-France - 73 avenue de Paris, 94165 Saint-Mandé cedex - Contact : contact@meteo.fr

Rédigé par Météo-France avec la contribution des observateurs du réseau nivo-météorologiques. Partenariat : ANMSM (Maires de Stations de Montagne), DSF (Domaines Skiables de France), ADSP (Directeurs de Pistes et de la Sécurité des Stations de Sports d'Hiver) et autres acteurs de la montagne.

Bulletin neige & avalanches par téléphone au
0 892 68 10 20 Service 0,35 € / min + prix appel